Bulletin d'estimation du risque d'avalanche
(valable en dehors des pistes balisées et ouvertes)

MASSIF : Ubaye

Rédigé le mardi 10 mars 2026 à 16h

Estimation des risques pour le : MERCREDI 11 MARS

RARES INSTABILITÉS EN UBACS D'ALTITUDE, FAIBLE HUMIDIFICATION

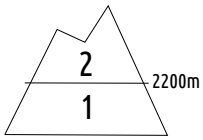

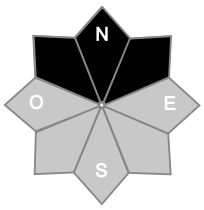

Au-dessus de 2200m indice de risque limité, plus bas indice faible.

Départs spontanés : rares départs superficiels de neige humide au soleil.

Déclenchements provoqués : rares instabilités superficielles en neige récente, et rares instabilités plus volumineuses difficiles à déclencher en ubacs d'altitude.

Indices de risque : 5 très fort - 4 fort - 3 marqué - 2 limité - 1 faible -- En noir : les pentes les plus dangereuses

Stabilité du manteau neigeux

Situation avalancheuse typique : couche fragile persistante

Déclenchements provoqués :
- De rares plaques sont possibles dans la neige récente : présentes principalement au dessus de 2200 m en versants nord-ouest à nord-est, elles sont le plus souvent d'aspect poudreux et peuvent être localement faciles à déclencher, mais restent de petite taille.
- D'anciennes plaques dures reposant sur des couches fragiles persistantes enfouies sont toujours présentes en orientations nord-ouest, nord ou nord-est au-dessus de 2200 m, surtout en Haute-Ubaye. Elles sont difficiles à solliciter par un seul skieur, mais elles peuvent toutefois en cas de déclenchement mobiliser d'importants volumes de neige (taille moyenne, voire grande non exclue).

Départs spontanés :
- rares départs ponctuels de petite taille en neige récente humidifiée, possibles en pentes raides au fil de la course du soleil.
- éventuellement une avalanche de glissement de taille moyenne, en pentes d'un large secteur sud, en terrain favorable (pentes herbeuses, dalles rocheuses).

Qualité de la neige

Enneigement proche des normales pour un début mars.
Données observées : 75 cm à la Nivôse de Restefond à 2550 m (secteur venté), 88 cm au-dessus de Larche à 2270 m en adret.

Enneigement skiable : vers 1600 m en ubacs, 1900/2000 m en adrets peu pentus.

État de la neige en surface : petite couche de neige récente (entre 5 et 15 cm) restée sèche au dessus de 2200 m environ, voire plus haut en versants sud. En dessous, regel nocturne limité, avec reprise d'une humidification superficielle en cours de journée. Sur les crêtes, d'anciennes corniches épaisses côtoient des zones dégarnies.

Aperçu météo pour le mercredi 11 mars

	nuit	matin	après-midi	soir

Ciel souvent voilé le matin, devenant plus nuageux l'après-midi à l'avant d'un faible passage perturbé en début de nuit suivante.

Pluie-Neige				1 600 m
Iso 0 °C	2 000 m	2 100 m	2 200 m	2 100 m
Vent 2000 m	↑ 5 km/h	→ 10 km/h	→ 20 km/h	→ 15 km/h
Vent 3000 m	→ 20 km/h	→ 30 km/h	→ 40 km/h	→ 35 km/h

Épaisseur de neige hors-piste

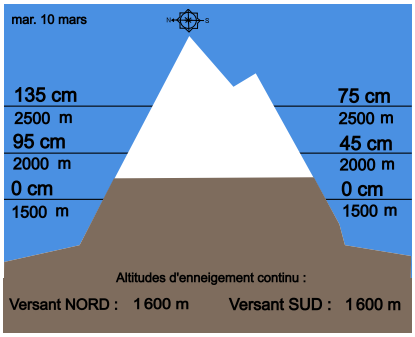

Précipitations à 1800 m

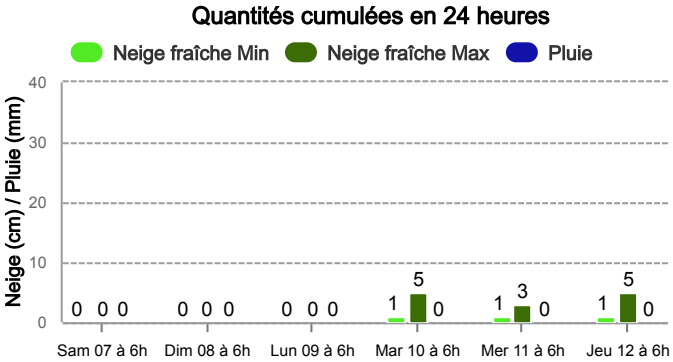

Tendance du jeudi 12 mars

Indice de risque limité

Risque restant limité, avec de nouvelles instabilités superficielles dans la neige fraîche après la perturbation de la nuit, et un peu d'humidification en journée.

Pour consulter la vigilance en cours, veuillez vous rendre sur le site https://vigilance.meteofrance.fr/fr

Météo-France - 73 avenue de Paris, 94165 Saint-Mandé cedex - Contact : contact@meteo.fr

Rédigé par Météo-France avec la contribution des observateurs du réseau nivo-météorologiques. Partenariat : ANMSM (Maires de Stations de Montagne), DSF (Domaines Skiables de France), ADSP (Directeurs de Pistes et de la Sécurité des Stations de Sports d'Hiver) et autres acteurs de la montagne.

Bulletin neige & avalanches par téléphone au **0 892 68 10 20** Service 0,35 € / min + prix appel

Bulletin d'estimation du risque d'avalanche

(valable en dehors des pistes balisées et ouvertes)

MASSIF : Ubaye

Rédigé le mardi 10 mars 2026 à 16h

Conditions nivo-météo des 7 derniers jours

	mer. 04/03				jeu. 05/03				ven. 06/03				sam. 07/03				dim. 08/03				lun. 09/03				mar. 10/03			
	03h	09h	15h	21h	03h	09h	15h	21h	03h	09h	15h	21h	03h	09h	15h	21h	03h	09h	15h	21h	03h	09h	15h	21h	03h	09h	15h	21h
Météo																												
Vent (km/h)	10	10	10	10	20	20	30	45	60	60	50	45	40	30	25	20	25	15	15	15	15	20	25	30	40	40	30	15
à 3000m																												
Vent (km/h)	5	5	10	10	25	30	35	40	35	30	30	30	25	25	20	15	15	15	15	5	5	10	20	20	15	10	5	5
à 2000m																												

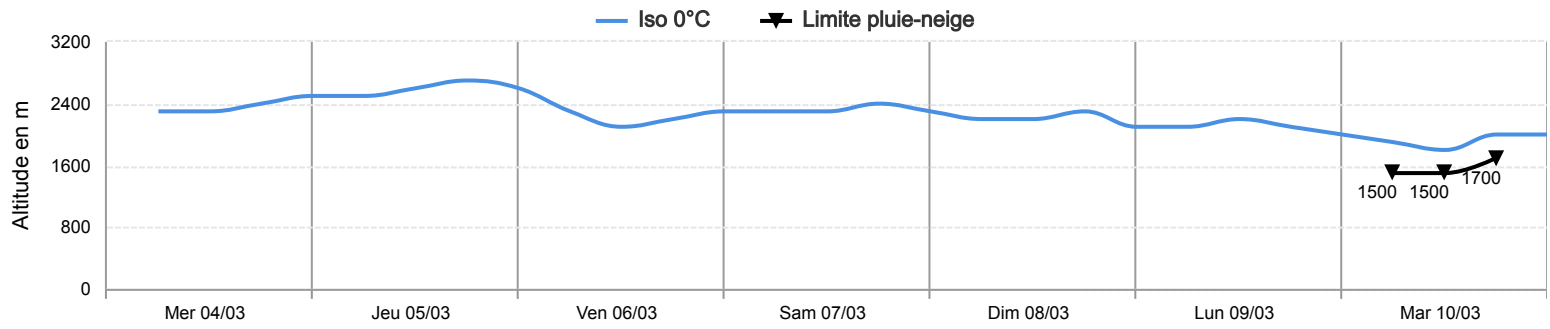

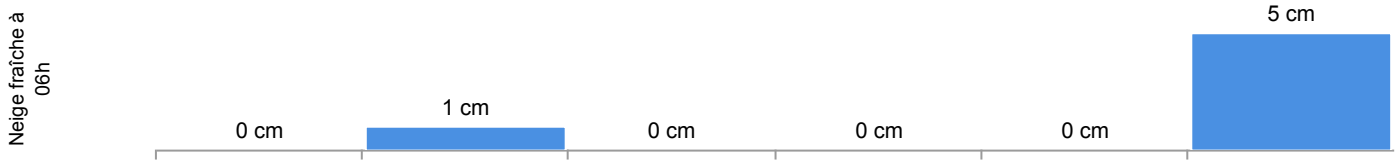

Risque d'avalanche	mer. 04/03	jeu. 05/03	ven. 06/03	sam. 07/03	dim. 08/03	lun. 09/03	mar. 10/03
	2	2	2	2	2	2	2

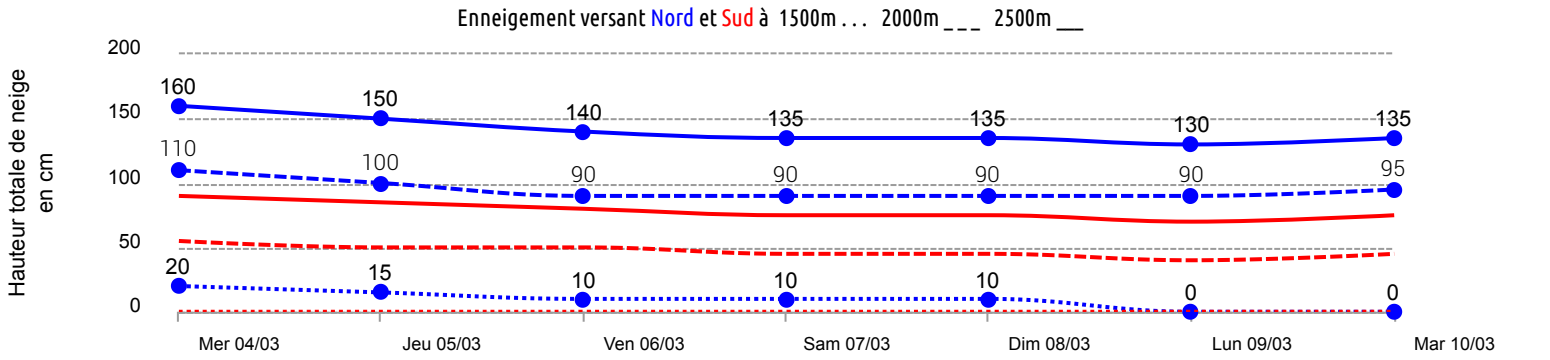

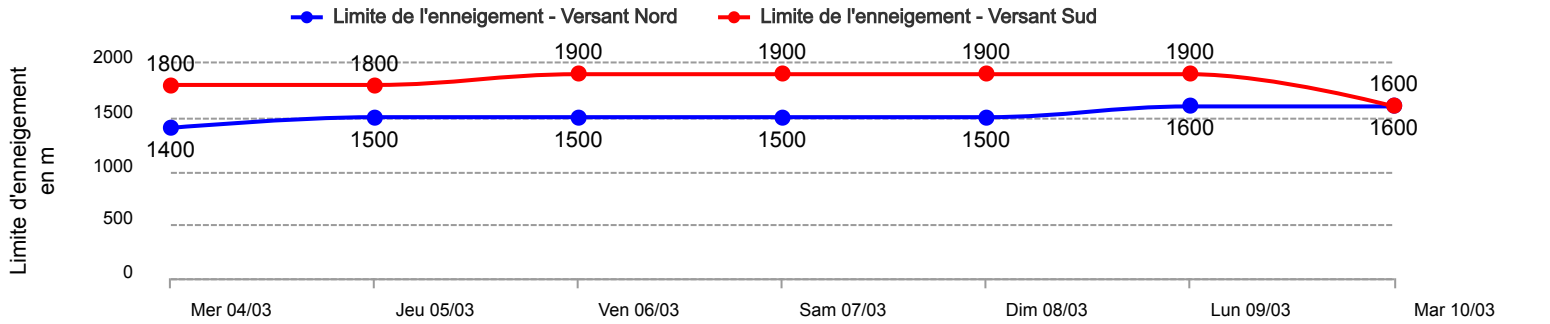

Pour consulter la vigilance en cours, veuillez vous rendre sur le site https://vigilance.meteofrance.fr/fr

Météo-France - 73 avenue de Paris, 94165 Saint-Mandé cedex - Contact : contact@meteo.fr

Rédigé par Météo-France avec la contribution des observateurs du réseau nivo-météorologiques. Partenariat : ANMSM (Maires de Stations de Montagne), DSF (Domaines Skiables de France), ADSP (Directeurs de Pistes et de la Sécurité des Stations de Sports d'Hiver) et autres acteurs de la montagne.

Bulletin neige & avalanches par téléphone au

0 892 68 10 20 Service 0,35 € / min + prix appel