Bulletin d'estimation du risque d'avalanche
(valable en dehors des pistes balisées et ouvertes)

MASSIF : Aure Louron

Rédigé le mardi 10 mars 2026 à 17h

Estimation des risques pour le : MERCREDI 11 MARS

AVALANCHES DE FOND, PLAQUES EN SECTEURS NORD D'ALTITUDE

2

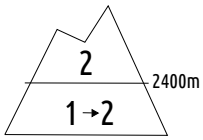

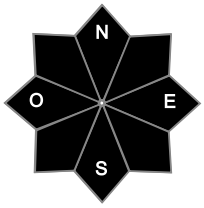

Plaques et soleil

Au-dessus de 2400m indice de risque limité, plus bas indice faible évoluant en limité.

Départs spontanés : Avalanches de fond

Déclenchements provoqués : Plaques dans la neige récente

Indices de risque : 5 très fort - 4 fort - 3 marqué - 2 limité - 1 faible -- En noir : les pentes les plus dangereuses

Stabilité du manteau neigeux

Situation avalancheuse typique : avalanches de fond neige ventée

Départs spontanés :
Des avalanches de fond se produisent régulièrement ces derniers jours, partant en général de fissures ouvertes dans des expositions variées mais plutôt au soleil. Activité faible en début de journée grâce à un bon regel, reprenant en journée au fil de l'ensoleillement. Ces avalanches atteignent une taille moyenne, une grande est possible partant d'une accumulation au-dessus de 2000m en versants Est principalement. De petits départs ponctuels dans les pentes raides sont aussi à attendre.

Déclenchements provoqués :
Au-dessus de 2400m, des plaques se sont formées lors des chutes de neige de ce weekend. Elles se situent dans les expositions ombragées, principalement à proximité des crêtes et cols d'altitude, et sont parfois facilement déclenchables : des déclenchements ont été observés ce lundi, avec des cassures d'environ 20cm. Leur localisation dans le massif est hétérogène, les averses ayant donné des cumuls assez variables (souvent plus importants vers la frontière).
D'une manière générale, le manteau en expositions nord d'altitude n'est pas encore printanier, des structures de plaques plus anciennes sont aussi en place, mais difficilement sollicitables car bien enfouies.

Autres : ponts de neige et corniches encore en place solides en début de journée, devenant fragiles avec le dégel.

Qualité de la neige

Enneigement bon pour la saison, sauf en expositions ouest souvent dégarnies par le vent.
Limites skiables : à partir de 1500m en versants froids, plutôt 1800/1900m en versants Sud.
État de la neige : Manteau printanier en expositions sud et sous 2400m à l'ombre. En expositions nord au-dessus de 2400m, on trouve jusqu'à 10-15cm localement (en secteurs frontaliers surtout) de neige fraîche restée froide. L'humidification en versants est est rapide le matin et assez nette en fin d'après-midi sous 2000m avec l'arrivée de la perturbation.

Aperçu météo pour le mercredi 11 mars

	nuit	matin	après-midi	soir

Voilé en matinée, puis les sommets sont accrochés. Le ciel se couvre l'après-midi, de faibles précipitations sont possibles en fin de journée.

Pluie-Neige				1 800 m
Iso 0 °C	2 300 m	2 400 m	2 200 m	2 100 m
Vent 1500 m	↑ 5 km/h	↑ 5 km/h	↓ 20 km/h	↘ 15 km/h
Vent 3000 m	→ 20 km/h	→ 30 km/h	↘ 50 km/h	↘ 50 km/h

Épaisseur de neige hors-piste

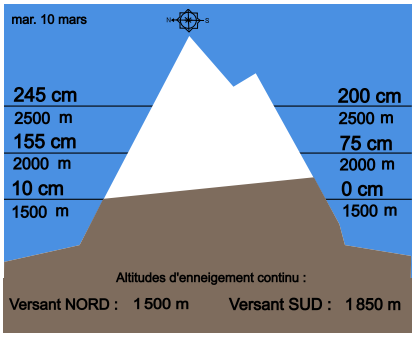

Précipitations à 1800 m

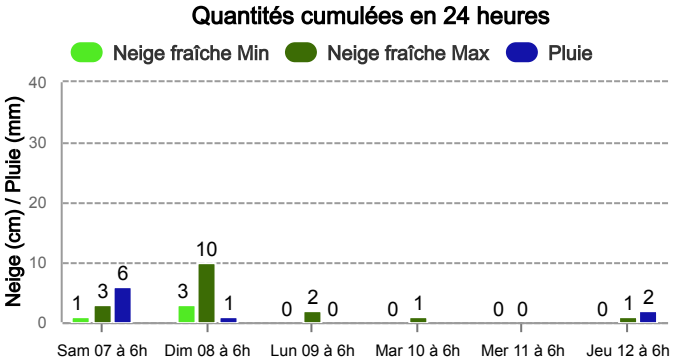

Tendance du jeudi 12 mars

2

Indice de risque limité

Lent tassement des structures de plaque d'altitude

Pour consulter la vigilance en cours, veuillez vous rendre sur le site https://vigilance.meteofrance.fr/fr

Météo-France - 73 avenue de Paris, 94165 Saint-Mandé cedex - Contact : contact@meteo.fr

Rédigé par Météo-France avec la contribution des observateurs du réseau nivo-météorologiques. Partenariat : ANMSM (Maires de Stations de Montagne), DSF (Domaines Skiables de France), ADSP (Directeurs de Pistes et de la Sécurité des Stations de Sports d'Hiver) et autres acteurs de la montagne.

Bulletin neige & avalanches par téléphone au
0 892 68 10 20 Service 0,35 € / min + prix appel

RÉPUBLIQUE FRANÇAISE
Liberté Égalité Fraternité

METEO FRANCE
À VOS CÔTÉS, DANS UN CLIMAT QUI CHANGE

Bulletin d'estimation du risque d'avalanche

(valable en dehors des pistes balisées et ouvertes)

MASSIF : Aure Louron

Rédigé le mardi 10 mars 2026 à 17h

Conditions nivo-météo des 7 derniers jours

	mer. 04/03				jeu. 05/03				ven. 06/03				sam. 07/03				dim. 08/03				lun. 09/03				mar. 10/03			
	03h	09h	15h	21h	03h	09h	15h	21h	03h	09h	15h	21h	03h	09h	15h	21h	03h	09h	15h	21h	03h	09h	15h	21h	03h	09h	15h	21h
Météo																												
Vent (km/h)	25	35	45	45	45	45	40	35	55	55	30	50	25	20	40	50	30	20	20	15	10	15	20	15	15	10	15	10
à 3000m																												
Vent (km/h)	10	20	25	30	30	25	20	20	10	10	15	10	10	15	10	10	10	5	5	5	2	5	5	5	5	5	15	5
à 1500m																												

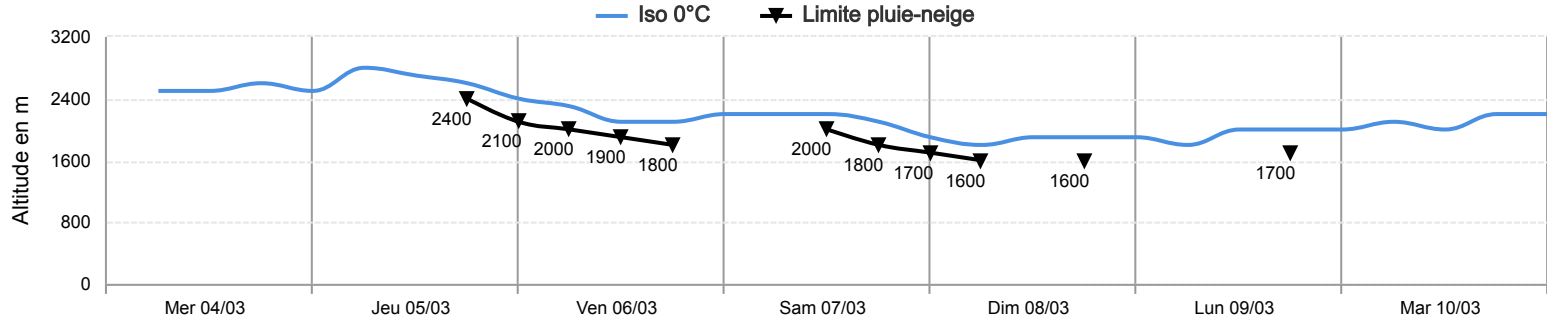

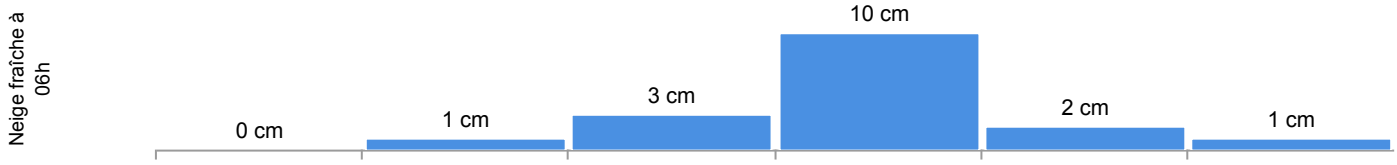

Risque d'avalanche	mer. 04/03	jeu. 05/03	ven. 06/03	sam. 07/03	dim. 08/03	lun. 09/03	mar. 10/03
	2	2	2	2	2	2	2

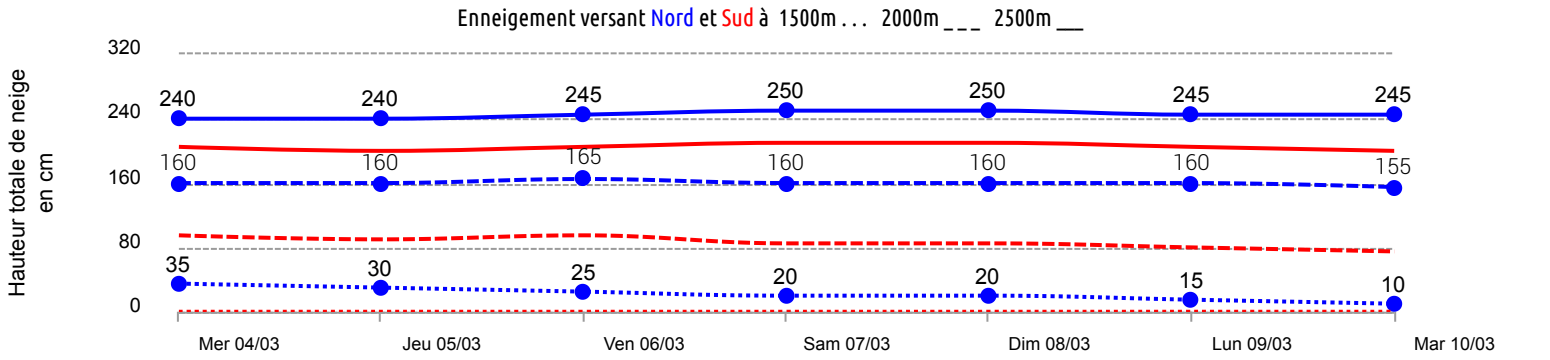

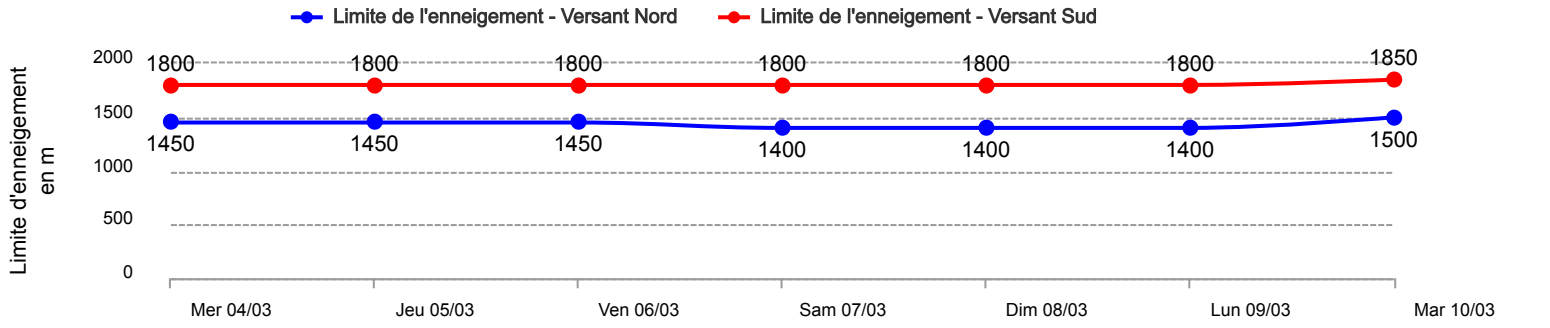

Pour consulter la vigilance en cours, veuillez vous rendre sur le site https://vigilance.meteofrance.fr/fr

Météo-France - 73 avenue de Paris, 94165 Saint-Mandé cedex - Contact : contact@meteo.fr

Rédigé par Météo-France avec la contribution des observateurs du réseau nivo-météorologiques. Partenariat : ANMSM (Maires de Stations de Montagne), DSF (Domaines Skiables de France), ADSP (Directeurs de Pistes et de la Sécurité des Stations de Sports d'Hiver) et autres acteurs de la montagne.

Bulletin neige & avalanches par téléphone au
0 892 68 10 20 Service 0,35 € / min + prix appel