RÉPUBLIQUE FRANÇAISE
Liberté Égalité Fraternité

METEO FRANCE
À VOS CÔTÉS, DANS UN CLIMAT QUI CHANGE

Bulletin d'estimation du risque d'avalanche
(valable en dehors des pistes balisées et ouvertes)
MASSIF : Capcir Puymorens

Rédigé le mardi 10 mars 2026 à 17h

Estimation des risques pour le : MERCREDI 11 MARS

AVALANCHES DE FOND, PLAQUES EN ALTITUDE

2

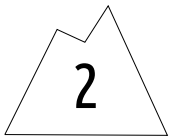

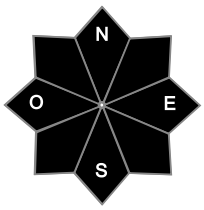

Indice de risque limité.

Départs spontanés : Rares avalanches de neige humide, emportant souvent toute l'épaisseur du manteau neigeux

Déclenchements provoqués : Quelques structures de plaques en altitude

Indices de risque : 5 très fort - 4 fort - 3 marqué - 2 limité - 1 faible -- En noir : les pentes les plus dangereuses

Stabilité du manteau neigeux

Situation avalancheuse typique : neige humide avalanches de fond

Départs spontanés :
Rares avalanches de neige humide avec cassure linéaire, souvent de fond sur les pentes raides favorables (pentes herbeuses ou dalles rocheuses) possibles en toutes orientations, et jusqu'à 2400/2500 m sur les versants ensoleillés. Cassures généralement plus épaisses au-dessus de 20000 à 2200m avec actuellement de nombreuses fissures ou gueules de baleines, signes précurseurs de telles avalanches, observables dans les pentes concernées. Ces avalanches sont de taille moyenne voire grande en partant d'une zone d'accumulation.
Des coulées en neige humide avec départs ponctuels sont également à attendre au fil de la journée dans les pentes raides des secteurs ensoleillés.

Déclenchements provoqués :
Les structures de plaques formées lors des dernières chutes de neige sont désormais difficilement déclenchables. Les plaques formées en fin de semaine dernière devraient maintenant être bien stabilisées mais dans de rares configurations, il n'est pas exclu qu'elles puissent encore être sollicitées, avec une avalanche de taille moyenne, voire grande.
En toute fin de journée les chutes de neige sont associées à un vent d'ouest à nord-ouest se renforçant d'où la formation de nouvelles plaques dans un large secteur sud à nord-est, certes fines mais facilement déclenchables.
Enfin une personne pourra toujours favoriser des départs superficiels en neige humide en traversant une pente raide déjà bien humidifiée avec le risque d'être déséquilibré.

Autre: Des chutes de corniches, parfois larges et épaisses, sont encore possibles et peuvent être à l'origine de départs d'avalanches.

Qualité de la neige

Enneigement :
L'enneigement est nettement excédentaire dès la moyenne montagne grâce à la succession de nombreuses perturbations neigeuses depuis le début de l'année, avec un nouvel apport conséquent et récent, de 50 cm à 1m, en haute-montagne. Les vallons ombragés sont encore bien enneigés notamment en versant est et nord.
Il est en général possible de chausser dès 1600/1800m d'altitude. La limite skiable remonte toutefois dans les pentes ensoleillées.

Qualité de la neige :
Mardi matin, on trouvera le plus souvent un manteau neigeux bien regelé, sauf dans les zones forestières où le regel peu être moins efficace. On pourra trouver localement dès 1700/1800m une fine couche de neige aux endroits concernés par les averses de ce lundi après-midi. En journée, la neige est à nouveau humidifiée au soleil, avec une humidification en profondeur sous 2000/2200 m et de la neige collante et lourde. Plus haut, on trouvera une couche de neige récente importante, notamment dans les secteurs à l'abri du vent d'est à sud-est, pouvant encore être poudreuse dans les combes ombragées.

Aperçu météo pour le mercredi 11 mars

	nuit	matin	après-midi	soir
	Ciel voilé en matinée, arrivée de petites précipitations en fin d'après-midi et soirée			
Pluie-Neige			2 000 m	1 900 m
Iso 0 °C	2 200 m	2 400 m	2 400 m	2 200 m
Vent 2000 m	↗ 10 km/h	↗ 10 km/h	↗ 15 km/h	↘ 20 km/h
Vent 3000 m	↗ 15 km/h	→ 15 km/h	↘ 15 km/h	↘ 35 km/h

Pour consulter la vigilance en cours, veuillez vous rendre sur le site https://vigilance.meteofrance.fr/fr

Météo-France - 73 avenue de Paris, 94165 Saint-Mandé cedex - Contact : contact@meteo.fr

Rédigé par Météo-France avec la contribution des observateurs du réseau nivo-météorologiques. Partenariat : ANMSM (Maires de Stations de Montagne), DSF (Domaines Skiables de France), ADSP (Directeurs de Pistes et de la Sécurité des Stations de Sports d'Hiver) et autres acteurs de la montagne.

Bulletin neige & avalanches par téléphone au
0 892 68 10 20 Service 0,35 € / min + prix appel

Bulletin d'estimation du risque d'avalanche

(valable en dehors des pistes balisées et ouvertes)

MASSIF : Capcir Puymorens

Rédigé le mardi 10 mars 2026 à 17h

Épaisseur de neige hors-piste

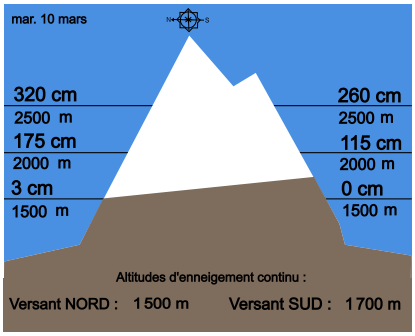

Précipitations à 1800 m

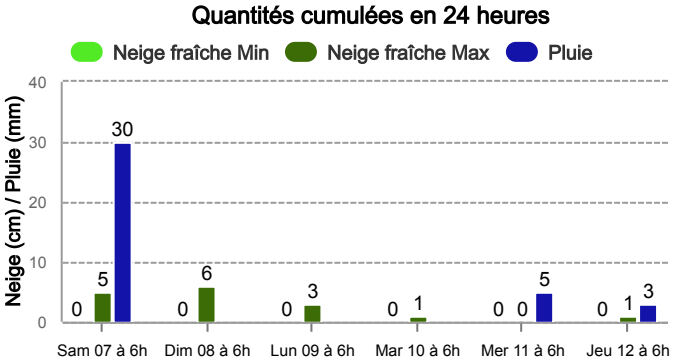

Tendance du jeudi 12 mars

Indice de risque limité

Maintien du risque du fait de nouvelles structures de plaques en altitude, et des avalanches en neige humide au soleil et aux altitudes basses

Pour consulter la vigilance en cours, veuillez vous rendre sur le site https://vigilance.meteofrance.fr/fr

Météo-France - 73 avenue de Paris, 94165 Saint-Mandé cedex - Contact : contact@meteo.fr

Rédigé par Météo-France avec la contribution des observateurs du réseau nivo-météorologiques. Partenariat : ANMSM (Maires de Stations de Montagne), DSF (Domaines Skiables de France), ADSP (Directeurs de Pistes et de la Sécurité des Stations de Sports d'Hiver) et autres acteurs de la montagne.

Bulletin neige & avalanches par téléphone au

0 892 68 10 20 Service 0,35 € / min + prix appel

RÉPUBLIQUE FRANÇAISE
Liberté Égalité Fraternité

METEO FRANCE
À VOS CÔTÉS, DANS UN CLIMAT QUI CHANGE

Bulletin d'estimation du risque d'avalanche

(valable en dehors des pistes balisées et ouvertes)

MASSIF : Capcir Puymorens

Rédigé le mardi 10 mars 2026 à 17h

Conditions nivo-météo des 7 derniers jours

	mer. 04/03				jeu. 05/03				ven. 06/03				sam. 07/03				dim. 08/03				lun. 09/03				mar. 10/03			
	03h	09h	15h	21h	03h	09h	15h	21h	03h	09h	15h	21h	03h	09h	15h	21h	03h	09h	15h	21h	03h	09h	15h	21h	03h	09h	15h	21h
Météo																												
Vent (km/h)	25	20	35	30	35	35	40	40	45	50	55	40	40	40	30	25	30	25	25	20	20	15	15	15	15	15	20	15
à 3000m																												
Vent (km/h)	15	15	25	20	20	25	30	25	25	35	35	30	25	30	20	15	20	20	15	10	10	10	10	5	5	5	10	10
à 2000m																												

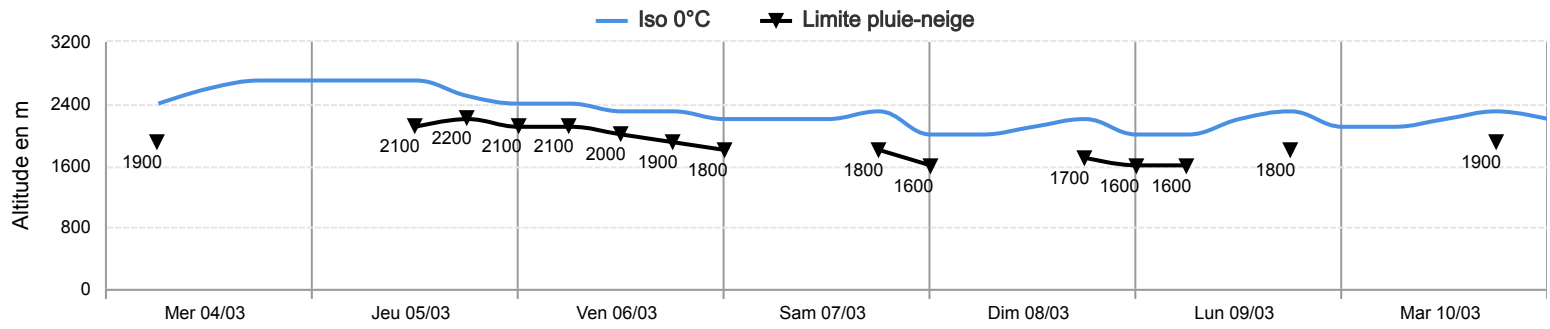

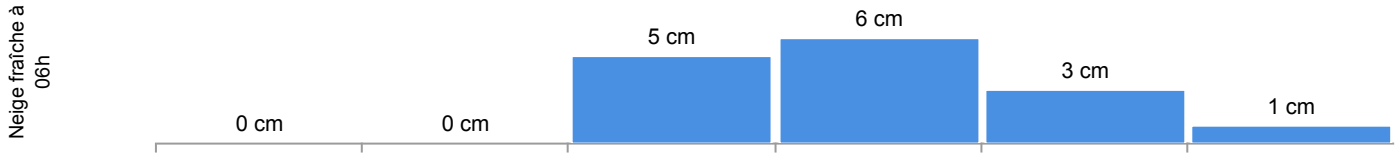

Risque d'avalanche	mer. 04/03	jeu. 05/03	ven. 06/03	sam. 07/03	dim. 08/03	lun. 09/03	mar. 10/03
	2	2	3	3	3	3	2

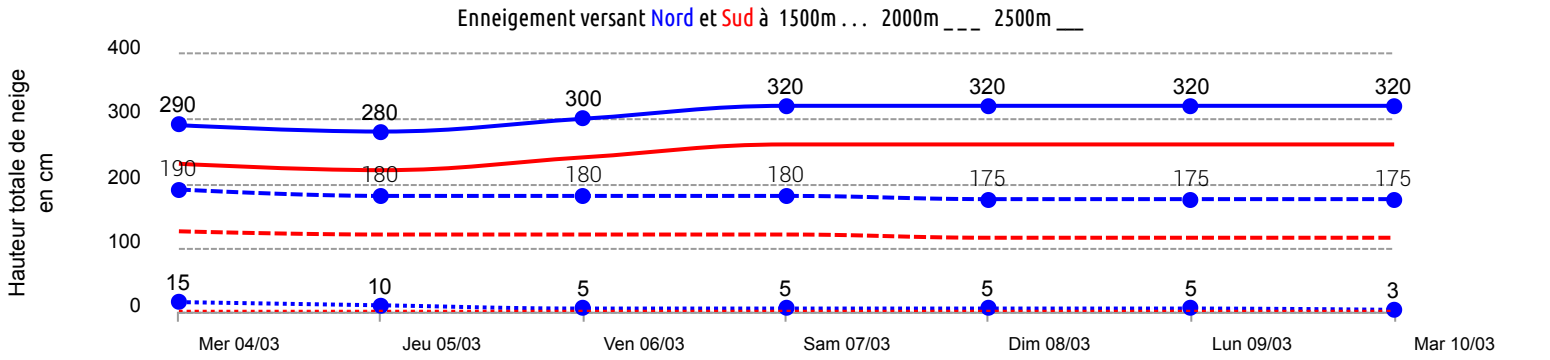

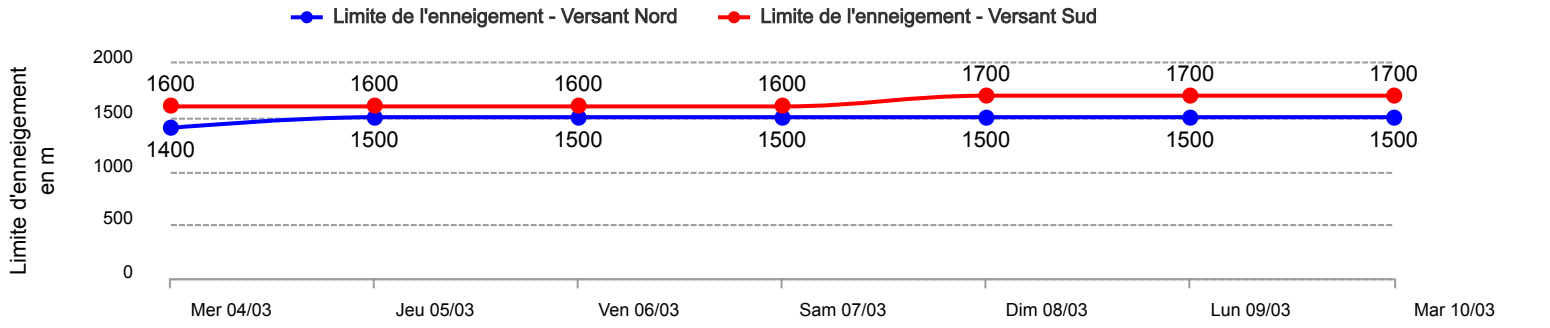

Pour consulter la vigilance en cours, veuillez vous rendre sur le site https://vigilance.meteofrance.fr/fr

Météo-France - 73 avenue de Paris, 94165 Saint-Mandé cedex - Contact : contact@meteo.fr

Rédigé par Météo-France avec la contribution des observateurs du réseau nivo-météorologiques. Partenariat : ANMSM (Maires de Stations de Montagne), DSF (Domaines Skiables de France), ADSP (Directeurs de Pistes et de la Sécurité des Stations de Sports d'Hiver) et autres acteurs de la montagne.

Bulletin neige & avalanches par téléphone au
0 892 68 10 20 Service 0,35 € / min + prix appel