RÉPUBLIQUE FRANÇAISE
Liberté Égalité Fraternité

METEO FRANCE
À VOS CÔTÉS, DANS UN CLIMAT QUI CHANGE

Bulletin d'estimation du risque d'avalanche
(valable en dehors des pistes balisées et ouvertes)
MASSIF : Cerdagne Canigou

Rédigé le mardi 10 mars 2026 à 17h

Estimation des risques pour le : MERCREDI 11 MARS

AVALANCHES DE NEIGE HUMIDE, PLAQUES EN ALTITUDE

2

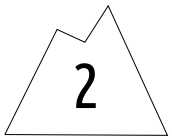

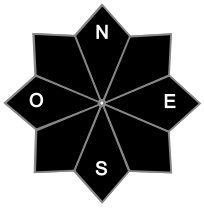

Indice de risque limité.

Départs spontanés : Quelques avalanches de neige humide, parfois grandes

Déclenchements provoqués : Quelques structures de plaques en altitude

Indices de risque : 5 très fort - 4 fort - 3 marqué - 2 limité - 1 faible -- En noir : les pentes les plus dangereuses

Stabilité du manteau neigeux

Situation avalancheuse typique : neige humide avalanches de fond

Départs spontanés :
Avec l'ensoleillement et les quantités importantes de neige récente, des avalanches de neige humide avec cassure linéaire, parfois jusqu'au sol, de taille moyenne voire grande sont à attendre jusqu'à 2400/2500m dans les secteurs ensoleillés. L'ouverture de fissures est un signe précurseur d'avalanche pouvant partir jusqu'au sol (avalanche de fonds), à surveiller y compris dans les secteurs pas ou peu ensoleillés.
Des coulées en neige humide avec départs ponctuels sont également à attendre au fil de la journée dans les pentes raides des secteurs ensoleillés.

Déclenchements provoqués :
Les plaques formées en fin de semaine dernière devraient maintenant être bien stabilisées mais dans de rares configurations, il n'est pas exclu qu'elles puissent encore être sollicitées, avec une avalanche de taille moyenne, voire grande.
Suite aux averses de lundi à mercredi compris des avalanches de plaques sont possibles dans les secteurs restés froids au-dessus de 2000/2200m. Ces plaques sont généralement assez fines au vu des faibles cumuls de neige mais leur déclenchement est parfois possible même par faible surcharge.
Enfin, une personne pourra toujours favoriser des départs superficiels en neige humide en traversant une pente raide déjà bien humidifiée avec alors le risque d'être déséquilibré.

Autre: Des chutes de corniches, parfois larges et épaisses, ont encore été reportées récemment et peuvent être à l'origine de départs d'avalanches.

Qualité de la neige

Enneigement :
L'enneigement est excédentaire dès la moyenne montagne grâce à la succession de nombreuses perturbations neigeuses depuis le début de l'année. Il est en général possible de chausser dès 1600/1800m d'altitude. La limite skiable remonte toutefois dans les pentes ensoleillées. Le manteau neigeux atteint rapidement 1m d'épaisseur et dépasse encore les 2m au-dessus de 2200m.

Qualité de la neige :
Mercredi matin, on trouvera le plus souvent un manteau neigeux plus ou moins bien regelé sous 2000m sous le voile nuageux. On pourra trouver localement dès 1800m une petite couche de neige fraîche aux endroits concernés par les averses des jours précédents. En journée, la neige est à nouveau humidifiée au soleil, avec une humidification en profondeur sous 2000/2200 m et de la neige collante et lourde. Plus haut, on trouvera une couche de neige récente importante, notamment dans les secteurs à l'abri du vent d'est à sud-est, pouvant encore être poudreuse dans les combes ombragées.

Aperçu météo pour le mercredi 11 mars

	nuit	matin	après-midi	soir
Ciel voilé en matinée, rares averses l'après-midi				
Pluie-Neige			1 900 m	1 800 m
Iso 0 °C	2 200 m	2 500 m	2 400 m	2 200 m
Vent 2000 m	↗ 10 km/h	↗ 10 km/h	↘ 15 km/h	↘ 15 km/h
Vent 3000 m	↑ 20 km/h	→ 15 km/h	→ 20 km/h	↘ 25 km/h

Pour consulter la vigilance en cours, veuillez vous rendre sur le site https://vigilance.meteofrance.fr/fr

Météo-France - 73 avenue de Paris, 94165 Saint-Mandé cedex - Contact : contact@meteo.fr

Rédigé par Météo-France avec la contribution des observateurs du réseau nivo-météorologiques. Partenariat : ANMSM (Maires de Stations de Montagne), DSF (Domaines Skiables de France), ADSP (Directeurs de Pistes et de la Sécurité des Stations de Sports d'Hiver) et autres acteurs de la montagne.

Bulletin neige & avalanches par téléphone au
0 892 68 10 20 Service 0,35 € / min + prix appel

Bulletin d'estimation du risque d'avalanche

(valable en dehors des pistes balisées et ouvertes)

MASSIF : Cerdagne Canigou

Rédigé le mardi 10 mars 2026 à 17h

Épaisseur de neige hors-piste

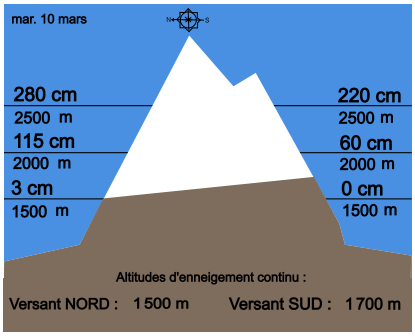

Précipitations à 1800 m

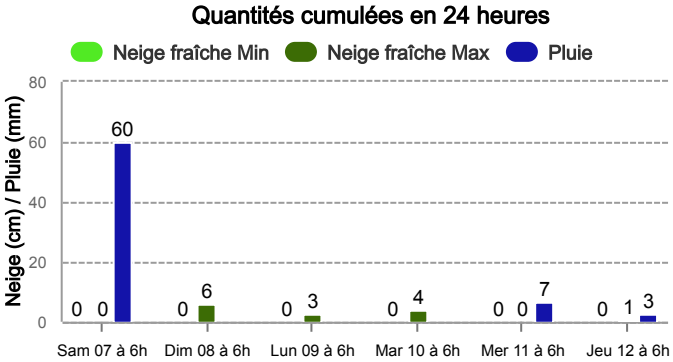

Tendance du jeudi 12 mars

Indice de risque limité

Maintien du risque du fait de nouvelles structures de plaques en altitude, et des avalanches en neige humide au soleil et aux altitudes basses

Pour consulter la vigilance en cours, veuillez vous rendre sur le site https://vigilance.meteofrance.fr/fr

Météo-France - 73 avenue de Paris, 94165 Saint-Mandé cedex - Contact : contact@meteo.fr

Rédigé par Météo-France avec la contribution des observateurs du réseau nivo-météorologiques. Partenariat : ANMSM (Maires de Stations de Montagne), DSF (Domaines Skiables de France), ADSP (Directeurs de Pistes et de la Sécurité des Stations de Sports d'Hiver) et autres acteurs de la montagne.

Bulletin neige & avalanches par téléphone au

0 892 68 10 20 Service 0,35 € / min + prix appel

RÉPUBLIQUE FRANÇAISE
Liberté Égalité Fraternité

METEO FRANCE
À VOS CÔTÉS, DANS UN CLIMAT QUI CHANGE

Bulletin d'estimation du risque d'avalanche
(valable en dehors des pistes balisées et ouvertes)
MASSIF : Cerdagne Canigou

Rédigé le mardi 10 mars 2026 à 17h

Conditions nivo-météo des 7 derniers jours

	mer. 04/03				jeu. 05/03				ven. 06/03				sam. 07/03				dim. 08/03				lun. 09/03				mar. 10/03			
	03h	09h	15h	21h	03h	09h	15h	21h	03h	09h	15h	21h	03h	09h	15h	21h	03h	09h	15h	21h	03h	09h	15h	21h	03h	09h	15h	21h
Météo																												
Vent (km/h)	40	35	40	25	45	50	50	50	45	50	55	40	40	40	30	25	30	25	25	20	20	15	15	10	15	15	15	15
à 3000m																												
Vent (km/h)	25	20	25	15	30	30	30	30	25	35	35	30	25	30	20	15	20	20	15	10	10	10	10	5	10	10	10	5
à 2000m																												

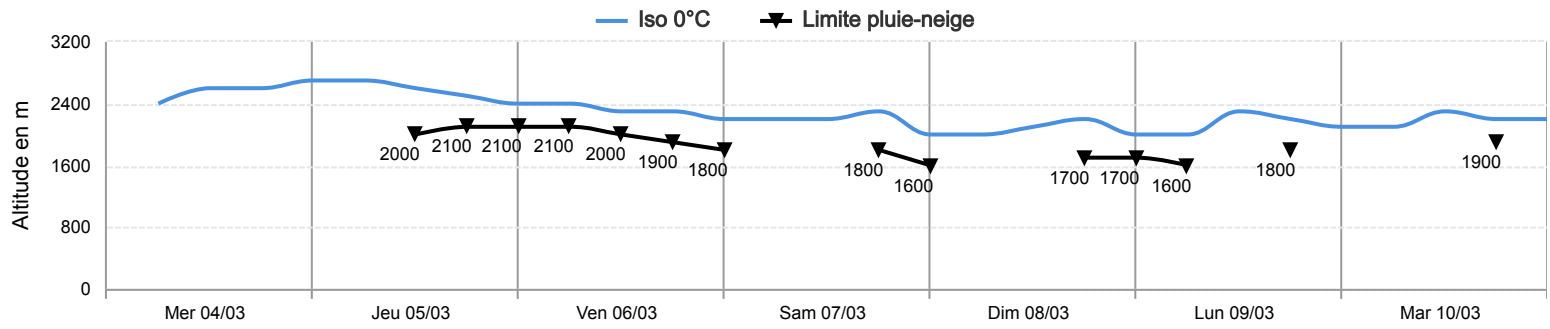

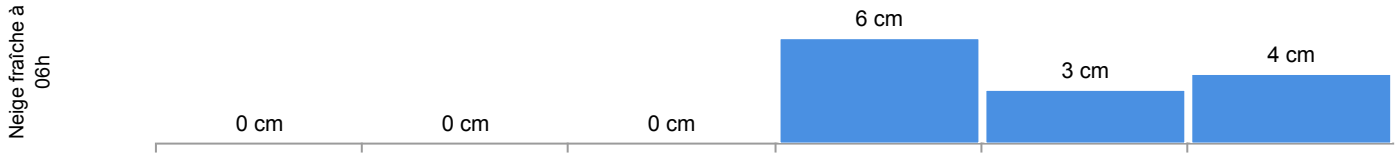

Risque d'avalanche	mer. 04/03	jeu. 05/03	ven. 06/03	sam. 07/03	dim. 08/03	lun. 09/03	mar. 10/03
	2	3	3	3	3	3	2

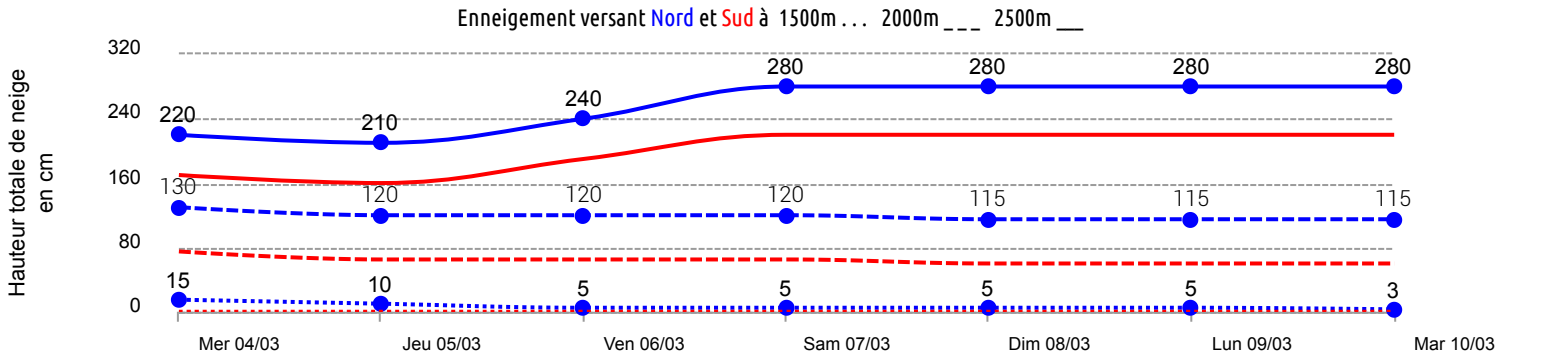

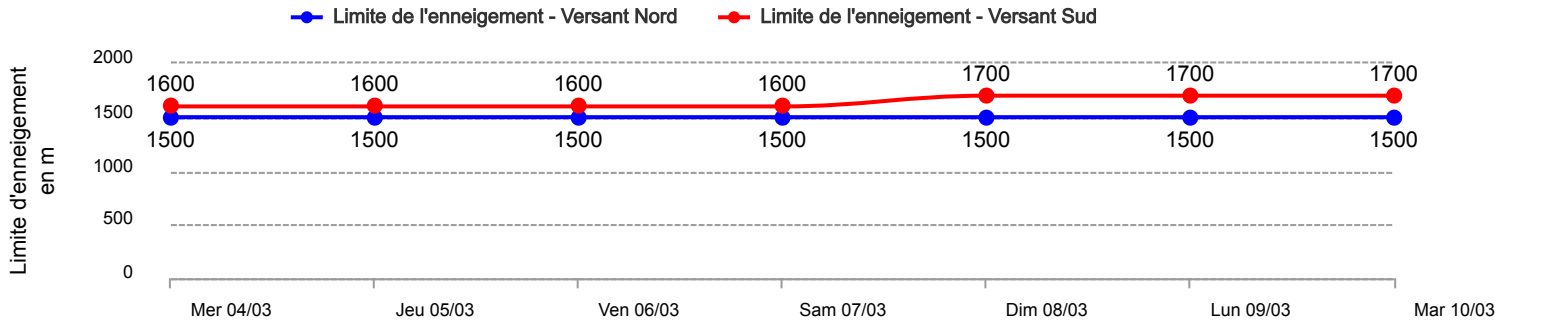

Pour consulter la vigilance en cours, veuillez vous rendre sur le site https://vigilance.meteofrance.fr/fr

Météo-France - 73 avenue de Paris, 94165 Saint-Mandé cedex - Contact : contact@meteo.fr

Rédigé par Météo-France avec la contribution des observateurs du réseau nivo-météorologiques. Partenariat : ANMSM (Maires de Stations de Montagne), DSF (Domaines Skiables de France), ADSP (Directeurs de Pistes et de la Sécurité des Stations de Sports d'Hiver) et autres acteurs de la montagne.

Bulletin neige & avalanches par téléphone au
0 892 68 10 20 Service 0,35 € / min + prix appel