RÉPUBLIQUE FRANÇAISE
Liberté Égalité Fraternité

METEO FRANCE
À VOS CÔTÉS, DANS UN CLIMAT QUI CHANGE

Bulletin d'estimation du risque d'avalanche
(valable en dehors des pistes balisées et ouvertes)

MASSIF : Haute-Ariege

Rédigé le mardi 10 mars 2026 à 17h

Estimation des risques pour le : MERCREDI 11 MARS

AVALANCHES DE FOND, PLAQUES EN ALTITUDE EN SECTEURS NORD

2

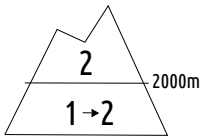

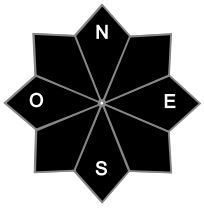

Au-dessus de 2000m indice de risque limité, plus bas indice faible évoluant en limité.

Départs spontanés : Rares avalanches de neige humide, emportant souvent toute l'épaisseur du manteau neigeux

Déclenchements provoqués : Quelques structures de plaques en altitude

Indices de risque : 5 très fort - 4 fort - 3 marqué - 2 limité - 1 faible -- En noir : les pentes les plus dangereuses

Stabilité du manteau neigeux

Situation avalancheuse typique : avalanches de fond neige humide

Départs spontanés :
Rares avalanches de neige humide avec cassure linéaire, souvent de fond sur les pentes raides favorables (pentes herbeuses ou dalles rocheuses) possibles en toutes orientations, et jusqu'à 2400/2500m sur les versants ensoleillés. Cassures généralement plus épaisses au-dessus de 2000m avec actuellement de nombreuses fissures ou gueules de baleines, signes précurseurs de telles avalanches, fréquemment observables dans les pentes concernées. Ces avalanches sont de taille moyenne voire grande en partant d'une zone d'accumulation.
Des coulées en neige humide avec départs ponctuels sont également à attendre au fil de la journée dans les pentes raides des secteurs ensoleillés.

Déclenchements provoqués :
Avalanches de plaques possibles peu épaisses dans les secteurs restés froids au-dessus de 2000/2200 m dans la neige récente avec les fréquentes averses des derniers jours. Ces déclenchements sont généralement de petite taille au vu des faibles cumuls de neige. Des plaques plus épaisses peuvent encore être présentes localement en nord d'altitude, elles sont désormais déclenchables seulement par forte surcharge mais pourraient donner des avalanches de plus grande taille.
En fin de journée les chutes de neige sont associées à un vent d'ouest à nord-ouest se renforçant d'où la formation de nouvelles plaques dans un large secteur sud à nord-est, certes fines mais facilement déclenchables.
Enfin, une personne pourra toujours favoriser des départs superficiels en neige humide en traversant une pente raide déjà bien transformée.

Autre : des ruptures de corniches parfois larges et épaisses sont toujours possibles à proximité des crêtes.

Qualité de la neige

Enneigement :
L'enneigement est excédentaire dès la moyenne montagne grâce aux perturbations neigeuses qui se sont succédé depuis le début de l'année. On peut souvent chausser les skis entre 1500 et 1800m dans les secteurs orientés sud alors que certaines vallées bien ombragées sont encore enneigées dès 1400 m. On trouve ensuite des quantités de neige plus conséquentes à partir de 2000 m en toutes orientations.

Qualité de la neige :
Mardi matin, on devrait trouver un manteau bien regelé en surface après une nuit claire. Dès 1700/1900m, on pourra également trouver une fine couche de neige fraiche des averses récentes. En journée, la neige s'humidifie assez vite dès le matin dans les versants prenant le soleil puis poursuit son humidification en journée dans les nuages. Plus haut en altitude, on trouvera une neige fréquemment dense et compacte sous 2500 m avec quelques secteurs restant poudreux dans les combes abritées de haute montagne.

Aperçu météo pour le mercredi 11 mars

Ciel voilé en matinée, arrivée de petites précipitations en cours d'après-midi et soirée

	nuit	matin	après-midi	soir
Pluie-Neige			1 900 m	1 800 m
Iso 0 °C	2 300 m	2 400 m	2 300 m	2 100 m
Vent 2000 m	↗ 15 km/h	↗ 10 km/h	↘ 10 km/h	↓ 20 km/h
Vent 3000 m	↑ 15 km/h	↗ 10 km/h	↘ 20 km/h	↓ 30 km/h

Pour consulter la vigilance en cours, veuillez vous rendre sur le site https://vigilance.meteofrance.fr/fr

Météo-France - 73 avenue de Paris, 94165 Saint-Mandé cedex - Contact : contact@meteo.fr

Rédigé par Météo-France avec la contribution des observateurs du réseau nivo-météorologiques. Partenariat : ANMSM (Maires de Stations de Montagne), DSF (Domaines Skiables de France), ADSP (Directeurs de Pistes et de la Sécurité des Stations de Sports d'Hiver) et autres acteurs de la montagne.

Bulletin neige & avalanches par téléphone au
0 892 68 10 20 Service 0,35 € / min + prix appel

Bulletin d'estimation du risque d'avalanche

(valable en dehors des pistes balisées et ouvertes)

MASSIF : Haute-Ariege

Rédigé le mardi 10 mars 2026 à 17h

Épaisseur de neige hors-piste

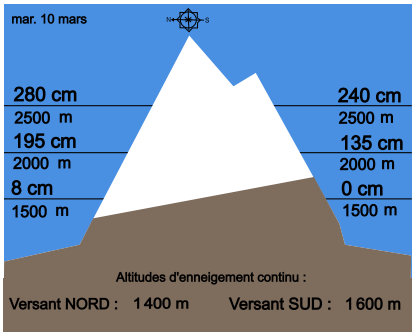

Précipitations à 1800 m

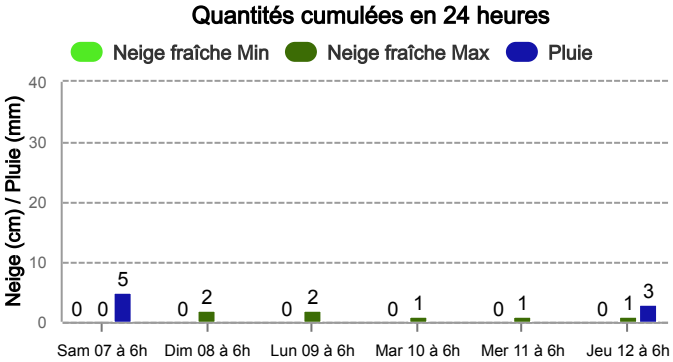

Tendance du jeudi 12 mars

Indice de risque limité

Maintien du risque du fait de nouvelles structures de plaques en altitude, et des avalanches en neige humide au soleil et aux altitudes basses

Pour consulter la vigilance en cours, veuillez vous rendre sur le site https://vigilance.meteofrance.fr/fr

Météo-France - 73 avenue de Paris, 94165 Saint-Mandé cedex - Contact : contact@meteo.fr

Rédigé par Météo-France avec la contribution des observateurs du réseau nivo-météorologiques. Partenariat : ANMSM (Maires de Stations de Montagne), DSF (Domaines Skiables de France), ADSP (Directeurs de Pistes et de la Sécurité des Stations de Sports d'Hiver) et autres acteurs de la montagne.

Bulletin neige & avalanches par téléphone au

0 892 68 10 20 Service 0,35 € / min + prix appel

Bulletin d'estimation du risque d'avalanche

(valable en dehors des pistes balisées et ouvertes)

MASSIF : Haute-Ariege

Rédigé le mardi 10 mars 2026 à 17h

Conditions nivo-météo des 7 derniers jours

	mer. 04/03				jeu. 05/03				ven. 06/03				sam. 07/03				dim. 08/03				lun. 09/03				mar. 10/03			
	03h	09h	15h	21h	03h	09h	15h	21h	03h	09h	15h	21h	03h	09h	15h	21h	03h	09h	15h	21h	03h	09h	15h	21h	03h	09h	15h	21h
Météo																												
Vent (km/h)	25	25	30	40	40	35	30	30	40	25	25	25	40	40	30	25	30	25	25	20	20	15	15	10	15	10	10	15
à 3000m																												
Vent (km/h)	20	20	25	30	35	30	20	20	25	15	20	20	25	30	20	15	20	20	15	10	10	10	10	5	5	5	5	10
à 2000m																												

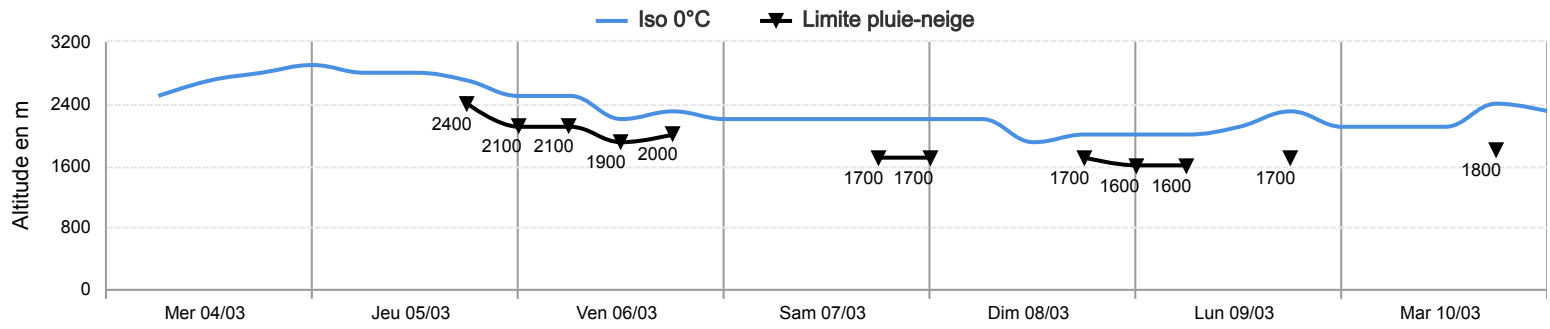

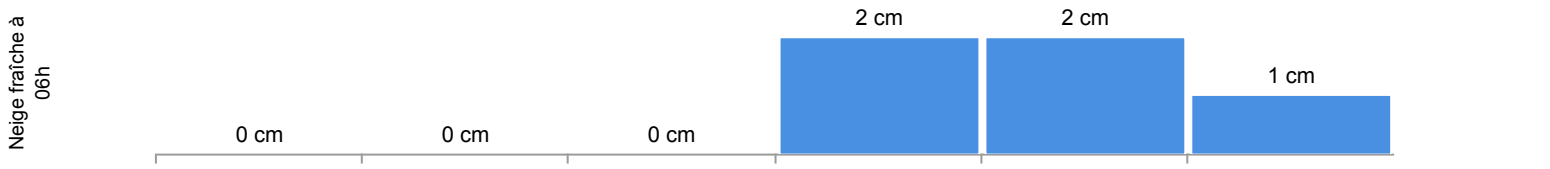

Risque d'avalanche	mer. 04/03	jeu. 05/03	ven. 06/03	sam. 07/03	dim. 08/03	lun. 09/03	mar. 10/03
	2	2	2	2	2	2	2

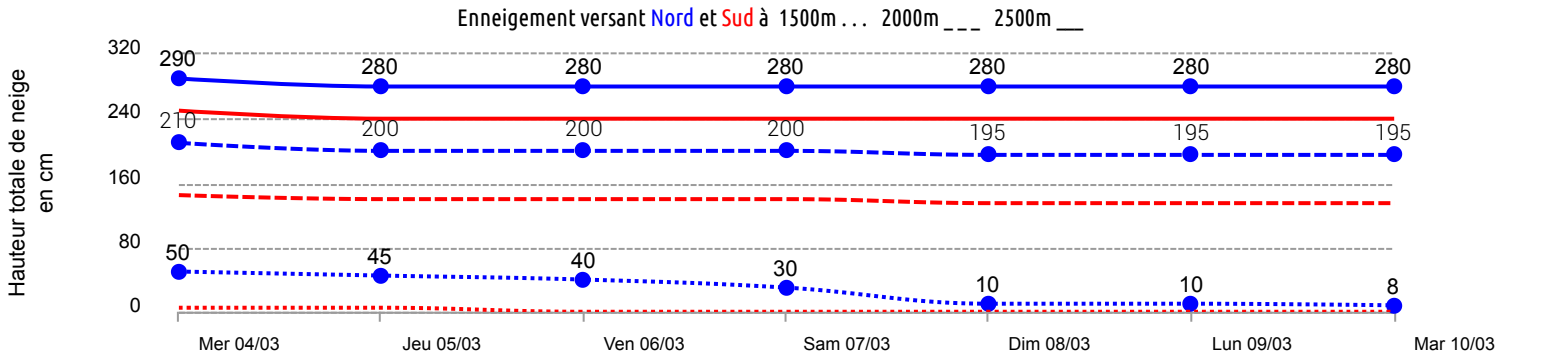

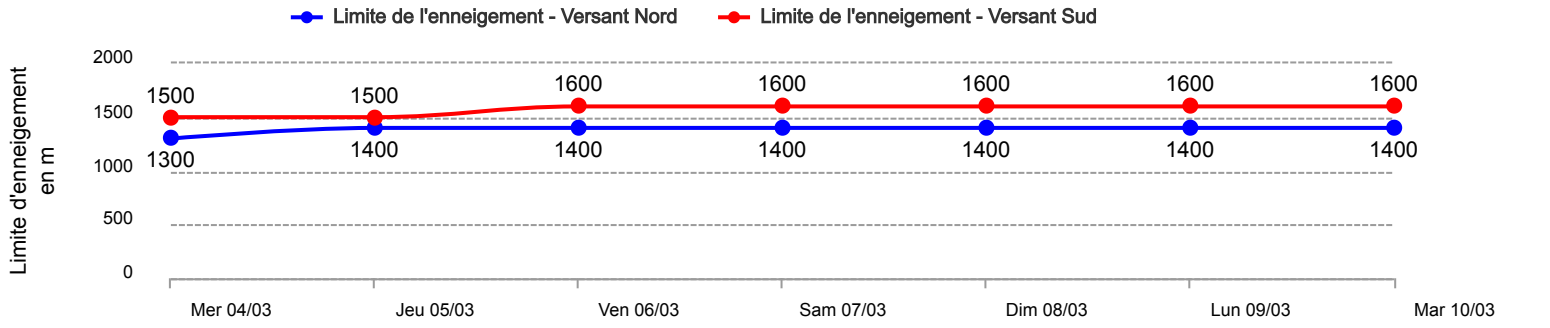

Pour consulter la vigilance en cours, veuillez vous rendre sur le site https://vigilance.meteofrance.fr/fr

Météo-France - 73 avenue de Paris, 94165 Saint-Mandé cedex - Contact : contact@meteo.fr

Rédigé par Météo-France avec la contribution des observateurs du réseau nivo-météorologiques. Partenariat : ANMSM (Maires de Stations de Montagne), DSF (Domaines Skiables de France), ADSP (Directeurs de Pistes et de la Sécurité des Stations de Sports d'Hiver) et autres acteurs de la montagne.

Bulletin neige & avalanches par téléphone au 0 892 68 10 20 Service 0,35 € / min + prix appel