Bulletin d'estimation du risque d'avalanche
(valable en dehors des pistes balisées et ouvertes)

MASSIF : Pays-Basque

Rédigé le mardi 10 mars 2026 à 17h

Estimation des risques pour le : MERCREDI 11 MARS

MANTEAU PRINTANIER QUELQUES AVALANCHES DE FOND

2

1 → 2

N O E S

En neige humide

Indice de risque faible évoluant en limité.

Départs spontanés : Pontuels en neige humide, rares plaques de fond

Déclenchements provoqués : Difficiles

Indices de risque : 5 très fort - 4 fort - 3 marqué - 2 limité - 1 faible -- En noir : les pentes les plus dangereuses

Stabilité du manteau neigeux

Situation avalancheuse typique : neige humide

Départs spontanés :
Pas d'activité en tout début de journée à la faveur d'un bon regel, puis, en matinée, quelques départs au soleil, ponctuels de petite taille, plus rarement de taille moyenne par départ d'une plaque de fond depuis une zone d'accumulation en altitude. Plus tard en journée, les nuages puis les pluies humidifient le manteau en toutes expositions, des départs deviennent possibles en tous secteurs, restant de petite taille, plus rarement moyenne.

Déclenchements provoqués :
Il n'y a plus de structure de plaques en place. Le passage d'un skieur en pente très raide peut éventuellement favoriser un départ ponctuel

Autres : ponts de neige et corniches fragiles avec le dégel.

Qualité de la neige

Enneigement : Enneigement bon pour la saison, plutôt maigre en versants exposés au vent d'ouest.
Limites skiables : à partir de 1500/1600m en versants froids, plutôt 1700/1800m en versants Sud
État de la neige : Regel incertain à cause du vent mercredi matin, neige s'humidifiant au soleil le matin, puis en toutes expositions sous les nuages. Corniches fréquentes vers les crêtes et cols.

Aperçu météo pour le mercredi 11 mars

	nuit	matin	après-midi	soir

Voilé en matinée, puis les sommets sont accrochés. Le relief se bouche l'après-midi, quelques précipitations se produisent jusqu'en soirée.

	nuit	matin	après-midi	soir
Pluie-Neige			1 900 m	1 800 m
Iso 0 °C	2 200 m	2 200 m	2 100 m	1 900 m
Vent 1000 m	↑ 25 km/h	↑ 35 km/h	↘ 20 km/h	↓ 15 km/h
Vent 2000 m	↑ 40 km/h	↗ 35 km/h	↗ 30 km/h	↘ 25 km/h

Épaisseur de neige hors-piste

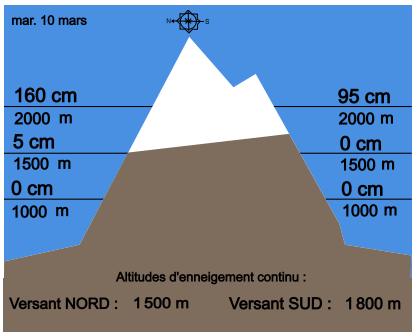

Précipitations à 1800 m

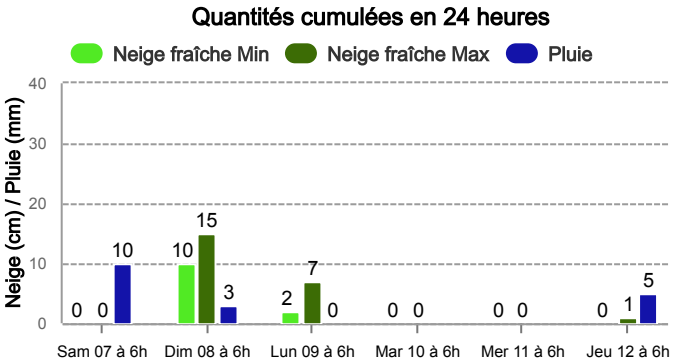

Tendance du jeudi 12 mars

2

Indice de risque limité

Pas d'évolution

Pour consulter la vigilance en cours, veuillez vous rendre sur le site https://vigilance.meteofrance.fr/fr

Météo-France - 73 avenue de Paris, 94165 Saint-Mandé cedex - Contact : contact@meteo.fr

Rédigé par Météo-France avec la contribution des observateurs du réseau nivo-météorologiques. Partenariat : ANMSM (Maires de Stations de Montagne), DSF (Domaines Skiables de France), ADSP (Directeurs de Pistes et de la Sécurité des Stations de Sports d'Hiver) et autres acteurs de la montagne.

Bulletin neige & avalanches par téléphone au 0 892 68 10 20 Service 0,35 € / min + prix appel

RÉPUBLIQUE FRANÇAISE
Liberté Égalité Fraternité

METEO FRANCE
À VOS CÔTÉS, DANS UN CLIMAT QUI CHANGE

Bulletin d'estimation du risque d'avalanche

(valable en dehors des pistes balisées et ouvertes)

MASSIF : Pays-Basque

Rédigé le mardi 10 mars 2026 à 17h

Conditions nivo-météo des 7 derniers jours

	mer. 04/03				jeu. 05/03				ven. 06/03				sam. 07/03				dim. 08/03				lun. 09/03				mar. 10/03			
	03h	09h	15h	21h	03h	09h	15h	21h	03h	09h	15h	21h	03h	09h	15h	21h	03h	09h	15h	21h	03h	09h	15h	21h	03h	09h	15h	21h
Météo																												
Vent (km/h)	25	25	55	70	70	60	45	35	30	25	25	15	20	25	30	25	40	35	30	15	25	25	20	20	15	15	15	20
à 2000m	↑	↑	↑	↑	↑	↑	↓	↙	↙	↓	↓	↙	↓	↖	↙	↑	↑	↑	↑	↑	↗	↑	↑	↑	←	←	↓	↑
Vent (km/h)	15	15	25	50	50	35	25	20	15	15	15	5	5	10	10	5	10	5	5	5	10	10	5	5	10	10	15	10
à 1000m	↑	↑	↖	↑	↑	↑	↓	↓	↘	↓	↓	↻	↻	↓	↻	↑	↑	↻	↻	↑	↑	↑	↻	↑	←	↙	↙	↻

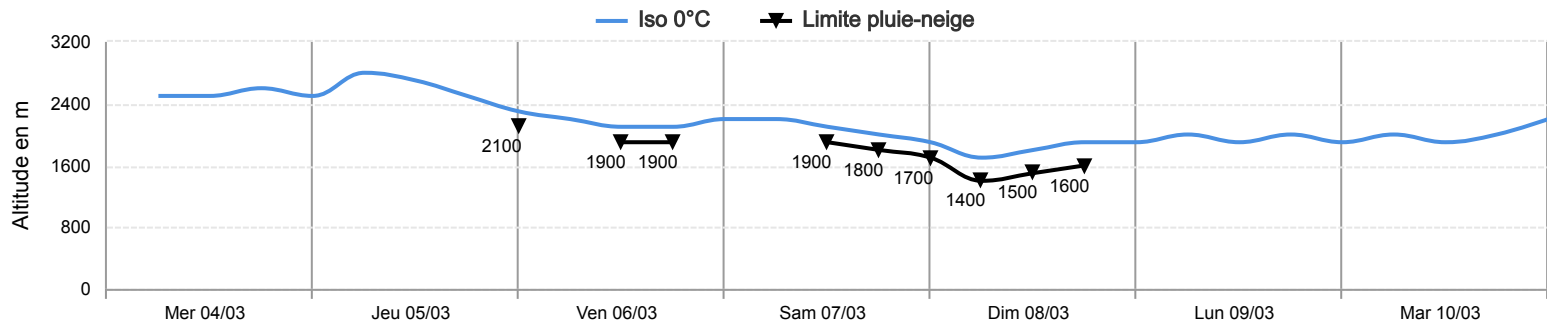

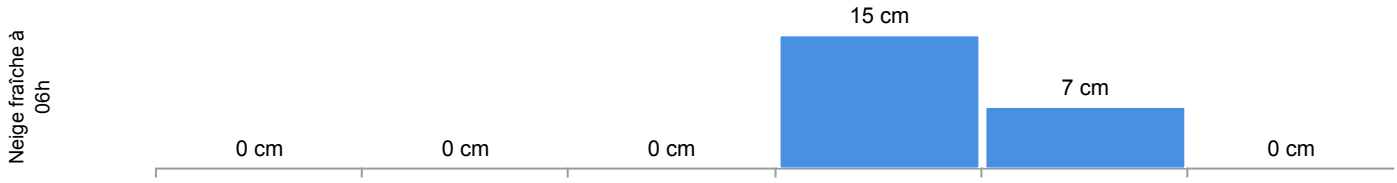

Risque d'avalanche	mer. 04/03	jeu. 05/03	ven. 06/03	sam. 07/03	dim. 08/03	lun. 09/03	mar. 10/03
	2	2	2	2	2	2	2

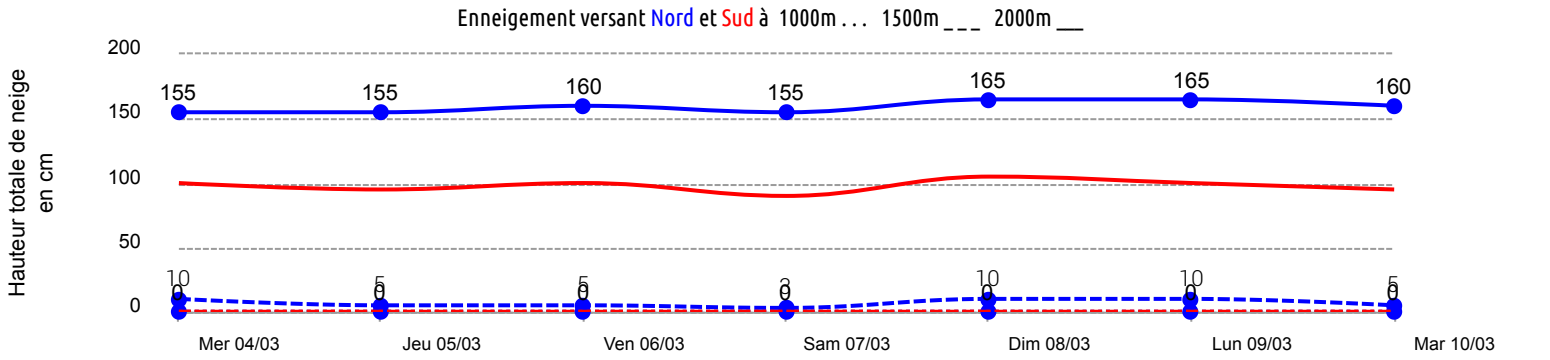

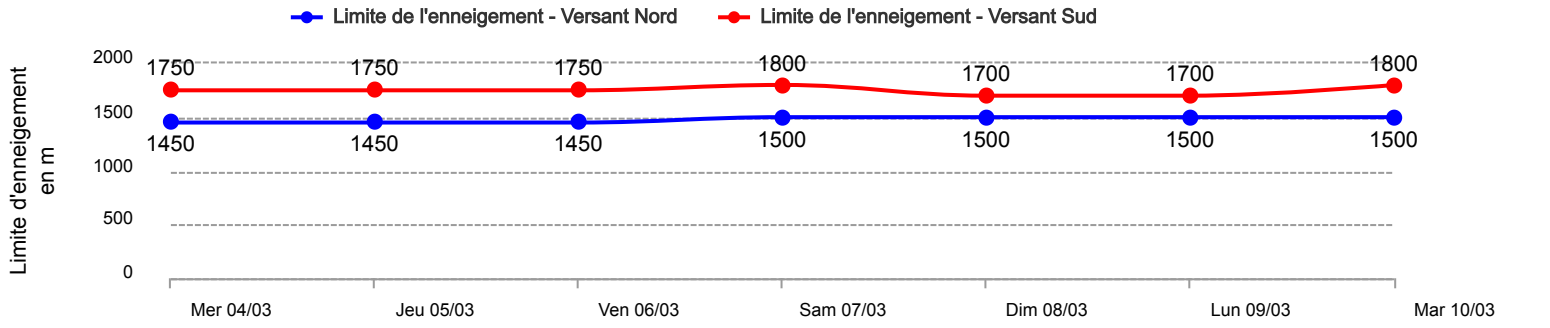

Pour consulter la vigilance en cours, veuillez vous rendre sur le site https://vigilance.meteofrance.fr/fr

Météo-France - 73 avenue de Paris, 94165 Saint-Mandé cedex - Contact : contact@meteo.fr

Rédigé par Météo-France avec la contribution des observateurs du réseau nivo-météorologiques. Partenariat : ANMSM (Maires de Stations de Montagne), DSF (Domaines Skiables de France), ADSP (Directeurs de Pistes et de la Sécurité des Stations de Sports d'Hiver) et autres acteurs de la montagne.

Bulletin neige & avalanches par téléphone au

0 892 68 10 20 Service 0,35 € / min + prix appel