GOBIERNO DE ESPAÑA
VICEPRESIDENCIA TERCERA DEL GOBIERNO
MINISTERIO PARA LA TRANSICIÓN ECOLÓGICA Y EL RETO DEMOGRÁFICO

Boletín de información nivológica y de peligro de aludes

Pirineo Navarro y Aragonés

aemet Agencia Estatal de Meteorología

miércoles, 11 de marzo de 2026

Pronóstico hasta las 24 horas del jueves, día 12 de marzo

(Válido fuera de pistas de esquí balizadas y abiertas)

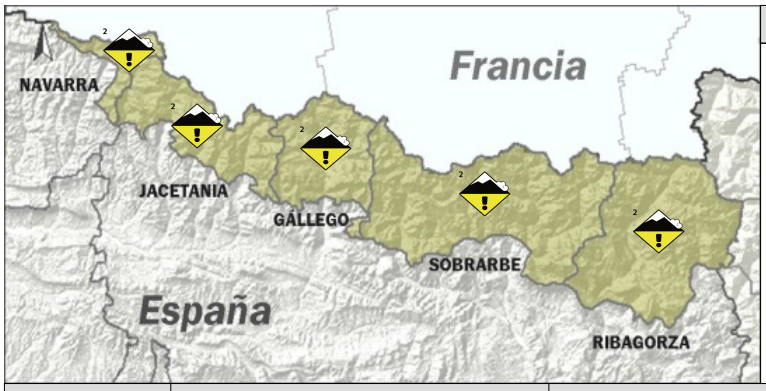

Problemas de aludes

Nieve húmeda

Placas de viento

Macizo	Peligro	Problemas de aludes, cota, orientación, tamaño	Innivación observada (m)
Navarra	2 — 2 — Limitado	Nieve húmeda: 2 — N, E, S, O — 2 Placas de viento: 2100 — N, E, S, O — 2	2026-03-11 N S Cota más baja caras N
Jacetania	2 — 2 — Limitado	Nieve húmeda: 2400 — N, E, S, O — 2 Placas de viento: 2100 — N, E, S, O — 2	2026-03-11 N S Cota más baja caras N
Gállego	2 — 2 — Limitado	Nieve húmeda: 2400 — N, E, S, O — 2 Placas de viento: 2100 — N, E, S, O — 2	2026-03-11 N S Cota más baja caras N

AEMET. Se autoriza la reproducción de su contenido citando la fuente.

Boletín de información nivológica y de peligro de aludes

Pirineo Navarro y Aragonés

Sobrarbe	2 **Limitado**	**Nieve húmeda** 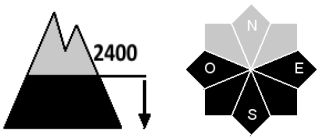 **Placas de viento** 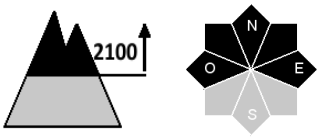	2026-03-11 Cota más baja caras N
Ribagorza	2 **Limitado**	**Nieve húmeda** 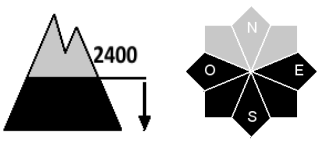 **Placas de viento** 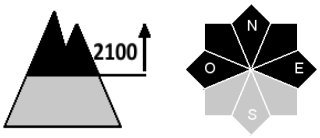	2026-03-11 Cota más baja caras N

Estado del manto y observaciones recientes

Manto continuo desde cotas medias, mostrando cierta disimetría entre solanas y umbrías. Pese a la mengua progresiva, los espesores siguen siendo importantes, rondando los 120 a 160 cm en torno a 1.800 metros y superando los 200 cm por encima de 2.100 metros, cantidades sensiblemente mayores en ventisqueros, hoyas y otras zonas propensas a la acumulación.

La nieve está humedecida hasta su base en medianías y cotas bajas, con una capa de nieve más reciente en superficie depositada durante las últimas nevadas. En en la alta montaña se presenta generalmente más seca y venteada, observándose la presencia de placas de viento que pueden estar aposentadas sobre estratos frágiles que contienen deposiciones de polvo sahariano correspondientes a jornadas previas. También es posible encontrar en las umbrías estratos débiles ubicados a considerable profundidad, y que se encuentran, por lo general, inactivos.

Evolución del manto y peligro de aludes para el jueves, día 12

Situación de nieve húmeda, y de placas de viento en cotas altas.

El ascenso térmico, así como el aumento de la insolación, tenderán a ir humedeciendo el manto desde media mañana, reblandeciendo la nieve y fundiendo las costras de rehielo que puedan formase como consecuencia de las heladas nocturnas. En consecuencia seguirán siendo probables las purgas de nieve húmeda en pendientes con suficiente inclinación, sobre todo en áreas de solana y durante las horas centrales del día, que en general serán de tamaño pequeño o mediano, pero no puede descartarse del todo algún deslizamiento basal en superficies herbosas o de roca lisa, susceptibles de movilizar una mayor cantidad de nieve.

AEMET. Se autoriza la reproducción de su contenido citando la fuente.

Las placas de viento ubicadas en la alta montaña, gran parte de ellas situadas en orientaciones noroeste, norte y nordeste, aún permanecen activas. Estas estructuras podrán fracturarse ante sobrecargas débiles, como es el paso de un esquiador, dando lugar a aludes de dimensiones pequeñas o medianas, más que suficiente como para enterrar a una persona. por lo que se recomienda tomar precauciones si se va a transitar por la zona.

Predicción meteorológica para el jueves, día 12

Intervalos nubosos, tendiendo a poco nuboso o despejado por la tarde. Temperaturas mínimas en ligero o moderado descenso, y máximas en moderado ascenso. Heladas débiles, moderadas en cotas altas. Vientos flojos o moderados del oeste y noroeste, ocasionalmente fuertes en cotas altas y zonas expuestas.

Datos en la atmósfera libre:

Altitud de la isoterma de 0 ºC: 2.600 m
Altitud de la isoterma de -10 ºC: 4.000 m

Viento a 1500 m: NW 20 km/h
Viento a 3000 m: NW 30 km/h

Evolución para el viernes día 13

Nivel de peligro con pocos cambios.

(Información elaborada a partir de los datos recibidos de los refugios de Linza, Lizara, Panticosa, Bachimaña, Góriz, Pineta, Estós, Angel Orús, La Renclusa, Cap de Llauset y Belagua, de las estaciones de esquí de Candanchú, Formigal y Panticosa (lagos), de la estación de esquí de fondo de Llanos del Hospital y de Ordesa Pradera)

Escala europea de peligro de aludes

Problemas de aludes

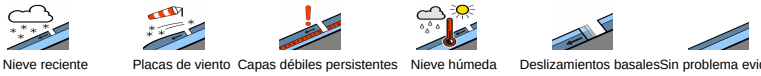

Nota1: Se recuerda que, siempre que haya nieve, la ausencia total de peligro no existe. Hay que tener presente que en circunstancias desfavorables, con aludes de tamaño 1 (alud pequeño o colada) y tamaño 2 (alud mediano), se pueden sufrir severos daños personales.

Nota2: Los BPA se elaboran en base a información meteorológica así como al estado del manto nivoso a través de sondeos puntuales. Se advierte a los usuarios de la variabilidad de esta información al extrapolarla a zonas extensas de montaña. Por ello, AEMET no se hace responsable de su uso para la toma de decisiones que conciernen a la seguridad personal, ni de los riesgos físicos o materiales de ellas derivadas.

AEMET. Se autoriza la reproducción de su contenido citando la fuente.