ICGC Institut Cartogràfic i Geològic de Catalunya

Servei Meteorològic de Catalunya meteo.cat

Boletín de peligro de aludes para el Pirineo de Catalunya
Del 11/03/2026 al 12/03/2026

(Válido fuera pistas de esquí y zonas no controladas)

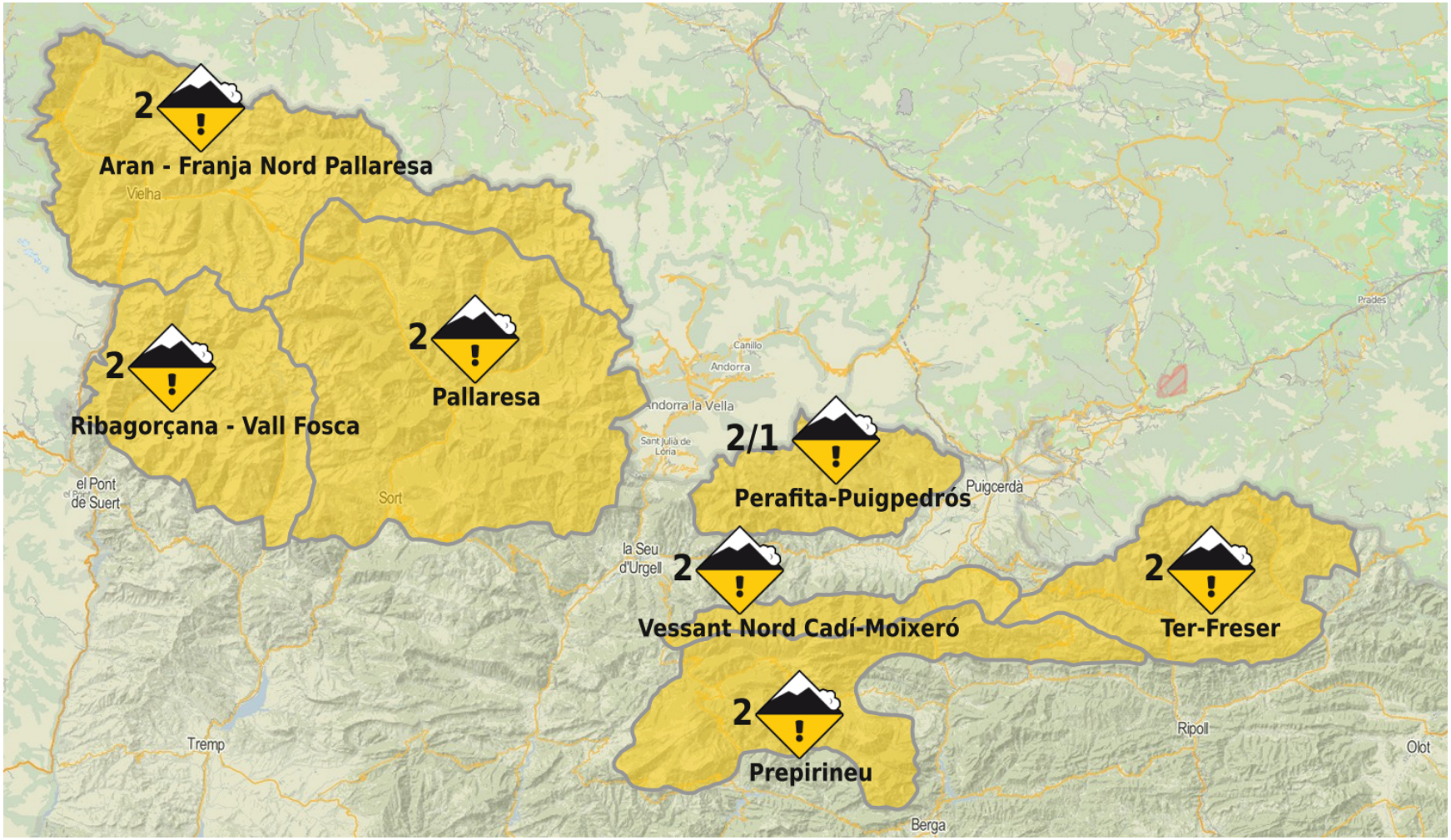

5 MUY FUERTE	4 FUERTE	3 NOTABLE	2 LIMITADO	1 DÉBIL

ICGC Institut Cartogràfic i Geològic de Catalunya

Servei Meteorològic de Catalunya

Boletín de peligro de aludes Aran - Franja Nord Pallaresa Del 11/03/2026 al 12/03/2026

(Válido fuera pistas de esquí y zonas no controladas)

LIMITADO (2)

Situación primaria

Nieve venteada

Distribución

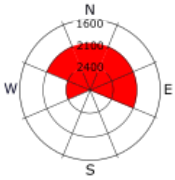

Tamaño

Origen

Tendencia

Situación secundaria

Nieve húmeda

Distribución

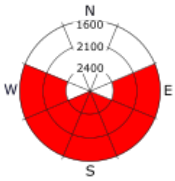

Tamaño

Origen

Tendencia

Estado del manto nivoso

La nieve sigue seca en umbrías de cota alta con niveles débiles internos que se han podido desarrollar algo más desde ayer, mientras que en solanas el manto se va humedeciendo en las horas centrales del día y se rehiela por la noche y madrugada.

Las placas, blandas en general, localizadas principalmente en umbrías de cotas altas, podrán ceder por sobrecarga y desencadenar aludes que podrían alcanzar tamaño 2, medio, en general.

A partir de mediodía, con la insolación y aumento térmico, se reactiva el humedecimiento en solanas, y orientaciones E y W de cotas bajas y medias, siendo probables la caída de bolas y aludes pequeños de nieve húmeda, localmente medianos, en vertientes más pendientes, más frecuentes bajo resaltes rocosos o árboles. Asimismo, pueden reactivarse también los deslizamientos basales sobre sustrato liso herboso o rocoso, de tamaños pequeño o mediano.

Distribución del manto nivoso

Hay nieve por encima de unos 1.400-1-500 m en umbrías y 1.700 m en solanas. Los espesores a unos 2.200 m son superiores a los normales en la Franja Nord de la Pallaresa y en la mitad sur del Aran donde rondan los 170-210 cm. En la mitad norte de Arán hay unos 110-130 cm de grosor total.

Tendencia para las próximas 48-72h

Hasta el viernes por la tarde las condiciones de estabilidad del manto variarán poco, a partir de entonces, habrá formación de nuevas placas. Peligro ESTACIONARIO hasta el viernes tarde, en AUMENTO a partir de entonces.

El próximo boletín será emitido el día 2026-03-12

5 MUY FUERTE	4 FUERTE	3 NOTABLE	2 LIMITADO	1 DÉBIL

EAWS EUROPEAN AVALANCHE WARNING SERVICES

ICGC Institut Cartogràfic i Geològic de Catalunya

Servei Meteorològic de Catalunya

Boletín de peligro de aludes Ribagorçana - Vall Fosca Del 11/03/2026 al 12/03/2026

(Válido fuera pistas de esquí y zonas no controladas)

LIMITADO (2)

Situación primaria

Nieve húmeda

Distribución

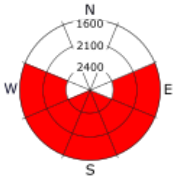

Tamaño

Origen

Tendencia

Situación secundaria

Nieve venteada

Distribución

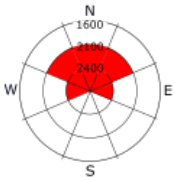

Tamaño

Origen

Tendencia

Estado del manto nivoso

Las nevadas muy débiles del miércoles no incrementarán la inestabilidad del manto, que en conjunto se muestra húmedo en solanas durante el día y con nieve seca en cotas altas de las umbrías. Por debajo del límite del bosque, el manto presenta en general unas condiciones estables hasta primeras horas de la mañana, en las que se observa una costra superficial.

A partir del mediodía, con la insolación y aumento térmico, el manto se irá humedeciendo en solanas, y también orientaciones E y W de cotas bajas y medias, y serán probables caída de bolas y aludes pequeños de nieve húmeda, localmente medianos, en laderas de fuerte pendiente, más frecuentes bajo resaltes rocosos.

En umbrías de cota alta todavía puede haber presencia de algunas placas, blandas en general, que pueden ceder al paso de una persona y desencadenar aludes de pequeño tamaño, o medio en sectores de más sobreacumulaciones.

Distribución del manto nivoso

Hay nieve en el suelo a 1.600 m en terreno umbrío, y por encima de unos 1.800 m en laderas soleadas. El manto es esquiable por encima de unos 1.800-1.900 m en umbrías. Los grosores alcanzan los 100-130 cm a unos 2.200 m. Estos valores son superiores a los normales para la época.

Tendencia para las próximas 48-72h

Hasta el viernes por la tarde las condiciones de estabilidad del manto variarán poco, a partir de entonces, habrá formación de nuevas placas. Peligro ESTACIONARIO hasta el viernes tarde, en AUMENTO a partir de entonces.

El próximo boletín será emitido el día 2026-03-12

5 MUY FUERTE	4 FUERTE	3 NOTABLE	2 LIMITADO	1 DÉBIL

EAWS EUROPEAN AVALANCHE WARNING SERVICES

ICGC Institut Cartogràfic i Geològic de Catalunya

meteo.cat Servei Meteorològic de Catalunya

Boletín de peligro de aludes Pallaresa
Del 11/03/2026 al 12/03/2026

(Válido fuera pistas de esquí y zonas no controladas)

LIMITADO (2)

Situación primaria

Nieve húmeda

Distribución

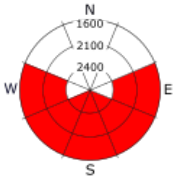

Tamaño

Origen

Tendencia

Situación secundaria

Nieve venteada

Distribución

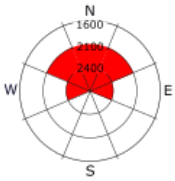

Tamaño

Origen

Tendencia

Estado del manto nivoso

Se han registrado caída de bolas y algunas purgas de nieve húmeda en solanas principalmente. Las nevadas muy débiles del miércoles no incrementarán la inestabilidad del manto, que en conjunto se muestra húmedo en solanas durante el día y con nieve seca en cotas altas de las umbrías.

Por debajo del límite del bosque, el manto presenta por lo general unas condiciones estables hasta primeras horas de la mañana, donde se observa una costra superficial. A partir del mediodía, con la insolación y aumento térmico, el manto se irá humedeciendo en solanas, y orientaciones E y W de cotas bajas y medias, y serán probables caída de bolas y aludes pequeños de nieve húmeda, localmente medianos, en laderas de fuerte pendiente, más frecuentes bajo resaltes rocosos.

En umbrías de cota alta todavía puede haber presencia de algunas placas, blandas en general, que pueden ceder al paso de una persona y desencadenar aludes de pequeño tamaño, o medio en sectores de más sobreacumulaciones.

Distribución del manto nivoso

Hay nieve en el suelo a 1.600 m en N, y a 1.800-1.900 m en S. El manto es esquiable por encima de unos 1.800-1.900 m en umbrías. Los espesores alcanzan los 110-150 cm en cotas medias, variable según los efectos del viento.

Tendencia para las próximas 48-72h

Hasta el viernes por la tarde las condiciones de estabilidad del manto variarán poco, a partir de entonces, habrá formación de nuevas placas. Peligro ESTACIONARIO hasta el viernes tarde, en AUMENTO a partir de entonces.

El próximo boletín será emitido el día 2026-03-12

5 MUY FUERTE	4 FUERTE	3 NOTABLE	2 LIMITADO	1 DÉBIL

EAWS EUROPEAN AVALANCHE WARNING SERVICES

ICGC Institut Cartogràfic i Geològic de Catalunya

Servei Meteorològic de Catalunya

Boletín de peligro de aludes Perafita-Puigpedrós Del 11/03/2026 al 12/03/2026

(Válido fuera pistas de esquí y zonas no controladas)

LIMITADO (2) a partir de mediodía
DÉBIL (1) hasta mediodía

Situación primaria

Nieve húmeda

Distribución

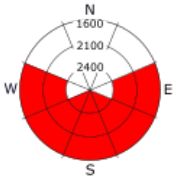

Tamaño

Origen

Tendencia

Estado del manto nivoso

Las nevadas muy débiles que el miércoles puedan caer en el sector, con viento flojo o alguna racha moderada, no harán variar la estabilidad del manto.

El manto se presenta bastante estable incluso en umbrías altas del sector, donde no se observan capas débiles internas. Hasta primeras horas de la mañana encontraremos unas condiciones estables del manto por debajo del nivel del bosque. A partir del mediodía, con la insolación y aumento térmico, el manto se irá humedeciendo en solanas, y orientaciones E y W de cotas bajas y medias, y serán probables caída de bolas y aludes pequeños de nieve húmeda, localmente medianos, en laderas más pendientes, más frecuentes bajo resaltes rocosos o árboles.

Distribución del manto nivoso

Hay nieve en el suelo por encima de unos 1.700 m en N y 1.900 en S. Los espesores, aunque irregulares, rondan los 80-100 cm en cotas medias. Son grosores por encima de los habituales para la época.

Tendencia para las próximas 48-72h

Hasta el viernes por la tarde las condiciones de estabilidad del manto variarán poco, a partir de entonces, habrá formación de nuevas placas. Peligro ESTACIONARIO hasta el viernes tarde, en AUMENTO a partir de entonces.

El próximo boletín será emitido el día 2026-03-12

5 MUY FUERTE	4 FUERTE	3 NOTABLE	2 LIMITADO	1 DÉBIL

EAWS EUROPEAN AVALANCHE WARNING SERVICES

ICGC Institut Cartogràfic i Geològic de Catalunya

meteo.cat Servei Meteorològic de Catalunya

Boletín de peligro de aludes
Vessant Nord Cadí-Moixeró
Del 11/03/2026 al 12/03/2026

(Válido fuera pistas de esquí y zonas no controladas)

LIMITADO (2)

Situación primaria

Nieve húmeda

Distribución

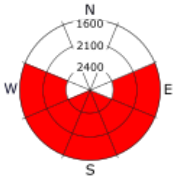

Tamaño

Origen

Tendencia

Situación secundaria

Nieve venteada

Distribución

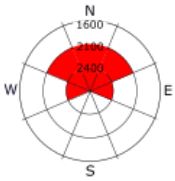

Tamaño

Origen

Tendencia

Estado del manto nivoso

El manto sigue frío en umbrías altas y húmedo en solanas durante el transcurso del día. Hasta primeras horas de la mañana encontraremos unas condiciones bastante estables del manto por debajo del nivel del bosque. A partir del mediodía, con la insolación y aumento térmico, el manto se irá humedeciendo en solanas, y orientaciones E y W de cotas bajas y medias, y serán probables caída de bolas y aludes pequeños de nieve húmeda, localmente medianos, sobre todo en las canales y bajo resaltes rocosos o árboles.

En umbrías de cota alta todavía podemos encontrar placas, blandas en general, que pueden ceder al paso de una persona y desencadenar aludes de hasta tamaño 2, medio. Serán más probables bajo collados y cordales y en las canales, donde muy localmente, en sectores de gran sobreacumulación no se descarta que algún alud pudiera llegar a tamaño 3, grande.

Distribución del manto nivoso

En umbrías hay nieve por encima de 1.600 m, esquiable por encima de unos 1.700 m. En solanas la nieve está presente por encima de 1.800 m. Los grosores están alrededor de 160-180 cm a 2.200 m. Estos valores son muy excedentarios para la época del año.

Tendencia para las próximas 48-72h

Hasta el viernes por la tarde las condiciones de estabilidad del manto variarán poco, a partir de entonces, habrá formación de nuevas placas. Peligro ESTACIONARIO hasta el viernes tarde, en AUMENTO a partir de entonces.

El próximo boletín será emitido el día 2026-03-12

5 MUY FUERTE	4 FUERTE	3 NOTABLE	2 LIMITADO	1 DÉBIL

EAWS EUROPEAN AVALANCHE WARNING SERVICES

ICGC Institut Cartogràfic i Geològic de Catalunya

Servei Meteorològic de Catalunya

Boletín de peligro de aludes Prepirineu
Del 11/03/2026 al 12/03/2026

(Válido fuera pistas de esquí y zonas no controladas)

LIMITADO (2)

Situación primaria

Nieve húmeda

Distribución

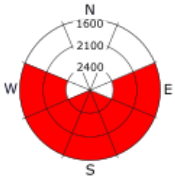

Tamaño

Origen

Tendencia

Situación secundaria

Nieve venteada

Distribución

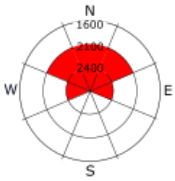

Tamaño

Origen

Tendencia

Estado del manto nivoso

No se prevén demasiados cambios en la estabilidad del manto para el jueves. Las condiciones, por debajo del nivel del bosque, permanecerán bastante estables hasta primeras horas de la mañana. A partir del mediodía, con la insolación y aumento térmico, el manto se irá humedeciendo en solanas, y orientaciones E y W de cotas bajas y medias, y serán probables caída de bolas y aludes pequeños de nieve húmeda, localmente medianos, en laderas más pendientes, sobre todo bajo resaltes rocosos o árboles.
En umbrías de cota alta todavía pueden quedar algunas placas, blandas en general, que pueden ceder al paso de una persona y desencadenar aludes que serían de tamaño 1, pequeño, o 2, medio.

Distribución del manto nivoso

En umbrías hay nieve por encima de 1.600-1700 m. En solanas la nieve está presente por encima de 1.800-1.900 m. Los espesores, aunque irregulares, rondan los 60-80 cm en cotas medias.

Tendencia para las próximas 48-72h

Hasta el viernes por la tarde las condiciones de estabilidad del manto variarán poco, a partir de entonces, habrá formación de nuevas placas. Peligro ESTACIONARIO hasta el viernes tarde, en AUMENTO a partir de entonces.

El próximo boletín será emitido el día 2026-03-12

5 MUY FUERTE	4 FUERTE	3 NOTABLE	2 LIMITADO	1 DÉBIL

EAWS EUROPEAN AVALANCHE WARNING SERVICES

ICGC Institut Cartogràfic i Geològic de Catalunya

Servei Meteorològic de Catalunya meteo.cat

Boletín de peligro de aludes Ter-Freser
Del 11/03/2026 al 12/03/2026

(Válido fuera pistas de esquí y zonas no controladas)

LIMITADO (2)

Situación primaria

Nieve húmeda

Distribución

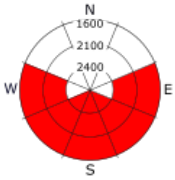

Tamaño

Origen

Tendencia

Situación secundaria

Nieve venteada

Distribución

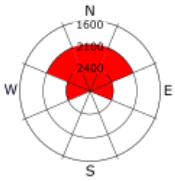

Tamaño

Origen

Tendencia

Estado del manto nivoso

Las nevadas muy débiles que el miércoles puedan caer en el sector, con viento flojo o alguna racha moderada, no harán variar la estabilidad del manto. Hasta primeras horas de la mañana encontraremos unas condiciones bastante estables del manto por debajo del nivel del bosque. A partir del mediodía, con la insolación y aumento térmico, el manto se irá humedeciendo en solanas, y orientaciones E y W de cotas bajas y medias, y serán probables caída de bolas y aludes pequeños de nieve húmeda, localmente medianos, en laderas más pendientes, más frecuentes bajo resaltes rocosos o árboles.

En umbrías de cota alta todavía podemos encontrar placas, blandas en general, que pueden ceder al paso de una persona y desencadenar aludes de hasta tamaño 2, medio. En sectores muy puntuales y más favorables de acumulación no se descarta que algún alud pudiera llegar a tamaño 3, grande.

Distribución del manto nivoso

Hay nieve en el suelo por encima de 1.600-1.700 m. Es esquiable a partir de unos 1700 m. El manto nivoso presenta grosores muy excedentarios para la época del año. En lugares no afectados por el viento los grosores oscilan entre 80-100 cm a unos 2.000 m y más de 150 cm por encima de 2.400 m.

Tendencia para las próximas 48-72h

Hasta el viernes por la tarde las condiciones de estabilidad del manto variarán poco, a partir de entonces, habrá formación de nuevas placas. Peligro ESTACIONARIO hasta el viernes tarde, en AUMENTO a partir de entonces.

El próximo boletín será emitido el día 2026-03-12

5 MUY FUERTE	4 FUERTE	3 NOTABLE	2 LIMITADO	1 DÉBIL

EAWS EUROPEAN AVALANCHE WARNING SERVICES