BUTLLETÍ DEL PERILL D'ALLAUS DEL PRINCIPAT D'ANDORRA

Servei meteorològic nacional
Principat d'Andorra

Elaborat el 11/03/2026 16:00
Propera actualització 12/03/2026 a les 16h

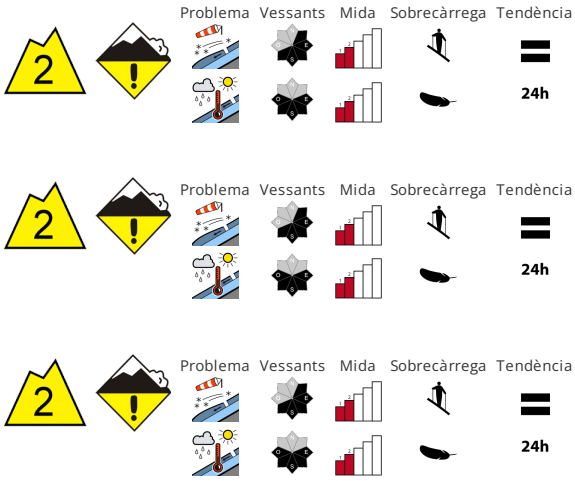

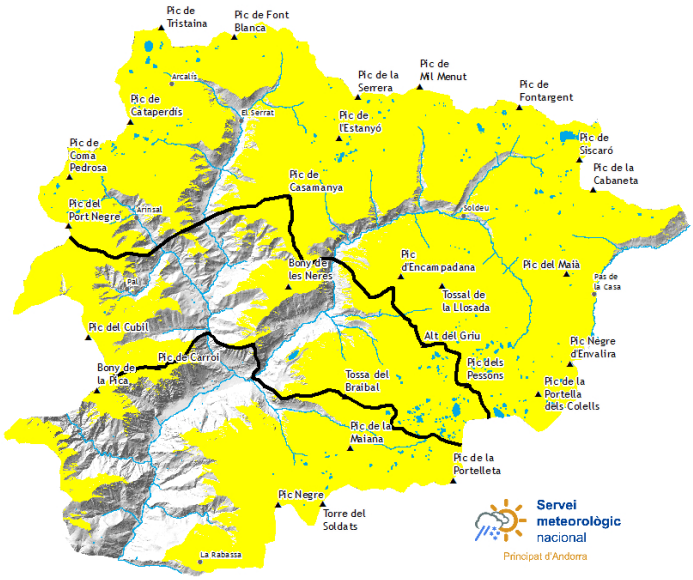

ESTABILITAT DEL MANTELL NIVAL

En el transcurs de la nit, amb la neu nova i l'augment del vent de nord-oest, es formaran plaques de vent majoritàriament de mida petita especialment als vessants prop de les carenes orientats a nord-est , est i sud-est. Aquestes poden ser desencadenades fàcilment o de manera natural. A més del perill de ser enterrat per una allau, cal tenir en compte també el perill de ser arrossegat cap a una trampa del terreny. Amb la pujada de la temperatura i la radiació solar diürna, sobretot als vessants assolellats són possibles algunes allaus de neu humida de mida petita i mitjana. A més, són possibles allaus de lliscament basal en qualsevol moment.

QUALITAT DE LA NEU

A cotes baixes : la superfície del mantell de neu es regelarà per formar una crosta portant i s'estovarà ja durant el matí. als vessants obacs i a cotes mitges i altes : la part superior del mantell és seca, amb una superfície solta. Evitar les zones amb esquerdes de lliscament basal. Sobretot prop de colls i carenes els gruixos de neu varien molt per sobre dels 2400 m aproximadament per la influència del vent. Fins al divendres el temps serà parcialment assolellat. El dissabte caurà neu per sobre dels 1200 m aproximadament sobretot als al nord.

GRUIXOS DEL MANTELL NIVAL FORA DE PISTA

Zona nord		Gruix neu		
Mantell Nival		1500m	2000m	2500m
N	1600 m	0 cm	150 cm	200 cm
S	1900 m	0 cm	100 cm	150 cm

Zona centre		Gruix neu		
Mantell Nival		1500m	2000m	2500m
N	1600 m	0 cm	150 cm	200 cm
S	1900 m	0 cm	100 cm	150 cm

Zona sud		Gruix neu		
Mantell Nival		1500m	2000m	2500m
N	1600 m	0 cm	120 cm	150 cm
S	1900 m	0 cm	60 cm	100 cm

Govern d'Andorra

EAWS EUROPEAN AVALANCHE WARNING SERVICES

Aquest butlletí ha estat elaborat seguint les normes i recomanacions de l'**European Avalanche Warning Services**, del qual el **Servei meteorològic Nacional** n'és membre

BUTLLETÍ DEL PERILL D'ALLAUS DEL PRINCIPAT D'ANDORRA

Servei meteorològic nacional
Principat d'Andorra

Informació detallada per espais naturals protegits

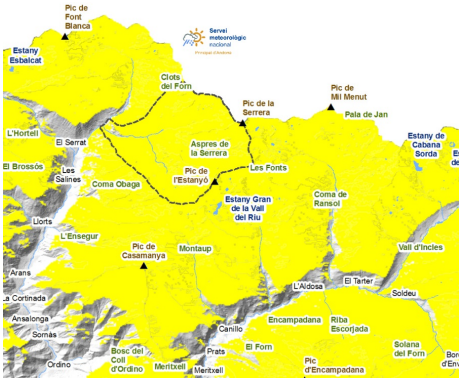

SORTENY

El vent associat al pas del front d´aquesta propera nit de dimecres a dijous transportarà la neu pols i pot crear plaques als vessants amb component est. Localment aquestes plaques es poden formar a sobre de gebre, que pot actuar com a capa feble. Durant el dia la temperatura pujarà notablement i podem tenir un pic d´activitat d´allaus naturals de neu humida, sobretot als vessants assolellats.

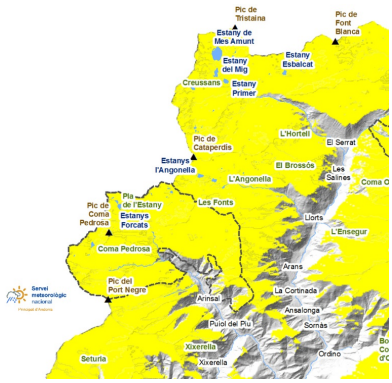

COMAPEDROSA

Com a Sorteny, el vent crearà noves acumulacions als vessants amb component est, mentre l´augment de temperatures al llarg del dia facilitarà que baixin allaus de neu humida que en algun cas poden arribar als camins de les parts baixes del Parc.

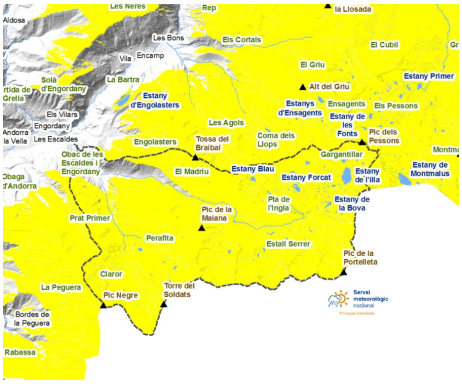

MADRIU-PERAFITA-CLAROR

Els vessants est es veuran una altra vegada carregats amb plaques de vent. En altura encara trobarem neu pols durant el matí, però tindrà tendència a transformar-se al llarg del dia.

Govern d'Andorra

EAWS
EUROPEAN AVALANCHE WARNING SERVICES

Aquest butlletí ha estat elaborat seguint les normes i recomanacions de l'**European Avalanche Warning Services**, del qual el **Servei meteorològic Nacional** n'és membre

BUTLLETÍ DEL PERILL D'ALLAUS DEL PRINCIPAT D'ANDORRA

Servei meteorològic nacional
Principat d'Andorra

Gruixos de neu nova dels darrers dies (de les últimes 24h mesurat a les 06:00h UTC)

	07/03/2026	08/03/2026	09/03/2026	10/03/2026
FEDA (Central)	0 cm	0 cm	0 cm	0 cm
Engolasters - FEDA	0 cm	0 cm	0 cm	0 cm
Bony de les Neres	0 cm	0 cm	0 cm	0 cm
Sorteny	2 cm	6 cm	4 cm	0 cm
Les Fonts d'Arinsal	0 cm	4 cm	0 cm	0 cm
Perafita	0 cm	3 cm	0 cm	0 cm
Tossa Espiolets	0 cm	2 cm	0 cm	0 cm
Grau Roig - FEDA	0 cm	4 cm	1 cm	0 cm
Fontverd	0 cm	1 cm	0 cm	0 cm
Ransol - FEDA	0 cm	0 cm	0 cm	0 cm
Caborreu	0 cm	2 cm	0 cm	1 cm
La Solana	1 cm	5 cm	0 cm	0 cm
Coll Pa	0 cm	0 cm	0 cm	0 cm
Envalira Antenes	0 cm	9 cm	3 cm	2 cm
Vall del Riu FEDA	3 cm	3 cm	0 cm	0 cm