BUTLLETÍ DEL PERILL D'ALLAUS DEL PRINCIPAT D'ANDORRA

Elaborado el 11/03/2026 16:00
Proxima actualización 12/03/2026 a las 16h

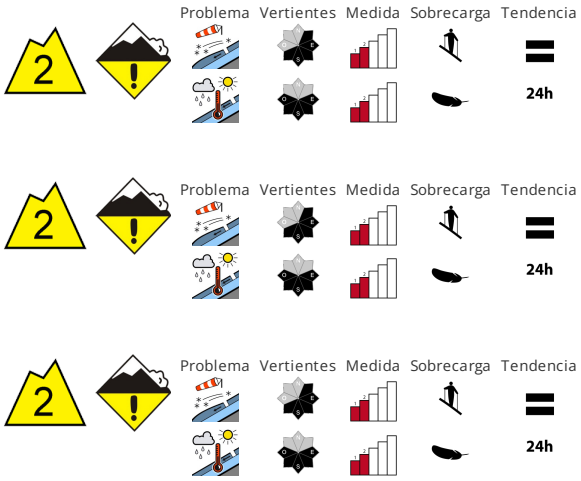

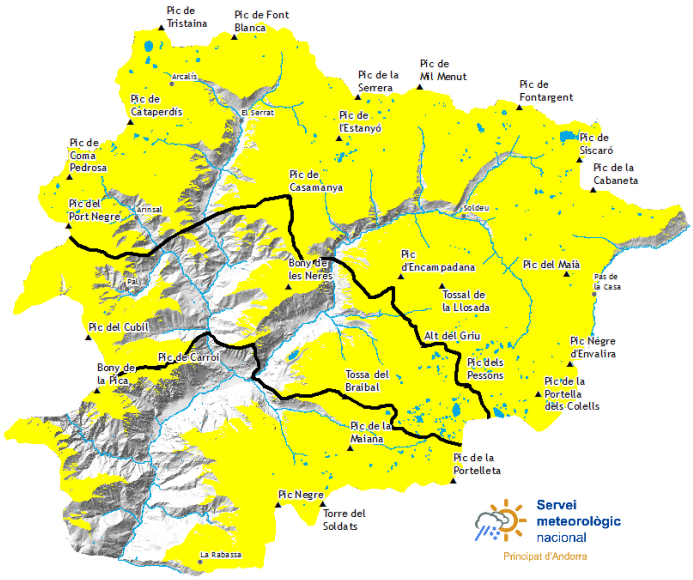

CALIDAD DE LA NIEVE

En el transcurso de la noche, con la nieve reciente y el aumento del viento de noroeste, se formarán placas de viento en su mayoría de tamaño pequeño especialmente en las laderas cercanas a los cordales orientadas a nordeste , este y sudeste. Estas pueden ser desencadenadas fácilmente o de forma natural. Además del peligro de ser enterrado por un alud, se debe tener en cuenta también el peligro de ser arrastrado hacia una trampa del terreno. Con la subida de la temperatura y la radiación solar diurna, sobre todo en las laderas solanas son posibles algunas avalanchas de nieve húmeda de tamaño pequeño y mediano. Además son posibles aludes de deslizamiento basal en cualquier momento.

ESTABILIDAD DEL MANTO NIVOSO

En cotas bajas :. La superficie del manto de nieve se volverá a helar para formar una costra portante y se ablandará ya durante la mañana. en las laderas umbrías y en cotas medias y altas :. La parte superior del manto es seca, con una superficie blanda. Evitar las zonas con grietas de deslizamiento basal. Sobre todo cerca de collados y cordales los espesores de nieve varían mucho por encima de los 2400 m aproximadamente por la influencia del viento. Hasta el viernes el tiempo será parcialmente soleado. El sábado caerá nieve por encima de los 1200 m aproximadamente sobre todo en los norte.

ESPESORES DEL MANTO NIVOSO FUERA DE PISTA

Zona norte		Espesor nieve		
Manto Nival		1500m	2000m	2500m
N	1600 m	0 cm	150 cm	200 cm
S	1900 m	0 cm	100 cm	150 cm

zona centro		Espesor nieve		
Manto Nival		1500m	2000m	2500m
N	1600 m	0 cm	150 cm	200 cm
S	1900 m	0 cm	100 cm	150 cm

Zona sur		Espesor nieve		
Manto Nival		1500m	2000m	2500m
N	1600 m	0 cm	120 cm	150 cm
S	1900 m	0 cm	60 cm	100 cm

Govern d'Andorra

EAWS EUROPEAN AVALANCHE WARNING SERVICES

Aquest butlletí ha estat elaborat seguint les normes i recomanacions de l'**European Avalanche Warning Services**, del qual el **Servei meteorològic Nacional** n'és membre

BUTLLETÍ DEL PERILL D'ALLAUS DEL PRINCIPAT D'ANDORRA

Servei meteorològic nacional
Principat d'Andorra

Información detallada por espacios naturales protegidos

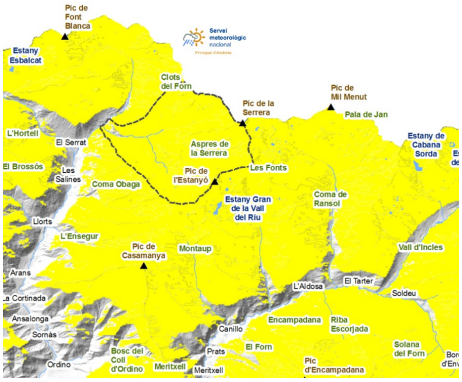

SORTENY

El viento asociado al paso del frente de esta próxima noche del miércoles al jueves transportará la nieve polvo y puede crear placas en las laderas con componente este. Localmente estas placas se pueden formar sobre escarcha, que puede actuar como capa débil. Durante el día la temperatura subirá notablemente y podemos tener un pico de actividad de aludes naturales de nieve húmeda, sobre todo en las vertientes soleadas.

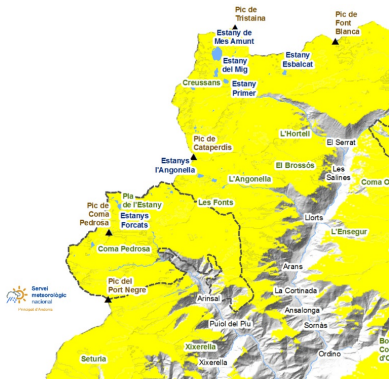

COMAPEDROSA

Como en Sorteny, el viento creará nuevas acumulaciones en las laderas con componente este, mientras el aumento de temperaturas a lo largo del día facilitará que bajen aludes de nieve húmeda que en algún caso pueden llegar a los caminos de las partes bajas del Parque.

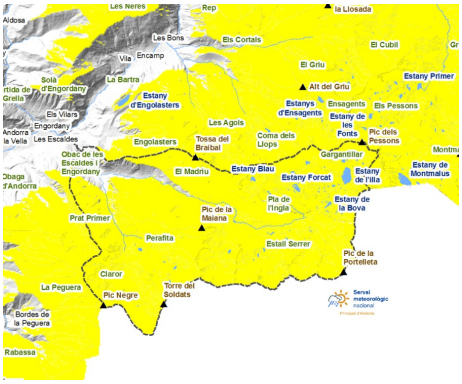

MADRIU-PERAFITA-CLAROR

Las vertientes este se verán otra vez cargadas con placas de viento. En altura todavía encontraremos nieve polvo durante la mañana, pero tendrá tendencia a transformarse a lo largo del día.

Govern d'Andorra

EAWS EUROPEAN AVALANCHE WARNING SERVICES

Aquest butlletí ha estat elaborat seguint les normes i recomanacions de l'**European Avalanche Warning Services**, del qual el **Servei meteorològic Nacional** n'és membre

BUTLLETÍ DEL PERILL D'ALLAUS DEL PRINCIPAT D'ANDORRA

Servei meteorològic nacional
Principat d'Andorra

Espesores de nieve nueva de los últimos días (de las ultimas 24h mesurado a las 06:00h UTC)

	07/03/2026	08/03/2026	09/03/2026	10/03/2026
FEDA (Central)	0 cm	0 cm	0 cm	0 cm
Engolasters - FEDA	0 cm	0 cm	0 cm	0 cm
Bony de les Neres	0 cm	0 cm	0 cm	0 cm
Sorteny	2 cm	6 cm	4 cm	0 cm
Les Fonts d'Arinsal	0 cm	4 cm	0 cm	0 cm
Perafita	0 cm	3 cm	0 cm	0 cm
Tossa Espiolets	0 cm	2 cm	0 cm	0 cm
Grau Roig - FEDA	0 cm	4 cm	1 cm	0 cm
Fontverd	0 cm	1 cm	0 cm	0 cm
Ransol - FEDA	0 cm	0 cm	0 cm	0 cm
Caborreu	0 cm	2 cm	0 cm	1 cm
La Solana	1 cm	5 cm	0 cm	0 cm
Coll Pa	0 cm	0 cm	0 cm	0 cm
Envalira Antenes	0 cm	9 cm	3 cm	2 cm
Vall del Riu FEDA	3 cm	3 cm	0 cm	0 cm