BUTLLETÍ DEL PERILL D'ALLAUS DEL PRINCIPAT D'ANDORRA

Préparé le 11/03/2026 16:00
Prochaine mise à jour le 12/03/2026 à 16h

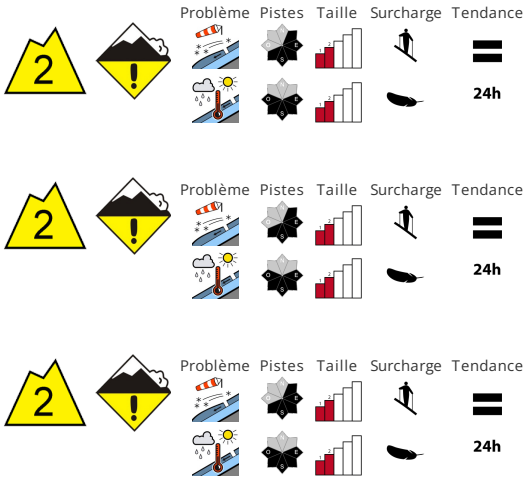

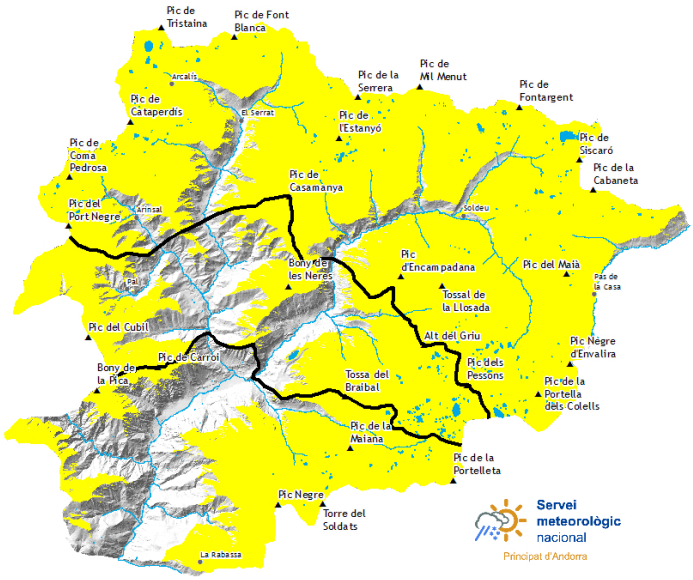

STABILITÉ DU MANTEAU NEIGEUX

Des accumulations de neige soufflée en général petites se forment avec la neige récente et le vent du nord-ouest, en cours de nuit sur les pentes exposées au nord-est , à l'est et au sud-est surtout à proximité des crêtes. Celles-ci peuvent peut être déchaîné facilement ou se déclencher spontanément.. A côté du danger d'ensevelissement, il faut aussi penser au danger d'être emporté et de chuter.. Avec le réchauffement diurne et le rayonnement solaire de rares avalanches humides de petite et moyenne taille sont possibles surtout sur les pentes au soleil. En outre, des avalanches de glissement sont possibles à tout moment..

QUALITÈ DE LA NEIGE

À basse altitude (-):. La surface de la neige regèle et devient porteuse et se ramollit dès la matinée.. sur les pentes à l'ombre et aux altitudes moyennes et élevées (-):. La zone supérieure du manteau neigeux est sèche , avec une surface meuble. Les zones présentant des fissures de glissement doivent être évitées.. Surtout à proximité des crêtes et des cols on trouve suivant l'influence du vent des hauteurs de neiges très différentes au-dessus d'environ 2400 m. Jusqu'à vendredi il fait un temps partiellement ensoleillé. Samedi il tombera de la neige au-dessus d'environ 1200 m surtout au nord.

EPAISSEUR DE NEIGE HORS PISTE

Zone nord		Epaisseur de neige		
Nival manteau		1500m	2000m	2500m
N	1600 m	0 cm	150 cm	200 cm
S	1900 m	0 cm	100 cm	150 cm

Zone centre		Epaisseur de neige		
Nival manteau		1500m	2000m	2500m
N	1600 m	0 cm	150 cm	200 cm
S	1900 m	0 cm	100 cm	150 cm

Zone sud		Epaisseur de neige		
Nival manteau		1500m	2000m	2500m
N	1600 m	0 cm	120 cm	150 cm
S	1900 m	0 cm	60 cm	100 cm

Govern d'Andorra

Aquest butlletí ha estat elaborat seguint les normes i recomanacions de l'**European Avalanche Warning Services**, del qual el **Servei meteorològic Nacional** n'és membre

BUTLLETÍ DEL PERILL D'ALLAUS DEL PRINCIPAT D'ANDORRA

Servei meteorològic nacional
Principat d'Andorra

Des informations détaillées par espace naturel protégé

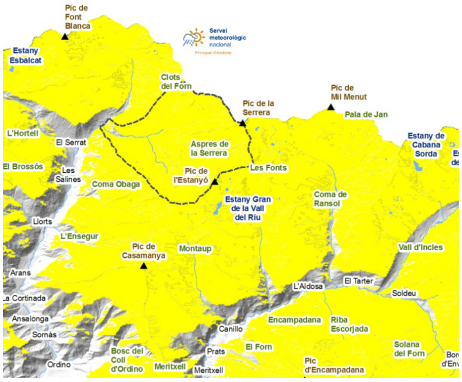

SORTENY

Le vent associé au passage du front dans la nuit de mercredi à jeudi entraînera la neige poudreuse et pourrait créer des plaques sur les pentes est. Localement, ces plaques peuvent se former sur le gel, qui peut agir comme une couche fragile. Pendant la journée, la température augmentera considérablement et nous pourrons avoir un pic d'activité d'avalanches naturelles de neige mouillée, surtout sur les pentes ensoleillées. , , , , ,

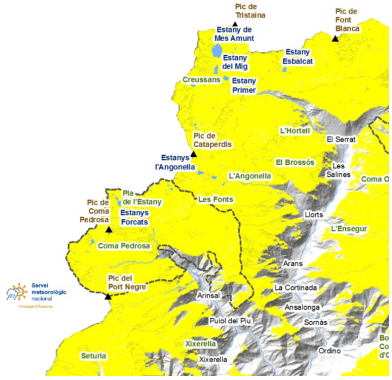

COMAPEDROSA

Comme à Sorteny, le vent créera de nouvelles accumulations sur les pentes avec une composante orientale, tandis que l'augmentation des températures tout au long de la journée facilitera la chute des avalanches de neige mouillée qui, dans certains cas, pourront atteindre les sentiers des parties basses du Parc. ,

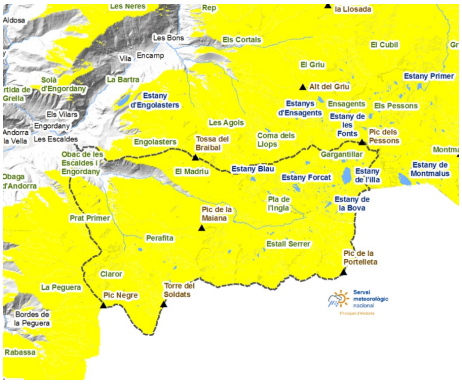

MADRIU-PERAFITA-CLAROR

Les versants Est seront à nouveau chargés de plaques de vent. En altitude on trouvera encore de la poudreuse au cours de la matinée, mais elle aura tendance à changer au cours de la journée. , , ,

Govern d'Andorra

EAWS
EUROPEAN AVALANCHE WARNING SERVICES

Aquest butlletí ha estat elaborat seguint les normes i recomanacions de l'**European Avalanche Warning Services**, del qual el **Servei meteorològic Nacional** n'és membre

BUTLLETÍ DEL PERILL D'ALLAUS DEL PRINCIPAT D'ANDORRA

Servei meteorològic nacional
Principat d'Andorra

Couche de neige fraiche des derniers jours (De 24 h mesurée à 06:00 h UTC)

	07/03/2026	08/03/2026	09/03/2026	10/03/2026
FEDA (Central)	0 cm	0 cm	0 cm	0 cm
Engolasters - FEDA	0 cm	0 cm	0 cm	0 cm
Bony de les Neres	0 cm	0 cm	0 cm	0 cm
Sorteny	2 cm	6 cm	4 cm	0 cm
Les Fonts d'Arinsal	0 cm	4 cm	0 cm	0 cm
Perafita	0 cm	3 cm	0 cm	0 cm
Tossa Espiolets	0 cm	2 cm	0 cm	0 cm
Grau Roig - FEDA	0 cm	4 cm	1 cm	0 cm
Fontverd	0 cm	1 cm	0 cm	0 cm
Ransol - FEDA	0 cm	0 cm	0 cm	0 cm
Caborreu	0 cm	2 cm	0 cm	1 cm
La Solana	1 cm	5 cm	0 cm	0 cm
Coll Pa	0 cm	0 cm	0 cm	0 cm
Envalira Antenes	0 cm	9 cm	3 cm	2 cm
Vall del Riu FEDA	3 cm	3 cm	0 cm	0 cm