Bulletin d'estimation du risque d'avalanche

(valable en dehors des pistes balisées et ouvertes)

MASSIF : Aure Louron

Rédigé le mercredi 11 mars 2026 à 16h

Estimation des risques pour le : JEUDI 12 MARS

RECENTES PETITES CHUTES DE NEIGE VENTEES, AU SOLEIL EN JOURNEE DE JEUDI.

2

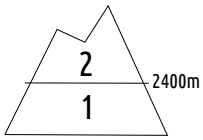

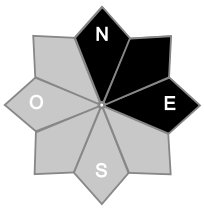

Au-dessus de 2400m indice de risque limité, plus bas indice faible.

Départs spontanés : en neige récente, s'humidifiant au soleil, quelques avalanches de fond.

Déclenchements provoqués : plaques instables au-dessus de 2400m en Nord à Est.

Indices de risque : 5 très fort - 4 fort - 3 marqué - 2 limité - 1 faible -- En noir : les pentes les plus dangereuses

Stabilité du manteau neigeux

Situation avalancheuse typique : neige ventée neige humide

Déclenchements provoqués :
- **au-dessus de 2300/24000m en secteurs Nord à Est**, **plaques instables peu épaisses** formées par les chutes de neige faibles et légèrement ventées d'Ouest à Nord-Ouest de mercredi. **Un seul skieur ou randonneur peut facilement déclencher une avalanche de taille petite à moyenne dans ces pentes Nord, Nord-Est et Est**, où la neige légèrement frittée de mercredi s'est déposé à l'ombre et à l'abri du vent sur la **neige de la fin de semaine dernière** restée sèche, meuble et sans cohésion (**mobilisable et servant ainsi de couche fragile**). Ces plaques sont **peu identifiables,** situées près des cols et des crêtes.
- les **anciennes structures de plaques**, présentes au-dessus de 2400m dans les pentes Nord, bien enfouies, restent quant à elles **difficilement déclenchables**.
- partout ailleurs, déclenchements peu probables en début de journée, **sollicitation forte à moyenne nécessaire** pour déclencher une **coulée de neige s'humidifiant au soleil**.

Départs spontanés :
- en **pentes raides**, **rares** et en **départs ponctuels** de neige récente en **début de journée**, **coulées et petites avalanches de neige humide au soleil** un peu plus fréquentes au cours de la journée, quelques unes de taille moyenne possibles au plus chaud de la journée près d'une rupture de pentes, par chutes d'une corniche fragilisée au soleil entraînant le manteau neigeux humide et lourd en contrebas.
- **localement**, cassure linéaire encore possible et départ d'une **avalanche de fond de taille moyenne**, **rarement grande,** dans un large secteur Sud, en partant des **accumulations encore en place** ou au niveau des **fissures**.

Autres : ponts de neige et corniches fragilisés au soleil.

Qualité de la neige

Enneigement : enneigement encore assez bon pour la saison, plutôt maigre en versants exposés au vent d'Ouest et en versants Sud.
Limites skiables : à partir de 1500/1600m en versants froids, plutôt 1800/1900m en versants Sud
État de la neige : en début de matinée, regel nocturne correct sous 1700/1800m, quelques centimètres de neige récente légèrement travaillée par le vent au-dessus, posés sur un manteau ressaisi et portant. En journée, humidification progressive au soleil, rapide dans les pentes sud-Est à Sud-Ouest raides, lent à l'ombre sous 2000/2200m, neige restant sèche mais légèrement fritté au-dessus de 2300/2400m. Corniches encore fréquentes vers les crêtes et cols.

Aperçu météo pour le jeudi 12 mars

	nuit	matin	après-midi	soir

Temps sec et bien ensoleillé, redoux rapide.

Pluie-Neige				
Iso 0 °C	2 400 m	2 500 m	2 500 m	2 600 m
Vent 1500 m	↑ 10 km/h	↓ 5 km/h	↓ 10 km/h	↑ 5 km/h
Vent 3000 m	↘ 40 km/h	↘ 30 km/h	↘ 40 km/h	↘ 20 km/h

Épaisseur de neige hors-piste

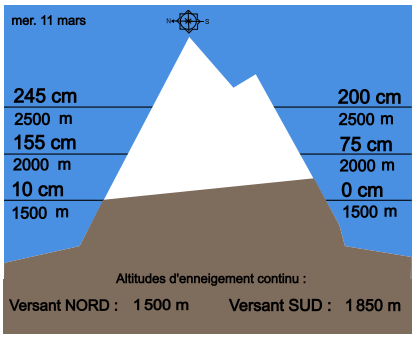

Précipitations à 1800 m

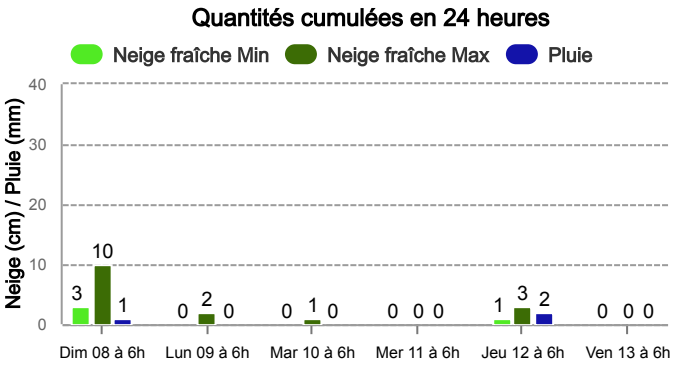

Tendance du vendredi 13 mars

2 **Indice de risque limité**

Temps encore sec et assez bien ensoleillé en journée de vendredi après un bon regel, risque restant "limité" pour les départs provoqués dans les pentes Nord d'altitude. Par contre, risque en augmentation rapide dans la nuit de vendredi à samedi avec le temps perturbé, froid, neigeux et venté qui se profile.

Pour consulter la vigilance en cours, veuillez vous rendre sur le site https://vigilance.meteofrance.fr/fr

Météo-France - 73 avenue de Paris, 94165 Saint-Mandé cedex - Contact : contact@meteo.fr

Rédigé par Météo-France avec la contribution des observateurs du réseau nivo-météorologiques. Partenariat : ANMSM (Maires de Stations de Montagne), DSF (Domaines Skiables de France), ADSP (Directeurs de Pistes et de la Sécurité des Stations de Sports d'Hiver) et autres acteurs de la montagne.

Bulletin neige & avalanches par téléphone au **0 892 68 10 20** Service 0,35 € / min + prix appel

RÉPUBLIQUE FRANÇAISE
Liberté Égalité Fraternité

METEO FRANCE
À VOS CÔTÉS, DANS UN CLIMAT QUI CHANGE

Bulletin d'estimation du risque d'avalanche

(valable en dehors des pistes balisées et ouvertes)

MASSIF : Aure Louron

Rédigé le mercredi 11 mars 2026 à 16h

Conditions nivo-météo des 7 derniers jours

	jeu. 05/03				ven. 06/03				sam. 07/03				dim. 08/03				lun. 09/03				mar. 10/03				mer. 11/03			
	03h	09h	15h	21h	03h	09h	15h	21h	03h	09h	15h	21h	03h	09h	15h	21h	03h	09h	15h	21h	03h	09h	15h	21h	03h	09h	15h	21h
Météo																												
Vent (km/h)	45	45	40	35	55	55	30	50	25	20	40	50	30	20	20	15	10	15	20	15	15	10	45	35	40	65	60	55
à 3000m																												
Vent (km/h)	30	25	20	20	10	10	15	10	10	15	10	10	10	5	5	5	2	5	5	5	5	5	15	10	20	15	15	5
à 1500m																												

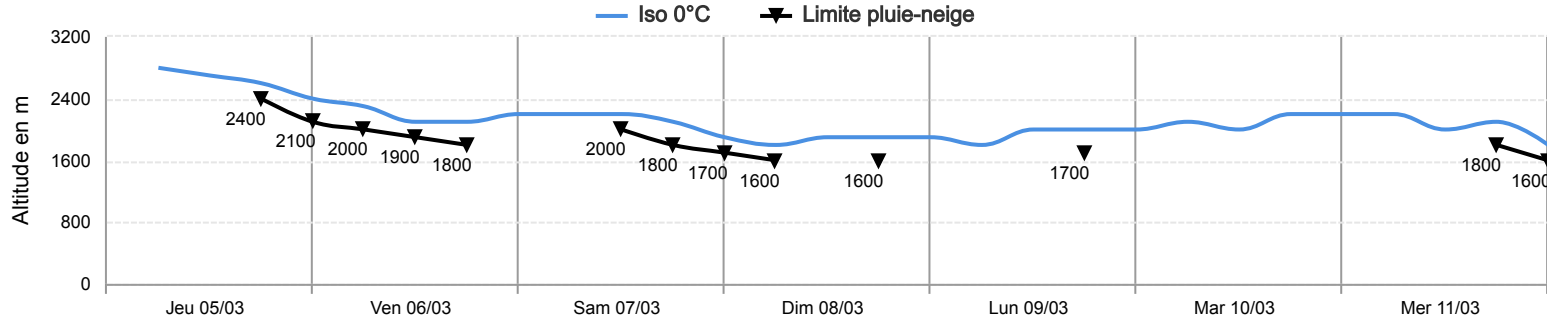

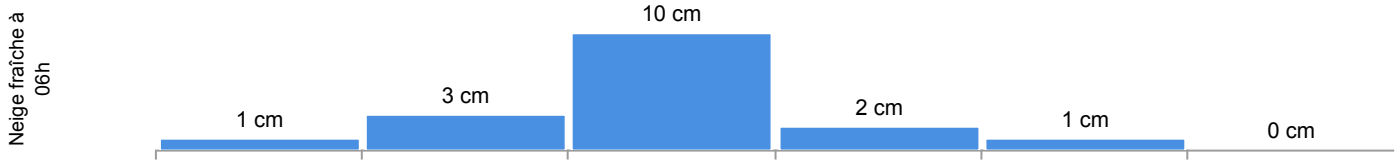

Risque d'avalanche	jeu. 05/03	ven. 06/03	sam. 07/03	dim. 08/03	lun. 09/03	mar. 10/03	mer. 11/03
	2	2	2	2	2	2	2

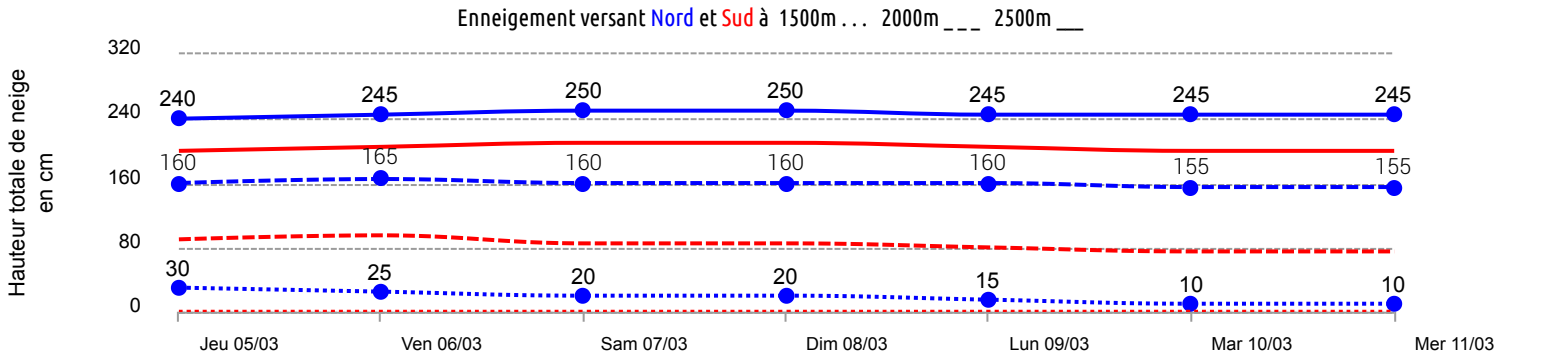

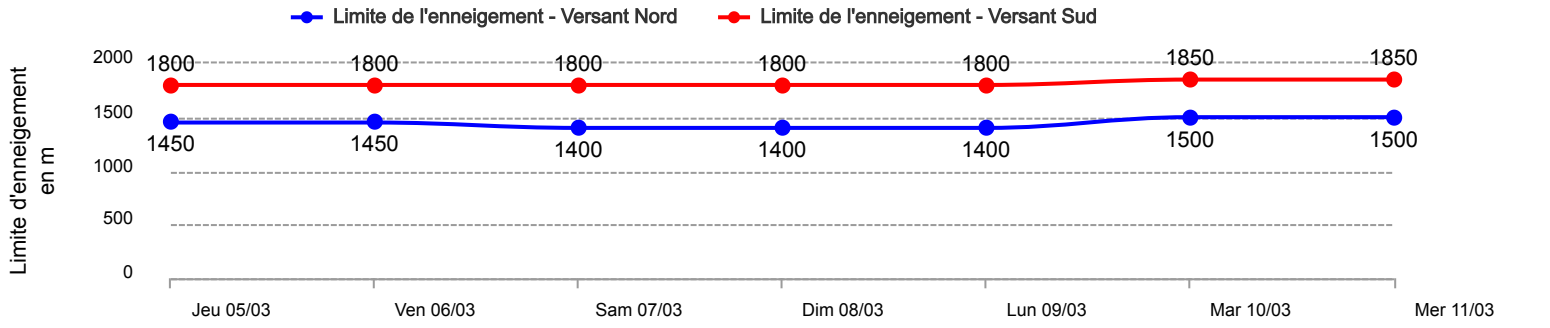

Pour consulter la vigilance en cours, veuillez vous rendre sur le site https://vigilance.meteofrance.fr/fr

Météo-France - 73 avenue de Paris, 94165 Saint-Mandé cedex - Contact : contact@meteo.fr

Rédigé par Météo-France avec la contribution des observateurs du réseau nivo-météorologiques. Partenariat : ANMSM (Maires de Stations de Montagne), DSF (Domaines Skiables de France), ADSP (Directeurs de Pistes et de la Sécurité des Stations de Sports d'Hiver) et autres acteurs de la montagne.

Bulletin neige & avalanches par téléphone au
0 892 68 10 20 Service 0,35 € / min + prix appel