RÉPUBLIQUE FRANÇAISE
Liberté Égalité Fraternité

METEO FRANCE
À VOS CÔTÉS, DANS UN CLIMAT QUI CHANGE

Bulletin d'estimation du risque d'avalanche
(valable en dehors des pistes balisées et ouvertes)

MASSIF : Beaufortain

Rédigé le mercredi 11 mars 2026 à 16h

Estimation des risques pour le : JEUDI 12 MARS

NOUVELLES AVALANCHES DE PLAQUE POSSIBLES SUITE AUX CHUTES DE NEIGE DE LA NUIT.

2

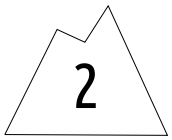

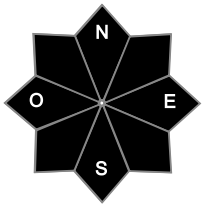

Indice de risque limité.

Départs spontanés : départs ponctuels en suivant la course du Soleil.

Déclenchements provoqués : quelques plaques d'aspect poudreux.

Indices de risque : 5 très fort - 4 fort - 3 marqué - 2 limité - 1 faible -- En noir : les pentes les plus dangereuses

Stabilité du manteau neigeux

Situation avalancheuse typique : neige fraîche neige humide

Déclenchement provoqués : les chutes de neige de la nuit de mercredi à jeudi crées des plaques d'aspect poudreux en tous versants. Elles gagnent en épaisseur au-delà de 1800/2000 m avec des cumuls de neige fraîche dépassant 10/15 cm. Les plaques installées en versant ombragé (NE, N et NO) au-delà de 2400 m sont particulièrement réactives car elles reposent sur des grains anguleux (face plane). Avalanche de taille moyenne (taille 2) à prévoir.

Départs spontanés : nombreux départs en poire (départs ponctuels) aux abords des cailloux dans les pentes raides, au gré de la course du Soleil (taille 1 à 2). Aussi, rares avalanches de glissement, allant jusqu'à la taille moyenne car le manteau neigeux est épais. Plutôt sous les 2400m et sur terrains propices de type pentes herbeuses et dalles rocheuses.

Qualité de la neige

Enneigement : en général légèrement excédentaire pour la saison, mais en train de devenir déficitaire en basse montagne et en versants sud.

Limite skiable : encore skiable dès 1100/1200 m dans les prairies orientées nord, plutôt 1400/1500 m en sud pas trop raide.

Qualité de la neige : nouvelle couche de neige fraîche en montagne. Il faut monter au-delà de 1800/2000 m pour observer un cumul de 10/15 cm. En coeur de massif, le cumul monte à 15/20 cm. Elle est poudreuse et faiblement travaillée par le vent dans toutes les orientations au réveil.
Cependant, au gré de la course du Soleil, cette neige fraîche s'humidifie rapidement. Gare au "bottage" à la montée !

Aperçu météo pour le jeudi 12 mars

	nuit	matin	après-midi	soir
	Retour d'un Soleil très large en matinée.			
Pluie-Neige	1 100 m			
Iso 0 °C	1 500 m	1 900 m	2 300 m	2 500 m
Vent 2000 m	20 km/h	15 km/h	10 km/h	10 km/h
Vent 3000 m	30 km/h	25 km/h	20 km/h	20 km/h

Épaisseur de neige hors-piste

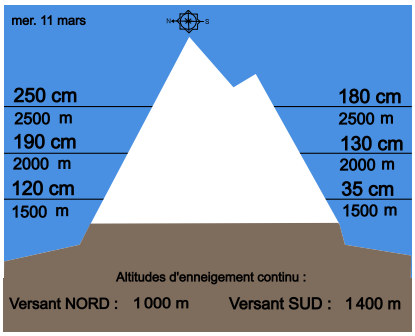

Précipitations à 1800 m

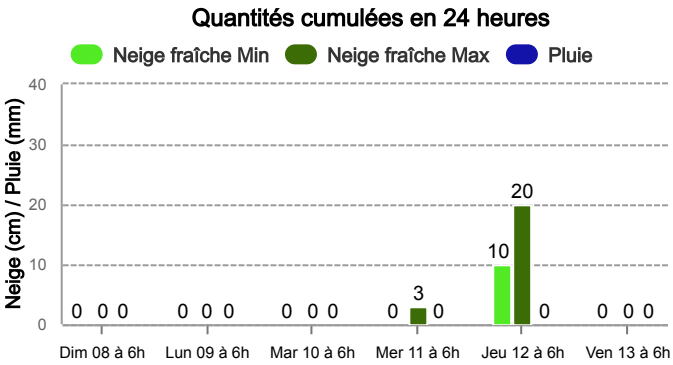

Tendance du vendredi 13 mars

2

Indice de risque limité

La neige fraîchement tombée se tasse rapidement. L'activité naturelle en versant ensoleillé est en forte baisse.

Pour consulter la vigilance en cours, veuillez vous rendre sur le site https://vigilance.meteofrance.fr/fr

Météo-France - 73 avenue de Paris, 94165 Saint-Mandé cedex - Contact : contact@meteo.fr

Rédigé par Météo-France avec la contribution des observateurs du réseau nivo-météorologiques. Partenariat : ANMSM (Maires de Stations de Montagne), DSF (Domaines Skiables de France), ADSP (Directeurs de Pistes et de la Sécurité des Stations de Sports d'Hiver) et autres acteurs de la montagne.

Bulletin neige & avalanches par téléphone au
0 892 68 10 20 Service 0,35 € / min + prix appel

RÉPUBLIQUE FRANÇAISE
Liberté Égalité Fraternité

METEO FRANCE
À VOS CÔTÉS, DANS UN CLIMAT QUI CHANGE

Bulletin d'estimation du risque d'avalanche
(valable en dehors des pistes balisées et ouvertes)

MASSIF : Beaufortain

Rédigé le mercredi 11 mars 2026 à 16h

Conditions nivo-météo des 7 derniers jours

	jeu. 05/03				ven. 06/03				sam. 07/03				dim. 08/03				lun. 09/03				mar. 10/03				mer. 11/03			
	03h	09h	15h	21h	03h	09h	15h	21h	03h	09h	15h	21h	03h	09h	15h	21h	03h	09h	15h	21h	03h	09h	15h	21h	03h	09h	15h	21h
Météo																												
Vent (km/h)	20	25	30	30	30	30	25	20	20	25	25	15	20	20	20	20	20	20	30	30	25	25	20	25	25	25	30	45
à 3000m																												
Vent (km/h)	15	20	25	30	30	30	20	10	10	15	15	10	10	5	10	10	10	20	30	20	15	15	10	15	15	15	20	35
à 2000m																												

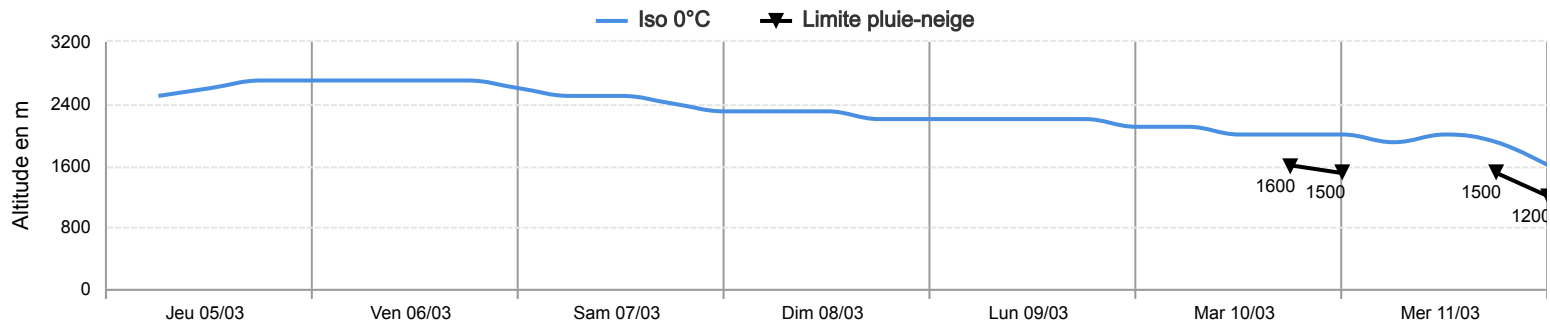

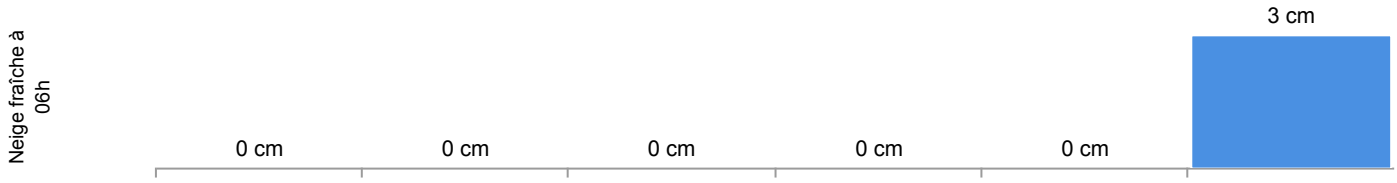

Risque d'avalanche	jeu. 05/03	ven. 06/03	sam. 07/03	dim. 08/03	lun. 09/03	mar. 10/03	mer. 11/03
	2	2	2	2	2	1	1

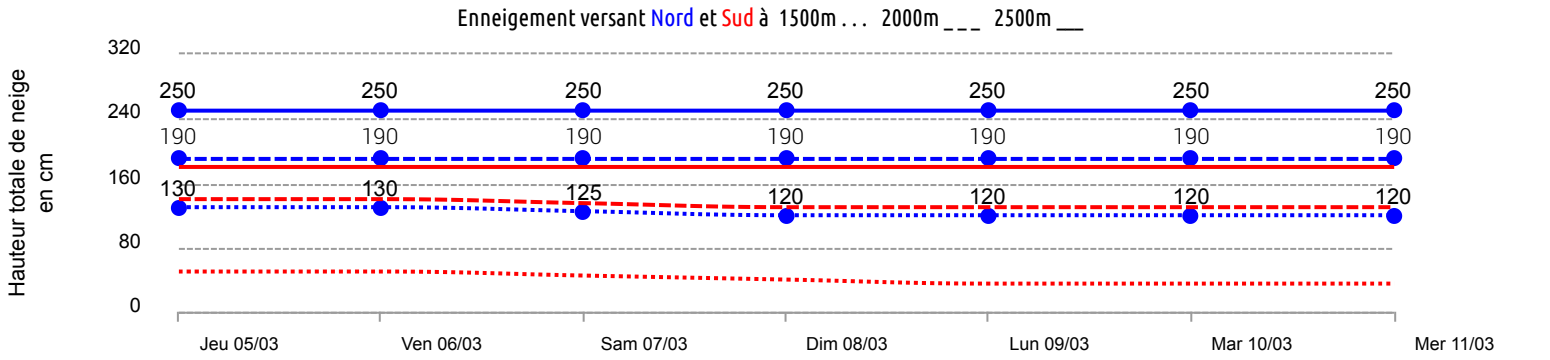

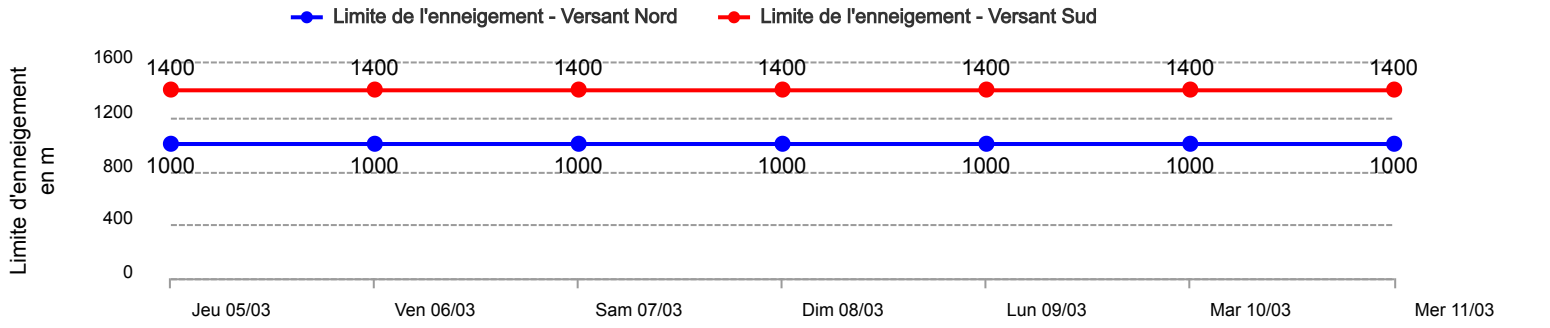

Pour consulter la vigilance en cours, veuillez vous rendre sur le site https://vigilance.meteofrance.fr/fr

Météo-France - 73 avenue de Paris, 94165 Saint-Mandé cedex - Contact : contact@meteo.fr

Rédigé par Météo-France avec la contribution des observateurs du réseau nivo-météorologiques. Partenariat : ANMSM (Maires de Stations de Montagne), DSF (Domaines Skiables de France), ADSP (Directeurs de Pistes et de la Sécurité des Stations de Sports d'Hiver) et autres acteurs de la montagne.

Bulletin neige & avalanches par téléphone au
0 892 68 10 20 Service 0,35 € / min + prix appel