Bulletin d'estimation du risque d'avalanche
(valable en dehors des pistes balisées et ouvertes)

MASSIF : Capcir Puymorens

Rédigé le mercredi 11 mars 2026 à 16h

Estimation des risques pour le : JEUDI 12 MARS

NOUVELLES PLAQUES EN FORMATION À PARTIR DE MERCREDI SOIR EN ALTITUDE; REPRISE DE L'HUMIDIFICATION JEUDI EN JOURNÉE

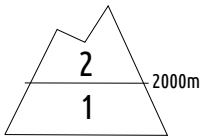

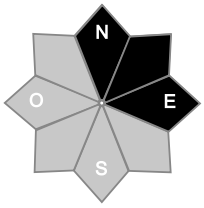

Plaques en formation

Au-dessus de 2000m indice de risque limité, plus bas indice faible.

Départs spontanés : Avalanches de neige humide, emportant parfois toute l'épaisseur du manteau neigeux

Déclenchements provoqués : Nouvelles structures de plaques en formation en altitude

Indices de risque : 5 très fort - 4 fort - 3 marqué - 2 limité - 1 faible -- En noir : les pentes les plus dangereuses

Stabilité du manteau neigeux

Situation avalancheuse typique : neige ventée neige humide

Déclenchements provoqués :
Nouvelles avalanches de plaques facilement déclenchables par un skieur, dans les versants Nord à Est encore froids au-dessus de 2000/2200 m. Sous l'action du vent de Nord-Ouest qui se renforce dès mercredi soir, de nouvelles structures de plaques, plutôt dures et proches des crêtes, sont attendues sous le vent de Nord-Ouest. Les volumes de neige transportables en altitude sont encore conséquents avec l'épisode de la fin de la semaine dernière et pourraient donc mener à des avalanches de taille moyenne.
Observables : fissures devant les skis, neige de surface changeante et travaillée par le vent, transport de neige par le vent.

Départs spontanés :
Rares avalanches de neige humide avec cassure linéaire, souvent de fond sur les pentes raides favorables (pentes herbeuses ou dalles rocheuses) possibles en toutes orientations, et jusqu'à 2400/2500 m sur les versants ensoleillés. Cassures généralement plus épaisses au-dessus de 2000/2200 m avec des fissures ou gueules de baleines, précurseurs de telles avalanches, observables dans les pentes concernées. Ces avalanches sont de taille moyenne, rarement grande en partant d'une zone d'accumulation.
Des départs ponctuels en neige humide sont également à attendre au fil de la journée dans les pentes raides des secteurs ensoleillés.

Autre: Des chutes de corniches, parfois larges et épaisses, sont encore possibles et peuvent être à l'origine de départs d'avalanches.

Qualité de la neige

Enneigement :
L'enneigement est nettement excédentaire dès la moyenne montagne grâce à la succession de nombreuses perturbations neigeuses depuis le début de l'année. Les vallons ombragés sont encore bien enneigés notamment en versant est et nord. Il est en général possible de chausser dès 1600/1900 m d'altitude. La limite skiable remonte de jour en jour dans les pentes ensoleillées.

Qualité de la neige :
Jeudi matin, on trouvera un saupoudrage de neige dès 1600m plutôt sur le Capcir puis une fine couche de quelques cm dès 2000m, hétérogène avec le vent en altitude. La neige devrait être bien regelé sous 1800 m. Plus haut, la fine couche de neige sera parfois collante si elle repose sur de la neige humide de la veille. En journée, reprise de l'humidification au soleil et dans la douceur. La neige sera lourde et humide en fin de journée sous 2100/2200m en de multiples orientations. On pourra par contre toujours trouver quelques secteurs poudreux dans les combes abritées et ombragées.

Aperçu météo pour le jeudi 12 mars

	nuit	matin	après-midi	soir

Renforcement du vent ce soir et faibles chutes de neige d'ici jeudi matin sur le Capcir. Ciel de plus en plus dégagé jeudi en journée.

Pluie-Neige	1 600 m			
Iso 0 °C	1 900 m	2 300 m	2 500 m	2 600 m
Vent 2000 m	↘ 30 km/h	↘ 20 km/h	↘ 20 km/h	→ 15 km/h
Vent 3000 m	↘ 45 km/h	↘ 30 km/h	↘ 25 km/h	↘ 20 km/h

Épaisseur de neige hors-piste

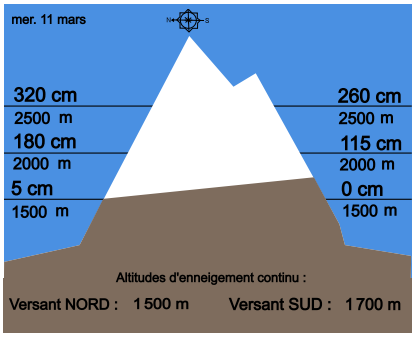

Précipitations à 1800 m

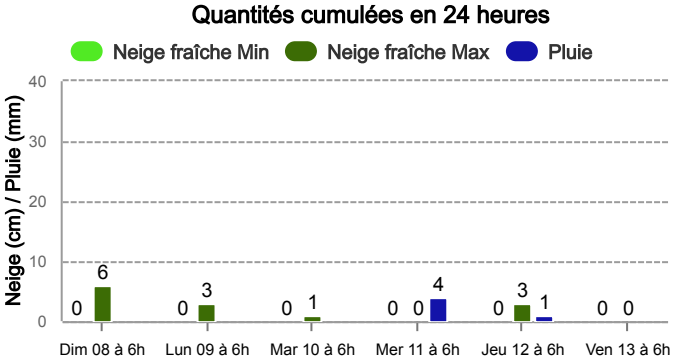

Tendance du vendredi 13 mars

Indice de risque limité

Maintien du risque avant l'arrivée d'une perturbation à partir de la nuit de vendredi à samedi.

Pour consulter la vigilance en cours, veuillez vous rendre sur le site https://vigilance.meteofrance.fr/fr

Météo-France - 73 avenue de Paris, 94165 Saint-Mandé cedex - Contact : contact@meteo.fr

Rédigé par Météo-France avec la contribution des observateurs du réseau nivo-météorologiques. Partenariat : ANMSM (Maires de Stations de Montagne), DSF (Domaines Skiables de France), ADSP (Directeurs de Pistes et de la Sécurité des Stations de Sports d'Hiver) et autres acteurs de la montagne.

Bulletin neige & avalanches par téléphone au
0 892 68 10 20 Service 0,35 € / min + prix appel

RÉPUBLIQUE FRANÇAISE
Liberté Égalité Fraternité

METEO FRANCE
À VOS CÔTÉS, DANS UN CLIMAT QUI CHANGE

Bulletin d'estimation du risque d'avalanche

(valable en dehors des pistes balisées et ouvertes)

MASSIF : Capcir Puymorens

Rédigé le mercredi 11 mars 2026 à 16h

Conditions nivo-météo des 7 derniers jours

	jeu. 05/03				ven. 06/03				sam. 07/03				dim. 08/03				lun. 09/03				mar. 10/03				mer. 11/03			
	03h	09h	15h	21h	03h	09h	15h	21h	03h	09h	15h	21h	03h	09h	15h	21h	03h	09h	15h	21h	03h	09h	15h	21h	03h	09h	15h	21h
Météo																												
Vent (km/h)	35	35	40	40	45	50	55	40	40	40	30	25	30	25	25	20	20	15	15	15	15	15	20	15	15	25	40	55
à 3000m																												
Vent (km/h)	20	25	30	25	25	35	35	30	25	30	20	15	20	20	15	10	10	10	10	5	5	5	10	10	10	10	25	35
à 2000m																												

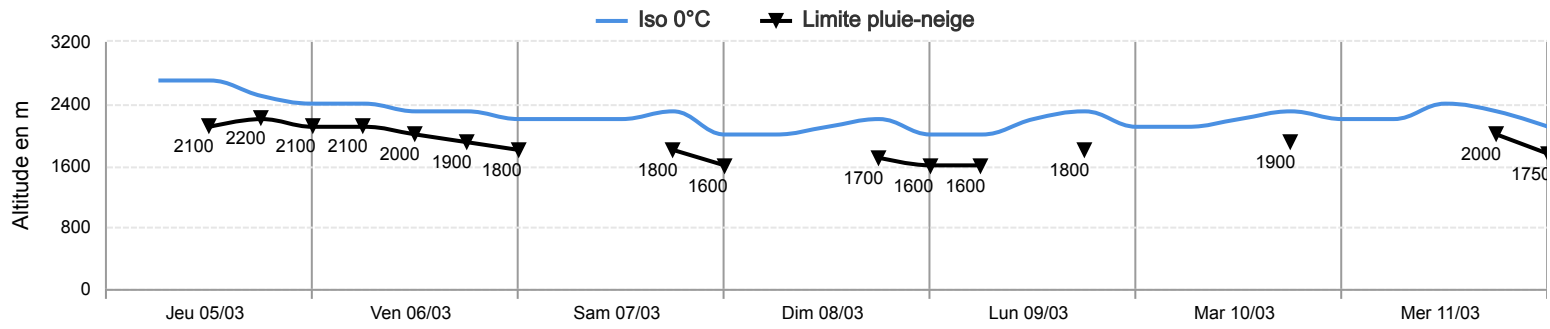

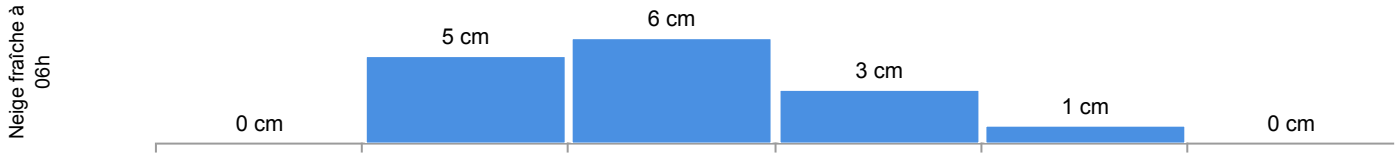

Risque d'avalanche	jeu. 05/03	ven. 06/03	sam. 07/03	dim. 08/03	lun. 09/03	mar. 10/03	mer. 11/03
	2	3	3	3	3	2	2

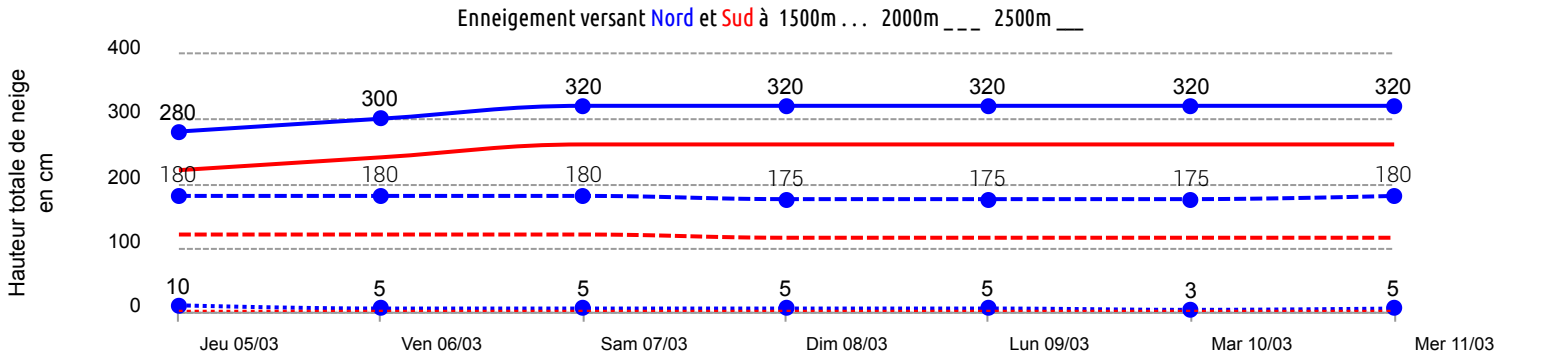

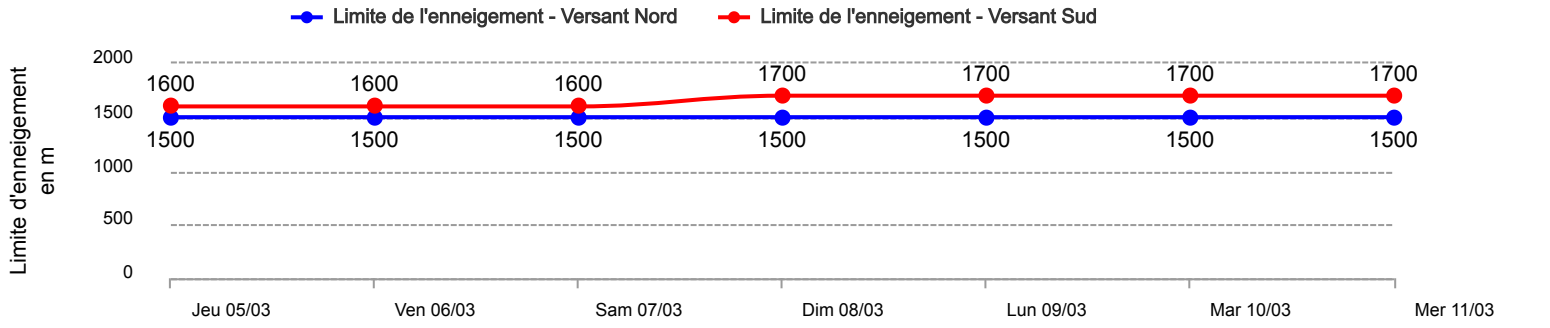

Pour consulter la vigilance en cours, veuillez vous rendre sur le site https://vigilance.meteofrance.fr/fr

Météo-France - 73 avenue de Paris, 94165 Saint-Mandé cedex - Contact : contact@meteo.fr

Rédigé par Météo-France avec la contribution des observateurs du réseau nivo-météorologiques. Partenariat : ANMSM (Maires de Stations de Montagne), DSF (Domaines Skiables de France), ADSP (Directeurs de Pistes et de la Sécurité des Stations de Sports d'Hiver) et autres acteurs de la montagne.

Bulletin neige & avalanches par téléphone au

0 892 68 10 20 Service 0,35 € / min + prix appel