Bulletin d'estimation du risque d'avalanche

(valable en dehors des pistes balisées et ouvertes)

MASSIF : Cerdagne Canigou

Rédigé le mercredi 11 mars 2026 à 16h

Estimation des risques pour le : JEUDI 12 MARS

NOUVELLES PLAQUES EN FORMATION À PARTIR DE MERCREDI SOIR EN ALTITUDE; HUMIDIFICATION QUI REPREND EN JOURNÉE AU SOLEIL

2

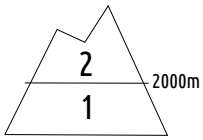

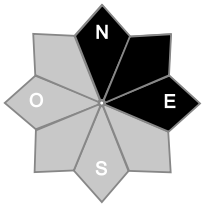

Plaques en formation

Au-dessus de 2000m indice de risque limité, plus bas indice faible.

Départs spontanés : Avanches de neige humide, rarement grandes

Déclenchements provoqués : Nouvelles structures de plaques en altitude

Indices de risque : 5 très fort - 4 fort - 3 marqué - 2 limité - 1 faible -- En noir : les pentes les plus dangereuses

Stabilité du manteau neigeux

Situation avalancheuse typique : neige ventée — neige humide

Déclenchements provoqués :

Nouvelles avalanches de plaques facilement déclenchables par un skieur, dans les versants Nord à Est encore froids au-dessus de 2000/2200 m. Sous l'action du vent de Nord-Ouest qui se renforce dès mercredi soir, de nouvelles structures de plaques, plutôt dures et proches des crêtes, sont attendues sous le vent de Nord-Ouest. Les volumes de neige transportables en altitude sont encore conséquents avec l'épisode de la fin de la semaine dernière et pourraient mener à des avalanches de taille moyenne.

Observables : fissures devant les skis, neige de surface changeante et travaillée par le vent, transport de neige par le vent.

Départs spontanés :

Des coulées en neige humide avec départs ponctuels sont à attendre au fil de la journée dans les pentes raides des secteurs ensoleillés avec la douceur générale. De plus, avec les quantités importantes de neige récente, des avalanches de neige humide avec cassure linéaire, parfois jusqu'au sol, de taille moyenne voire grande sont à attendre jusqu'à 2400/2500m dans les secteurs ensoleillés. L'ouverture de fissures est un signe précurseur d'avalanche pouvant partir jusqu'au sol (avalanche de fond), à surveiller y compris dans les secteurs pas ou peu ensoleillés.

Autre: Des chutes de corniches, parfois larges et épaisses, ont encore été reportées récemment et peuvent être à l'origine de départs d'avalanches.

Qualité de la neige

Enneigement :

L'enneigement est excédentaire dès la moyenne montagne grâce à la succession de nombreuses perturbations neigeuses depuis le début de l'année. Il est en général possible de chausser dès 1600/1800m d'altitude. La limite skiable remonte au fil des jours dans les pentes ensoleillées. Le manteau neigeux atteint rapidement 1m d'épaisseur et dépasse encore les 2m au-dessus de 2200m.

Qualité de la neige :

Jeudi matin, on trouvera un manteau neigeux plus ou moins bien regelé sous 2000/2100 m avec les nuages. Plus haut, on trouvera toujours une couche de neige récente importante, notamment dans les secteurs à l'abri du vent d'est à sud-est, pouvant encore être poudreuse dans les combes ombragées, mais aussi travaillée par le vent de la nuit prochaine proche des crêtes et sommets. En journée, la neige est à nouveau humidifiée au soleil, avec une humidification en profondeur sous 2000/2200 m et de la neige collante et lourde.

Aperçu météo pour le jeudi 12 mars

nuit	matin	après-midi	soir

Renforcement du vent ce soir et jusqu'à demain matin. En journée, ciel nuageux mais devenant de plus en plus dégagé. Douceur généralisée.

Pluie-Neige				
Iso 0 °C	2 200 m	2 600 m	2 700 m	2 700 m
Vent 2000 m	25 km/h	20 km/h	15 km/h	10 km/h
Vent 3000 m	45 km/h	35 km/h	25 km/h	20 km/h

Épaisseur de neige hors-piste

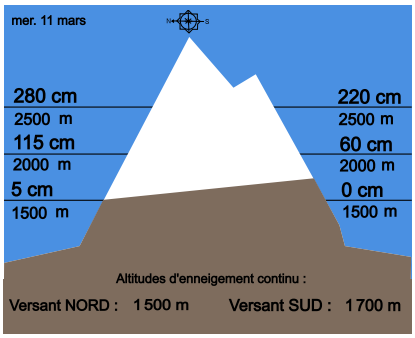

Précipitations à 1800 m

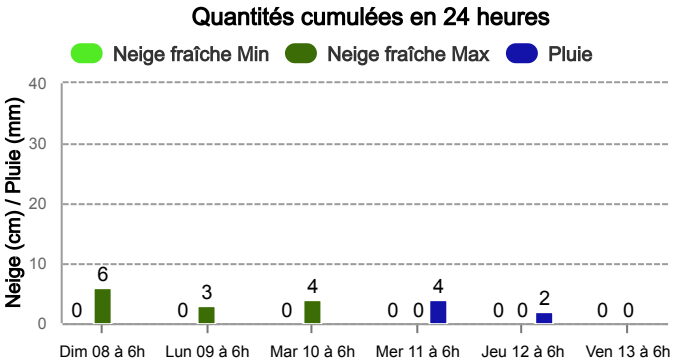

Tendance du vendredi 13 mars

2

Indice de risque limité

Maintien du risque avant l'arrivée d'une perturbation à partir de la nuit de vendredi à samedi.

Pour consulter la vigilance en cours, veuillez vous rendre sur le site https://vigilance.meteofrance.fr/fr

Météo-France - 73 avenue de Paris, 94165 Saint-Mandé cedex - Contact : contact@meteo.fr

Rédigé par Météo-France avec la contribution des observateurs du réseau nivo-météorologiques. Partenariat : ANMSM (Maires de Stations de Montagne), DSF (Domaines Skiables de France), ADSP (Directeurs de Pistes et de la Sécurité des Stations de Sports d'Hiver) et autres acteurs de la montagne.

Bulletin neige & avalanches par téléphone au 0 892 68 10 20 Service 0,35 € / min + prix appel

RÉPUBLIQUE FRANÇAISE
Liberté Égalité Fraternité

METEO FRANCE
À VOS CÔTÉS, DANS UN CLIMAT QUI CHANGE

Bulletin d'estimation du risque d'avalanche

(valable en dehors des pistes balisées et ouvertes)

MASSIF : Cerdagne Canigou

Rédigé le mercredi 11 mars 2026 à 16h

Conditions nivo-météo des 7 derniers jours

	jeu. 05/03				ven. 06/03				sam. 07/03				dim. 08/03				lun. 09/03				mar. 10/03				mer. 11/03			
	03h	09h	15h	21h	03h	09h	15h	21h	03h	09h	15h	21h	03h	09h	15h	21h	03h	09h	15h	21h	03h	09h	15h	21h	03h	09h	15h	21h
Météo																												
Vent (km/h)	45	50	50	50	45	50	55	40	40	40	30	25	30	25	25	20	20	15	15	10	15	15	15	15	20	25	35	45
à 3000m	↑	←	←	↖	↖	←	←	↖	↑	↑	↑	↑	↑	↑	↑	↑	↑	↑	↑	↑	↗	↑	→	→	↑	→	→	↘
Vent (km/h)	30	30	30	30	25	35	35	30	25	30	20	15	20	20	15	10	10	10	10	5	10	10	10	5	10	10	15	20
à 2000m	↖	↖	←	←	←	←	←	↖	↖	↖	↑	↑	↑	↑	↑	↑	↑	↑	↑	↑	↑	←	↖	←	↗	↗	↘	↘

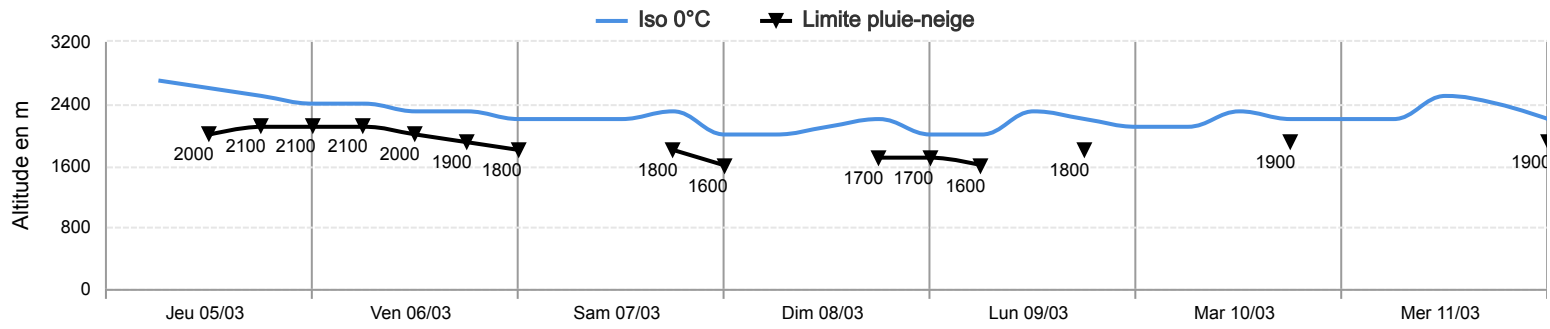

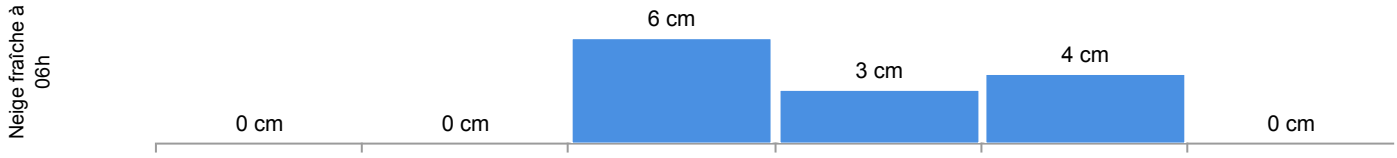

Risque d'avalanche	jeu. 05/03	ven. 06/03	sam. 07/03	dim. 08/03	lun. 09/03	mar. 10/03	mer. 11/03
	3	3	3	3	3	2	2

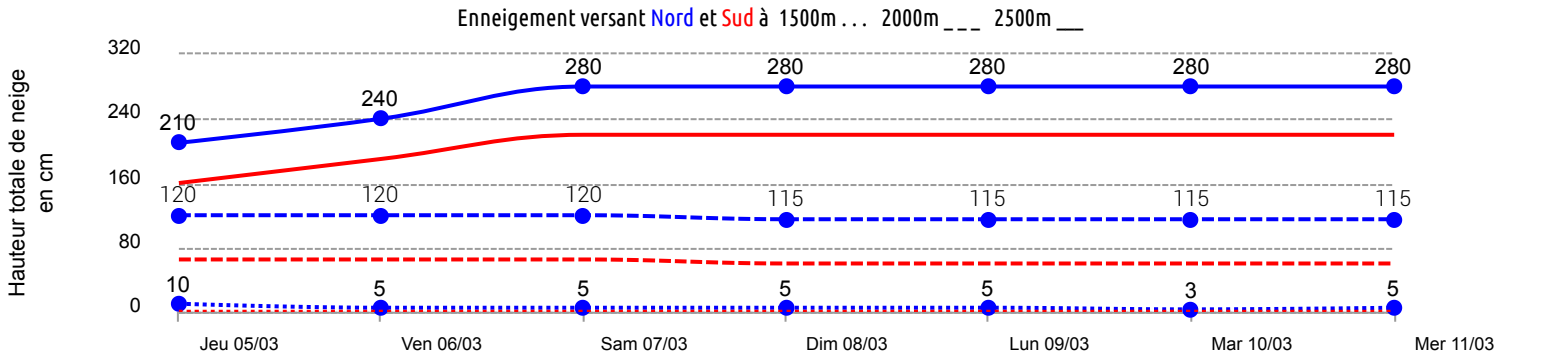

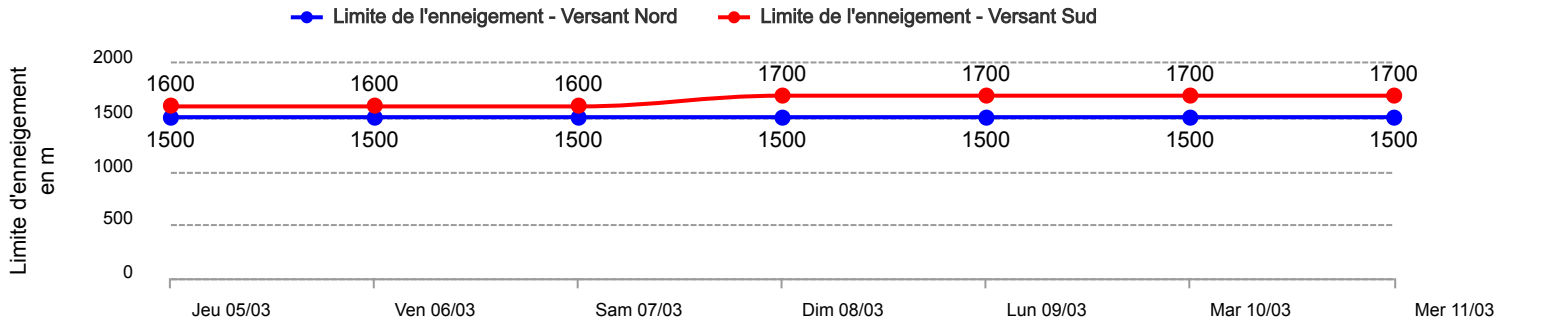

Pour consulter la vigilance en cours, veuillez vous rendre sur le site https://vigilance.meteofrance.fr/fr

Météo-France - 73 avenue de Paris, 94165 Saint-Mandé cedex - Contact : contact@meteo.fr

Rédigé par Météo-France avec la contribution des observateurs du réseau nivo-météorologiques. Partenariat : ANMSM (Maires de Stations de Montagne), DSF (Domaines Skiables de France), ADSP (Directeurs de Pistes et de la Sécurité des Stations de Sports d'Hiver) et autres acteurs de la montagne.

Bulletin neige & avalanches par téléphone au
0 892 68 10 20 Service 0,35 € / min + prix appel