Bulletin d'estimation du risque d'avalanche
(valable en dehors des pistes balisées et ouvertes)
MASSIF : Chablais

Rédigé le mercredi 11 mars 2026 à 16h

Estimation des risques pour le : JEUDI 12 MARS

NOUVELLES INSTABILITÉS DANS LA NEIGE FRAICHE

2

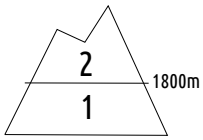

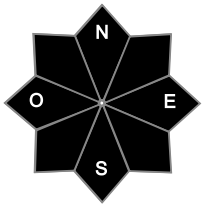

Au-dessus de 1800m indice de risque limité, plus bas indice faible.

Départs spontanés : Avalanches de neige humide en versants ensoleillés, rares plaques de fond

Déclenchements provoqués : Plaques friables dans la neige fraiche

Indices de risque : 5 très fort - 4 fort - 3 marqué - 2 limité - 1 faible -- En noir : les pentes les plus dangereuses

Stabilité du manteau neigeux

Situation avalancheuse typique : neige fraîche — neige humide

Déclenchements provoqués :
* Quelques plaques friables dans la neige fraiche, en tous versants au-dessus de 1800 m, facilement déclenchables par un skieur. Taille 1 (petite) à 2 (moyenne). Dans les versants ombragés, au-dessus de 2400 m, ces plaques friables sont plus réactives.
Facteur aggravant : au-dessus de 2200 m, présence d'une sous-couche fragile persistante enfouie. Difficile à déclencher. Une première avalanche dans la neige récente peut dans de rares cas déclencher en cascade cette couche fragile. Taille 2 (moyenne) avec d'épaisses cassures.

Départs spontanés :
* Quelques avalanches de neige fraiche pendant les chutes, en tous versants. Taille 1 (petite).
* Départs ponctuels de neige humide dans les versants sud-est à ouest, suivant la course du soleil. Taille 1 (petite).
* Rares plaques de fond, de jour comme de nuit, dans les pentes lisses et raides (zones herbeuses, dalles rocheuses). Présentes dans les versants sud sous 2300 m et dans les versants nord sous 2000 m. Taille 2 (moyenne).

Qualité de la neige

Enneigement :
Pour la saison, l'enneigement est correct.
On peut chausser les skis vers 1200/1300 m en nord, est et ouest et 1400/1700 m en sud.
Grosses corniches encore présentes.

Qualité de la neige jeudi :
* En dessous de 1600 m : Manteau neigeux de type printanier recouvert d'une couche de neige fraiche humide dès 1300 m. 5-10 cm de nouvelle neige à 1500 m.
* Au-dessus de 1600 m :15-20 cm de neige fraiche reposant sur un fond dur. Cette neige est le plus souvent d'aspect poudreux, plus rarement travaillé par le vent proche des crêtes au-dessus de 2000 m.

Aperçu météo pour le jeudi 12 mars

	nuit	matin	après-midi	soir
	Chutes de neige dans la nuit. Nombreux nuages en début de journée, puis rapidement ensoleillé. -4/3°C à 2000 m.			
Pluie-Neige	1 200 m			
Iso 0 °C	1 400 m	1 500 m	2 000 m	2 300 m
Vent 2000 m	↘ 20 km/h	↙ 10 km/h	↙ 5 km/h	↗ 5 km/h
Vent 2500 m	↘ 30 km/h	↙ 20 km/h	↙ 5 km/h	↗ 10 km/h

Épaisseur de neige hors-piste

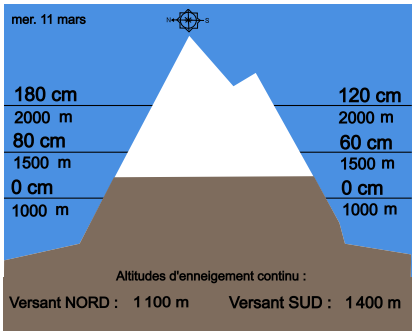

Précipitations à 1800 m

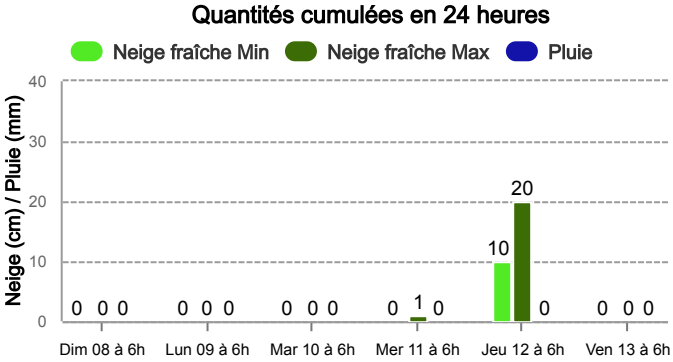

Tendance du vendredi 13 mars

2

Indice de risque limité

Risque stationnaire. Encore quelques instabilités dans la neige fraiche.

Pour consulter la vigilance en cours, veuillez vous rendre sur le site https://vigilance.meteofrance.fr/fr

Météo-France - 73 avenue de Paris, 94165 Saint-Mandé cedex - Contact : contact@meteo.fr

Rédigé par Météo-France avec la contribution des observateurs du réseau nivo-météorologiques. Partenariat : ANMSM (Maires de Stations de Montagne), DSF (Domaines Skiables de France), ADSP (Directeurs de Pistes et de la Sécurité des Stations de Sports d'Hiver) et autres acteurs de la montagne.

Bulletin neige & avalanches par téléphone au 0 892 68 10 20 Service 0,35 € / min + prix appel

Bulletin d'estimation du risque d'avalanche

(valable en dehors des pistes balisées et ouvertes)

MASSIF : Chablais

Rédigé le mercredi 11 mars 2026 à 16h

Conditions nivo-météo des 7 derniers jours

	jeu. 05/03				ven. 06/03				sam. 07/03				dim. 08/03				lun. 09/03				mar. 10/03				mer. 11/03			
	03h	09h	15h	21h	03h	09h	15h	21h	03h	09h	15h	21h	03h	09h	15h	21h	03h	09h	15h	21h	03h	09h	15h	21h	03h	09h	15h	21h
Météo																												
Vent (km/h)	10	25	25	15	10	25	20	15	10	20	5	20	10	10	10	15	10	10	10	15	15	30	40	40	40	50	60	45
à 2500m																												
Vent (km/h)	5	20	10	10	5	20	15	10	5	10	5	10	5	5	5	5	5	5	5	10	10	20	30	30	30	40	50	30
à 2000m																												

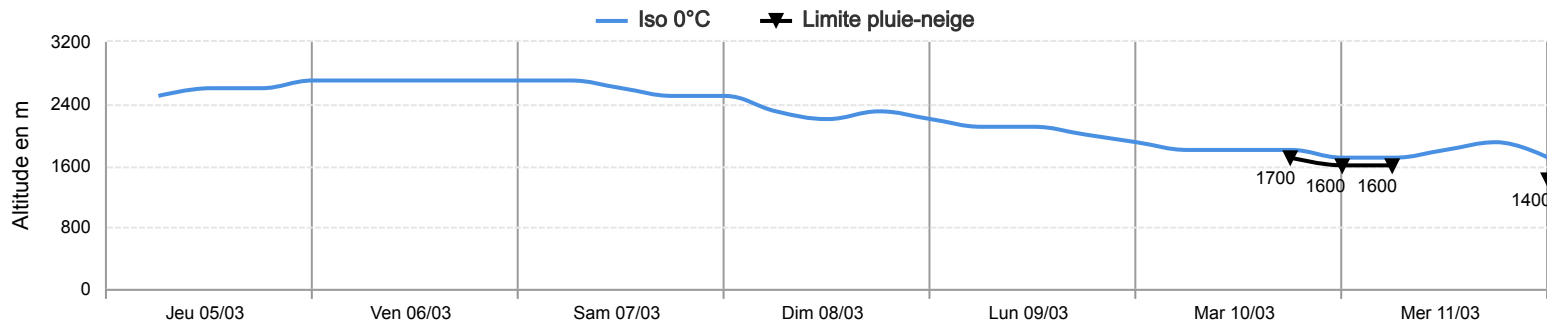

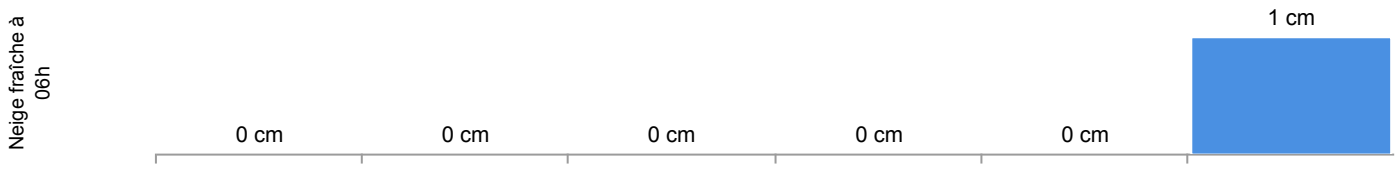

Risque d'avalanche	jeu. 05/03	ven. 06/03	sam. 07/03	dim. 08/03	lun. 09/03	mar. 10/03	mer. 11/03
	2	2	2	2	2	2	1

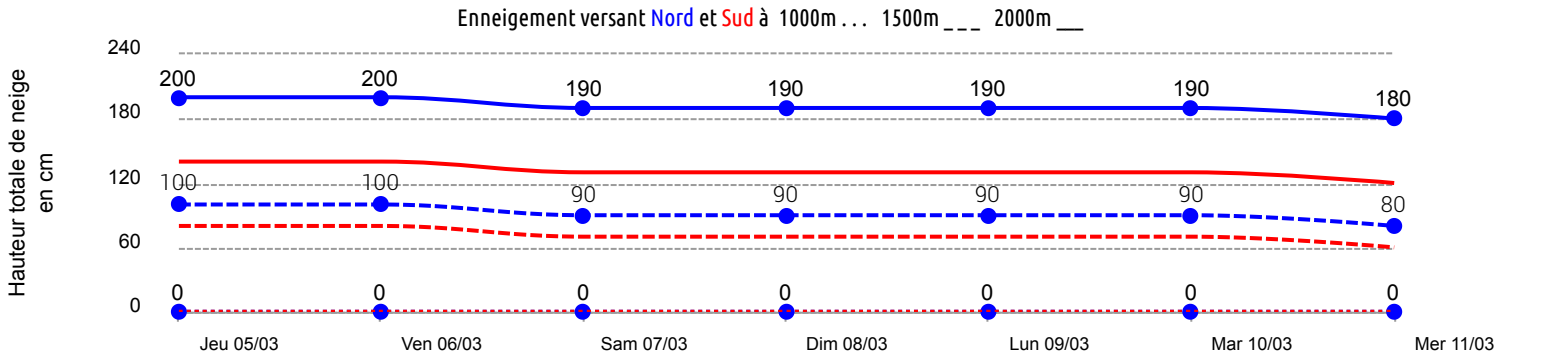

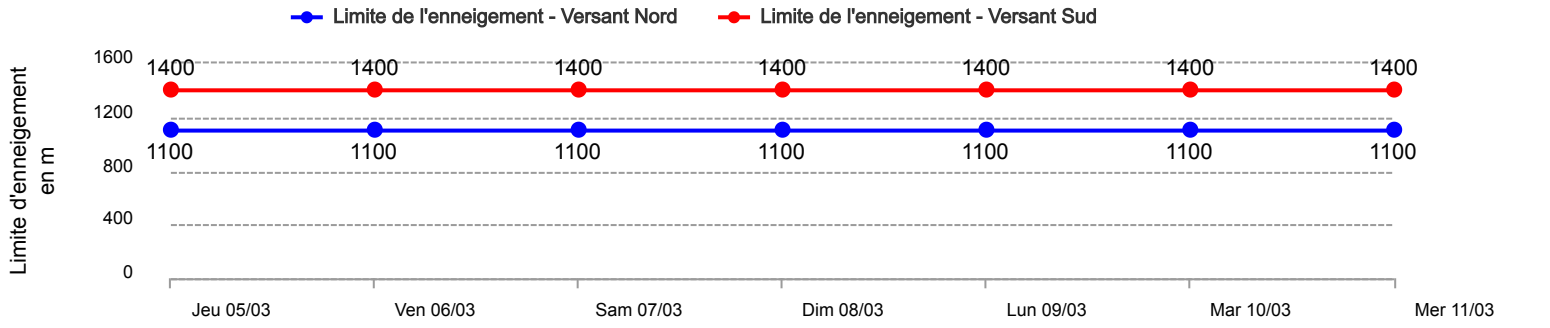

Pour consulter la vigilance en cours, veuillez vous rendre sur le site https://vigilance.meteofrance.fr/fr

Météo-France - 73 avenue de Paris, 94165 Saint-Mandé cedex - Contact : contact@meteo.fr

Rédigé par Météo-France avec la contribution des observateurs du réseau nivo-météorologiques. Partenariat : ANMSM (Maires de Stations de Montagne), DSF (Domaines Skiables de France), ADSP (Directeurs de Pistes et de la Sécurité des Stations de Sports d'Hiver) et autres acteurs de la montagne.

Bulletin neige & avalanches par téléphone au

0 892 68 10 20 Service 0,35 € / min + prix appel