Bulletin d'estimation du risque d'avalanche

(valable en dehors des pistes balisées et ouvertes)

MASSIF : Grandes-Rousses

Rédigé le mercredi 11 mars 2026 à 16h

Estimation des risques pour le : JEUDI 12 MARS

UN PEU DE FRAICHE (10 VOIRE 15 CM SUR OUEST DU MASSIF) LOCALEMENT SOUFFLEE VERS LES HAUTES CRETES ...

2

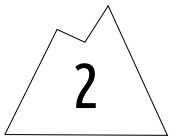

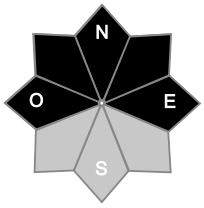

Crêtes d'altitude

Indices de risque : 5 très fort - 4 fort - 3 marqué - 2 limité - 1 faible -- En noir : les pentes les plus dangereuses

Indice de risque limité.

Départs spontanés : Coulées/boules (superficielles) de neige récente au soleil, rare avalanche de fond en pentes herbeuses/ secteurs de reptation...

Déclenchements provoqués : Minces plaques à l'abord des hautes crêtes et sommets (plus instables jeudi matin ?). En faces Nord d'altitude, des sous couches fragiles parfois..

Stabilité du manteau neigeux

Situation avalancheuse typique : neige fraîche avalanches de fond

Un peu de neige fraîche localement soufflée à l'abord des hautes crêtes et sommets, petites plaques temporairement instables au passage de skieur... Sinon sous couches denses, souvent stabilisée....

Déclenchements provoqués :

Petites plaques temporairement fragiles au passage de skieurs, surtout en matinée à l'abord des hautes crêtes. Plaques peu volumineuses mais parfois suffisantes pour déstabiliser un skieur.

Noter qu'en faces Nord des sous couches à moindre cohésion sont parfois observées, risque de rupture accidentelle plus large?

Indices observables : 10/15 cm attendus en altitude versant Vaujany, parfois soufflés (vent d'Ouest puis de Nord jeudi matin). En faces Nord, possibles fissures sous les skis ?

Vers Emparis moins de neige fraîche attendue...

L'après-midi, humidification locale attendue, tassement de cette neige récente...

Départs spontanés :

En matinée lors d'éclaircies, puis l'après-midi en tous versants : des coulées ponctuelles de surface/escargots de neige fraîche humidifiée.

Enfin dans une très rare pente herbeuse/secteur de reptation, une avalanche de fond, glissant au terrain reste possible (de taille moyenne/ rarement grande).

Qualité de la neige

Qualification de l'enneigement : L'enneigement est bon pour la saison au dessus de 1600/2000m. Il a récemment régressé en faces Sud, vers les crêtes.

Limites skiables : Vers 1200/1700m hors forêts, guère de sous couche plus bas.

Qualité de la neige jeudi : Petite couche de fraîche encore poudreuse en début de journée, à l'ombre. En journée humidification en pentes favorisées, au soleil, notamment sous 2500m environ... Sous couche en neige de printemps dure ou vieille poudreuse dense.

Aperçu météo pour le jeudi 12 mars

	nuit	matin	après-midi	soir
Neige durant la nuit de mercredi à jeudi (10/15 cm vers les sommets). Vent sensible jeudi matin puis faiblissant ; l'après-midi éclaircies/redoux.				
Pluie-Neige	1 400 m			
Iso 0 °C	1 700 m	1 700 m	2 200 m	2 400 m
Vent 2000 m	↙ 25 km/h	↙ 25 km/h	↙ 10 km/h	↑ 10 km/h
Vent 3000 m	↘ 40 km/h	↓ 50 km/h	↙ 20 km/h	↙ 10 km/h

Épaisseur de neige hors-piste

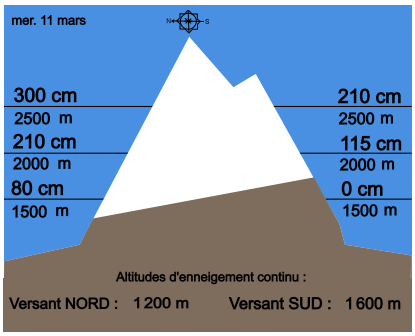

Précipitations à 1800 m

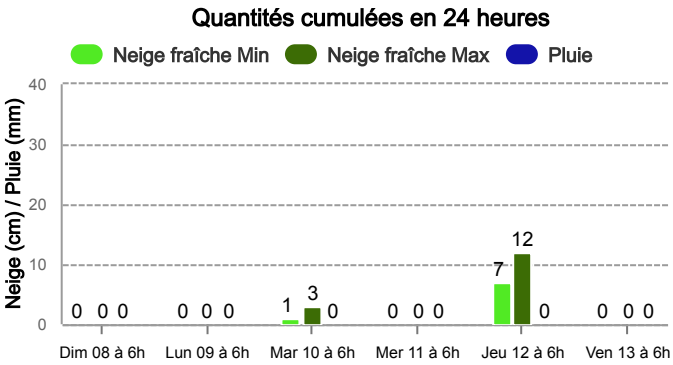

Tendance du vendredi 13 mars

2

Indice de risque limité

Risque d'avalanche en légère hausse vendredi après-midi ou soir : Vent de Sud-Sud-Ouest se renforçant, chassant parfois la neige...

Samedi perturbé/froid pas mal de neige fraîche attendue (30 cm), la situation nivologique évolue défavorablement...

Pour consulter la vigilance en cours, veuillez vous rendre sur le site https://vigilance.meteofrance.fr/fr

Météo-France - 73 avenue de Paris, 94165 Saint-Mandé cedex - Contact : contact@meteo.fr

Rédigé par Météo-France avec la contribution des observateurs du réseau nivo-météorologiques. Partenariat : ANMSM (Maires de Stations de Montagne), DSF (Domaines Skiables de France), ADSP (Directeurs de Pistes et de la Sécurité des Stations de Sports d'Hiver) et autres acteurs de la montagne.

Bulletin neige & avalanches par téléphone au

0 892 68 10 20 Service 0,35 € / min + prix appel

RÉPUBLIQUE FRANÇAISE
Liberté Égalité Fraternité

METEO FRANCE
À VOS CÔTÉS, DANS UN CLIMAT QUI CHANGE

Bulletin d'estimation du risque d'avalanche

(valable en dehors des pistes balisées et ouvertes)

MASSIF : Grandes-Rousses

Rédigé le mercredi 11 mars 2026 à 16h

Conditions nivo-météo des 7 derniers jours

	jeu. 05/03				ven. 06/03				sam. 07/03				dim. 08/03				lun. 09/03				mar. 10/03				mer. 11/03			
	03h	09h	15h	21h	03h	09h	15h	21h	03h	09h	15h	21h	03h	09h	15h	21h	03h	09h	15h	21h	03h	09h	15h	21h	03h	09h	15h	21h
Météo																												
Vent (km/h)	15	20	15	10	20	25	20	20	10	10	15	15	25	15	15	15	15	20	35	40	35	35	20	15	20	30	35	25
à 3000m																												
Vent (km/h)	10	10	5	20	25	25	15	15	10	5	5	5	15	10	10	10	10	15	25	30	25	25	15	10	10	10	25	15
à 2000m																												

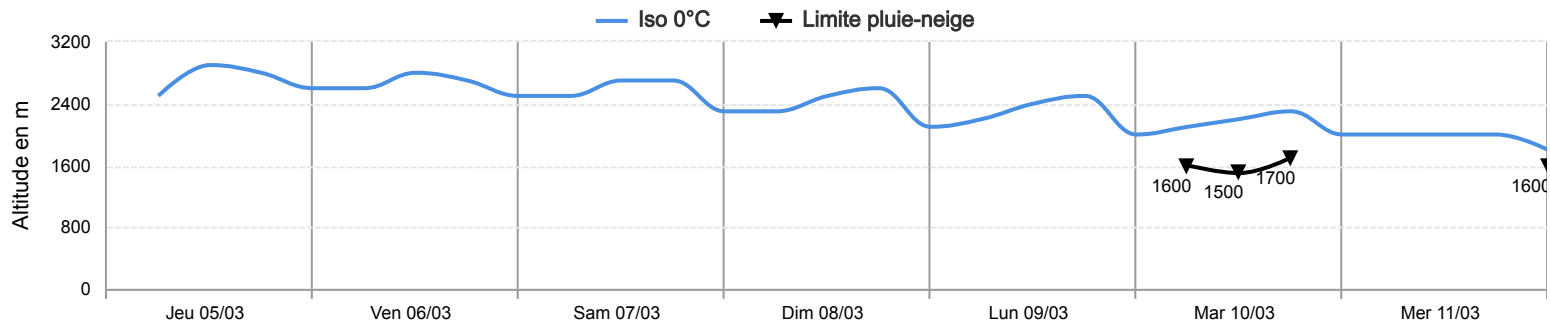

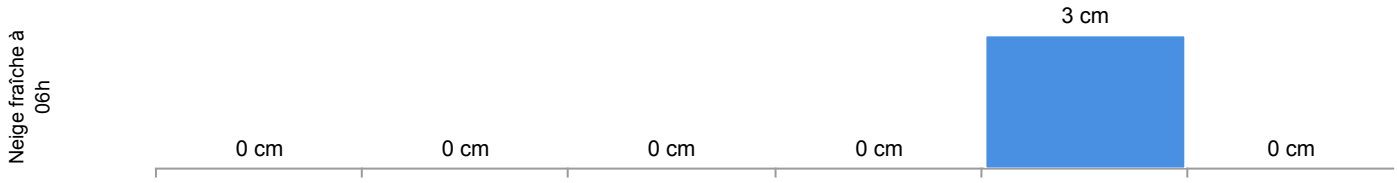

Risque d'avalanche	jeu. 05/03	ven. 06/03	sam. 07/03	dim. 08/03	lun. 09/03	mar. 10/03	mer. 11/03

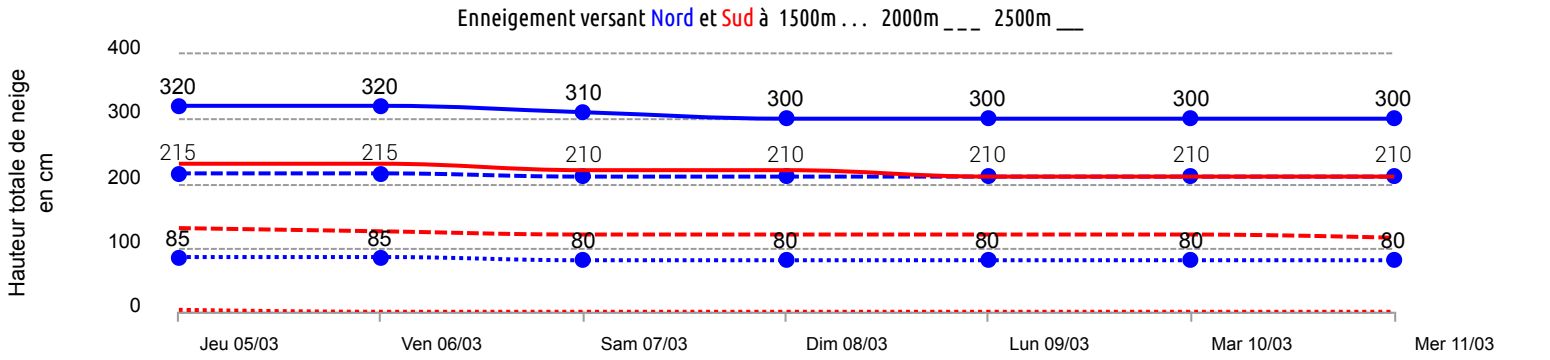

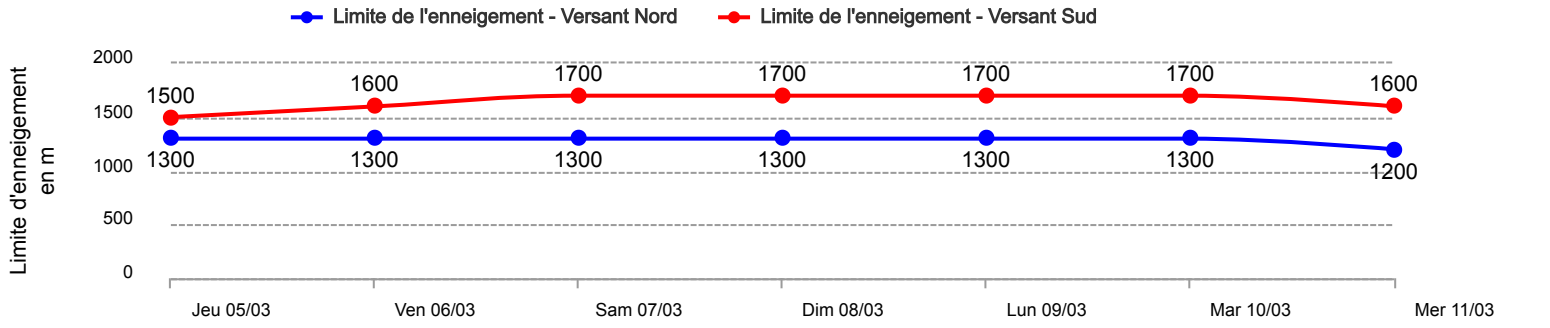

Pour consulter la vigilance en cours, veuillez vous rendre sur le site https://vigilance.meteofrance.fr/fr

Météo-France - 73 avenue de Paris, 94165 Saint-Mandé cedex - Contact : contact@meteo.fr

Bulletin neige & avalanches par téléphone au

0 892 68 10 20 Service 0,35 € / min + prix appel

Rédigé par Météo-France avec la contribution des observateurs du réseau nivo-météorologiques. Partenariat : ANMSM (Maires de Stations de Montagne), DSF (Domaines Skiables de France), ADSP (Directeurs de Pistes et de la Sécurité des Stations de Sports d'Hiver) et autres acteurs de la montagne.