Bulletin d'estimation du risque d'avalanche
(valable en dehors des pistes balisées et ouvertes)

MASSIF : Haut-Var Haut-Verdon

Rédigé le mercredi 11 mars 2026 à 16h

Estimation des risques pour le : JEUDI 12 MARS

QUELQUES PLAQUES DE NEIGE FRAÎCHE EN ALTITUDE, HUMIDIFICATION SUPERFICIELLE

2

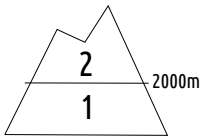

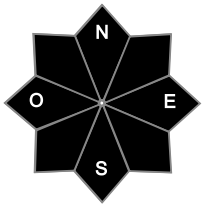

Au-dessus de 2000m indice de risque limité, plus bas indice faible.

Départs spontanés : quelques départs superficiels de neige humide au soleil.

Déclenchements provoqués : quelques instabilités superficielles en neige fraîche.

Indices de risque : 5 très fort - 4 fort - 3 marqué - 2 limité - 1 faible -- En noir : les pentes les plus dangereuses

Stabilité du manteau neigeux

Situation avalancheuse typique : neige ventée

Déclenchements provoqués :
- quelques plaques sont possibles dans la neige fraîche, présentes au dessus de 1800/2000 m, principalement côté Haut-Verdon. Elles sont le plus souvent d'aspect poudreux, parfois travaillées par le vent de nord, et peuvent être localement faciles à déclencher, mais restent de petite taille.

Départs spontanés :
- quelques départs ponctuels de petite taille dans le Haut-Verdon, en neige fraîche s'humidifiant en pentes raides au fil de la course du soleil.
- éventuellement une avalanche de glissement de taille moyenne est toujours possible, en pentes d'un large secteur sud, en terrain favorable (pentes herbeuses, dalles rocheuses).

Qualité de la neige

Enneigement plutôt excédentaire pour un début mars en général, notamment dans le Haut-Verdon.
Données observées : vers 2000 m, 170 cm en fond de vallon dans le Haut Verdon, 120 cm dans le Haut Var.

Enneigement skiable : vers 1400/1500 m en ubacs, 1800/1900 m en adrets peu pentus.

État de la neige en surface : jeudi matin, petite couche de neige récente en Haut-Verdon (entre 5 et 10 cm). Elle repose sur une neige encore froide en ubacs au dessus de 2200 m, croutée en dessous ainsi que dans les adrets. Reprise de l'humidification au soleil en cours de journée. Sur les crêtes, d'anciennes corniches épaisses côtoient des zones dégarnies.

Aperçu météo pour le jeudi 12 mars

nuit	matin	après-midi	soir

Quelques averses éparses en seconde partie de nuit, puis temps généralement sec et bien ensoleillé en journée.

Pluie-Neige	1 300 m			
Iso 0 °C	2 000 m	2 100 m	2 300 m	2 300 m
Vent 2000 m	25 km/h	25 km/h	20 km/h	10 km/h
Vent 3000 m	40 km/h	30 km/h	20 km/h	20 km/h

Épaisseur de neige hors-piste

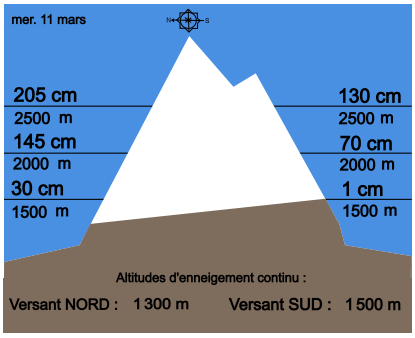

Précipitations à 1800 m

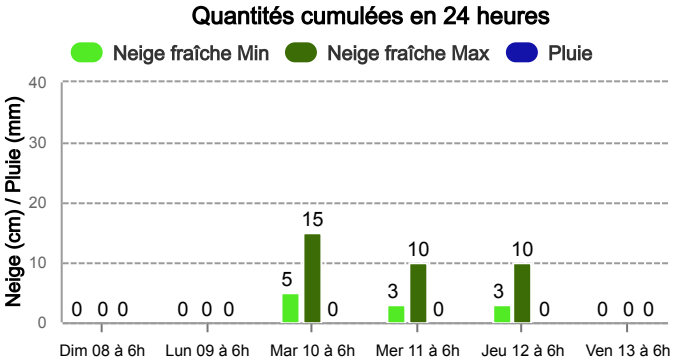

Tendance du vendredi 13 mars

2

Indice de risque limité

Maintient d'un risque limité, avec poursuite d'une humidification superficielle, et de rares plaques en altitude, avant une dégradation des conditions dans la nuit de vendredi à samedi.

Pour consulter la vigilance en cours, veuillez vous rendre sur le site https://vigilance.meteofrance.fr/fr

Météo-France - 73 avenue de Paris, 94165 Saint-Mandé cedex - Contact : contact@meteo.fr

Rédigé par Météo-France avec la contribution des observateurs du réseau nivo-météorologiques. Partenariat : ANMSM (Maires de Stations de Montagne), DSF (Domaines Skiables de France), ADSP (Directeurs de Pistes et de la Sécurité des Stations de Sports d'Hiver) et autres acteurs de la montagne.

Bulletin neige & avalanches par téléphone au 0 892 68 10 20 Service 0,35 € / min + prix appel

Bulletin d'estimation du risque d'avalanche

(valable en dehors des pistes balisées et ouvertes)

MASSIF : Haut-Var Haut-Verdon

Rédigé le mercredi 11 mars 2026 à 16h

Conditions nivo-météo des 7 derniers jours

	jeu. 05/03				ven. 06/03				sam. 07/03				dim. 08/03				lun. 09/03				mar. 10/03				mer. 11/03			
	03h	09h	15h	21h	03h	09h	15h	21h	03h	09h	15h	21h	03h	09h	15h	21h	03h	09h	15h	21h	03h	09h	15h	21h	03h	09h	15h	21h
Météo																												
Vent (km/h)	15	20	25	45	65	60	55	50	35	30	25	15	20	15	15	15	15	20	30	50	40	25	20	20	15	30	45	40
à 3000m																												
Vent (km/h)	20	20	25	40	45	40	40	35	25	20	15	10	15	10	15	10	15	15	20	35	5	15	20	5	5	10	20	15
à 2000m																												

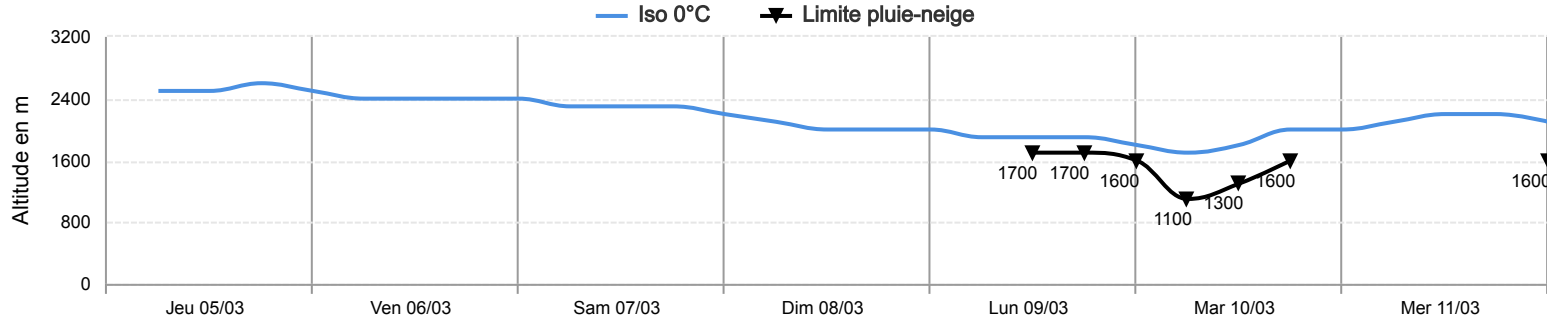

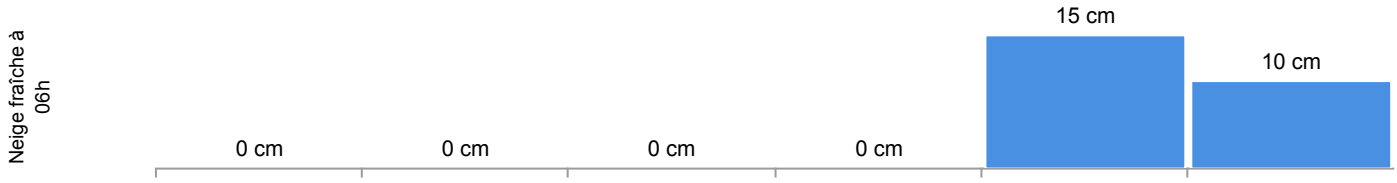

Risque d'avalanche	jeu. 05/03	ven. 06/03	sam. 07/03	dim. 08/03	lun. 09/03	mar. 10/03	mer. 11/03
	2	2	2	2	1	2	2

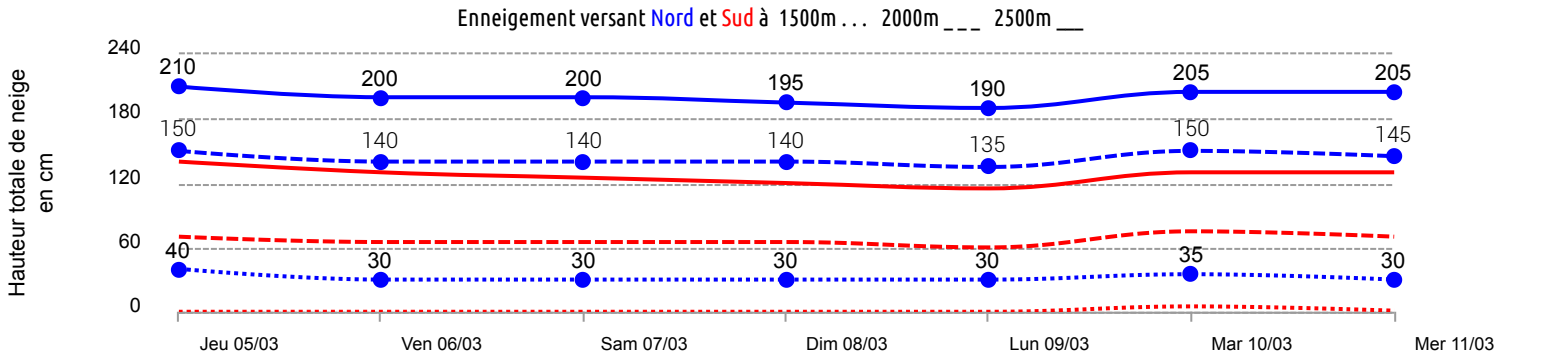

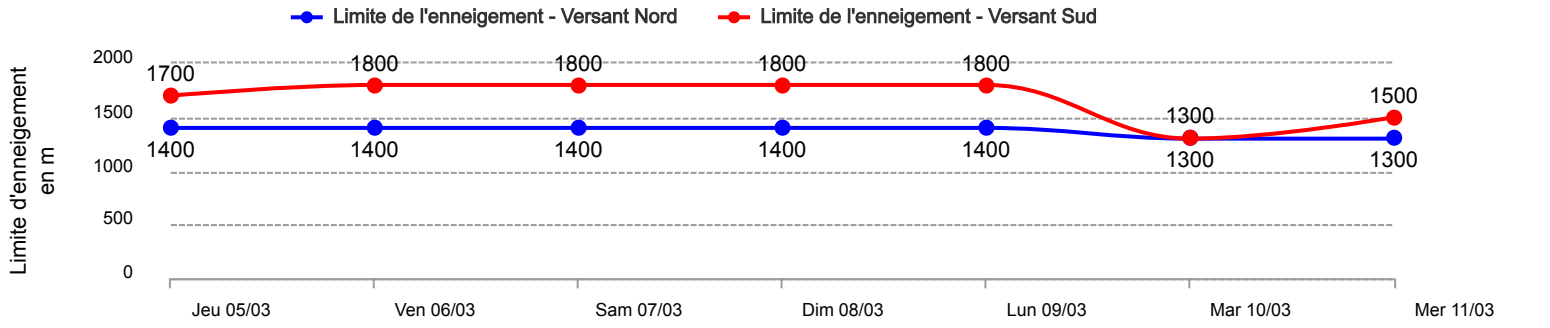

Pour consulter la vigilance en cours, veuillez vous rendre sur le site https://vigilance.meteofrance.fr/fr

Météo-France - 73 avenue de Paris, 94165 Saint-Mandé cedex - Contact : contact@meteo.fr

Bulletin neige & avalanches par téléphone au

0 892 68 10 20 Service 0,35 € / min + prix appel

Rédigé par Météo-France avec la contribution des observateurs du réseau nivo-météorologiques. Partenariat : ANMSM (Maires de Stations de Montagne), DSF (Domaines Skiables de France), ADSP (Directeurs de Pistes et de la Sécurité des Stations de Sports d'Hiver) et autres acteurs de la montagne.