Bulletin d'estimation du risque d'avalanche

(valable en dehors des pistes balisées et ouvertes)

MASSIF : Haute-Ariege

Rédigé le mercredi 11 mars 2026 à 16h

Estimation des risques pour le : JEUDI 12 MARS

NOUVELLES PLAQUES EN FORMATION EN ALTITUDE SOUS LE VENT DE SECTEUR NORD-OUEST; HUMIDIFICATION DANS LES VERSANTS ENSOLEILLÉS EN JOURNÉE

2

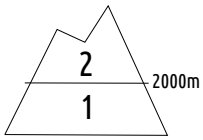

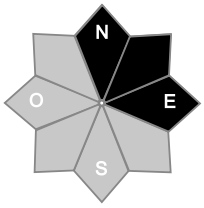

Plaques en altitude

Au-dessus de 2000m indice de risque limité, plus bas indice faible.

Départs spontanés : Avalanches de neige humide, emportant parfois tout le manteau neigeux

Déclenchements provoqués : Quelques nouvelles structures de plaques en altitude sous l'action du vent de nord-ouest

Indices de risque : 5 très fort - 4 fort - 3 marqué - 2 limité - 1 faible -- En noir : les pentes les plus dangereuses

Stabilité du manteau neigeux

Situation avalancheuse typique : neige ventée neige humide

Déclenchements provoqués :

Nouvelles avalanches de plaques peu épaisses, mais facilement déclenchables, dans les versants Nord à Est encore froids au-dessus de 2000/2200 m. De nouvelles structures de plaques, plutôt proches des crêtes, sont attendues sous le vent de Nord-Ouest qui souffle à partir de mercredi soir. Ces déclenchements sont généralement de taille petite à moyenne.

Observables : fissures devant les skis, neige de surface changeante et travaillée par le vent, transport de neige par le vent.

Départs spontanés :

Activité qui reprend au fil de la journée avec le soleil et la douceur donnant de rares avalanches de neige humide avec cassure linéaire, souvent de fond sur les pentes raides favorables (pentes herbeuses ou dalles rocheuses) possibles en toutes orientations, et jusqu'à 2400/2500m sur les versants ensoleillés. Avalanches de taille moyenne, rarement grande au-dessus de 2000m avec actuellement de nombreuses fissures ou gueules de baleines, signes précurseurs de telles avalanches, observables dans les pentes concernées.

Des coulées en neige humide avec départs ponctuels sont également à attendre au fil de la journée dans les pentes raides des secteurs ensoleillés.

Autre : Des ruptures de corniches parfois larges et épaisses sont toujours possibles à proximité des crêtes.

Qualité de la neige

Enneigement :

L'enneigement est encore excédentaire dès la moyenne montagne grâce aux perturbations neigeuses depuis le début de l'année. On peut souvent chausser les skis entre 1500 et 1800m en fonction des endroits en versants sud alors que certaines vallées ombragées sont enneigées dès 1400m. On trouve ensuite des quantités de neige plus conséquentes à partir de 2000 m en toutes orientations.

Qualité de la neige :

Jeudi matin, on trouvera un saupoudrage de neige dès 1400/1500m puis une couche de quelques cm à partir de 2000m, hétérogène avec le vent en altitude. La neige devrait être bien regelé sous 1800 m. Plus haut, la fine couche de neige récente sera parfois collante si elle repose sur de la neige encore humide de la veille. En journée, la neige s'humidifie au soleil et avec les températures douces. La neige sera donc lourde et humide en fin de journée sous 2100/2200m en de multiples orientations. On pourra par contre toujours trouver quelques secteurs poudreux dans les combes abritées et ombragées d'altitude.

Aperçu météo pour le jeudi 12 mars

	nuit	matin	après-midi	soir

Renforcement du vent à partir de ce soir avec un peu de neige d'ici jeudi matin puis le ciel se dégage de plus en plus en journée dans la douceur.

Pluie-Neige	1 500 m			
Iso 0 °C	1 800 m	2 400 m	2 500 m	2 500 m
Vent 2000 m	↘ 25 km/h	↘ 15 km/h	↘ 15 km/h	→ 10 km/h
Vent 3000 m	↘ 40 km/h	↘ 25 km/h	↘ 25 km/h	↘ 20 km/h

Épaisseur de neige hors-piste

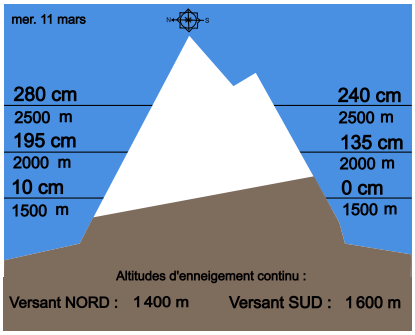

Précipitations à 1800 m

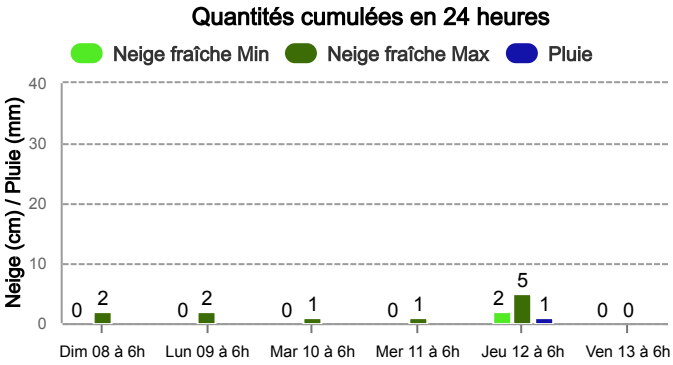

Tendance du vendredi 13 mars

2 **Indice de risque limité**

Évolution à venir à partir de vendredi soir avec une perturbation neigeuse

Pour consulter la vigilance en cours, veuillez vous rendre sur le site https://vigilance.meteofrance.fr/fr

Météo-France - 73 avenue de Paris, 94165 Saint-Mandé cedex - Contact : contact@meteo.fr

Rédigé par Météo-France avec la contribution des observateurs du réseau nivo-météorologiques. Partenariat : ANMSM (Maires de Stations de Montagne), DSF (Domaines Skiables de France), ADSP (Directeurs de Pistes et de la Sécurité des Stations de Sports d'Hiver) et autres acteurs de la montagne.

Bulletin neige & avalanches par téléphone au **0 892 68 10 20** Service 0,35 € / min + prix appel

RÉPUBLIQUE FRANÇAISE
Liberté Égalité Fraternité

METEO FRANCE
À VOS CÔTÉS, DANS UN CLIMAT QUI CHANGE

Bulletin d'estimation du risque d'avalanche
(valable en dehors des pistes balisées et ouvertes)
MASSIF : Haute-Ariege

Rédigé le mercredi 11 mars 2026 à 16h

Conditions nivo-météo des 7 derniers jours

	jeu. 05/03				ven. 06/03				sam. 07/03				dim. 08/03				lun. 09/03				mar. 10/03				mer. 11/03			
	03h	09h	15h	21h	03h	09h	15h	21h	03h	09h	15h	21h	03h	09h	15h	21h	03h	09h	15h	21h	03h	09h	15h	21h	03h	09h	15h	21h
Météo																												
Vent (km/h)	40	35	30	30	40	25	25	25	40	40	30	25	30	25	25	20	20	15	15	10	15	10	10	15	15	20	35	45
à 3000m																												
Vent (km/h)	35	30	20	20	25	15	20	20	25	30	20	15	20	20	15	10	10	10	10	5	5	5	5	10	10	10	15	30
à 2000m																												

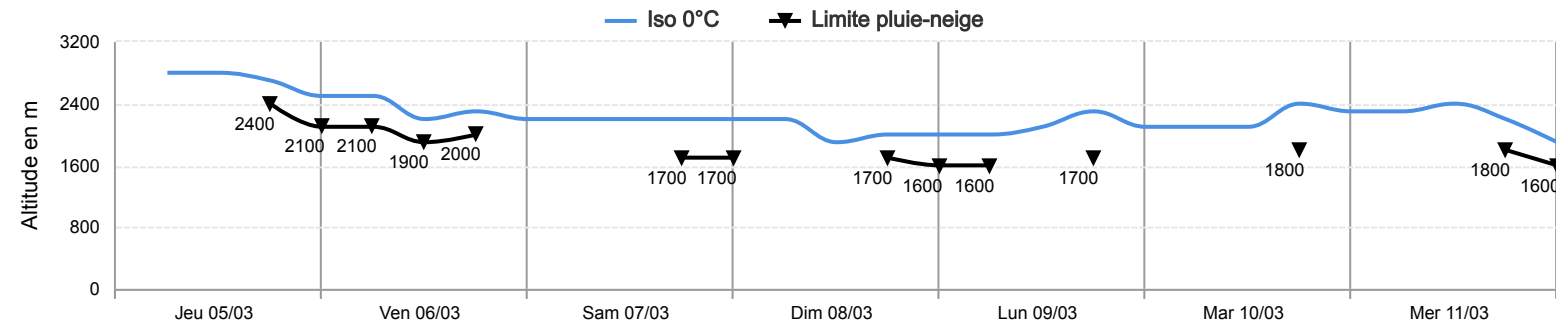

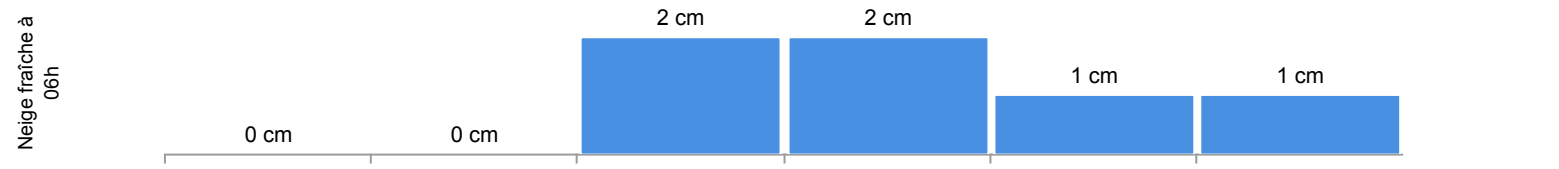

Risque d'avalanche	jeu. 05/03	ven. 06/03	sam. 07/03	dim. 08/03	lun. 09/03	mar. 10/03	mer. 11/03
	2	2	2	2	2	2	2

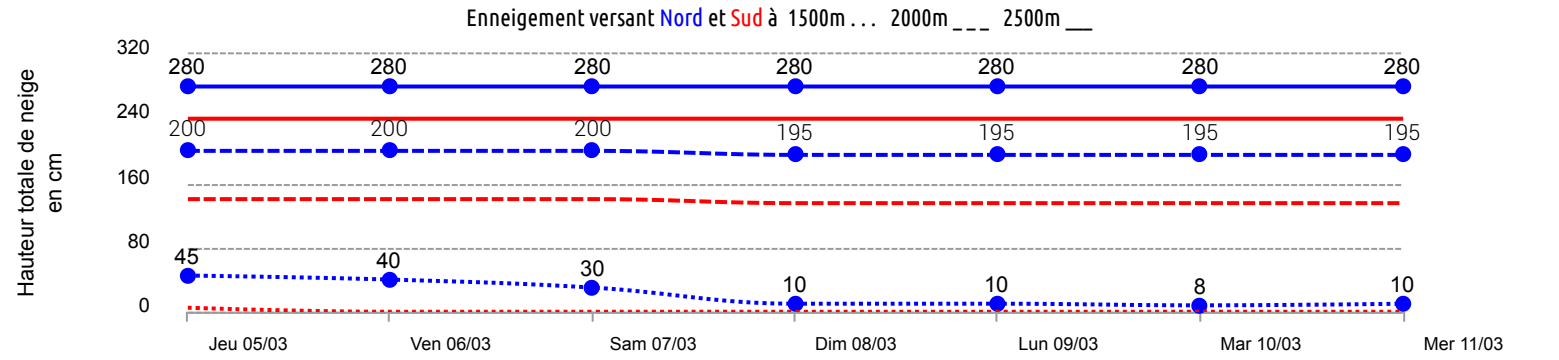

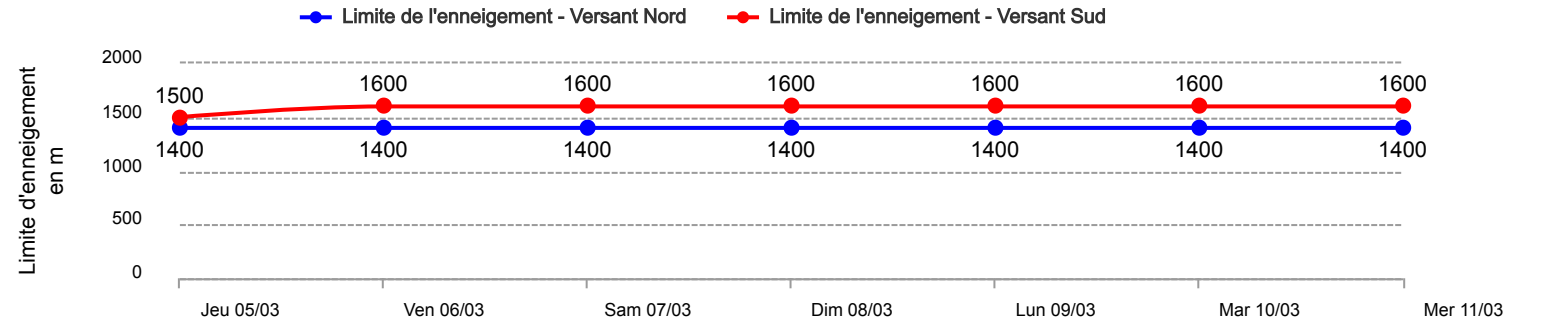

Pour consulter la vigilance en cours, veuillez vous rendre sur le site https://vigilance.meteofrance.fr/fr

Météo-France - 73 avenue de Paris, 94165 Saint-Mandé cedex - Contact : contact@meteo.fr

Rédigé par Météo-France avec la contribution des observateurs du réseau nivo-météorologiques. Partenariat : ANMSM (Maires de Stations de Montagne), DSF (Domaines Skiables de France), ADSP (Directeurs de Pistes et de la Sécurité des Stations de Sports d'Hiver) et autres acteurs de la montagne.

Bulletin neige & avalanches par téléphone au
0 892 68 10 20 Service 0,35 € / min + prix appel