Bulletin d'estimation du risque d'avalanche
(valable en dehors des pistes balisées et ouvertes)

MASSIF : Haute-Maurienne

Rédigé le mercredi 11 mars 2026 à 16h

Estimation des risques pour le : JEUDI 12 MARS

QUELQUES PLAQUES VENT EN ALTITUDE. COUCHES FRAGILES ENFOUIES GÉNÉRALISÉES MAIS PEU RÉACTIVES.

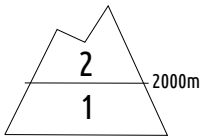

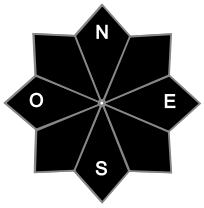

Au-dessus de 2000m indice de risque limité, plus bas indice faible.

Départs spontanés : rares petites plaques dans le très raide.

Déclenchements provoqués : rares plaques à vent et sur couches fragiles persistantes, tous versants.

Indices de risque : 5 très fort - 4 fort - 3 marqué - 2 limité - 1 faible -- En noir : les pentes les plus dangereuses

Stabilité du manteau neigeux

Situation avalancheuse typique : neige ventée couche fragile persistante

Déclenchements provoqués :
(1) des plaques en neige ferme/dure sont en place suite au coup de vent de Nord Ouest de la nuit de mercredi à jeudi. Généralement au-dessus de ~2400 m (là où la neige est restée froide), elles peuvent être réactives car elles reposent sur des grains anguleux (face plane). De dimension assez modeste, elle engendrent des avalanches petites à moyenne (taille 1 à 2).
(2) des **couches fragiles persistantes** (grains anguleux) sont **enfouies de manière généralisée dans le manteau** (en tous versants, même en sud de haute altitude). Leur sollicitation est très peu probable la majorité du temps mais devient possible :
- en versants NO/N/NE, au-dessus de 2000 m, dans les zones moins enneigées (abords de crête, croupes dégarnies) où une rare plaque dure peut subsister. Taille 1 à 2 (petite à moyenne).
- en versants ensoleillés à haute altitude, en journée lorsque la neige ramollit en surface, ce qui facilite la sollicitation d'une couche fragile enfouie (scénario moins probable que les jours précédents grâce aux nuages). Taille 2, plus rarement 3 (grande).

Départs spontanés : peu probables. Une petite plaque peut se décrocher là où le vent dépose la neige dans une pente raide - plutôt le matin.

Qualité de la neige

Enneigement : légèrement excédentaire pour la saison en moyenne montagne, mais en train de devenir déficitaire en basse montagne et en versants sud. Et très déficitaire en haute montagne près de la crête frontalière, voire carrément absent de certains cols ou faces très exposées au vent.

Limite skiable : encore skiable dès 1100/1200 m dans les prairies orientées nord, plutôt 1500/1600 m en sud pas trop raide.

Qualité de la neige : il est tombé très localement, près de la frontière italienne, 5/10 cm de neige fraîche.
On trouve une neige croutée en nord jusqu'à 2300/2500 m, encore froide plus haut mais généralement travaillée par le vent (rares secteurs en vieille poudre agréable). En versants O/S/E, neige de printemps qui "décaille" peu ou pas en journée à cause du vent.

Aperçu météo pour le jeudi 12 mars

	nuit	matin	après-midi	soir

Retour d'un Soleil très large en matinée. Vent de Nord Ouest en baisse progressive.

Pluie-Neige	1 200 m			
Iso 0 °C	1 600 m	2 000 m	2 300 m	2 300 m
Vent 2500 m	↘ 35 km/h	↘ 30 km/h	↘ 30 km/h	↘ 30 km/h
Vent 3500 m	↘ 45 km/h	↘ 35 km/h	↘ 35 km/h	↘ 35 km/h

Épaisseur de neige hors-piste

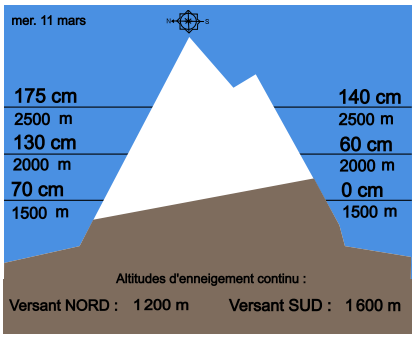

Précipitations à 1800 m

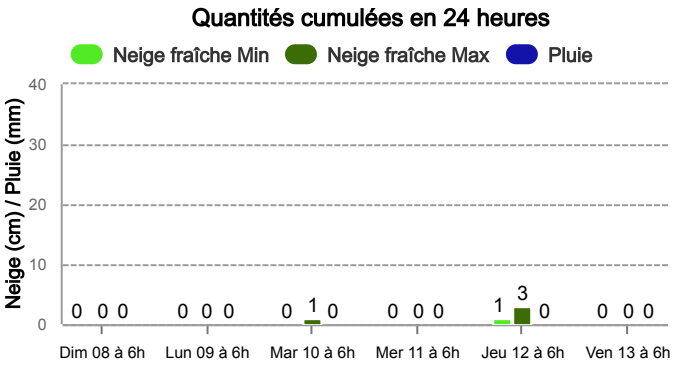

Tendance du vendredi 13 mars

Indice de risque limité

Les plaques à vent formées en altitude se stabilisent doucement.

Pour consulter la vigilance en cours, veuillez vous rendre sur le site https://vigilance.meteofrance.fr/fr

Météo-France - 73 avenue de Paris, 94165 Saint-Mandé cedex - Contact : contact@meteo.fr

Rédigé par Météo-France avec la contribution des observateurs du réseau nivo-météorologiques. Partenariat : ANMSM (Maires de Stations de Montagne), DSF (Domaines Skiables de France), ADSP (Directeurs de Pistes et de la Sécurité des Stations de Sports d'Hiver) et autres acteurs de la montagne.

Bulletin neige & avalanches par téléphone au
0 892 68 10 20 Service 0,35 € / min + prix appel

RÉPUBLIQUE FRANÇAISE
Liberté Égalité Fraternité

METEO FRANCE
À VOS CÔTÉS, DANS UN CLIMAT QUI CHANGE

Bulletin d'estimation du risque d'avalanche
(valable en dehors des pistes balisées et ouvertes)
MASSIF : Haute-Maurienne

Rédigé le mercredi 11 mars 2026 à 16h

Conditions nivo-météo des 7 derniers jours

	jeu. 05/03				ven. 06/03				sam. 07/03				dim. 08/03				lun. 09/03				mar. 10/03				mer. 11/03			
	03h	09h	15h	21h	03h	09h	15h	21h	03h	09h	15h	21h	03h	09h	15h	21h	03h	09h	15h	21h	03h	09h	15h	21h	03h	09h	15h	21h
Météo																												
Vent (km/h)	15	20	20	25	30	35	30	30	25	30	25	25	20	15	15	15	15	15	20	25	30	30	30	20	20	25	35	50
à 3500m																												
Vent (km/h)	15	20	20	25	30	30	25	25	20	25	20	15	20	15	15	15	15	15	20	30	25	20	15	10	10	10	25	40
à 2500m																												

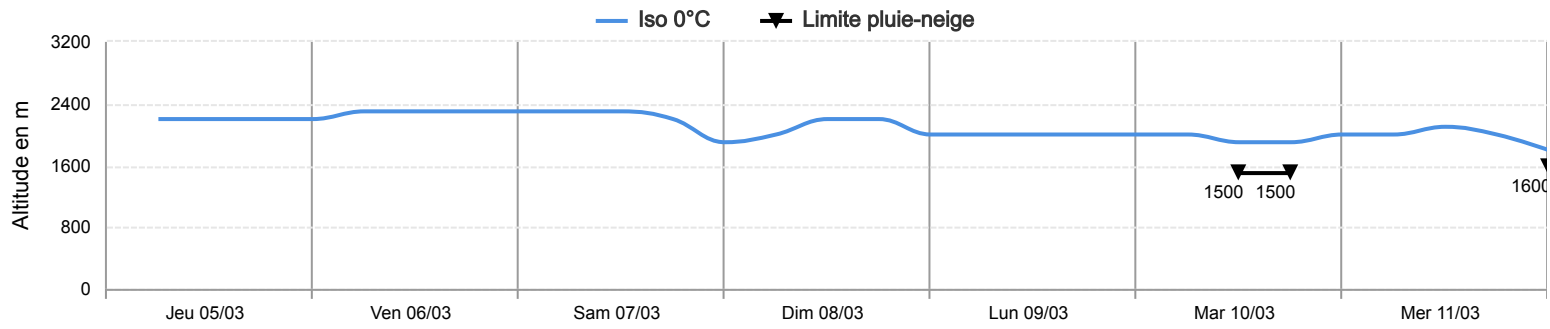

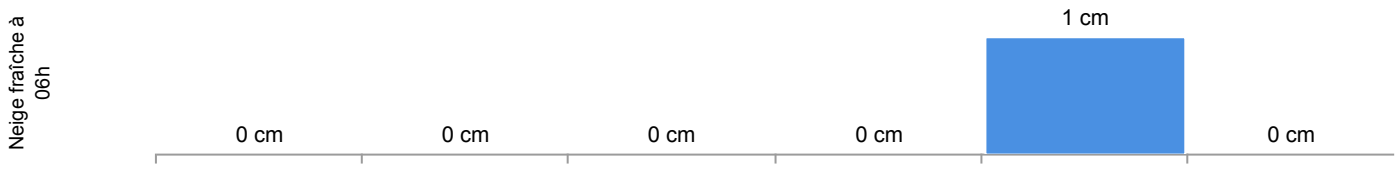

Risque d'avalanche	jeu. 05/03	ven. 06/03	sam. 07/03	dim. 08/03	lun. 09/03	mar. 10/03	mer. 11/03
	2	2	2	2	2	2	2

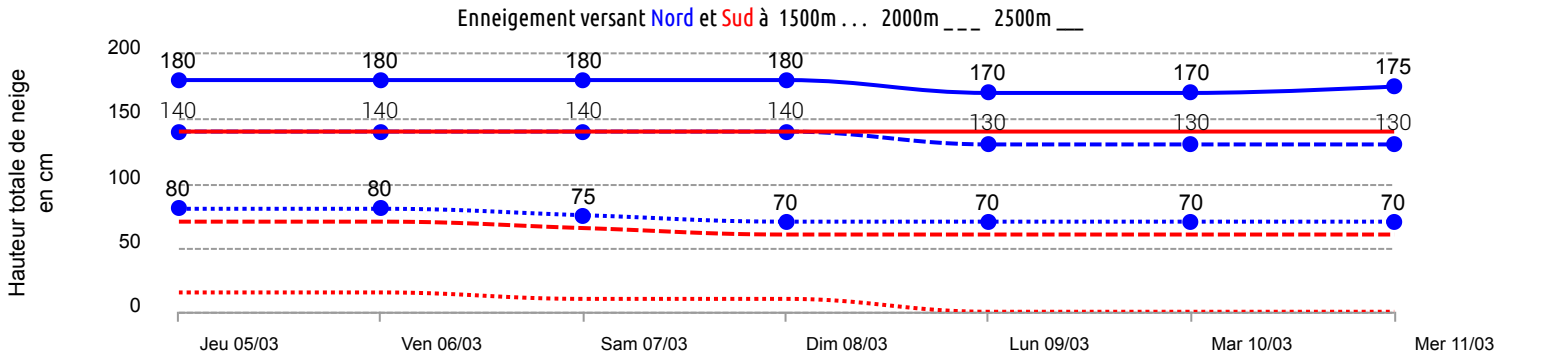

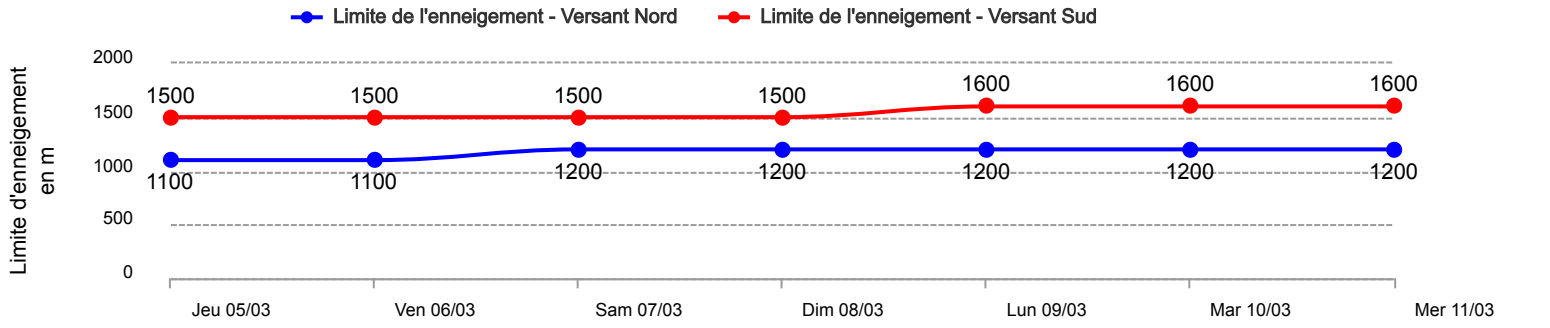

Pour consulter la vigilance en cours, veuillez vous rendre sur le site https://vigilance.meteofrance.fr/fr

Météo-France - 73 avenue de Paris, 94165 Saint-Mandé cedex - Contact : contact@meteo.fr

Rédigé par Météo-France avec la contribution des observateurs du réseau nivo-météorologiques. Partenariat : ANMSM (Maires de Stations de Montagne), DSF (Domaines Skiables de France), ADSP (Directeurs de Pistes et de la Sécurité des Stations de Sports d'Hiver) et autres acteurs de la montagne.

Bulletin neige & avalanches par téléphone au
0 892 68 10 20 Service 0,35 € / min + prix appel