Bulletin d'estimation du risque d'avalanche
(valable en dehors des pistes balisées et ouvertes)

MASSIF : Haute-Tarentaise

Rédigé le mercredi 11 mars 2026 à 16h

Estimation des risques pour le : JEUDI 12 MARS

QUELQUES PLAQUES VENT EN ALTITUDE. COUCHES FRAGILES ENFOUIES GÉNÉRALISÉES MAIS PEU RÉACTIVES.

2

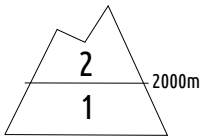

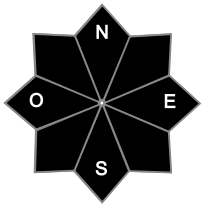

Au-dessus de 2000m indice de risque limité, plus bas indice faible.

Départs spontanés : escargots et départs ponctuels au Soleil.

Déclenchements provoqués : rares plaques à vent et sur couches fragiles persistantes, tous versants.

Indices de risque : 5 très fort - 4 fort - 3 marqué - 2 limité - 1 faible -- En noir : les pentes les plus dangereuses

Stabilité du manteau neigeux

Situation avalancheuse typique : neige ventée — couche fragile persistante

Déclenchements provoqués :
(1) quelques plaques dans la neige fraîche, en toutes orientations. De taille modeste secteur Tignes/Val d'Isère, les cassures gagnent en épaisseur secteur La Rosière, où les cumuls de neige fraîche sont plus importants (jusqu'à 20 cm sur les crêtes). Les plaques installées en versant ombragé (NE, N et NO) au-delà de 2400 m sont plus réactives que les autres car elles reposent sur des grains anguleux (face plane).
(2) des **couches fragiles persistantes** (grains anguleux) sont **enfouies de manière généralisée dans le manteau** au-dessus de 2200 m en large Nord et même en sud de haute altitude (en tous versants). Leur sollicitation est très peu probable mais elles engendrent des avalanches de taille 2 à 3 (moyenne à grande). Le déclenchement est plus probable dans les pentes peu enneigées.

Départs spontanés : en suivant la course du Soleil, des départs ponctuels (avalanche en poire) s'observent au départ des rochers, dans les pentes raides. Petites avalanches (taille 1) à prévoir.

Qualité de la neige

Enneigement : en général légèrement excédentaire pour la saison, mais en train de devenir déficitaire en basse montagne et en versant sud.

Limite skiable : encore skiable dès 1100/1200 m dans les prairies orientées nord, plutôt 1500/1600 m en sud pas trop raide.

Qualité de la neige : nouvelle petite couche de neige fraîche. Au-dessus de 2000 m, on trouve 20 à 10 cm du Nord Sud.
Dans les versants ombragés, elle reste bonne à skier toute la journée. Ailleurs, cette neige colle et botte rapidement une fois au Soleil.

Aperçu météo pour le jeudi 12 mars

	nuit	matin	après-midi	soir
	Retour d'un Soleil très large en matinée.			
Pluie-Neige	1 200 m			
Iso 0 °C	1 500 m	2 100 m	2 200 m	2 200 m
Vent 2500 m	30 km/h	20 km/h	20 km/h	20 km/h
Vent 3500 m	45 km/h	30 km/h	30 km/h	30 km/h

Épaisseur de neige hors-piste

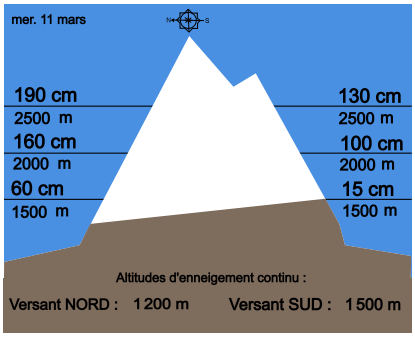

Précipitations à 1800 m

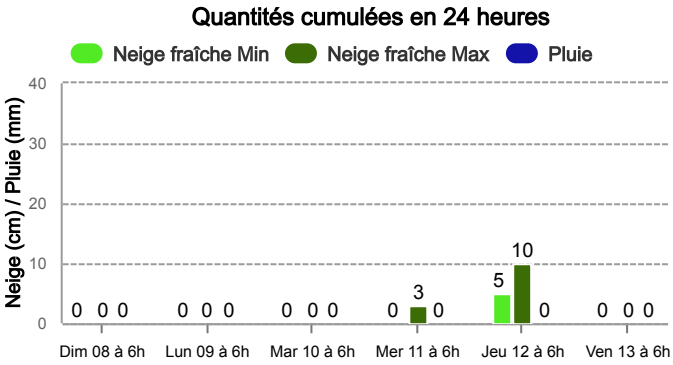

Tendance du vendredi 13 mars

2

Indice de risque limité

La neige fraîchement tombée se tasse rapidement. L'activité naturelle en versant ensoleillé est en forte baisse.

Pour consulter la vigilance en cours, veuillez vous rendre sur le site https://vigilance.meteofrance.fr/fr

Météo-France - 73 avenue de Paris, 94165 Saint-Mandé cedex - Contact : contact@meteo.fr

Rédigé par Météo-France avec la contribution des observateurs du réseau nivo-météorologiques. Partenariat : ANMSM (Maires de Stations de Montagne), DSF (Domaines Skiables de France), ADSP (Directeurs de Pistes et de la Sécurité des Stations de Sports d'Hiver) et autres acteurs de la montagne.

Bulletin neige & avalanches par téléphone au
0 892 68 10 20 Service 0,35 € / min + prix appel

RÉPUBLIQUE FRANÇAISE
Liberté Égalité Fraternité

METEO FRANCE
À VOS CÔTÉS, DANS UN CLIMAT QUI CHANGE

Bulletin d'estimation du risque d'avalanche

(valable en dehors des pistes balisées et ouvertes)

MASSIF : Haute-Tarentaise

Rédigé le mercredi 11 mars 2026 à 16h

Conditions nivo-météo des 7 derniers jours

	jeu. 05/03				ven. 06/03				sam. 07/03				dim. 08/03				lun. 09/03				mar. 10/03				mer. 11/03			
	03h	09h	15h	21h	03h	09h	15h	21h	03h	09h	15h	21h	03h	09h	15h	21h	03h	09h	15h	21h	03h	09h	15h	21h	03h	09h	15h	21h
Météo																												
Vent (km/h)	20	30	30	35	40	40	40	40	20	20	25	25	20	20	20	20	20	20	20	30	40	40	30	30	20	25	35	50
à 3500m																												
Vent (km/h)	15	20	30	35	50	50	40	30	25	25	20	15	20	15	15	15	15	15	20	40	25	20	10	5	10	10	25	40
à 2500m																												

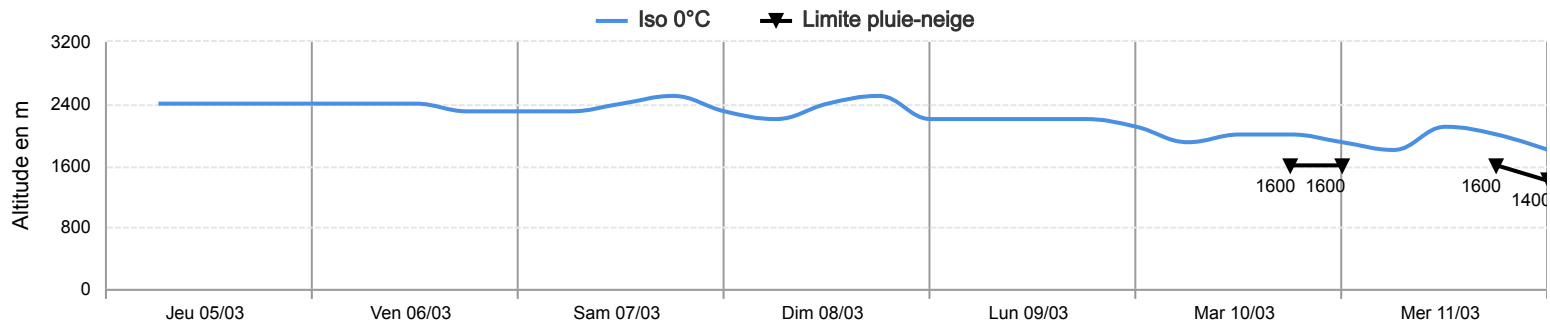

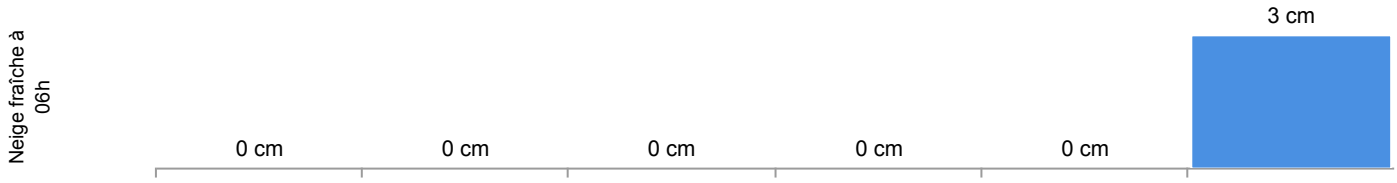

Risque d'avalanche	jeu. 05/03	ven. 06/03	sam. 07/03	dim. 08/03	lun. 09/03	mar. 10/03	mer. 11/03
	2	2	2	2	2	2	2

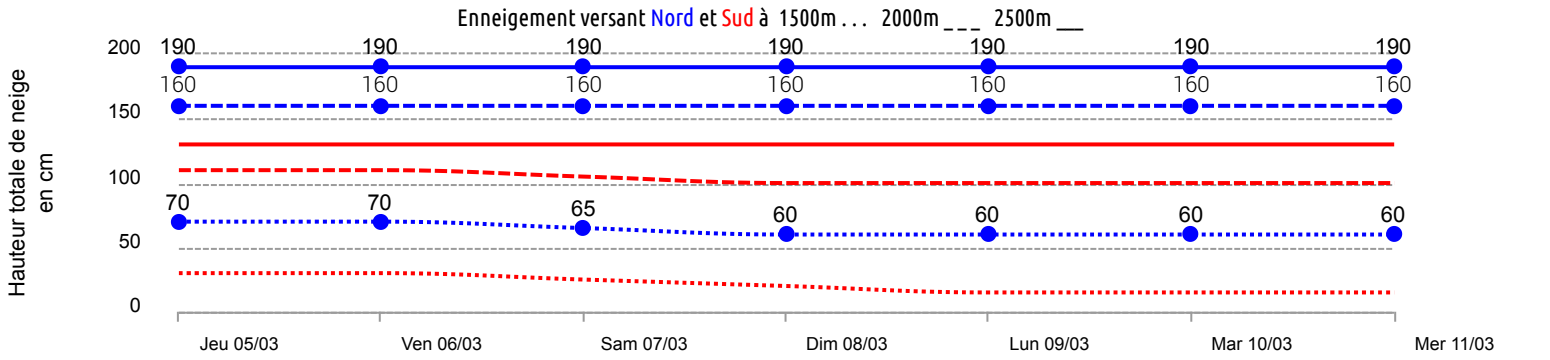

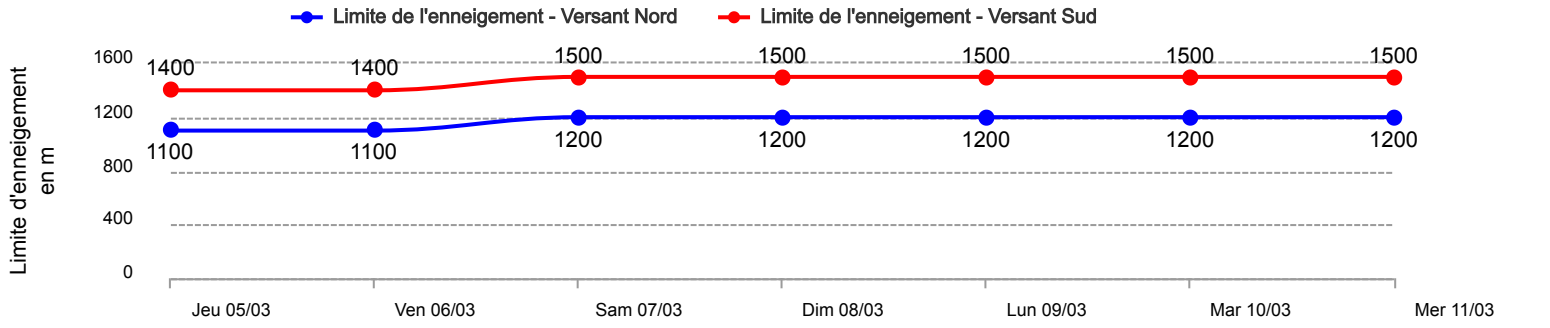

Pour consulter la vigilance en cours, veuillez vous rendre sur le site https://vigilance.meteofrance.fr/fr

Météo-France - 73 avenue de Paris, 94165 Saint-Mandé cedex - Contact : contact@meteo.fr

Rédigé par Météo-France avec la contribution des observateurs du réseau nivo-météorologiques. Partenariat : ANMSM (Maires de Stations de Montagne), DSF (Domaines Skiables de France), ADSP (Directeurs de Pistes et de la Sécurité des Stations de Sports d'Hiver) et autres acteurs de la montagne.

Bulletin neige & avalanches par téléphone au
0 892 68 10 20 Service 0,35 € / min + prix appel