Bulletin d'estimation du risque d'avalanche
(valable en dehors des pistes balisées et ouvertes)

MASSIF : Mercantour

Rédigé le mercredi 11 mars 2026 à 16h

Estimation des risques pour le : JEUDI 12 MARS

QUELQUES INSTABILITÉS EN NEIGE FRAÎCHE

2

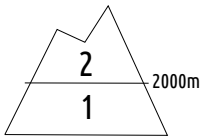

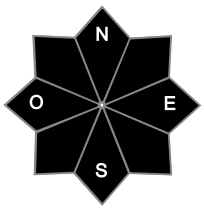

Au-dessus de 2000m indice de risque limité, plus bas indice faible.

Départs spontanés : quelques départs superficiels de neige humide au soleil.

Déclenchements provoqués : quelques instabilités en neige fraîche.

Indices de risque : 5 très fort - 4 fort - 3 marqué - 2 limité - 1 faible -- En noir : les pentes les plus dangereuses

Stabilité du manteau neigeux

Situation avalancheuse typique : neige ventée

Déclenchements provoqués :
- quelques plaques sont possibles dans la neige fraîche, présentes surtout au dessus de 1800/2000 m à proximité de la frontière italienne. Elles sont le plus souvent d'aspect poudreux, parfois travaillées par le vent de nord, et peuvent être localement faciles à déclencher, mais restent généralement de petite taille, localement moyenne.

Départs spontanés :
- quelques départs ponctuels de petite taille, en neige fraîche s'humidifiant en pentes raides ensoleillées sous les éclaircies.

Qualité de la neige

Enneigement plutôt excédentaire pour un début mars en général, notamment dans le Haut-Verdon.
Données observées : 142 cm à la nivôse de Millefonts à 2430 m.

Enneigement skiable : vers 1400/1500 m en ubacs, 1800/1900 m en adrets peu pentus.

État de la neige en surface : jeudi matin, petite couche de neige récente vers la frontière italienne (entre 3 et 7 cm). Elle repose sur une neige encore froide en ubacs au dessus de 2200 m, croutée en dessous ainsi que dans les adrets.

Aperçu météo pour le jeudi 12 mars

	nuit	matin	après-midi	soir

Temps restant nuageux à la frontière italienne avec un peu de neige le matin, des averses plus éparses l'après-midi. Plus ensoleillé ailleurs.

Pluie-Neige	1 500 m	1 400 m	1 600 m	
Iso 0 °C	1 900 m	1 800 m	2 000 m	2 300 m
Vent 2000 m	20 km/h	40 km/h	35 km/h	25 km/h
Vent 3000 m	40 km/h	35 km/h	35 km/h	20 km/h

Épaisseur de neige hors-piste

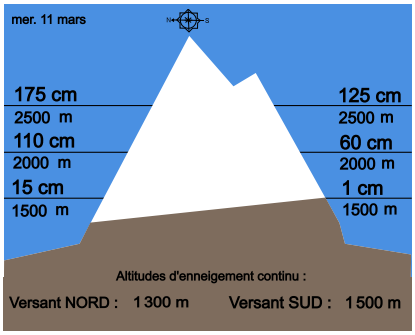

Précipitations à 1800 m

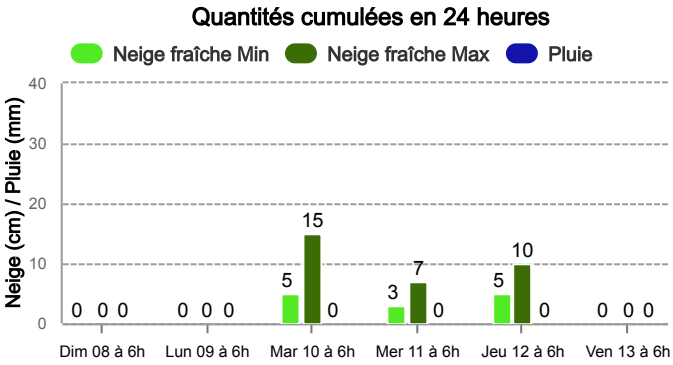

Tendance du vendredi 13 mars

2

Indice de risque limité

Maintient d'un risque limité, avec poursuite d'une humidification superficielle, et de rares plaques en altitude, avant une dégradation des conditions dans la nuit de vendredi à samedi.

Pour consulter la vigilance en cours, veuillez vous rendre sur le site https://vigilance.meteofrance.fr/fr

Météo-France - 73 avenue de Paris, 94165 Saint-Mandé cedex - Contact : contact@meteo.fr

Rédigé par Météo-France avec la contribution des observateurs du réseau nivo-météorologiques. Partenariat : ANMSM (Maires de Stations de Montagne), DSF (Domaines Skiables de France), ADSP (Directeurs de Pistes et de la Sécurité des Stations de Sports d'Hiver) et autres acteurs de la montagne.

Bulletin neige & avalanches par téléphone au
0 892 68 10 20 Service 0,35 € / min + prix appel

Bulletin d'estimation du risque d'avalanche

(valable en dehors des pistes balisées et ouvertes)

MASSIF : Mercantour

Rédigé le mercredi 11 mars 2026 à 16h

Conditions nivo-météo des 7 derniers jours

	jeu. 05/03				ven. 06/03				sam. 07/03				dim. 08/03				lun. 09/03				mar. 10/03				mer. 11/03			
	03h	09h	15h	21h	03h	09h	15h	21h	03h	09h	15h	21h	03h	09h	15h	21h	03h	09h	15h	21h	03h	09h	15h	21h	03h	09h	15h	21h
Météo																												
Vent (km/h)	10	15	20	35	50	45	40	35	35	30	25	20	20	15	15	10	15	20	25	30	45	40	30	20	25	35	45	40
à 3000m																												
Vent (km/h)	15	20	25	35	30	30	30	30	30	25	20	15	20	15	15	10	15	15	15	15	20	10	15	10	10	15	20	15
à 2000m																												

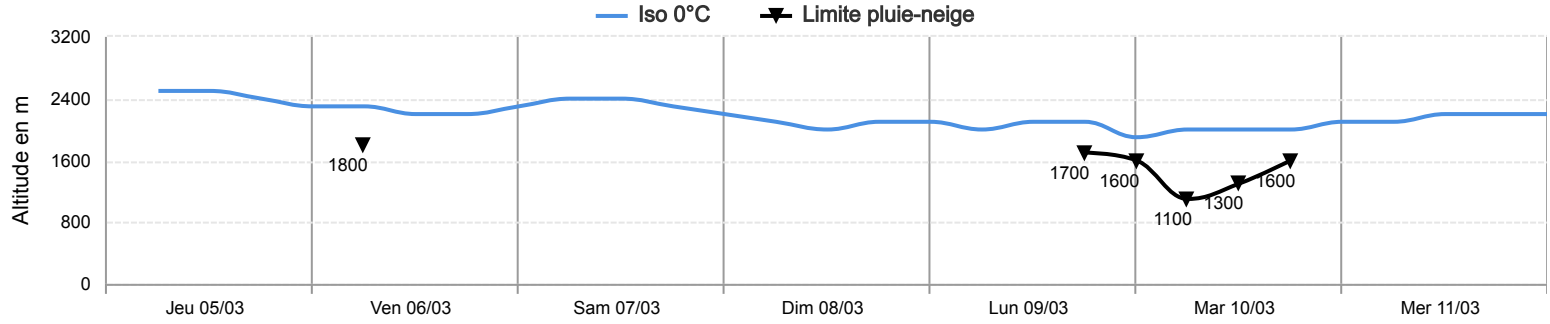

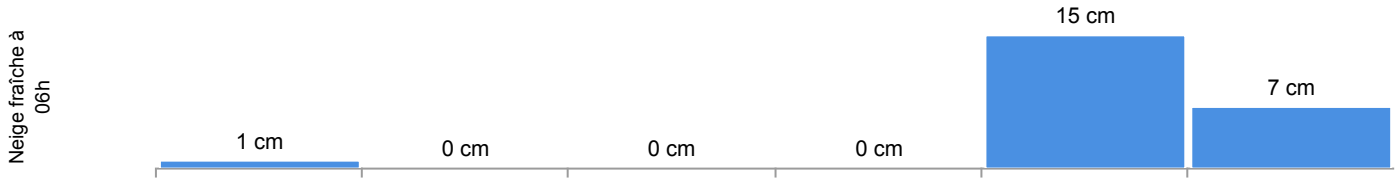

Risque d'avalanche	jeu. 05/03	ven. 06/03	sam. 07/03	dim. 08/03	lun. 09/03	mar. 10/03	mer. 11/03
	2	2	1	1	1	2	2

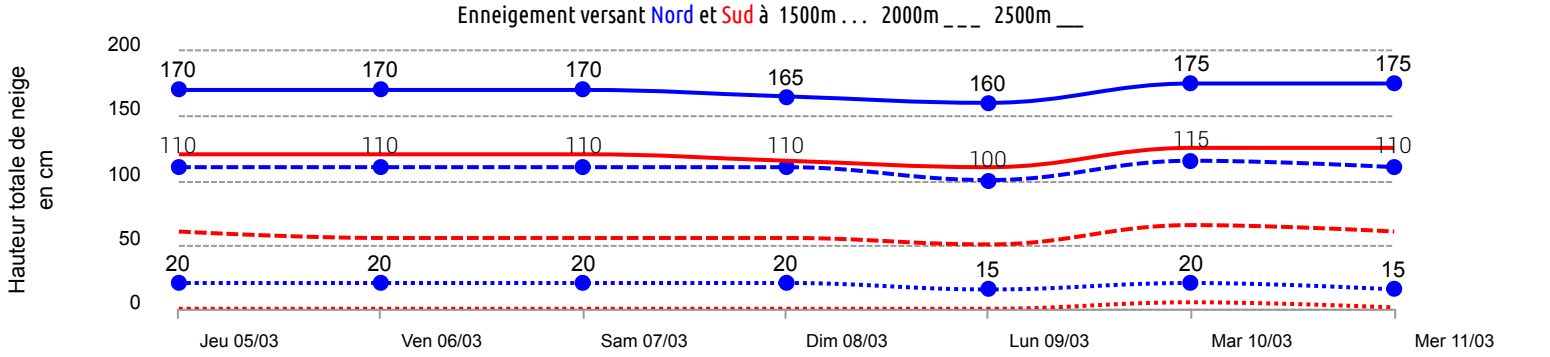

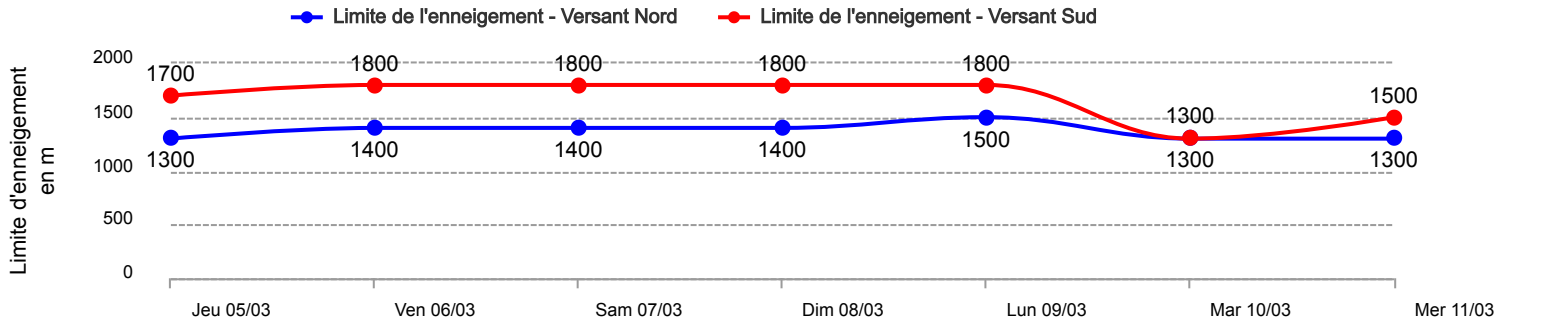

Pour consulter la vigilance en cours, veuillez vous rendre sur le site https://vigilance.meteofrance.fr/fr

Météo-France - 73 avenue de Paris, 94165 Saint-Mandé cedex - Contact : contact@meteo.fr

Bulletin neige & avalanches par téléphone au

0 892 68 10 20 Service 0,35 € / min + prix appel

Rédigé par Météo-France avec la contribution des observateurs du réseau nivo-météorologiques. Partenariat : ANMSM (Maires de Stations de Montagne), DSF (Domaines Skiables de France), ADSP (Directeurs de Pistes et de la Sécurité des Stations de Sports d'Hiver) et autres acteurs de la montagne.