Bulletin d'estimation du risque d'avalanche
(valable en dehors des pistes balisées et ouvertes)

MASSIF : Thabor

Rédigé le mercredi 11 mars 2026 à 16h

Estimation des risques pour le : JEUDI 12 MARS

PLAQUES RÉSIDUELLES EN ALTITUDE, DIFFICILES À SOLLICITER - FAIBLE ACTIVITÉ NATURELLE

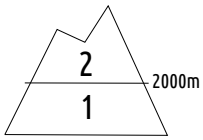

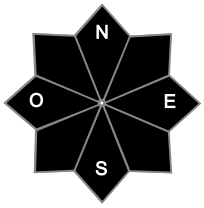

Au-dessus de 2000m indice de risque limité, plus bas indice faible.

Départs spontanés : quelques petits départs de neige fraiche s'humidifiant au soleil.

Déclenchements provoqués : quelques plaques superficielles. D'autres plus épaisses en altitude, difficiles à déclencher.

Indices de risque : 5 très fort - 4 fort - 3 marqué - 2 limité - 1 faible -- En noir : les pentes les plus dangereuses

Stabilité du manteau neigeux

Situation avalancheuse typique : couche fragile persistante neige ventée

Départs spontanés : - Quelques départs superficiels en neige fraîche s'humidifiant au soleil, restant de petite taille.
- Une avalanche de fond n'est pas exclue sur les secteurs avec un sol favorable (pentes herbeuses, dalles rocheuses). Avalanches de taille moyenne (taille 2).

Déclenchements provoqués : Manteau neigeux généralement bien stabilisé.
- Quelques plaques superficielles peuvent être présentes dans la neige fraiche ventée, plutôt en Ubacs au-dessus de 2000/2200 m ou à proximité des crêtes. Départs restant de petite taille.
- Un départ plus volumineux reste non exclu en cas de sollicitation de couches fragiles plus profondément enfouies, présentes en versant est, nord et ouest à partir de 2200 m, voir en versant sud à haute altitude. Déclenchement très difficile au passage d'un skieur, possible suite à un premier départ superficiel dans la neige récente, ou en pente fortement humidifiée d'altitude. Cassure épaisse en cas de départ, emportant une grande partie du manteau neigeux.

Qualité de la neige

L'enneigement est proche des normales. Les limites d'enneigement remontent dans les pentes bien exposées au soleil.
Hauteurs de neige observées vers 2500 m : 178 cm dans le vallon du Chardonnet, 114 cm à la nivôse des Rochilles, 87 cm à la Nivôse du Galibier (secteur venté).

Limite d'enneigement skiable : vers 1300/1400 m en ubacs, 1700/1800 m en adrets pas trop raides.

État de la neige de surface : Jeudi matin, on retrouve 5 à 10 cm de neige fraiche en surface, devenant rapidement collante au soleil, mais restant froide en ubac au-dessus de 1800/2000 m. Cette neige repose sur un manteau neigeux croûté dans les adrets, ainsi qu'en ubacs sous 2200/2300 m. Dans les pentes nord-ouest à nord-est au-dessus de 2200/2300 m environ, elle repose sur de la vielle poudreuse dense, parfois travaillée par le vent proche des crêtes.

Aperçu météo pour le jeudi 12 mars

	nuit	matin	après-midi	soir
Temps sec, généralement ensoleillé. Quelques cumulus l'après-midi.				
Pluie-Neige	1 300 m			
Iso 0 °C	1 600 m	1 900 m	2 400 m	2 300 m
Vent 2000 m	↘ 20 km/h	↓ 20 km/h	↘ 15 km/h	← 10 km/h
Vent 3000 m	↘ 40 km/h	↘ 30 km/h	↓ 20 km/h	↘ 10 km/h

Épaisseur de neige hors-piste

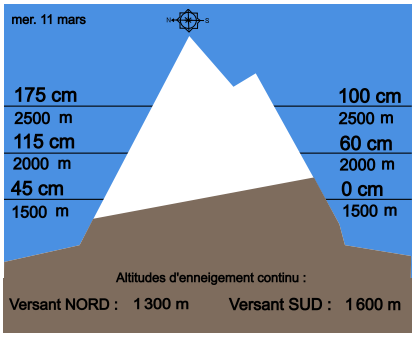

Précipitations à 1800 m

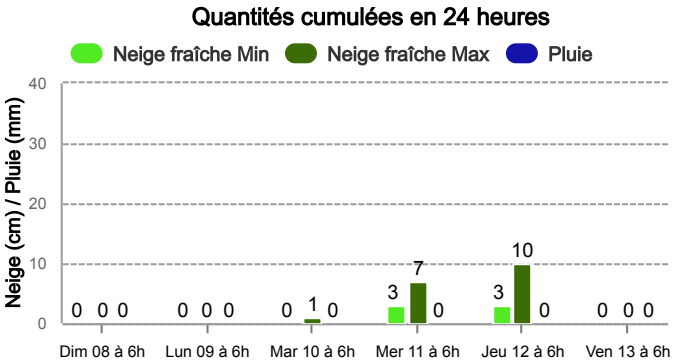

Tendance du vendredi 13 mars

Indice de risque limité

Risque en baisse avec la stabilisation rapide des plaques dans la neige fraiche.
Maintien de plaques résiduelles plus épaisses en altitude, difficiles à déclencher.

Pour consulter la vigilance en cours, veuillez vous rendre sur le site https://vigilance.meteofrance.fr/fr

Météo-France - 73 avenue de Paris, 94165 Saint-Mandé cedex - Contact : contact@meteo.fr

Rédigé par Météo-France avec la contribution des observateurs du réseau nivo-météorologiques. Partenariat : ANMSM (Maires de Stations de Montagne), DSF (Domaines Skiables de France), ADSP (Directeurs de Pistes et de la Sécurité des Stations de Sports d'Hiver) et autres acteurs de la montagne.

Bulletin neige & avalanches par téléphone au **0 892 68 10 20** Service 0,35 € / min + prix appel

Bulletin d'estimation du risque d'avalanche

(valable en dehors des pistes balisées et ouvertes)

MASSIF : Thabor

Rédigé le mercredi 11 mars 2026 à 16h

Conditions nivo-météo des 7 derniers jours

	jeu. 05/03				ven. 06/03				sam. 07/03				dim. 08/03				lun. 09/03				mar. 10/03				mer. 11/03			
	03h	09h	15h	21h	03h	09h	15h	21h	03h	09h	15h	21h	03h	09h	15h	21h	03h	09h	15h	21h	03h	09h	15h	21h	03h	09h	15h	21h
Météo																												
Vent (km/h)	20	25	25	35	40	40	35	40	40	30	30	35	30	30	25	25	30	35	35	50	35	30	25	10	15	20	35	40
à 3000m																												
Vent (km/h)	10	15	20	15	20	20	20	20	20	20	20	20	15	15	20	20	15	20	25	30	15	15	15	5	10	10	20	15
à 2000m																												

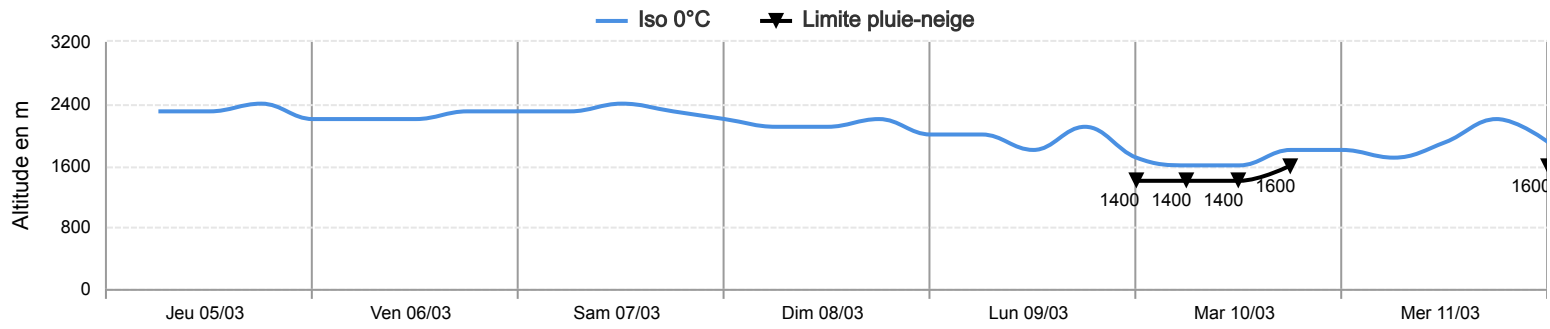

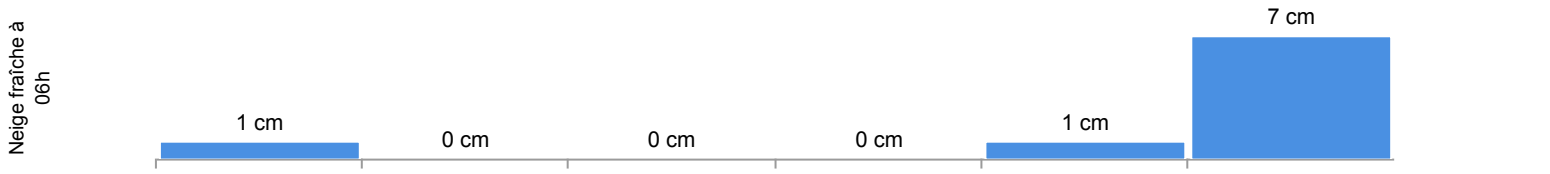

Risque d'avalanche	jeu. 05/03	ven. 06/03	sam. 07/03	dim. 08/03	lun. 09/03	mar. 10/03	mer. 11/03
	2	2	2	2	2	2	2

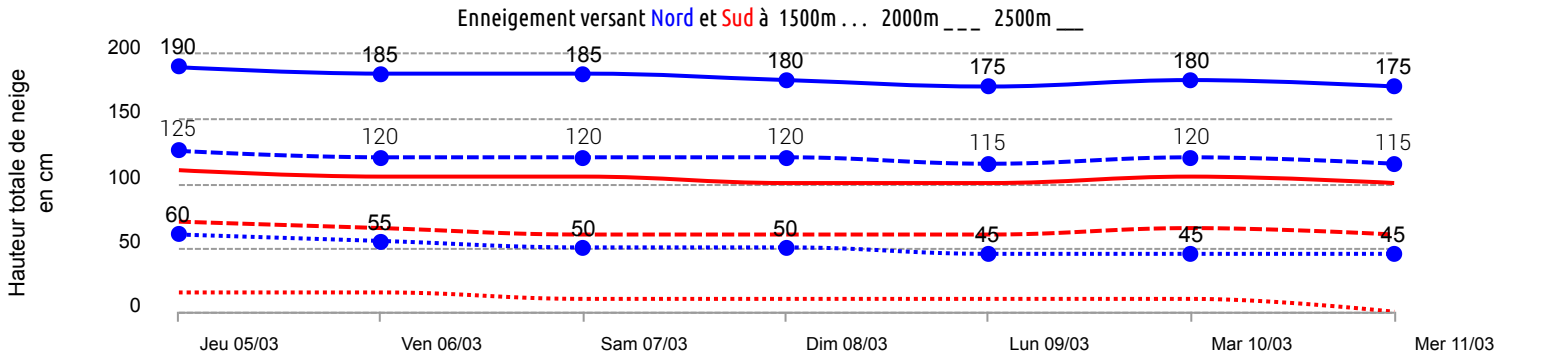

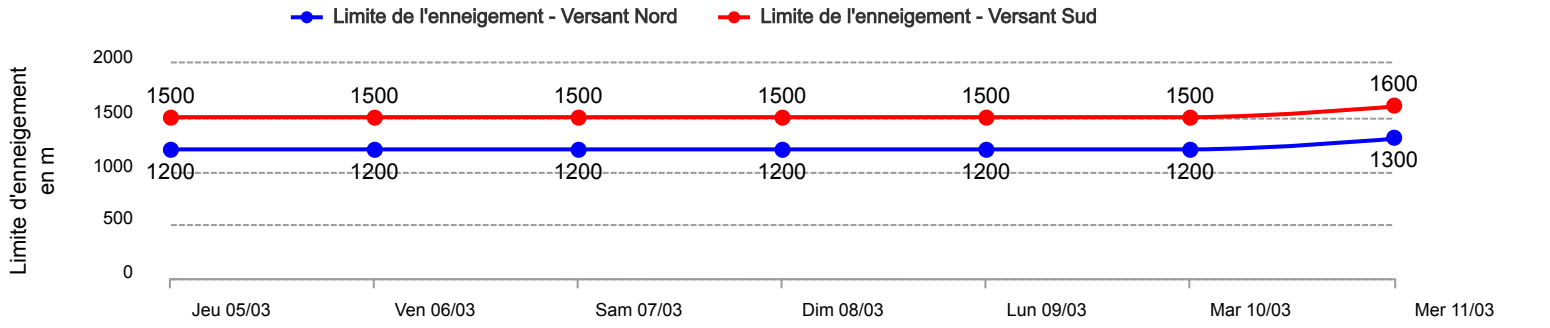

Pour consulter la vigilance en cours, veuillez vous rendre sur le site https://vigilance.meteofrance.fr/fr

Météo-France - 73 avenue de Paris, 94165 Saint-Mandé cedex - Contact : contact@meteo.fr

Rédigé par Météo-France avec la contribution des observateurs du réseau nivo-météorologiques. Partenariat : ANMSM (Maires de Stations de Montagne), DSF (Domaines Skiables de France), ADSP (Directeurs de Pistes et de la Sécurité des Stations de Sports d'Hiver) et autres acteurs de la montagne.

Bulletin neige & avalanches par téléphone au

0 892 68 10 20 Service 0,35 € / min + prix appel