Bulletin d'estimation du risque d'avalanche
(valable en dehors des pistes balisées et ouvertes)

MASSIF : Ubaye

Rédigé le mercredi 11 mars 2026 à 16h

Estimation des risques pour le : JEUDI 12 MARS

QUELQUES INSTABILITÉS EN ALTITUDE, HUMIDIFICATION SUPERFICIELLE

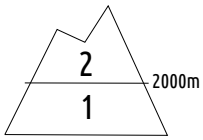

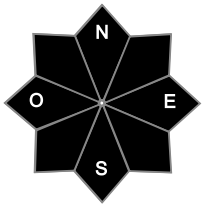

Au-dessus de 2000m indice de risque limité, plus bas indice faible.

Départs spontanés : quelques départs superficiels de neige humide au soleil.

Déclenchements provoqués : quelques instabilités superficielles en neige fraîche, et rares instabilités plus volumineuses difficiles à déclencher en ubacs d'altitude.

Indices de risque : 5 très fort - 4 fort - 3 marqué - 2 limité - 1 faible -- En noir : les pentes les plus dangereuses

Stabilité du manteau neigeux

Situation avalancheuse typique : couche fragile persistante neige ventée

Déclenchements provoqués :
- quelques plaques sont possibles dans la neige fraîche, présentes au dessus de 1800/2000 m. Elles sont le plus souvent d'aspect poudreux, parfois travaillées par le vent de nord, et peuvent être localement faciles à déclencher, mais restent de petite taille.
- D'anciennes plaques dures reposant sur des couches fragiles persistantes enfouies sont toujours présentes, principalement en orientations nord-ouest, nord ou nord-est au-dessus de 2200 m, surtout en Haute-Ubaye. Elles sont difficiles à solliciter par un seul skieur, mais elles peuvent toutefois en cas de déclenchement mobiliser d'importants volumes de neige (taille moyenne, voire grande non exclue).

Départs spontanés :
- quelques départs ponctuels de petite taille, en neige fraîche s'humidifiant en pentes raides au fil de la course du soleil.
- éventuellement une avalanche de glissement de taille moyenne, en pentes d'un large secteur sud, en terrain favorable (pentes herbeuses, dalles rocheuses).

Qualité de la neige

Enneigement proche des normales pour un début mars.
Données observées : 76 cm à la Nivôse de Restefond à 2550 m (secteur venté), 87 cm au-dessus de Larche à 2270 m en adret.

Enneigement skiable : vers 1600 m en ubacs, 1900/2000 m en adrets peu pentus.

État de la neige en surface : jeudi matin, petite couche de neige récente (entre 5 et 10 cm). Elle repose sur une neige encore froide en ubacs au dessus de 2200 m, croutée en dessous ainsi que dans les adrets. Reprise de l'humidification au soleil en cours de journée. Sur les crêtes, d'anciennes corniches épaisses côtoient des zones dégarnies.

Aperçu météo pour le jeudi 12 mars

	nuit	matin	après-midi	soir

Temps sec et généralement bien ensoleillé, plus nuageux à la frontière italienne où quelques flocons épars sont possibles l'après-midi.

Pluie-Neige	1 300 m			
Iso 0 °C	2 000 m	2 200 m	2 300 m	2 300 m
Vent 2000 m	15 km/h	15 km/h	15 km/h	10 km/h
Vent 3000 m	35 km/h	25 km/h	20 km/h	15 km/h

Épaisseur de neige hors-piste

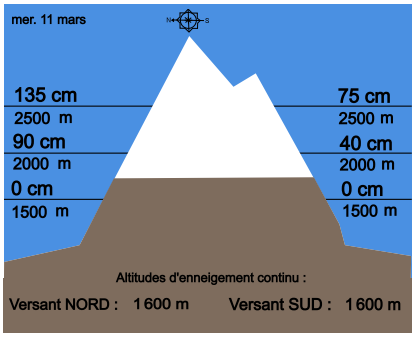

Précipitations à 1800 m

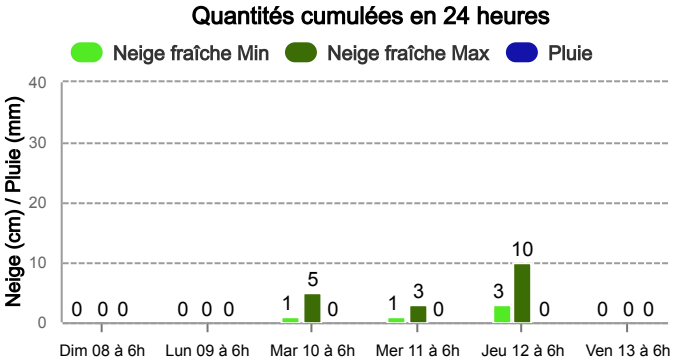

Tendance du vendredi 13 mars

Indice de risque limité

Maintient d'un risque limité, avec poursuite d'une humidification superficielle, et de rares plaques en altitude, avant une dégradation des conditions dans la nuit de vendredi à samedi.

Pour consulter la vigilance en cours, veuillez vous rendre sur le site https://vigilance.meteofrance.fr/fr

Météo-France - 73 avenue de Paris, 94165 Saint-Mandé cedex - Contact : contact@meteo.fr

Rédigé par Météo-France avec la contribution des observateurs du réseau nivo-météorologiques. Partenariat : ANMSM (Maires de Stations de Montagne), DSF (Domaines Skiables de France), ADSP (Directeurs de Pistes et de la Sécurité des Stations de Sports d'Hiver) et autres acteurs de la montagne.

Bulletin neige & avalanches par téléphone au **0 892 68 10 20** Service 0,35 € / min + prix appel

RÉPUBLIQUE FRANÇAISE
Liberté Égalité Fraternité

METEO FRANCE
À VOS CÔTÉS, DANS UN CLIMAT QUI CHANGE

Bulletin d'estimation du risque d'avalanche

(valable en dehors des pistes balisées et ouvertes)

MASSIF : Ubaye

Rédigé le mercredi 11 mars 2026 à 16h

Conditions nivo-météo des 7 derniers jours

	jeu. 05/03				ven. 06/03				sam. 07/03				dim. 08/03				lun. 09/03				mar. 10/03				mer. 11/03			
	03h	09h	15h	21h	03h	09h	15h	21h	03h	09h	15h	21h	03h	09h	15h	21h	03h	09h	15h	21h	03h	09h	15h	21h	03h	09h	15h	21h
Météo																												
Vent (km/h)	20	20	30	45	60	60	50	45	40	30	25	20	25	15	15	15	15	20	25	30	40	40	30	15	20	30	45	40
à 3000m	←	↑	↖	↖	↖	←	←	←	←	←	←	←	←	↖	↑	↑	↑	↑	↖	↖	↖	↑	↗	→	→	→	→	→
Vent (km/h)	25	30	35	40	35	30	30	30	25	25	20	15	15	15	15	5	5	10	20	20	15	10	5	5	5	10	20	15
à 2000m	←	←	←	←	←	←	←	←	←	←	←	←	←	↖	↖	←	↖	←	←	←	↖	←	↗	↑	↑	→	→	→

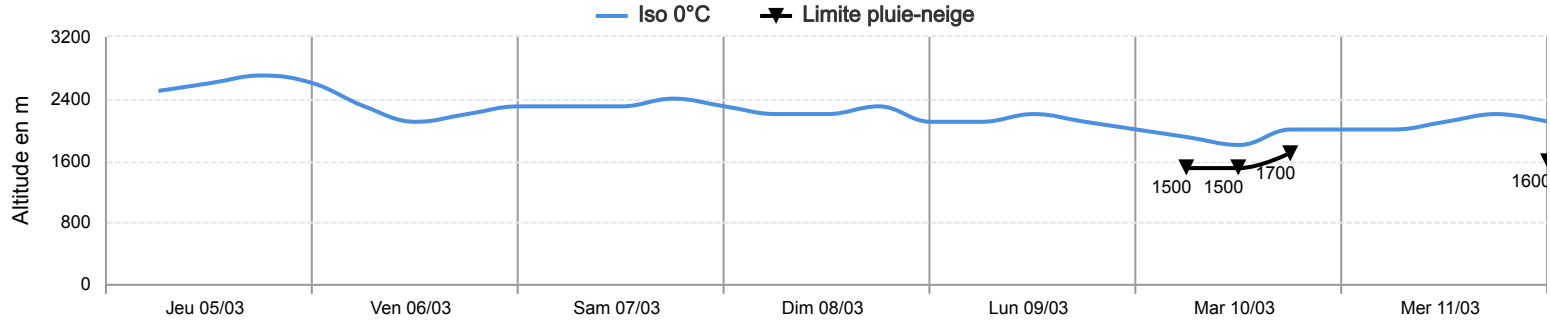

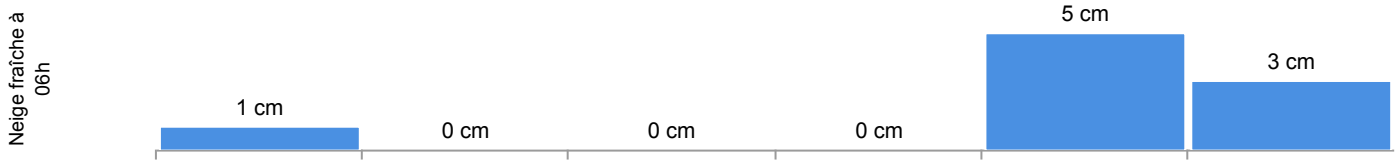

Risque d'avalanche	jeu. 05/03	ven. 06/03	sam. 07/03	dim. 08/03	lun. 09/03	mar. 10/03	mer. 11/03
	2	2	2	2	2	2	2

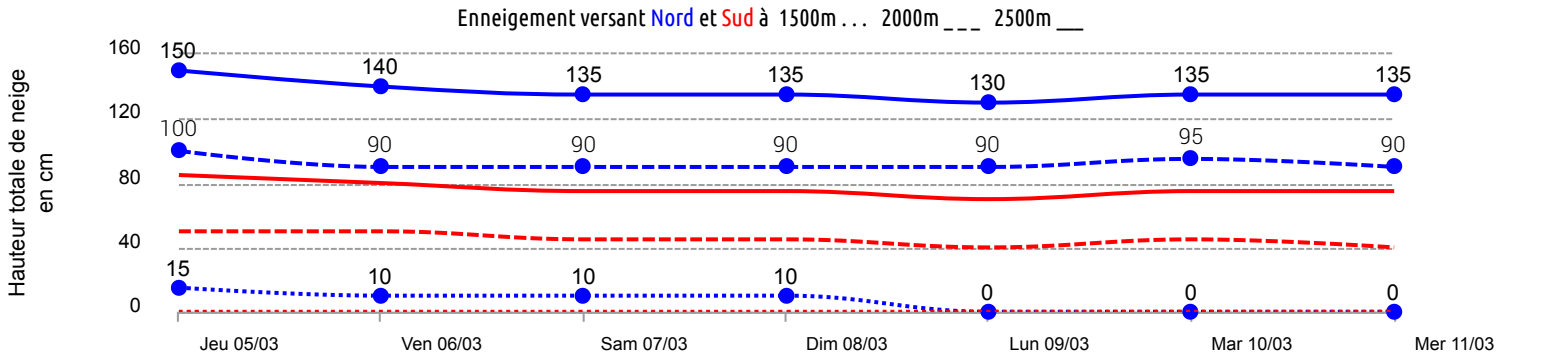

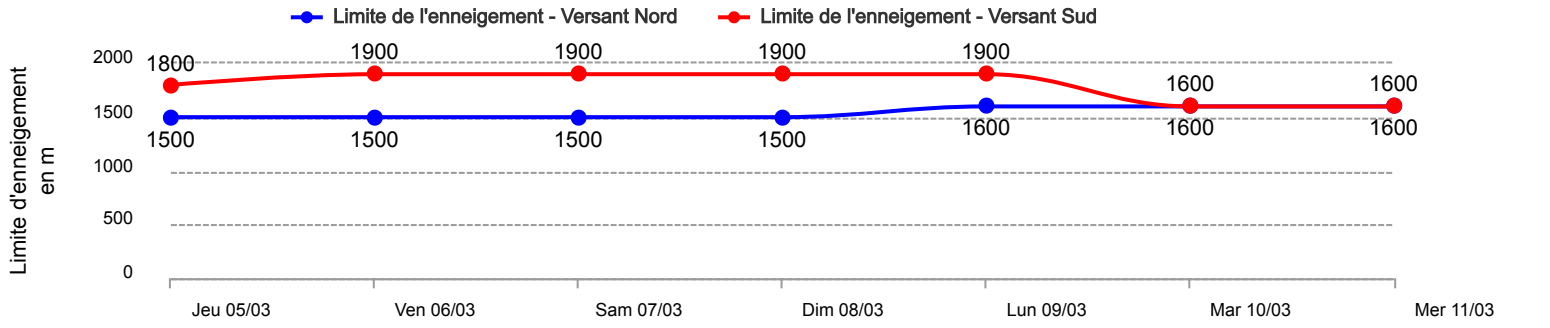

Pour consulter la vigilance en cours, veuillez vous rendre sur le site https://vigilance.meteofrance.fr/fr

Météo-France - 73 avenue de Paris, 94165 Saint-Mandé cedex - Contact : contact@meteo.fr

Rédigé par Météo-France avec la contribution des observateurs du réseau nivo-météorologiques. Partenariat : ANMSM (Maires de Stations de Montagne), DSF (Domaines Skiables de France), ADSP (Directeurs de Pistes et de la Sécurité des Stations de Sports d'Hiver) et autres acteurs de la montagne.

Bulletin neige & avalanches par téléphone au
0 892 68 10 20 Service 0,35 € / min + prix appel