Bulletin d'estimation du risque d'avalanche

(valable en dehors des pistes balisées et ouvertes)

MASSIF : Vercors

Rédigé le mercredi 11 mars 2026 à 16h

Estimation des risques pour le : JEUDI 12 MARS

NEIGE FRAICHE (10/15 CM) LOCALEMENT SOUFFLEE VERS LES HAUTES CRETES + COULEES SUPERFICIELLES LORS D'ECLAIRCIES...

2

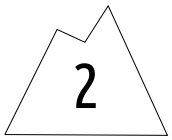

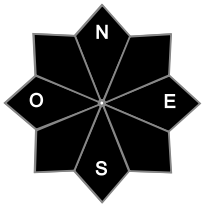

Crêtes d'altitude

Indices de risque : 5 très fort - 4 fort - 3 marqué - 2 limité - 1 faible -- En noir : les pentes les plus dangereuses

Indice de risque limité.

Départs spontanés : Coulées (superficielles) de neige récente au soleil, rare avalanche de fond en pentes herbeuses...

Déclenchements provoqués : Petites plaques temporairement instables à l'abord des hautes crêtes et sommets (jeudi matin surtout)...

Stabilité du manteau neigeux

Situation avalancheuse typique : neige fraîche avalanches de fond

Neige fraîche localement soufflée à l'abord des hautes crêtes et sommets, petites plaques temporairement instables au passage de skieur... Sinon sous couches denses, stables...

Déclenchements provoqués :

Petites plaques temporairement fragiles au passage de skieurs, surtout en matinée à l'abord des hautes crêtes. Plaques peu volumineuses mais parfois suffisantes pour déstabiliser un skieur.

10 à 15 cm attendus en altitude, parfois soufflés (vent d'Ouest puis de Nord jeudi matin).

L'après-midi, humidification possible au soleil, tassement de cette neige récente avec plutôt un risque de coulée humide ponctuelle sous les skis (glissant sur la veille neige dense).

Départs spontanés :

En matinée lors d'éclaircies, puis l'après-midi en tous versants : des coulées ponctuelles de surface et escargots de neige fraîche humidifiée.

Enfin dans une très rare pente herbeuse/secteur de reptation, une avalanche de fond, glissant au terrain reste possible (de taille moyenne).

Qualité de la neige

Qualification de l'enneigement : L'enneigement est bon pour la saison en versants ombragés au dessus de 1500 m, il a bien régressé en faces Sud, vers les crêtes. Amélioration du paysage jeudi.

Limites skiables : Vers 1200/1600m hors sapins, guère de sous couche plus bas.

Qualité de la neige jeudi : Fraîche encore poudreuse au petit matin, à l'ombre. En matinée humidification en pentes favorisées, au soleil. L'après-midi humidification se généralisant à tous versants (redoux et cumulus)...

Aperçu météo pour le jeudi 12 mars

	nuit	matin	après-midi	soir

Neige durant la nuit de mercredi à jeudi (10/15 cm vers les sommets). Vent sensible jeudi matin puis faiblissant ; l'après-midi éclaircies/redoux.

Pluie-Neige	1 300 m	1 300 m		
Iso 0 °C	1 700 m	1 700 m	2 200 m	2 400 m
Vent 1500 m	↓ 30 km/h	↙ 30 km/h	↓ 20 km/h	↙ 10 km/h
Vent 2000 m	↘ 45 km/h	↓ 35 km/h	↙ 25 km/h	↙ 10 km/h

Épaisseur de neige hors-piste

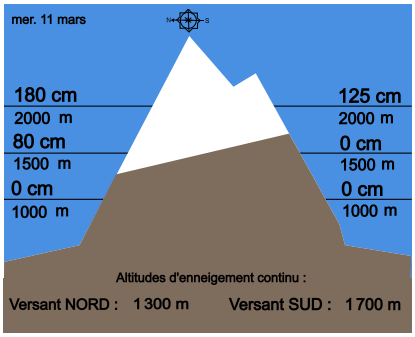

Précipitations à 1800 m

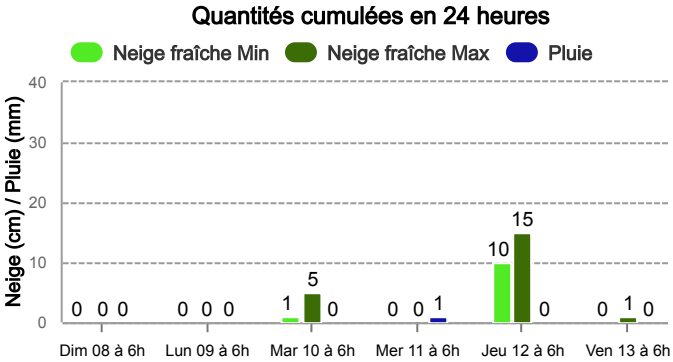

Tendance du vendredi 13 mars

2

Indice de risque limité

Risque d'avalanche en légère baisse vendredi. Regel au matin, vent de Sud-Sud-Ouest doux se renforçant vendredi soir, précédant un nouveau front neigeux... Samedi pas mal de neige fraîche attendue (30 cm), la situation nivologique va évoluer...

Pour consulter la vigilance en cours, veuillez vous rendre sur le site https://vigilance.meteofrance.fr/fr

Météo-France - 73 avenue de Paris, 94165 Saint-Mandé cedex - Contact : contact@meteo.fr

Rédigé par Météo-France avec la contribution des observateurs du réseau nivo-météorologiques. Partenariat : ANMSM (Maires de Stations de Montagne), DSF (Domaines Skiables de France), ADSP (Directeurs de Pistes et de la Sécurité des Stations de Sports d'Hiver) et autres acteurs de la montagne.

Bulletin neige & avalanches par téléphone au

0 892 68 10 20 Service 0,35 € / min + prix appel

RÉPUBLIQUE FRANÇAISE
Liberté Égalité Fraternité

METEO FRANCE
À VOS CÔTÉS, DANS UN CLIMAT QUI CHANGE

Bulletin d'estimation du risque d'avalanche

(valable en dehors des pistes balisées et ouvertes)

MASSIF : Vercors

Rédigé le mercredi 11 mars 2026 à 16h

Conditions nivo-météo des 7 derniers jours

	jeu. 05/03				ven. 06/03				sam. 07/03				dim. 08/03				lun. 09/03				mar. 10/03				mer. 11/03			
	03h	09h	15h	21h	03h	09h	15h	21h	03h	09h	15h	21h	03h	09h	15h	21h	03h	09h	15h	21h	03h	09h	15h	21h	03h	09h	15h	21h
Météo																												
Vent (km/h)	15	25	20	15	25	20	20	15	20	5	10	10	10	20	20	15	25	35	35	35	35	25	25	15	20	30	30	30
à 2000m																												
Vent (km/h)	10	15	10	10	15	5	10	5	5	5	5	5	10	10	20	15	20	30	30	30	30	20	20	15	20	25	30	20
à 1500m																												

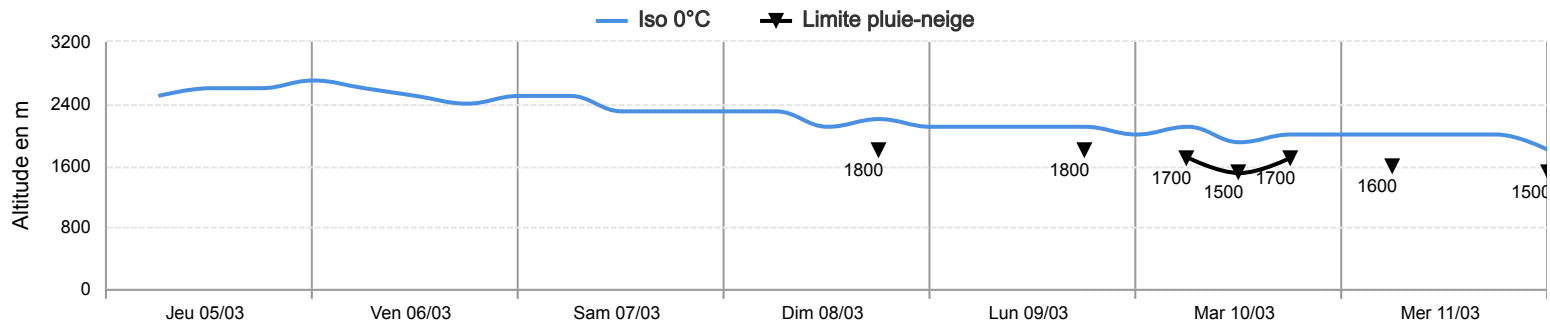

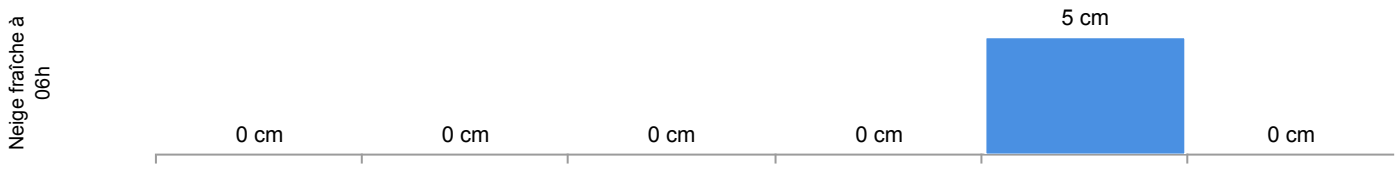

Risque d'avalanche	jeu. 05/03	ven. 06/03	sam. 07/03	dim. 08/03	lun. 09/03	mar. 10/03	mer. 11/03
	2	2	2	1	1	1	1

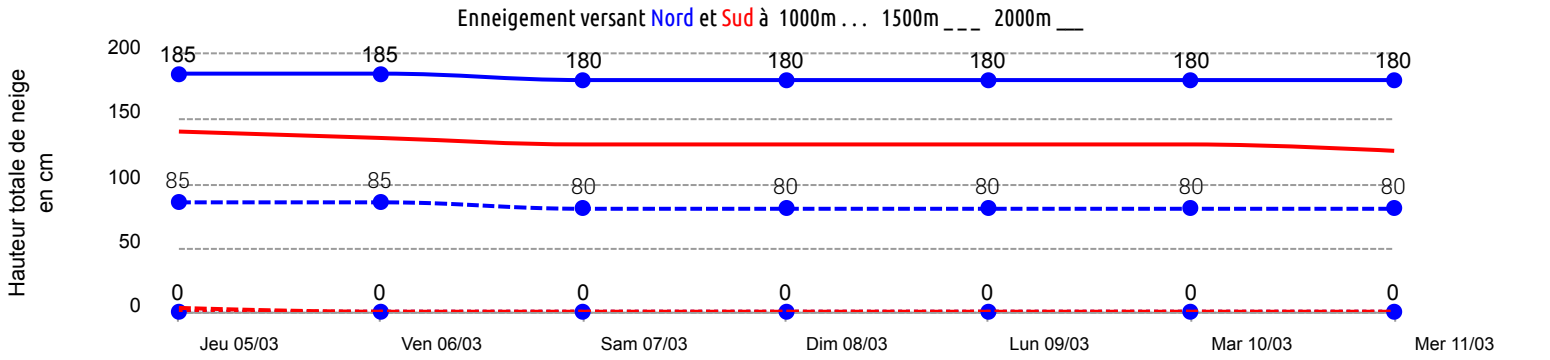

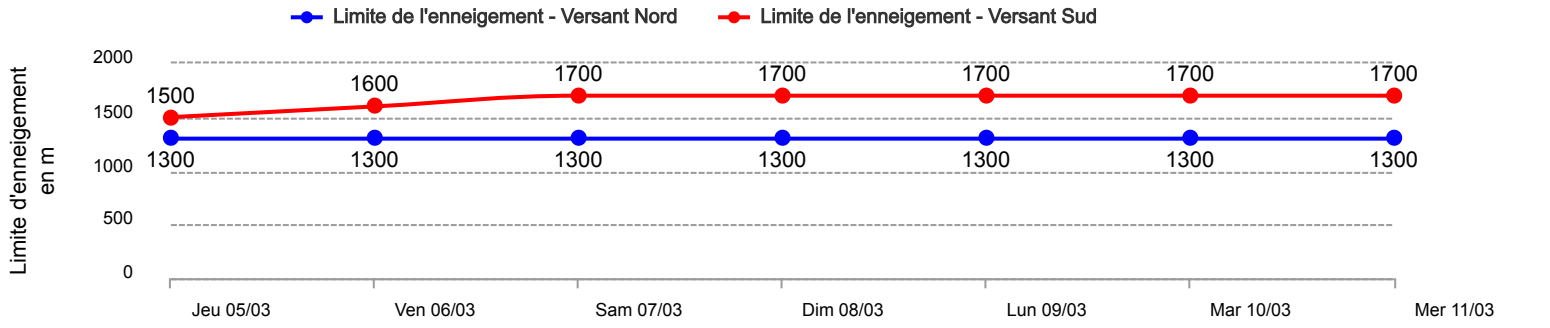

Pour consulter la vigilance en cours, veuillez vous rendre sur le site https://vigilance.meteofrance.fr/fr

Météo-France - 73 avenue de Paris, 94165 Saint-Mandé cedex - Contact : contact@meteo.fr

Rédigé par Météo-France avec la contribution des observateurs du réseau nivo-météorologiques. Partenariat : ANMSM (Maires de Stations de Montagne), DSF (Domaines Skiables de France), ADSP (Directeurs de Pistes et de la Sécurité des Stations de Sports d'Hiver) et autres acteurs de la montagne.

Bulletin neige & avalanches par téléphone au
0 892 68 10 20 Service 0,35 € / min + prix appel