GOBIERNO DE ESPAÑA
VICEPRESIDENCIA TERCERA DEL GOBIERNO
MINISTERIO PARA LA TRANSICIÓN ECOLÓGICA Y EL RETO DEMOGRÁFICO

Boletín de información nivológica y de peligro de aludes

Pirineo Catalán

aemet Agencia Estatal de Meteorología

jueves, 12 de marzo de 2026

Pronóstico hasta las 24 horas del viernes, día 13 de marzo

(Válido fuera de pistas de esquí balizadas y abiertas)

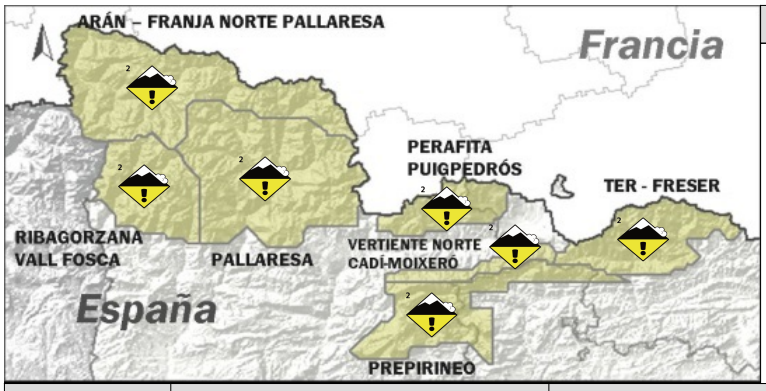

Problemas de aludes

Nieve húmeda

Placas de viento

Macizo	Peligro	Problemas de aludes, cota, orientación, tamaño	Innivación observada (m)
Arán - Franja norte Pallaresa	2 Limitado	Nieve húmeda: 2 (N, O, E, S) Placas de viento: 2100 (N, O, E, S)	2026-03-12 N / S Cota más baja caras N
Ribagorzana - Vall Fosca	2 Limitado	Nieve húmeda: 2 (N, O, E, S) Placas de viento: 2100 (N, O, E, S)	2026-03-12 N / S Cota más baja caras N
Pallaresa	2 Limitado	Nieve húmeda: 2 (N, O, E, S) Placas de viento: 2400 (N, O, E, S)	2026-03-12 N / S Cota más baja caras N

AEMET. Se autoriza la reproducción de su contenido citando la fuente.

Boletín de información nivológica y de peligro de aludes

Pirineo Catalán

Perafita - Puigpedrós	2 **Limitado**	**Nieve húmeda**  **Placas de viento** 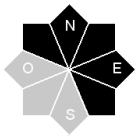 	2026-03-12 Cota más baja caras N
Ter - Freser	2 **Limitado**	**Nieve húmeda**  **Placas de viento** 	2026-03-12 Cota más baja caras N
Vertiente norte Cadí - Moixeró	2 **Limitado**	**Nieve húmeda** 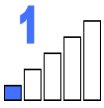 **Placas de viento** 	2026-03-12 Cota más baja caras N
Prepirineo	2 **Limitado**	**Nieve húmeda**  **Placas de viento** 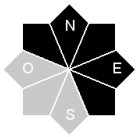 	2026-03-12 Cota más baja caras N

Estado del manto y observaciones recientes

Ayer se produjeron precipitaciones débiles, que fueron en forma de nieve por encima de 2100 metros, pudiendo dejar a lo sumo 1-4 cm nuevos. Por debajo la lluvia favoreció un descenso en los espesores de algunos pocos centímetros y el posterior rehielo nocturno.

El manto es continuo, en general, desde cotas medias, mostrando cierta disimetría entre solanas y umbrías. Pese a la mengua progresiva, los espesores siguen siendo importantes y se encuentran muy por encima de lo que cabe esperar a estas alturas de la temporada,

AEMET. Se autoriza la reproducción de su contenido citando la fuente.

superándose, por encima de los 2100 metros, los 120 a 200 cm, sensiblemente más en hoyas, ventisqueros y otras zonas propensas a la acumulación.

En cotas medias y bajas, así como en solanas a mayor altitud, la nieve está humedecida en profundidad y las heladas tienden a encostrarla durante las primeras horas. En umbrías de cotas altas se mantiene seca y venteada, con capas débiles enterradas recientemente y otras persistentes en profundidad, éstas últimas generalmente inactivas.

Evolución del manto y peligro de aludes para el viernes, día 13

Problemas de nieve húmeda y placas de viento.

El ascenso térmico y la insolación tenderán a ir humedeciendo el manto desde media mañana, reblandeciendo la nieve y fundiendo las costras de rehielo que puedan formase como consecuencia de las heladas nocturnas. En consecuencia seguirán siendo probables las purgas de nieve húmeda en pendientes con suficiente inclinación, sobre todo en áreas de solana y durante las horas centrales del día, que en general serán de tamaño pequeño (1, riesgo de caída) o mediano (2, capaz de enterrar a una persona). No se descartan deslizamientos basales en zonas con superficies herbosas o de roca lisa, susceptibles de generar aludes también pequeños o medianos.

El viento fuerte del oeste y suroeste en cotas altas podrá movilizar nieve reciente y formar nuevas placas de viento pequeñas, depositándose en umbrías sobre escarcha superficial y/o capas débiles de facetas enterradas. Asimismo, es posible que algunas antiguas placas de viento localizadas en zonas protegidas aún permanezcan activas. Todas ellas podrán fracturar ante una sobrecarga débil, como es el paso de un esquiador, provocando aludes de dimensiones pequeñas o medianas en zonas de mayor acumulación.

Predicción meteorológica para el viernes, día 13

Poco nuboso o despejado, tendiendo a muy nuboso o cubierto al final del día. No se descartan precipitaciones débiles ocasionales a últimas horas. Cota de nieve: 1800-2000 metros. Temperaturas mínimas sin cambios o en ligero descenso, que podrán darse al final del día en algunas zonas. Máximas en ligero ascenso. Heladas débiles, moderadas en cotas altas. Soplarán vientos del oeste y suroeste, inicialmente flojos y a partir de mediodía tenderán a ser moderados, en cotas altas fuertes.

Datos en la atmósfera libre:

Altitud de la isoterma de 0 ºC: 2400 m
Altitud de la isoterma de -10 ºC: 4100 m

Viento a 1500 m: SW 10 km/h
Viento a 3000 m: W 30 km/h

Evolución para el sábado día 14

Nivel de peligro en ascenso por las nevadas, vientos fuertes y el descenso de las temperaturas, con problemas de nieve reciente y placas de viento.

AEMET. Se autoriza la reproducción de su contenido citando la fuente.

Boletín de información nivológica y de peligro de aludes

Pirineo Catalán

Escala europea de peligro de aludes

Débil | Limitado | Notable | Fuerte | Muy Fuerte

Problemas de aludes

Nieve reciente | Placas de viento | Capas débiles persistentes | Nieve húmeda | Deslizamientos basales | Sin problema evidente

Nota1: Se recuerda que, siempre que haya nieve, la ausencia total de peligro no existe. Hay que tener presente que en circunstancias desfavorables, con aludes de tamaño 1 (alud pequeño o colada) y tamaño 2 (alud mediano), se pueden sufrir severos daños personales.

Nota2: Los BPA se elaboran en base a información meteorológica así como al estado del manto nivoso a través de sondeos puntuales. Se advierte a los usuarios de la variabilidad de esta información al extrapolarla a zonas extensas de montaña. Por ello, AEMET no se hace responsable de su uso para la toma de decisiones que conciernen a la seguridad personal, ni de los riesgos físicos o materiales de ellas derivadas.

AEMET. Se autoriza la reproducción de su contenido citando la fuente.