GOBIERNO DE ESPAÑA
VICEPRESIDENCIA TERCERA DEL GOBIERNO
MINISTERIO PARA LA TRANSICIÓN ECOLÓGICA Y EL RETO DEMOGRÁFICO

Boletín de información nivológica y de peligro de aludes

Pirineo Navarro y Aragonés

aemet Agencia Estatal de Meteorología

jueves, 12 de marzo de 2026

Pronóstico hasta las 24 horas del viernes, día 13 de marzo

(Válido fuera de pistas de esquí balizadas y abiertas)

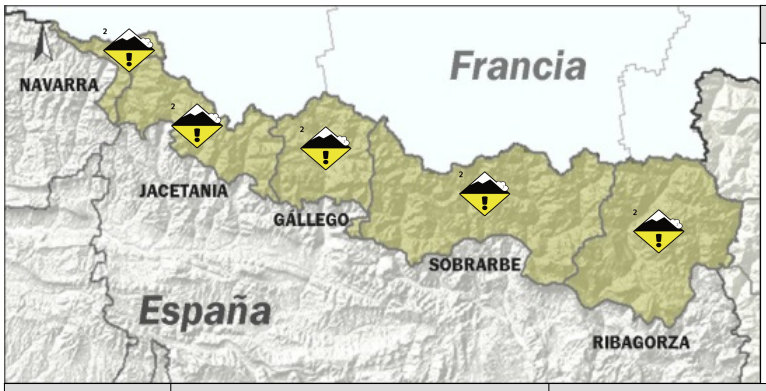

Problemas de aludes

Nieve húmeda

Placas de viento

Macizo	Peligro	Problemas de aludes, cota, orientación, tamaño	Innivación observada (m)
Navarra	2 Limitado	Nieve húmeda: 2 — Placas de viento: 2, 2200	2026-03-12 Cota más baja caras N
Jacetania	2 Limitado	Nieve húmeda: 2 — Placas de viento: 2, 2200	2026-03-12 Cota más baja caras N
Gállego	2 Limitado	Nieve húmeda: 2 — Placas de viento: 2, 2200	2026-03-12 Cota más baja caras N

AEMET. Se autoriza la reproducción de su contenido citando la fuente.

Boletín de información nivológica y de peligro de aludes

Pirineo Navarro y Aragonés

Sobrarbe	**Limitado**	**Nieve húmeda** 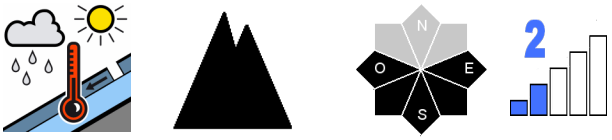 **Placas de viento** 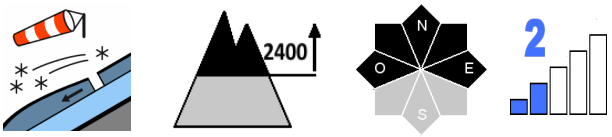	2026-03-12 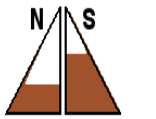 Cota más baja caras N
Ribagorza	**Limitado**	**Nieve húmeda** **Placas de viento** 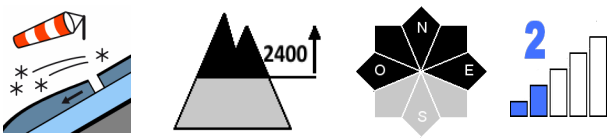	2026-03-12 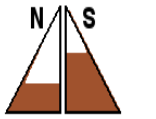 Cota más baja caras N

Estado del manto y observaciones recientes

Ayer se produjeron precipitaciones débiles, en torno a 2-10 l/m2 en la mitad occidental, muy escasas en la oriental. Fueron en forma de nieve por encima de 2100 metros, y por debajo, la lluvia favoreció un descenso en los espesores de algunos pocos centímetros y el posterior rehielo nocturno.

El manto es continuo desde 1400 metros en caras norte y 1600 en caras sur aproximadamente. Pese a la mengua progresiva, los espesores siguen siendo importantes, rondando los 90-140 cm en torno a 1800 metros y los 130-200 cm por encima de 2100 metros, pudiendo ser sensiblemente mayores en ventisqueros, hoyas y otras zonas propensas a la acumulación.

En general la nieve está humedecida hasta 2300 metros en umbrías y prácticamente hasta las cumbres en solanas, sumidas hace días en el ciclo de fusión y rehielo. Éste suele ser moderado y no tarda en ablandarse con la insolación. En umbrías de cotas altas hay presencia de escarcha en superficie y las capas de nieve reciente que se han ido acumulando durante los últimos días se mantienen frías y secas. Éstas capas y algunas placas de viento residuales cerca de collados y cordales pueden descansar sobre estratos frágiles que se han ido facetando, especialmente bajo las deposiciones de polvo sahariano de la semana pasada. También es posible encontrar en las umbrías capas débiles persistentes en profundidad y que se encuentran, por lo general, inactivas.

Un test realizado ayer en el entorno del refugio de Ángel Orús (2150 m, N) presentaba fractura de tipo difícil y sin propagación. Se han observado algunas purgas naturales en las últimas 24h.

AEMET. Se autoriza la reproducción de su contenido citando la fuente.

Evolución del manto y peligro de aludes para el viernes, día 13

Problemas de nieve húmeda y deslizamientos basales. Problema de placas de viento en cotas altas.

El ascenso térmico y la insolación tenderán a ir humedeciendo el manto desde media mañana, reblandeciendo la nieve y fundiendo las costras de rehielo que puedan formase como consecuencia de las heladas nocturnas. En consecuencia seguirán siendo probables las purgas de nieve húmeda, sobre todo en áreas de solana y durante las horas centrales del día, que en general serán de tamaño pequeño (1, riesgo de caída) o mediano (2, capaz de enterrar a una persona). También podrían darse deslizamientos basales en zonas con superficies herbosas o de roca lisa con la suficiente inclinación, generalmente en cotas bajas y medianías de solanas, susceptibles de generar aludes hasta de tamaño grande (3, capaz de enterrar a un grupo de personas) localmente.

El viento fuerte del oeste y suroeste en cotas altas podrá movilizar nieve reciente y formar nuevas placas de viento pequeñas, depositándose en umbrías sobre escarcha superficial y/o capas débiles de facetas enterradas. Asimismo, es posible que algunas antiguas placas de viento localizadas en zonas protegidas aún permanezcan activas. Todas ellas podrán fracturar ante una sobrecarga débil, como es el paso de un esquiador, provocando aludes de dimensiones pequeñas o medianas en zonas de mayor acumulación.

Predicción meteorológica para el viernes, día 13

Poco nuboso o despejado, tendiendo a muy nuboso o cubierto al final del día. Se esperan precipitaciones débiles o localmente moderadas a últimas horas en Navarra y los macizos occidentales de Aragón. Cota de nieve: 1800-2000 metros. Temperaturas mínimas en ligero o moderado descenso, que se darán al final del día. Máximas sin cambios. Heladas débiles, moderadas en cotas altas. Soplarán vientos flojos o moderados del oeste y sudoeste, tendiendo a arreciar por la noche. Será más intenso en cotas altas donde soplará fuerte a partir de mediodía.

Datos en la atmósfera libre:

Altitud de la isoterma de 0 ºC: 2300 m
Altitud de la isoterma de -10 ºC: 4000 m

Viento a 1500 m: SW 15 km/h
Viento a 3000 m: SW 40 km/h

Evolución para el sábado día 14

Nivel de peligro en ascenso por las nevadas, vientos fuertes y el descenso de las temperaturas, con problemas de nieve reciente y placas de viento.

(Información elaborada a partir de los datos recibidos de los refugios de Linza, Lizara, Panticosa, Bachimaña, Góriz, Pineta, Estós, Angel Orús, La Renclusa, Cap de Llauset y Belagua, de las estaciones de esquí de Candanchú, Formigal y Panticosa (lagos), de la estación de esquí de fondo de Llanos del Hospital y de Ordesa Pradera)

AEMET. Se autoriza la reproducción de su contenido citando la fuente.

Boletín de información nivológica y de peligro de aludes

Pirineo Navarro y Aragonés

Escala europea de peligro de aludes

Débil | Limitado | Notable | Fuerte | Muy Fuerte

Problemas de aludes

Nieve reciente | Placas de viento | Capas débiles persistentes | Nieve húmeda | Deslizamientos basales | Sin problema evidente

Nota1: Se recuerda que, siempre que haya nieve, la ausencia total de peligro no existe. Hay que tener presente que en circunstancias desfavorables, con aludes de tamaño 1 (alud pequeño o colada) y tamaño 2 (alud mediano), se pueden sufrir severos daños personales.

Nota2: Los BPA se elaboran en base a información meteorológica así como al estado del manto nivoso a través de sondeos puntuales. Se advierte a los usuarios de la variabilidad de esta información al extrapolarla a zonas extensas de montaña. Por ello, AEMET no se hace responsable de su uso para la toma de decisiones que conciernen a la seguridad personal, ni de los riesgos físicos o materiales de ellas derivadas.

AEMET. Se autoriza la reproducción de su contenido citando la fuente.