Freitag 13.03.2026

Veröffentlicht am 12.03.2026 um 17:00

Vormittag

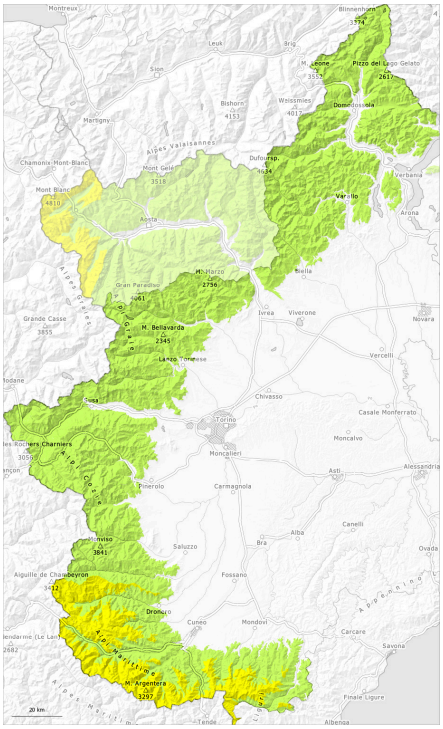

Nachmittag

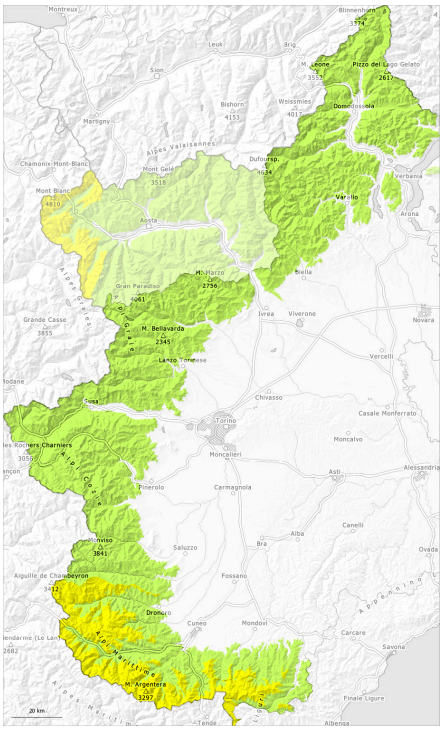

1	2	3	4	5
gering	mäßig	erheblich	groß	sehr groß

Gefahrenstufe 2 - Mäßig

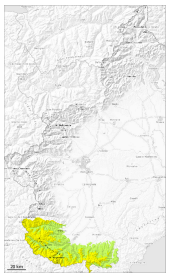

2300m

Tendenz: Lawinengefahr steigt
am Samstag, den 14.03.2026

Triebschnee

2300m

Nassschnee

2400m

Triebschnee und Nassschnee sind die Hauptgefahr.

In den letzten Tagen fielen oberhalb von rund 1800 m bis zu 20 cm Schnee, lokal auch mehr. Gestern fiel wenig Schnee.
Mit Neuschnee und teils mäßigem Wind aus westlichen Richtungen entstanden bis am Morgen vor allem in Kammlagen, Rinnen und Mulden sowie in hohen Lagen teils störanfällige Triebschneeansammlungen. Vor allem in den Hauptniederschlagsgebieten und an sehr steilen Hängen sind kleine und mittlere Lawinen möglich. Sie können vereinzelt schon von einzelnen Wintersportlern ausgelöst werden.
Mit der Sonneneinstrahlung sind unterhalb von rund 2600 m kleine und mittlere feuchte und nasse Lawinen möglich. Dies vor allem aus steilen sonnenbeschienenen noch nicht entladenen Einzugsgebieten in mittleren Lagen. Schon ein kleiner Rutsch kann Personen mitreißen und zum Absturz bringen.

Schneedecke

Gefahrenmuster gm.6: lockerer schnee und wind

Am Dienstag fielen oberhalb von rund 1600 m verbreitet 15 bis 20 cm Schnee, lokal bis zu 30 cm.
Föhngebiete des Südens: Am Donnerstag fielen oberhalb von rund 1800 m 2 bis 5 cm Schnee, lokal bis zu 10 cm. Der Neuschnee ist unterhalb von rund 2200 m stellenweise schlecht mit dem Altschnee verbunden.
Mittlere und hohe Lagen: Der Neuschnee liegt vor allem an den Expositionen Ost über Süd bis West auf einer Kruste. Der mäßige Wind hat den Neuschnee verfrachtet.

Verbreitet liegt noch viel Schnee.

Tendenz

Anstieg der Lawinengefahr mit dem Schneefall.

Gefahrenstufe 1 - Gering

AM:

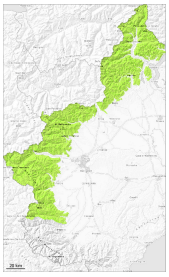

1

Tendenz: Lawinengefahr steigt
am Samstag, den 14.03.2026

PM:

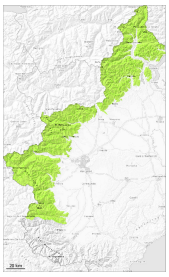

1

Tendenz: Lawinengefahr steigt
am Samstag, den 14.03.2026

Nassschnee

N S

2400m

Die Tourenverhältnisse sind meist günstig.

In den letzten Tagen fielen lokal oberhalb von rund 2000 m bis zu 10 cm Schnee, lokal auch weniger. Der Neuschnee überlagert eine recht günstige Altschneedecke.
Mit der Sonneneinstrahlung sind einzelne kleine feuchte und nasse Lawinen möglich. Dies vor allem an extrem steilen Sonnenhängen sowie im felsdurchsetzten Steilgelände.

Vor allem in den Föhngebieten des Nordens sind die Gefahrenstellen etwas häufiger und die Gefahr höher. Schon ein kleiner Rutsch kann Personen mitreißen und zum Absturz bringen.

Schwachschichten im Altschnee können besonders in der Höhe vereinzelt und meist mit großer Zusatzbelastung ausgelöst werden. Dies vor allem an extrem steilen Schattenhängen oberhalb von rund 2700 m.

Schneedecke

Gefahrenmuster gm.10: frühjahrssituation

Am Dienstag fielen oberhalb von rund 1600 m 5 bis 15 cm Schnee. Föhngebiete des Nordens Am Donnerstag fielen oberhalb von rund 1800 m 2 bis 5 cm Schnee.
Die Altschneedecke ist gut verfestigt, mit einer aus lockerem Schnee bestehenden Oberfläche, die auf einer oft tragfähigen Schmelzharschkruste liegt.
Sonne und Wärme führen ab dem Mittag vor allem an steilen Sonnenhängen in mittleren Lagen zu einer allmählichen Anfeuchtung der Schneedecke.
Mittlere und hohe Lagen: In der Schneedecke sind besonders an Nordwest-, Nord- und Nordosthängen einzelne Schwachschichten vorhanden.
Vor allem in Gipfellagen liegt wenig Schnee.

Tendenz

Anstieg der Lawinengefahr mit dem Schneefall.