Freitag 13.03.2026

Veröffentlicht am 12.03.2026 um 17:00

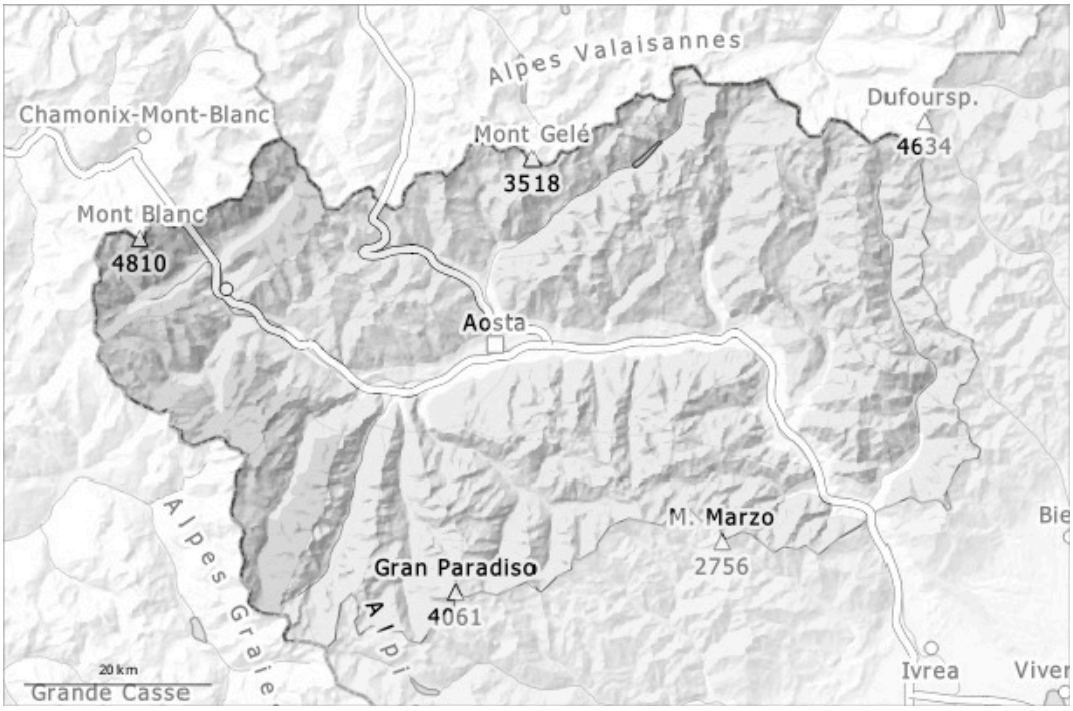

1	2	3	4	5
gering	mäßig	erheblich	groß	sehr groß

Gefahrenstufe 2 - Mäßig

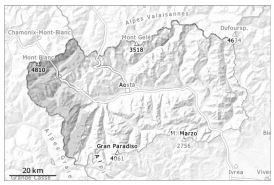

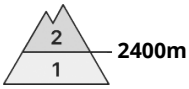

Tendenz: Lawinengefahr steigt
am Samstag, den 14.03.2026

Triebschnee

2400m

Die Tourenverhältnisse bleiben mehrheitlich günstig.

Die frischeren Triebschneeansammlungen bilden die Hauptgefahr. Sie sind gut erkennbar aber vorsichtig zu beurteilen.

Es sind meist kleine feuchte Rutsche im Tagesverlauf möglich, v.a. an extrem steilen Sonnenhängen bei Sonneneinstrahlung.
Schwachschichten im Altschnee können vereinzelt ausgelöst werden. Diese Gefahrenstellen liegen vor allem an sehr steilen Schattenhängen oberhalb von rund 2500 m sowie an Übergängen von wenig zu viel Schnee.

Schneedecke

Gefahrenmuster gm.6: lockerer schnee und wind

Am Dienstag fielen gebietsweise oberhalb von rund 2200 m 2 bis 10 cm Schnee. In der Nacht fielen gebietsweise oberhalb von rund 2200 m 5 bis 10 cm Schnee.
Der obere Teil der Schneedecke ist weitgehend stabil, mit einer oft tragfähigen Schmelzharschkruste an der Oberfläche.
Besonders steile Schattenhänge hohe Lagen und Hochgebirge: Oberflächlich sehr verdichteter Schnee, der durch die stürmischen Winde Ende Februar stabilisiert wurde, oder bestehend aus facettierten Kristallen und lokal aus Schnee mit schwacher Kohäsion und Oberflächenreif. In der Altschneedecke sind dort Schwachschichten vorhanden.
In Kamm- und Passlagen sowie in hohen Lagen liegen je nach Windeinfluss sehr unterschiedliche Schneehöhen.

Tendenz

Verbreitet Neuschnee: Der Neuschnee sowie die verbreitet entstehenden, teils großen Triebschneeansammlungen bilden die Hauptgefahr.

Gefahrenstufe 1 - Gering

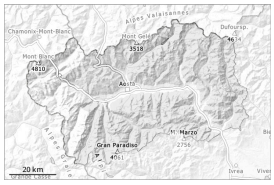

1

Tendenz: Lawinengefahr steigt
am Samstag, den 14.03.2026

Die Tourenverhältnisse bleiben mehrheitlich günstig.

Die Schneedecke bleibt allgemein stabil.

Mit dem Neuschnee sind kleine feuchte Rutsche im Tagesverlauf möglich, v.a. an sehr steilen Sonnenhängen bei Sonneneinstrahlung.
Schwachschichten im Altschnee können sehr vereinzelt ausgelöst werden. Diese Gefahrenstellen liegen vor allem an extrem steilen Schattenhängen oberhalb von rund 2400 m sowie an Übergängen von wenig zu viel Schnee.

Schneedecke

Es fielen gebietsweise oberhalb von rund 2200 m 2 bis 5 cm Schnee, lokal auch mehr.
Der obere Teil der Schneedecke ist weitgehend stabil, mit einer oft tragfähigen Schmelzharschkruste an der Oberfläche. Dort besteht im Steilgelände Absturzgefahr.
Besonders steile Schattenhänge hohe Lagen und Hochgebirge: Oberflächlich sehr verdichteter Schnee, der durch die stürmischen Winde Ende Februar stabilisiert wurde, oder bestehend aus facettierten Kristallen und lokal aus Schnee mit schwacher Kohäsion und Oberflächenreif. In der Altschneedecke sind dort Schwachschichten vorhanden.
In Kamm- und Passlagen sowie in hohen Lagen liegen je nach Windeinfluss sehr unterschiedliche Schneehöhen.

Tendenz

Neuschnee mit größeren Mengen im Südosten der Region: Der Neuschnee sowie die verbreitet entstehenden, teils großen Triebschneeansammlungen bilden die Hauptgefahr.