Venerdì 13.03.2026

Pubblicato il 12.03.2026 alle ore 17:00

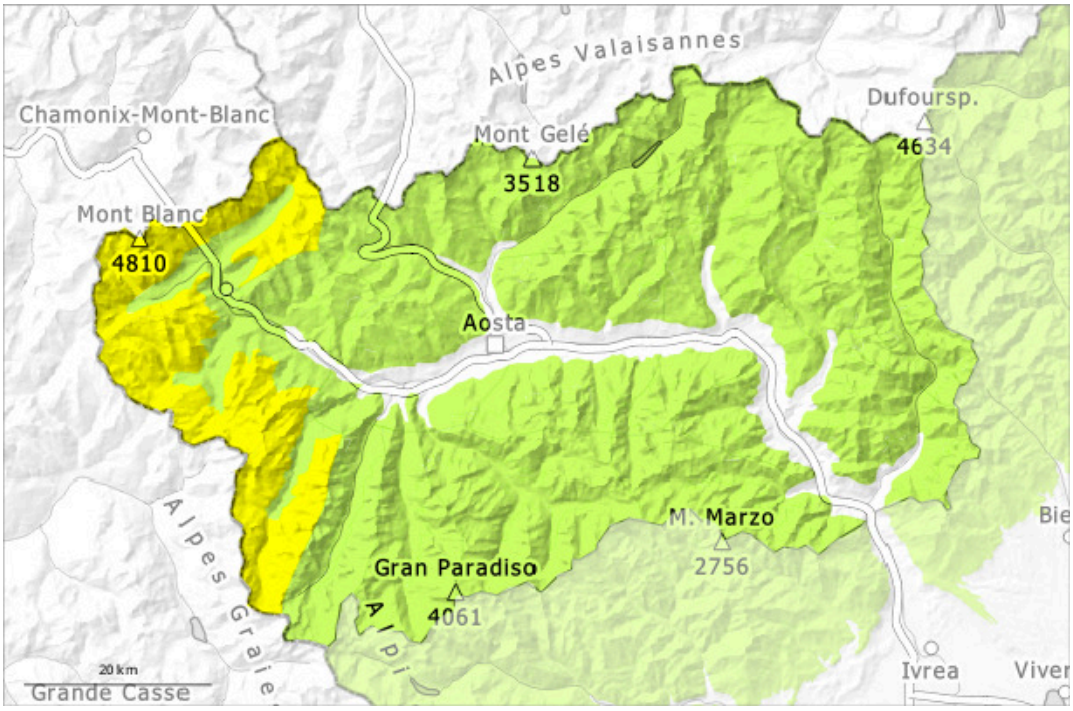

1	2	3	4	5
debole	moderato	marcato	forte	molto forte

Grado di pericolo 2 - Moderato

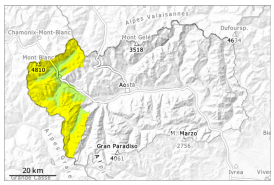

Tendenza: pericolo valanghe in aumento
per Sabato il 14.03.2026

Lastrone da vento

Le condizioni per le escursioni rimangono per lo più favorevoli.

Gli ultimi accumuli di neve ventata rappresentano la principale fonte di pericolo. Essi sono ben individuabili ma devono essere valutati con attenzione.

Sono possibili colate umide nel corso della giornata per lo più di piccole dimensioni, principalmente sui pendii soleggiati ripidi estremi in seguito all'irradiazione solare.
Gli strati deboli presenti nella neve vecchia possono distaccarsi a livello isolato. Questi punti pericolosi si trovano soprattutto sui pendii ombreggiati molto ripidi al di sopra dei 2500 m circa come pure nelle zone di passaggio da poca a molta neve.

Manto nevoso

Situazione tipo st.6: neve a debole coesione e vento

In alcune regioni martedì sono caduti da 2 a 10 cm di neve al di sopra dei 2200 m circa. In alcune regioni durante la notte sono caduti da 5 a 10 cm di neve al di sopra dei 2200 m circa.
La parte superiore del manto nevoso è per lo più stabile, con una crosta da rigelo spesso portante in superficie.
Principalmente sui pendii ripidi ombreggiati ad alta quota e in alta montagna: Neve superficialmente molto compattata e stabilizzata dai venti tempestosi di fine febbraio o composta da cristalli sfaccettati e localmente da neve a debole coesione e brina di superficie. Qui, all'interno del manto di neve vecchia si trovano strati fragili.
Nelle zone in prossimità delle creste e dei passi così come ad alta quota l'innevamento è estremamente variabile a seconda dell'azione del vento.

Tendenza

Neve fresca in molte regioni: La neve fresca così come gli accumuli di neve ventata che si formeranno in molti punti e in alcuni punti di grandi dmensioni rappresentano la principale fonte di pericolo.

Grado di pericolo 1 - Debole

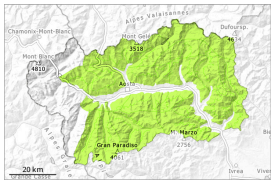

1

Tendenza: pericolo valanghe in aumento
per Sabato il 14.03.2026

Le condizioni per le escursioni rimangono per lo più favorevoli.

Il manto nevoso rimane stabile a livello generale.

Con la neve fresca, sono possibili colate umide nel corso della giornata di piccole dimensioni, principalmente sui pendii soleggiati molto ripidi in seguito all'irradiazione solare.
Gli strati deboli presenti nella neve vecchia possono distaccarsi a livello molto isolato. Questi punti pericolosi si trovano soprattutto sui pendii ombreggiati ripidi estremi al di sopra dei 2400 m circa come pure nelle zone di passaggio da poca a molta neve.

Manto nevoso

In alcune regioni sono caduti da 2 a 5 cm di neve al di sopra dei 2200 m circa, localmente anche di più.
La parte superiore del manto nevoso è per lo più stabile, con una crosta da rigelo spesso portante in superficie. Qui sussiste un pericolo di caduta nelle zone ripide.
Principalmente sui pendii ripidi ombreggiati ad alta quota e in alta montagna: Neve superficialmente molto compattata e stabilizzata dai venti tempestosi di fine febbraio o composta da cristalli sfaccettati e localmente da neve a debole coesione e brina di superficie. Qui, all'interno del manto di neve vecchia si trovano strati fragili.
Nelle zone in prossimità delle creste e dei passi così come ad alta quota l'innevamento è estremamente variabile a seconda dell'azione del vento.

Tendenza

Neve fresca con quantitativi maggiori nel sud-est della Regione: La neve fresca così come gli accumuli di neve ventata che si formeranno in molti punti e in alcuni punti di grandi dmensioni rappresentano la principale fonte di pericolo.