ICGC Institut Cartogràfic i Geològic de Catalunya

Servei Meteorològic de Catalunya meteo.cat

Boletín de peligro de aludes para el Pirineo de Catalunya
Del 12/03/2026 al 13/03/2026

(Válido fuera pistas de esquí y zonas no controladas)

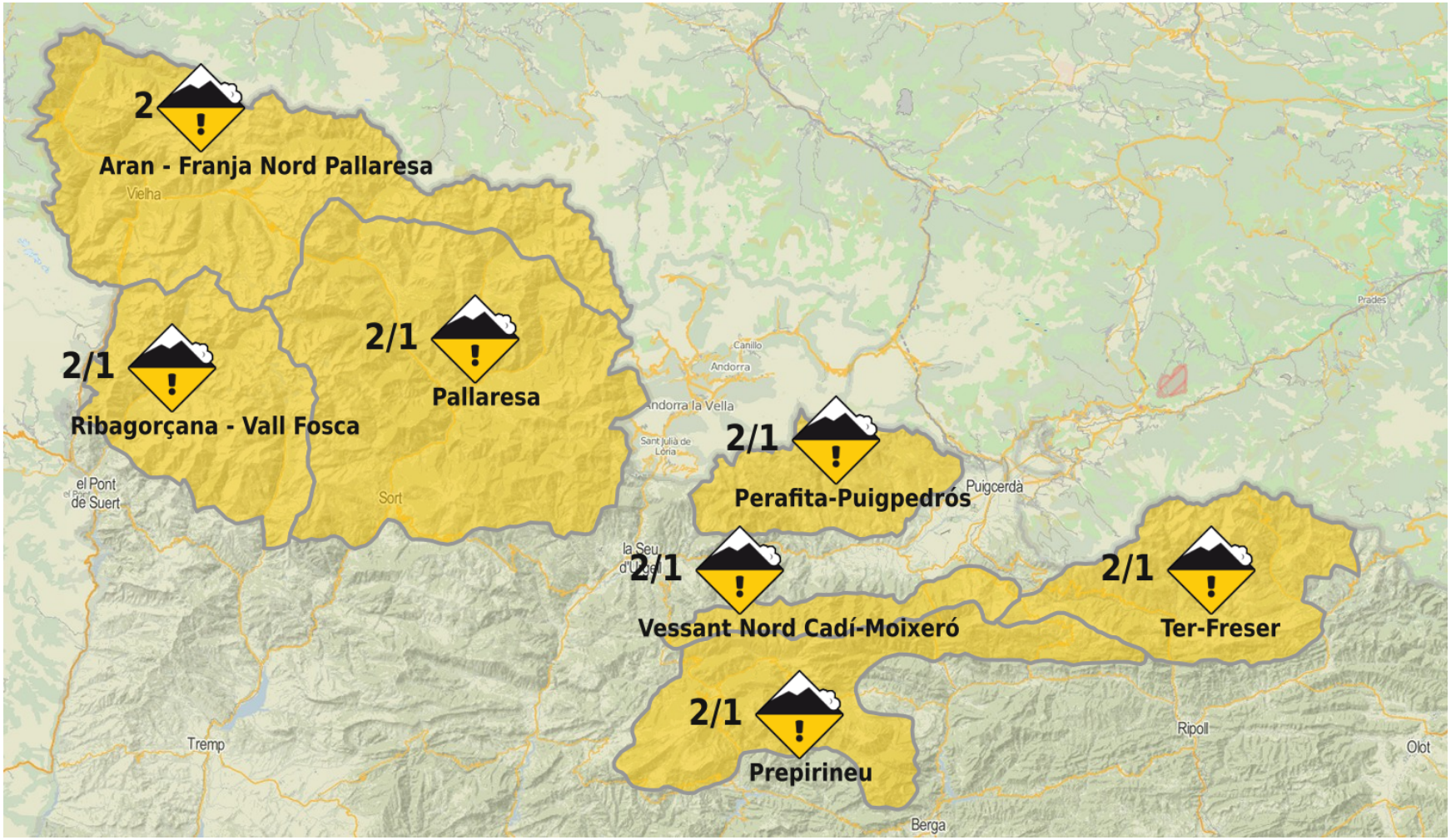

5 MUY FUERTE	4 FUERTE	3 NOTABLE	2 LIMITADO	1 DÉBIL

ICGC Institut Cartogràfic i Geològic de Catalunya

meteo.cat Servei Meteorològic de Catalunya

Boletín de peligro de aludes Aran - Franja Nord Pallaresa Del 12/03/2026 al 13/03/2026

(Válido fuera pistas de esquí y zonas no controladas)

LIMITADO (2)

Situación primaria

Nieve venteada

Distribución

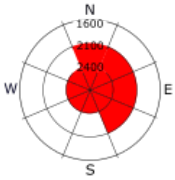

Tamaño

Origen

Tendencia

Situación secundaria

Nieve húmeda

Distribución

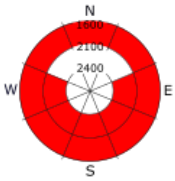

Tamaño

Origen

Tendencia

Estado del manto nivoso

Se están produciendo, al paso de personas, aludes de placa de tamaño 1 (pequeño, con capacidad de derribarnos y arrastrarnos), de nieve transportada por el viento y por capas débiles enterradas. Son placas blandas y se han formado por la nevada con viento de NW del miércoles (unos 5 cm); el viernes soplará viento del SW que transportará nieve de cimas y cordales y formará nuevas placas de viento en orientaciones NW, N y NE. Las capas débiles persistentes enterradas son facetas formadas por encima de la costra marrón y, más superficialmente, escarcha enterrada bajo la débil nevada del miércoles. A medida que el grosor de nieve se incremente por la nieve venteada, algún alud de placa será de tamaño 2 (mediano, con capacidad de enterrar a una persona). A partir del mediodía, con la insolación y el aumento térmico, el manto se irá humedeciendo en solanas y orientaciones E y W de cotas bajas y medias, y caerán aludes de nieve húmeda de tamaño 1, sobre todo a partir de puntos rocosos.

Distribución del manto nivoso

Hay nieve por encima de unos 1.400-1-500 m en umbrías y 1.700 m en solanas. Los espesores a unos 2.200 m son superiores a los normales en la Franja Norte de la Pallaresa y en la mitad sur del Aran donde rondan los 180-220 cm. En la mitad norte de Arán hay unos 120-140 cm de grosor total.

Tendencia para las próximas 48-72h

Desde la noche del viernes y durante el fin de semana se impondrá el problema de la nieve reciente y de placas de viento. Peligro en AUMENTO.

El próximo boletín será emitido el día 2026-03-13

5 MUY FUERTE	4 FUERTE	3 NOTABLE	2 LIMITADO	1 DÉBIL

EAWS EUROPEAN AVALANCHE WARNING SERVICES

ICGC Institut Cartogràfic i Geològic de Catalunya

meteo.cat Servei Meteorològic de Catalunya

Boletín de peligro de aludes Ribagorçana - Vall Fosca Del 12/03/2026 al 13/03/2026

(Válido fuera pistas de esquí y zonas no controladas)

LIMITADO (2) a partir de mediodía. DÉBIL (1) hasta mediodía.

Situación primaria

Nieve venteada

Distribución

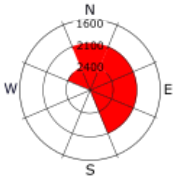

Tamaño

Origen

Tendencia

Situación secundaria

Nieve húmeda

Distribución

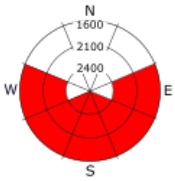

Tamaño

Origen

Tendencia

Estado del manto nivoso

El manto se presenta bastante asentado, con costras internas, excepto en cotas altas umbrías donde encima de la costra marrón (polvo sahariana) del 5 de marzo ya se observan algunas facetas que colapsan y generan pequeñas roturas de nieve placada. En superficie hay escarcha; el viernes quedará tapada bajo pequeñas placas de viento en las cotas más altas a medida que el viento vaya incrementado de velocidad, en orientaciones NE, E, SE y S. Así, a lo largo del viernes podrá haber algún alud de placa de viento al paso de personas, de tamaño 1 (pequeño, con capacidad de derribarnos y arrastrarnos), bajo collados y cordales en las orientaciones indicadas. A partir del mediodía, con la insolación y el aumento térmico, el manto se irá humedeciendo en solanas y orientaciones E y W de cotas bajas y medias, siendo probables caída de bolas y aludes de nieve húmeda de tamaño 1, pequeño, de debajo de rocas y de árboles.

Distribución del manto nivoso

Hay nieve en el suelo a 1.600 m en terreno umbrío, y por encima de unos 1.800 m en laderas soleadas. El manto es esquiable por encima de unos 1.800-1.900 m en umbrías. Los grosores alcanzan los 100-130 cm a unos 2.200 m. Estos valores son superiores a los normales para la época.

Tendencia para las próximas 48-72h

Desde la noche del viernes y el fin de semana se impondrá el problema de placas de viento; serán abundantes y frágiles. Peligro en AUMENTO.

El próximo boletín será emitido el día 2026-03-13

5 MUY FUERTE	4 FUERTE	3 NOTABLE	2 LIMITADO	1 DÉBIL

EAWS EUROPEAN AVALANCHE WARNING SERVICES

ICGC Institut Cartogràfic i Geològic de Catalunya

Servei Meteorològic de Catalunya

Boletín de peligro de aludes Pallaresa
Del 12/03/2026 al 13/03/2026

(Válido fuera pistas de esquí y zonas no controladas)

LIMITADO (2) a partir de mediodía. DÉBIL (1) hasta mediodía.

Situación primaria

Nieve húmeda

Distribución

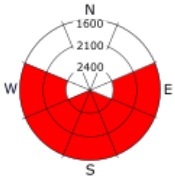

Tamaño

Origen

Tendencia

Situación secundaria

Nieve venteada

Distribución

Tamaño

Origen

Tendencia

Estado del manto nivoso

El manto se presenta bastante asentado, con costras internas, excepto en cotas altas umbrías donde encima de la costra marrón (polvo sahariano) del 5 de marzo ya se observan algunas facetas pero sin capacidad de propagar fracturas de momento. Hasta la mañana encontraremos unas condiciones bastante estables del manto por rehielo nocturno. A partir del mediodía, con el aumento térmico, el manto se irá humedeciendo en solanas y orientaciones E y W de cotas bajas y medias, y serán probables caída de bolas y aludes de nieve húmeda de tamaño 1 (pequeños, con capacidad de hacernos caer y arrastrarnos) en laderas de fuerte pendiente, más frecuente bajo resaltos rocosos y árboles. Se irán formando pequeñas placas de viento en las cotas más altas a medida que el viento vaya incrementado de velocidad, en orientaciones NE, E, SE y S. A lo largo del viernes podría haber algún alud de placa de viento al paso de personas, tamaño 1, pequeño, bajo collados y crestas en las laderas indicadas.

Distribución del manto nivoso

Hay nieve en el suelo a 1.600 m en N, y a 1.800-1.900 m en S. El manto es esquiable por encima de unos 1.800-1.900 m en umbrías. Los espesores alcanzan los 110-150 cm en cotas medias, variable según los efectos del viento.

Tendencia para las próximas 48-72h

Desde la noche del viernes y el fin de semana se impondrá el problema de placas de viento; serán abundantes y frágiles. Peligro en AUMENTO.

El próximo boletín será emitido el día 2026-03-13

5 MUY FUERTE	4 FUERTE	3 NOTABLE	2 LIMITADO	1 DÉBIL

EAWS EUROPEAN AVALANCHE WARNING SERVICES

ICGC Institut Cartogràfic i Geològic de Catalunya

Servei Meteorològic de Catalunya

Boletín de peligro de aludes Perafita-Puigpedrós Del 12/03/2026 al 13/03/2026

(Válido fuera pistas de esquí y zonas no controladas)

LIMITADO (2) a partir de mediodía. DÉBIL (1) hasta mediodía.

Situación primaria

Nieve húmeda

Distribución

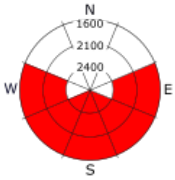

Tamaño

Origen

Tendencia

Situación secundaria

Nieve venteada

Distribución

Tamaño

Origen

Tendencia

Estado del manto nivoso

El manto se presenta bastante asentado, con costras internas. Sin embargo, en umbrías en cotas altas se empiezan a formar capas débiles internas sobre la costra marrón. Durante la mañana encontraremos unas condiciones bastante estables del manto por rehielo nocturno. A partir del mediodía, con la insolación y el aumento térmico, el manto se irá humedeciendo en solanas y orientaciones E y W de cotas bajas y medias, y serán probables caída de bolas y aludes de nieve húmeda de tamaño 1 (pequeños, con capacidad de hacernos caer y arrastrarnos) en vertientes de fuerte pendiente, más frecuente bajo resaltes rocosos y árboles. Poco a poco, se irán formando algunas pequeñas placas de viento en las cotas más altas a medida que el viento vaya incrementado de velocidad, en orientaciones NE, E, SE y S. A lo largo del viernes podría haber algún alud de placa de viento al paso de personas, de tamaño 1, pequeño, bajo collados y crestas en las orientaciones indicadas.

Distribución del manto nivoso

Hay nieve en el suelo por encima de unos 1.700 m en N y 1.900 en S. Los espesores, aunque irregulares, rondan los 80-100 cm en cotas medias. Son grosores por encima de los habituales para la época.

Tendencia para las próximas 48-72h

Desde la noche del viernes y el fin de semana se impondrá el problema de placas de viento; serán abudantes y frágiles en el extremo norte del sector. Peligro en AUMENTO.

El próximo boletín será emitido el día 2026-03-13

5 MUY FUERTE	4 FUERTE	3 NOTABLE	2 LIMITADO	1 DÉBIL

EAWS EUROPEAN AVALANCHE WARNING SERVICES

ICGC Institut Cartogràfic i Geològic de Catalunya

Servei Meteorològic de Catalunya meteo.cat

Boletín de peligro de aludes Vessant Nord Cadí-Moixeró Del 12/03/2026 al 13/03/2026

(Válido fuera pistas de esquí y zonas no controladas)

LIMITADO (2) a partir de mediodía.
DÉBIL (1) hasta mediodía.

Situación primaria

Nieve húmeda

Distribución

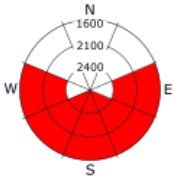

Tamaño

Origen

Tendencia

Situación secundaria

Nieve venteada

Distribución

Tamaño

Origen

Tendencia

Estado del manto nivoso

El manto se presenta bastante asentado, con costras internas, excepto en cotas altas umbrías donde encima de la costra marrón (polvo sahariana) del 5 de marzo ya se observan algunas facetas que de momento no dan propagaciones de fracturas. En superficie hay nieve granulada de los chubascos de los días pasados; el viernes quedará tapada bajo pequeñas placas de viento en las cotas más altas a medida que el viento vaya incrementado de velocidad, en orientaciones NE, E, SE y S. Así, a lo largo del viernes podrá haber algún alud de placa de viento al paso de personas, de tamaño 1 (pequeño, con capacidad de derribarnos y arrastrarnos) en las orientaciones indicadas. A partir del mediodía, con la insolación y el aumento térmico, el manto se irá humedeciendo en solanas y orientaciones E y W de cotas bajas y medias, siendo probables caídas de bolas y aludes de nieve húmeda de tamaño 1, pequeño, de debajo de rocas y de árboles.

Distribución del manto nivoso

En umbrías hay nieve por encima de 1.600 m, esquiable por encima de unos 1.700 m. En solanas la nieve está presente por encima de 1.800 m. Los grosores están alrededor de 160-180 cm a 2.200 m. Estos valores son muy excedentarios para la época del año.

Tendencia para las próximas 48-72h

Desde la noche del viernes y el fin de semana se impondrá el problema de placas de viento; serán abundantes y frágiles. Peligro en AUMENTO.

El próximo boletín será emitido el día 2026-03-13

5 MUY FUERTE	4 FUERTE	3 NOTABLE	2 LIMITADO	1 DÉBIL

EAWS EUROPEAN AVALANCHE WARNING SERVICES

ICGC Institut Cartogràfic i Geològic de Catalunya

Servei Meteorològic de Catalunya

Boletín de peligro de aludes Prepirineu
Del 12/03/2026 al 13/03/2026

(Válido fuera pistas de esquí y zonas no controladas)

LIMITADO (2) a partir de mediodía.
DÉBIL (1) hasta mediodía.

Situación primaria

Nieve venteada

Distribución

Tamaño

Origen

Tendencia

Situación secundaria

Nieve húmeda

Distribución

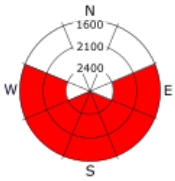

Tamaño

Origen

Tendencia

Estado del manto nivoso
En cotas altas, la nieve granulada (chubascos de los últimos días) quedará tapada por pequeñas placas de viento que se irán formando en orientaciones NE, E, SE y S, debido al viento que se irá reforzando durante el viernes. Así, a lo largo del viernes podría haber algún alud de placa de viento al paso de personas, de tamaño 1, pequeño, bajo collados y cordales en las vertientes indicadas. En las solanas, por debajo de 2.200-2.300 m el mantel se ha humedecido en los últimos días por niebla e insolación, mientras que por las noches ha rehelado; así, el manto está encostrado por la mañana. Por la mañana, con la insolación y el aumento térmico, el manto se irá humedeciendo en solanas y orientaciones E y W de cotas bajas y medias, y serán probables caída de bolas y aludes de nieve húmeda de tamaño 1 (pequeños, con capacidad de hacernos caer y arrastrarnos) a partir de puntos rocosos y árboles.

Distribución del manto nivoso
En umbrías hay nieve por encima de 1.600-1700 m. En solanas la nieve está presente por encima de 1.800-1.900 m. Los espesores, aunque irregulares, rondan los 60-80 cm en cotas medias.

Tendencia para las próximas 48-72h
Desde la noche del viernes y el fin de semana se impondrá el problema de placas de viento; serán abudantes y frágiles. Peligro en AUMENTO.

El próximo boletín será emitido el día 2026-03-13

5 MUY FUERTE	4 FUERTE	3 NOTABLE	2 LIMITADO	1 DÉBIL

EAWS EUROPEAN AVALANCHE WARNING SERVICES

ICGC Institut Cartogràfic i Geològic de Catalunya

Servei Meteorològic de Catalunya meteo.cat

Boletín de peligro de aludes Ter-Freser
Del 12/03/2026 al 13/03/2026

(Válido fuera pistas de esquí y zonas no controladas)

LIMITADO (2) a partir de mediodía.
DÉBIL (1) hasta mediodía.

Situación primaria

Nieve húmeda

Distribución

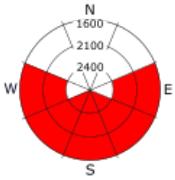

Tamaño

Origen

Tendencia

Situación secundaria

Nieve venteada

Distribución

Tamaño

Origen

Tendencia

Estado del manto nivoso

Por debajo de 2.200-2.300 m el manto se ha humedecido en los últimos días por niebla e insolación, mientras que por las noches ha rehelado y el manto está encostrado por la mañana. Durante la mañana, con la insolación y el aumento térmico, el manto se irá humedeciendo en solanas y orientaciones E y W de cotas bajas y medias, y serán probables caída de bolas y aludes de nieve húmeda de tamaño 1 (pequeños, con capacidad de hacernos caer y arrastrarnos) a partir de puntos rocosos y árboles. También puede caer algún deslizamiento basal en laderas sur, hasta tamaño 2 (mediano, con capacidad de enterrar a una persona). En cotas altas, la nieve granulada (chubascos de los últimos días) quedará tapada por pequeñas placas de viento que se irán formando en orientaciones NE, E, SE y S, debido al viento que se irá reforzando. A lo largo del viernes podría haber algún alud de placa de viento al paso de personas, de tamaño 1, pequeño, bajo collados y crestas en las vertientes indicadas.

Distribución del manto nivoso

Hay nieve en el suelo por encima de 1.600-1.700 m. Es esquiable a partir de unos 1.700 m. El manto nivoso presenta grosores muy excedentarios para la época del año. En lugares no afectados por el viento los grosores oscilan entre 80-100 cm a unos 2.000 m8 y más de 150 cm por encima de 2.400 m.

Tendencia para las próximas 48-72h

Desde la noche del viernes y el fin de semana se impondrá el problema de placas de viento; serán abudantes y frágiles en el extremo norte del sector. Peligro en AUMENTO.

El próximo boletín será emitido el día 2026-03-13

5 MUY FUERTE	4 FUERTE	3 NOTABLE	2 LIMITADO	1 DÉBIL

EAWS EUROPEAN AVALANCHE WARNING SERVICES