BUTLLETÍ DEL PERILL D'ALLAUS DEL PRINCIPAT D'ANDORRA

Servei meteorològic nacional
Principat d'Andorra

Elaborat el 12/03/2026 16:00
Propera actualització 13/03/2026 a les 16h

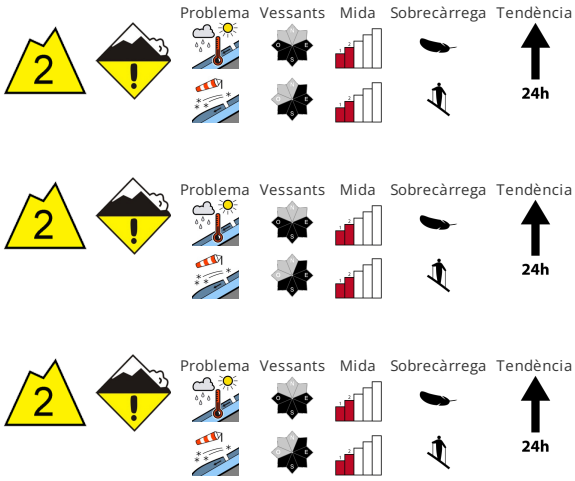

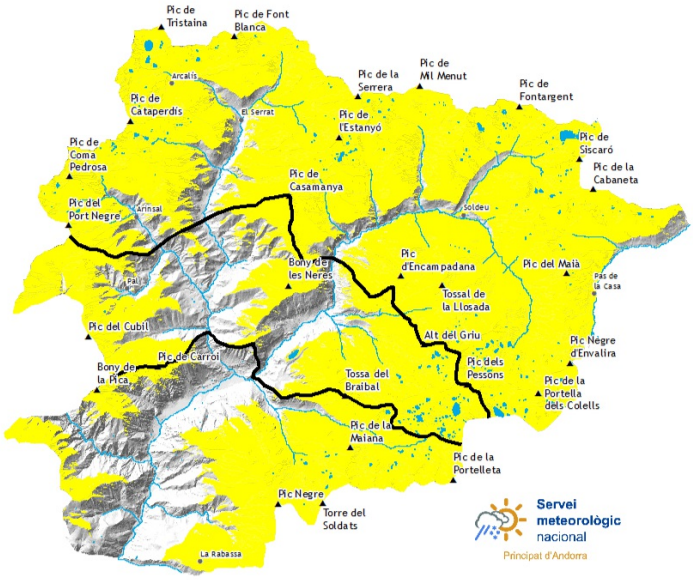

ESTABILITAT DEL MANTELL NIVAL

Amb l'augment de la temperatura diürna i la radiació solar, són possibles purgues i allaus de neu humida de mida petita i, localment, mitjana a totes les cotes. Això es dona especialment en zones de sortida molt inclinades, assolellades , encara no completament purgades. Les plaques de vent majoritàriament de mida petita d'ahir poden, de manera aïllada, desencadenar-se al pas d'un sol muntanyenc en orientacions nord-est a fins al sud-oest per l'est per sobre dels 2500 m aproximadament. A més del perill de ser enterrat per una allau, cal tenir en compte també el perill de ser arrossegat cap a una trampa del terreny. A més, són possibles allaus de lliscament basal en qualsevol moment.

QUALITAT DE LA NEU

El refredament nocturn serà bo. La superfície del mantell de neu es regelarà per formar una crosta portant i s'estovarà ja durant el matí. Als vessants obacs i a cotes mitges i altes : la part superior del mantell és seca, amb una superfície solta. Evitar les zones amb esquerdes de lliscament basal. Sobretot prop de colls i carenes els gruixos de neu varien molt per sobre dels 2400 m aproximadament per la influència del vent. Fins al divendres el temps serà parcialment assolellat. El dissabte caurà neu per sobre dels 1200 m aproximadament sobretot als al nord. El diumenge el vent serà fort.

GRUIXOS DEL MANTELL NIVAL FORA DE PISTA

Zona nord		Gruix neu		
Mantell Nival		1500m	2000m	2500m
N	1600 m	0 cm	150 cm	200 cm
S	1900 m	0 cm	100 cm	150 cm

Zona centre		Gruix neu		
Mantell Nival		1500m	2000m	2500m
N	1600 m	0 cm	150 cm	200 cm
S	1900 m	0 cm	100 cm	150 cm

Zona sud		Gruix neu		
Mantell Nival		1500m	2000m	2500m
N	1600 m	0 cm	120 cm	150 cm
S	1900 m	0 cm	60 cm	100 cm

Govern d'Andorra

EAWS
EUROPEAN AVALANCHE WARNING SERVICES

Aquest butlletí ha estat elaborat seguint les normes i recomanacions de l'**European Avalanche Warning Services**, del qual el **Servei meteorològic Nacional** n'és membre

BUTLLETÍ DEL PERILL D'ALLAUS DEL PRINCIPAT D'ANDORRA

Servei meteorològic nacional
Principat d'Andorra

Informació detallada per espais naturals protegits

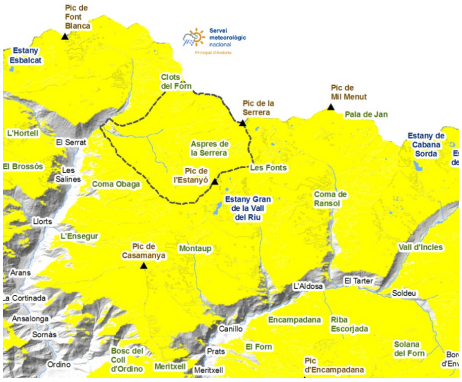

SORTENY

A cotes altes, prop dels cims, colls i carenes, poden haver-hi plaques de vent formades la nit de dimecres a dijous. Localment aquestes plaques poden reposar a sobre de grans angulosos, i actuar com a capa feble. Durant el dia la temperatura pujarà notablement i esperem activitat d´allaus naturals de neu humida, sobretot als vessants assolellats.

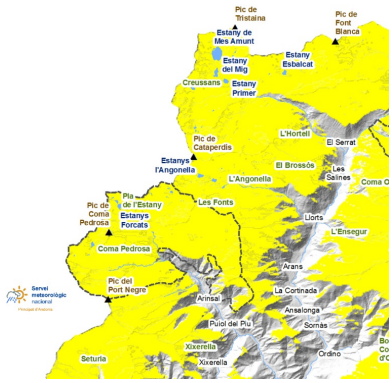

COMAPEDROSA

Com a Sorteny, el vent ha creat noves acumulacions als vessants amb component est, mentre l´augment de temperatures al llarg del dia facilitarà que baixin allaus de neu humida que en algun cas poden arribar als camins de les parts baixes del Parc.

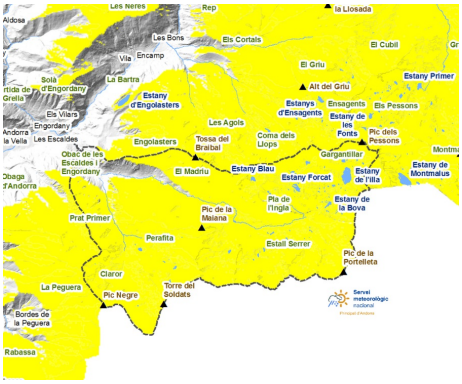

MADRIU-PERAFITA-CLAROR

Els vessants est s´han carregat una altra vegada amb plaques de vent. En altura i als vessants obacs encara trobarem neu pols durant el matí, però tindrà tendència a transformar-se al llarg del dia.

Govern d'Andorra

EAWS
EUROPEAN AVALANCHE WARNING SERVICES

Aquest butlletí ha estat elaborat seguint les normes i recomanacions de l'**European Avalanche Warning Services**, del qual el **Servei meteorològic Nacional** n'és membre

BUTLLETÍ DEL PERILL D'ALLAUS DEL PRINCIPAT D'ANDORRA

Servei meteorològic nacional
Principat d'Andorra

Gruixos de neu nova dels darrers dies (de les últimes 24h mesurat a les 06:00h UTC)

	08/03/2026	09/03/2026	10/03/2026	11/03/2026
FEDA (Central)	0 cm	0 cm	0 cm	0 cm
Engolasters - FEDA	0 cm	0 cm	0 cm	0 cm
Bony de les Neres	0 cm	0 cm	0 cm	0 cm
Sorteny	6 cm	4 cm	0 cm	7 cm
Les Fonts d'Arinsal	4 cm	0 cm	0 cm	5 cm
Perafita	3 cm	0 cm	0 cm	0 cm
Tossa Espiolets	2 cm	0 cm	0 cm	4 cm
Grau Roig - FEDA	4 cm	1 cm	0 cm	1 cm
Fontverd	1 cm	0 cm	0 cm	0 cm
Ransol - FEDA	0 cm	0 cm	0 cm	0 cm
Caborreu	2 cm	0 cm	1 cm	2 cm
La Solana	5 cm	0 cm	0 cm	3 cm
Coll Pa	0 cm	0 cm	0 cm	0 cm
Envalira Antenes	9 cm	3 cm	2 cm	0 cm
Vall del Riu FEDA	3 cm	0 cm	0 cm	0 cm