BUTLLETÍ DEL PERILL D'ALLAUS DEL PRINCIPAT D'ANDORRA

Elaborado el 12/03/2026 16:00
Proxima actualización 13/03/2026 a las 16h

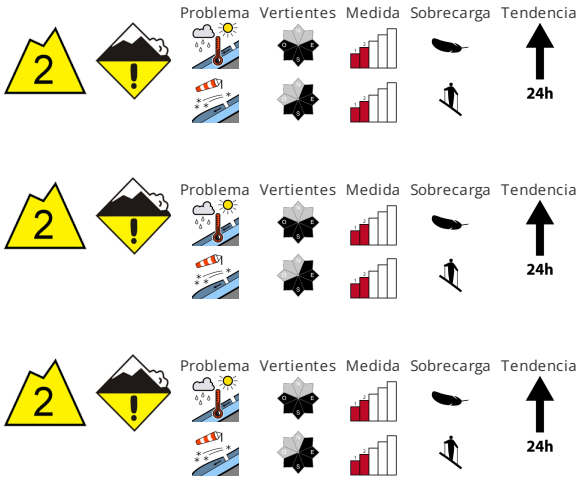

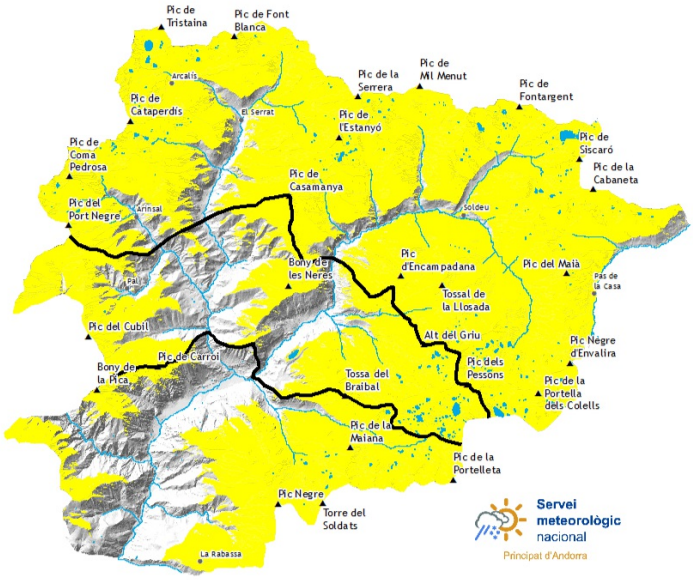

CALIDAD DE LA NIEVE

Con la subida de la temperatura diurna y la radiación solar, son posibles purgas y avalanchas de nieve húmeda de tamaño pequeño y, localmente, mediano en todas las cotas. Esto se da especialmente en zonas de salida muy inclinadas, solanas , aún no completamente purgadas. Las placas de viento , en su mayoría de tamaño pequeño, de ayer pueden, de manera aislada, desencadenarse al paso de un solo montañero en orientaciones nordeste a sudoeste por el este por encima de los 2500 m aproximadamente. Además del peligro de ser enterrado por un alud, se debe tener en cuenta también el peligro de ser arrastrado hacia una trampa del terreno. Además son posibles aludes de deslizamiento basal en cualquier momento.

ESTABILIDAD DEL MANTO NIVOSO

El enfriamiento nocturno será bueno. La superficie del manto de nieve se volverá a helar para formar una costra portante y se ablandará ya durante la mañana. en las laderas umbrías y en cotas medias y altas :. La parte superior del manto es seca, con una superficie blanda. Evitar las zonas con grietas de deslizamiento basal. Sobre todo cerca de collados y cordales los espesores de nieve varían mucho por encima de los 2400 m aproximadamente por la influencia del viento. Hasta el viernes el tiempo será parcialmente soleado. El sábado caerá nieve por encima de los 1200 m aproximadamente sobre todo en los norte. El domingo el viento soplará fuerte.

ESPESORES DEL MANTO NIVOSO FUERA DE PISTA

BUTLLETÍ DEL PERILL D'ALLAUS DEL PRINCIPAT D'ANDORRA

Servei meteorològic nacional
Principat d'Andorra

Zona norte		Espesor nieve		
Manto Nival		1500m	2000m	2500m
N	1600 m	0 cm	150 cm	200 cm
S	1900 m	0 cm	100 cm	150 cm

Zona centro		Espesor nieve		
Manto Nival		1500m	2000m	2500m
N	1600 m	0 cm	150 cm	200 cm
S	1900 m	0 cm	100 cm	150 cm

Zona sur		Espesor nieve		
Manto Nival		1500m	2000m	2500m
N	1600 m	0 cm	120 cm	150 cm
S	1900 m	0 cm	60 cm	100 cm

BUTLLETÍ DEL PERILL D'ALLAUS DEL PRINCIPAT D'ANDORRA

Servei meteorològic nacional
Principat d'Andorra

Información detallada por espacios naturales protegidos

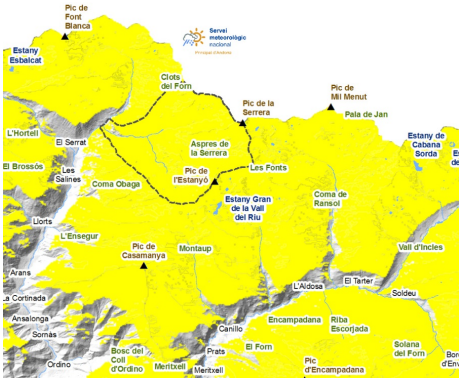

SORTENY

En cotas altas, cerca de las cimas, collados y cordales, pueden haber placas de viento formadas la noche del miércoles al jueves. Localmente estas placas pueden reposar sobre grandes angulosos, y actuar como capa débil. Durante el día la temperatura subirá notablemente y esperamos actividad de aludes naturales de nieve húmeda, sobre todo en las vertientes soleadas.

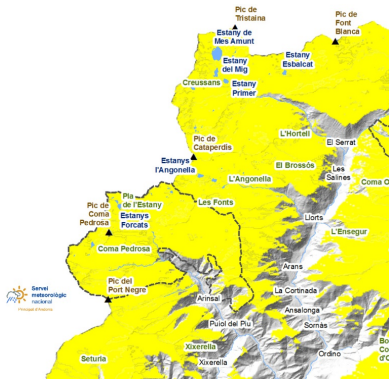

COMAPEDROSA

Como en Sorteny, el viento ha creado nuevas acumulaciones en las laderas con componente este, mientras el aumento de temperaturas a lo largo del día facilitará que bajen aludes de nieve húmeda que en algún caso pueden llegar a los caminos de las partes bajas del Parque.

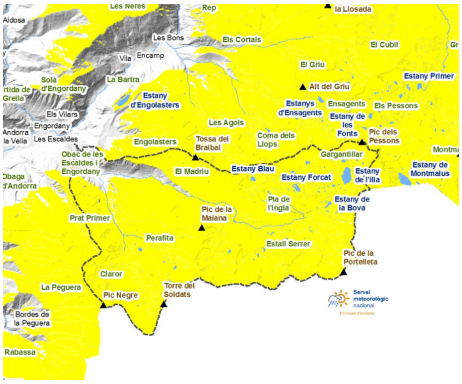

MADRIU-PERAFITA-CLAROR

Las vertientes este se han cargado otra vez con placas de viento. En altura y en las laderas umbrías todavía encontraremos nieve polvo durante la mañana, pero tendrá tendencia a transformarse a lo largo del día.

Govern d'Andorra

EAWS EUROPEAN AVALANCHE WARNING SERVICES

Aquest butlletí ha estat elaborat seguint les normes i recomanacions de l'**European Avalanche Warning Services**, del qual el **Servei meteorològic Nacional** n'és membre

BUTLLETÍ DEL PERILL D'ALLAUS DEL PRINCIPAT D'ANDORRA

Servei meteorològic nacional
Principat d'Andorra

Espesores de nieve nueva de los últimos días (de las ultimas 24h mesurado a las 06:00h UTC)

	08/03/2026	09/03/2026	10/03/2026	11/03/2026
FEDA (Central)	0 cm	0 cm	0 cm	0 cm
Engolasters - FEDA	0 cm	0 cm	0 cm	0 cm
Bony de les Neres	0 cm	0 cm	0 cm	0 cm
Sorteny	6 cm	4 cm	0 cm	7 cm
Les Fonts d'Arinsal	4 cm	0 cm	0 cm	5 cm
Perafita	3 cm	0 cm	0 cm	0 cm
Tossa Espiolets	2 cm	0 cm	0 cm	4 cm
Grau Roig - FEDA	4 cm	1 cm	0 cm	1 cm
Fontverd	1 cm	0 cm	0 cm	0 cm
Ransol - FEDA	0 cm	0 cm	0 cm	0 cm
Caborreu	2 cm	0 cm	1 cm	2 cm
La Solana	5 cm	0 cm	0 cm	3 cm
Coll Pa	0 cm	0 cm	0 cm	0 cm
Envalira Antenes	9 cm	3 cm	2 cm	0 cm
Vall del Riu FEDA	3 cm	0 cm	0 cm	0 cm