BUTLLETÍ DEL PERILL D'ALLAUS DEL PRINCIPAT D'ANDORRA

Préparé le 12/03/2026 16:00
Prochaine mise à jour le 13/03/2026 à 16h

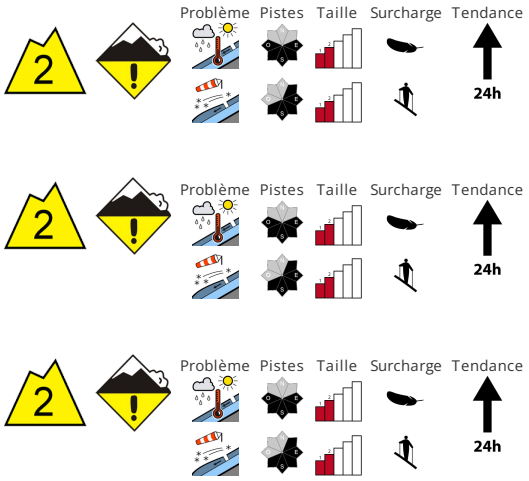

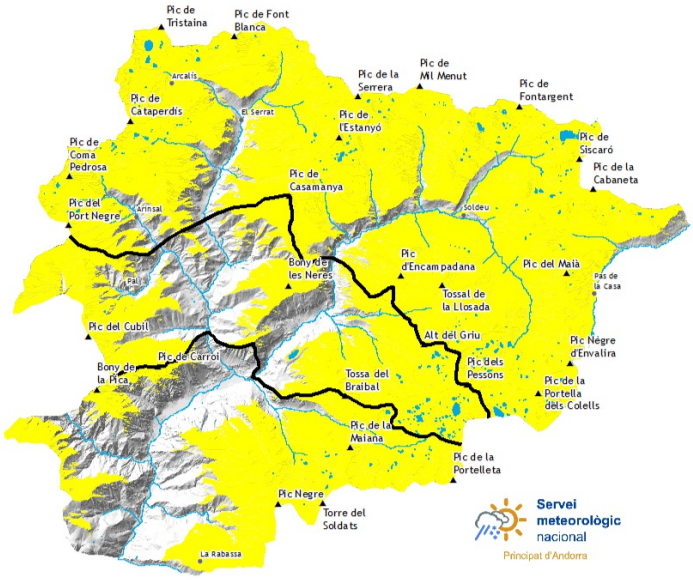

STABILITÉ DU MANTEAU NEIGEUX

Des avalanches et coulées humides de petite et rarement moyenne taille sont ils sont possibles avec le réchauffement diurne et le rayonnement solaire à toutes les altitudes. Ceci surtout dans les zones de départ très raides , ensoleillées , pas encore totalement déchargées. Les accumulations de neige soufflée généralement petites d'hier peuvent être déclenchées de manière isolée par un seul amateur de sports d'hiver au sur les pentes exposées au nord-est à sud-ouest en passant par l'est au-dessus d'environ 2500 m. A côté du danger d'ensevelissement, il faut aussi penser au danger d'être emporté et de chuter.. En outre, des avalanches de glissement sont possibles à tout moment..

QUALITÈ DE LA NEIGE

Le rayonnement nocturne est bon.. La surface de la neige regèle et devient porteuse et se ramollit dès la matinée.. sur les pentes à l'ombre et aux altitudes moyennes et élevées (-):. La zone supérieure du manteau neigeux est sèche , avec une surface meuble. Les zones présentant des fissures de glissement doivent être évitées.. Surtout à proximité des crêtes et des cols on trouve suivant l'influence du vent des hauteurs de neiges très différentes au-dessus d'environ 2400 m. Jusqu'à vendredi il fait un temps partiellement ensoleillé. Samedi il tombera de la neige au-dessus d'environ 1200 m surtout au nord. Dimanche le vent souffle fortement.

EPAISSEUR DE NEIGE HORS PISTE

BUTLLETÍ DEL PERILL D'ALLAUS DEL PRINCIPAT D'ANDORRA

Servei meteorològic nacional
Principat d'Andorra

Zone nord		Epaisseur de neige		
Nival manteau		1500m	2000m	2500m
N	1600 m	0 cm	150 cm	200 cm
S	1900 m	0 cm	100 cm	150 cm

Zone centre		Epaisseur de neige		
Nival manteau		1500m	2000m	2500m
N	1600 m	0 cm	150 cm	200 cm
S	1900 m	0 cm	100 cm	150 cm

Zone sud		Epaisseur de neige		
Nival manteau		1500m	2000m	2500m
N	1600 m	0 cm	120 cm	150 cm
S	1900 m	0 cm	60 cm	100 cm

BUTLLETÍ DEL PERILL D'ALLAUS DEL PRINCIPAT D'ANDORRA

Servei meteorològic nacional
Principat d'Andorra

Des informations détaillées par espace naturel protégé

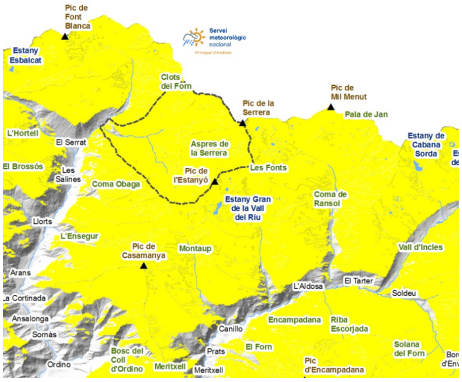

SORTENY

À des altitudes plus élevées, près des sommets, des cols et des crêtes, des plaques de vent peuvent se former dans la nuit de mercredi à jeudi. Localement, ces plaques peuvent reposer sur des grains angulaires et agir comme une couche faible. Pendant la journée, la température augmentera considérablement et on s'attend à une activité naturelle d'avalanches de neige mouillée, surtout sur les pentes ensoleillées. , , , , ,

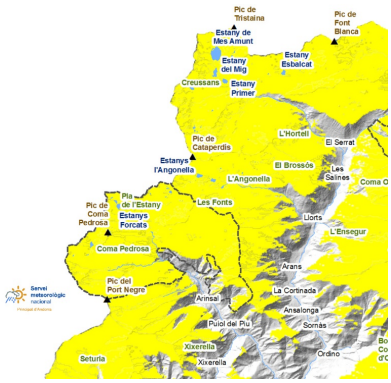

COMAPEDROSA

Comme à Sorteny, le vent a créé de nouvelles accumulations sur les pentes avec une composante orientale, tandis que l'augmentation des températures tout au long de la journée facilitera la chute des avalanches de neige mouillée qui, dans certains cas, pourront atteindre les sentiers des parties basses du Parc. ,

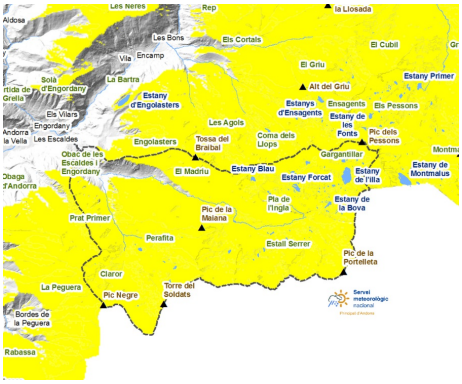

MADRIU-PERAFITA-CLAROR

Les pentes orientales ont été à nouveau chargées de plaques de vent. En altitude et sur les pistes opaques on trouvera encore de la poudreuse au cours de la matinée, mais elle aura tendance à changer au cours de la journée. , , ,

Govern d'Andorra

EAWS
EUROPEAN AVALANCHE WARNING SERVICES

Aquest butlletí ha estat elaborat seguint les normes i recomanacions de l'**European Avalanche Warning Services**, del qual el **Servei meteorològic Nacional** n'és membre

BUTLLETÍ DEL PERILL D'ALLAUS DEL PRINCIPAT D'ANDORRA

Servei meteorològic nacional
Principat d'Andorra

Couche de neige fraiche des derniers jours (De 24 h mesurée à 06:00 h UTC)

	08/03/2026	09/03/2026	10/03/2026	11/03/2026
FEDA (Central)	0 cm	0 cm	0 cm	0 cm
Engolasters - FEDA	0 cm	0 cm	0 cm	0 cm
Bony de les Neres	0 cm	0 cm	0 cm	0 cm
Sorteny	6 cm	4 cm	0 cm	7 cm
Les Fonts d'Arinsal	4 cm	0 cm	0 cm	5 cm
Perafita	3 cm	0 cm	0 cm	0 cm
Tossa Espiolets	2 cm	0 cm	0 cm	4 cm
Grau Roig - FEDA	4 cm	1 cm	0 cm	1 cm
Fontverd	1 cm	0 cm	0 cm	0 cm
Ransol - FEDA	0 cm	0 cm	0 cm	0 cm
Caborreu	2 cm	0 cm	1 cm	2 cm
La Solana	5 cm	0 cm	0 cm	3 cm
Coll Pa	0 cm	0 cm	0 cm	0 cm
Envalira Antenes	9 cm	3 cm	2 cm	0 cm
Vall del Riu FEDA	3 cm	0 cm	0 cm	0 cm