MINISTERO DELLA DIFESA

meteomont
Servizio Nazionale di previsione neve e valanghe

EAWS EUROPEAN AVALANCHE WARNING SERVICES

CARABINIERI

AERONAUTICA MILITARE SERVIZIO METEOROLOGICO

# ALPI GIULIE

Bollettino Valanghe N. 371/2026 del 11/03/2026 ore 14.00
Validità 48 ore prossima emissione 12/03/2026

**A cura del Servizio METEOMONT dell'ARMA dei CARABINIERI**
**In collaborazione con Servizio Meteorologico dell'Aeronautica militare**

## SITUAZIONE alle 14:00 del 11/03/2026

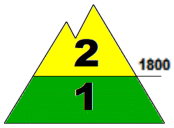


**SITUAZIONE TIPO: neve a debole coesione e vento.**

**SITUAZIONE TIPO: situazione primaverile.**

| Quota neve (mslm) | Nord | Sud |
|---|---|---|
| | 900 - 1000 | 1300 - 1800 |

| Altezza Neve (cm) | Neve al suolo | Neve Fresca | Quota (mslm) |
|---|---|---|---|
| | 400 | 001 | 2046 |
| | 74 | 00 | 1130 |

**VALANGHE OSSERVATE: Nessuna valanga.**

## PREVISIONI 12/03/2026

## GRADO DI PERICOLO: MODERATO 2

## SITUAZIONE TIPO: neve a debole coesione e vento.

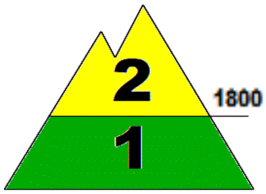


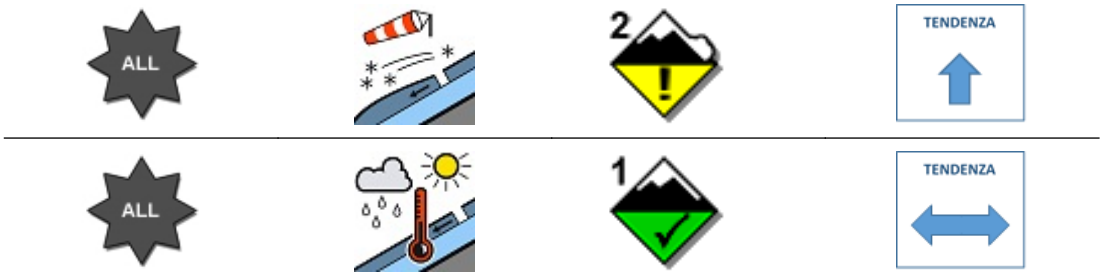


## SITUAZIONE TIPO: situazione primaverile.

**MANTO NEVOSO: La stabilità del manto nevoso è scarsa su alcuni punti (aree) per tutte le esposizioni al di sopra di 1800 mslm, possibili valanghe di dimensioni medie.**
**La stabilità del manto nevoso è discreta su pochi punti (aree) per tutte le esposizioni al di sotto di 1800 mslm, possibili valanghe di dimensioni piccole.**

## AVVERTENZE

Il rialzo termico diurno richiede un'attenta valutazione temporale dell'escursione che eviti l'attraversamento di pendii ripidi nelle ore più calde della giornata.

## SCALA EUROPEA DEL GRADO DI PERICOLO VALANGHE

## LEGENDA PROBLEMA

**Bollettino realizzato su scala sinottica-regionale (standard EAWS). La sua valutazione non può escludere in alcun modo la necessità di una seria e capace valutazione locale del pericolo (singolo pendio) che può essere anche sensibilmente diverso. Le previsioni meteorologiche sono relative all'orario UTC (per l'Italia +1 in inverno e +2 in estate).**

MINISTERO DELLA DIFESA

meteomont
Servizio Nazionale di previsione neve e valanghe

EAWS EUROPEAN AVALANCHE WARNING SERVICES

CARABINIERI

# ALPI GIULIE

## PREVISIONE METEO

| Quota | | 12/03/2026 h6:00 | 12/03/2026 h12:00 | 12/03/2026 h18:00 |
|---|---|---|---|---|
| 1000 | Venti | 01 Nodi da Est | 01 Nodi da N-Est | 01 Nodi da N-Est |
| | Temperature | +02 °C | +03 °C | +03 °C |
| | Temp.percepita | 2 °C | 3 °C | 3 °C |
| 2000 | Venti | 03 Nodi da Nord | 06 Nodi da N-Est | 04 Nodi da Est |
| | Temperature | -01 °C | -01 °C | -02 °C |
| | Temp.percepita | -3 °C | -5 °C | -5 °C |
| 3000 | Venti | 02 Nodi da Nord | 06 Nodi da Est | 03 Nodi da Sud |
| | Temperature | -07 °C | -07 °C | -07 °C |
| | Temp.percepita | -7 °C | -12 °C | -10 °C |
| Zero termico | | 1600-1800 m. | 1600-1800 m. | 1600-1800 m. |
| Fenomeno | | — | — | — |
| Stato del cielo | | | | |

## LEGENDA FENOMENI

— Assenza Fenomeni · Nebbia · Foschia · Pioggia debole · Pioggia moderata · Pioggia forte · Temporali

Nevicata debole · Nevicata moderata · Nevicata forte

## STATO DEL CIELO

Sereno · Poco nuvoloso · Nuvoloso · Molto nuvoloso · Coperto

## Parametri meteonivometrici registrati presso i campi di rilevamento il 11/03/2026.

| Località | Comune | Quota (m.s.l.m.) | Altezza neve (cm) | Neve caduta nelle 24 ore (cm) | Temp. Min (°C) | Temp. Max (°C) | Condizioni del tempo |
|---|---|---|---|---|---|---|---|
| MALBORGHETTO - VAL SAISERA | Tarvisio (UD) | 875 | 19 | 0 | +1 | +13 | Assenza di precipitazioni |
| PASSO PRAMOLLO | Pontebba (UD) | 1530 | 90 | 0 | +2 | +6 | Assenza di precipitazioni |
| MONTE LUSSARI | Tarvisio (UD) | 1750 | 92 | 0 | 0 | +10 | Assenza di precipitazioni |
| PASSO PREDIL | Tarvisio (UD) | 1130 | 74 | 0 | +1 | +8 | Assenza di precipitazioni |
| M.TE URSIC * | Resia (UD) | 2046 | 400 | 1 | N.P. | N.P. | Nevicata moderata |
| FORCELLA BILAPEC * | Chiusaforte (UD) | 1897 | 127 | 2 | N.P. | N.P. | Nevicata debole continua |

(*) Rilievi fuori campo

**L'INFORMAZIONE E' PREVENZIONE - LEGGI L'ATTUALE GRADO DI PERICOLO VALANGHE!**

IL CAPO DEL CENTRO NAZIONALE METEOMONT
(Ten. Col. RFI Emanuela Gini)
FIRMA AUTOGRAFA OMESSA AI SENSI
DELL'ART.3 DEL D.LGS N.39/1993

Bollettino realizzato su scala sinottica-regionale (standard EAWS). La sua valutazione non può escludere in alcun modo la necessità di una seria e capace valutazione locale del pericolo (singolo pendio) che può essere anche sensibilmente diverso. Le previsioni meteorologiche sono relative all'orario UTC (per l'Italia +1 in inverno e +2 in estate).