MINISTERO DELLA DIFESA

meteomont Servizio Nazionale di previsione neve e valanghe

EAWS EUROPEAN AVALANCHE WARNING SERVICES

CARABINIERI

In collaborazione con: arpav

# DOLOMITI SETTENTRIONALI

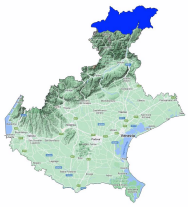

Bollettino Valanghe N. 370/2026 del 11/03/2026 ore 14.00
Validità 48 ore prossima emissione 12/03/2026

**A cura del Servizio METEOMONT dell'ARMA dei CARABINIERI**
**In collaborazione con Servizio Meteorologico dell'Aeronautica militare**

## SITUAZIONE alle 14:00 del 11/03/2026

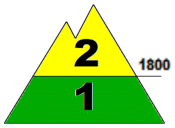


**SITUAZIONE TIPO: neve a debole coesione e vento.**




**SITUAZIONE TIPO: situazione primaverile.**

| Quota neve (mslm) | Nord | Sud |
|---|---|---|
| | 1100 - 1700 | 1300 - 2000 |

| Altezza Neve (cm) | Neve al suolo | Neve Fresca | Quota (mslm) |
|---|---|---|---|
| | 95 | 10 | 2550 |
| | 31 | 00 | 1246 |

**VALANGHE OSSERVATE: Nessuna valanga.**

## PREVISIONI 12/03/2026

## GRADO DI PERICOLO: MODERATO 2

## SITUAZIONE TIPO: neve a debole coesione e vento.

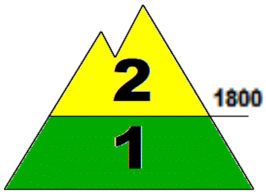





## SITUAZIONE TIPO: situazione primaverile.

**MANTO NEVOSO: La stabilità del manto nevoso è scarsa su alcuni punti (aree) per tutte le esposizioni al di sopra di 1800 mslm, possibili valanghe di dimensioni medie.**
**La stabilità del manto nevoso è buona su pochi punti (aree) per tutte le esposizioni al di sotto di 1800 mslm, possibili valanghe di dimensioni piccole.**

## AVVERTENZE

Il rialzo termico diurno richiede un'attenta valutazione temporale dell'escursione che eviti l'attraversamento di pendii ripidi nelle ore più calde della giornata.

## SCALA EUROPEA DEL GRADO DI PERICOLO VALANGHE

5 - MOLTO FORTE | 4 - FORTE | 3 - MARCATO | 2 - MODERATO | 1 - DEBOLE | NO NEVE | NO INFO

## LEGENDA PROBLEMA

NEVE FRESCA | LASTRONI DA VENTO | STRATI DEBOLI PERSISTENTI | NEVE BAGNATA | SLITTAMENTO | CORNICI | NESSUN PROBLEMA VALANGHIVO EVIDENTE | NO_INFO

**Bollettino realizzato su scala sinottica-regionale (standard EAWS). La sua valutazione non può escludere in alcun modo la necessità di una seria e capace valutazione locale del pericolo (singolo pendio) che può essere anche sensibilmente diverso. Le previsioni meteorologiche sono relative all'orario UTC (per l'Italia +1 in inverno e +2 in estate).**

MINISTERO DELLA DIFESA

meteomont
Servizio Nazionale di previsione neve e valanghe

EAWS EUROPEAN AVALANCHE WARNING SERVICES

CARABINIERI

In collaborazione con: arpav

# DOLOMITI SETTENTRIONALI

## PREVISIONE METEO

| Quota | | 12/03/2026 h6:00 | 12/03/2026 h12:00 | 12/03/2026 h18:00 |
|---|---|---|---|---|
| 1000 | Venti | 02 Nodi da N-Est | 01 Nodi da Est | 01 Nodi da Est |
| | Temperature | -01 °C | +01 °C | +00 °C |
| | Temp.percepita | -1 °C | 1 °C | 0 °C |
| 2000 | Venti | 03 Nodi da N-Est | 02 Nodi da Est | 01 Nodi da Est |
| | Temperature | -01 °C | -01 °C | -01 °C |
| | Temp.percepita | -3 °C | -1 °C | -1 °C |
| 3000 | Venti | 04 Nodi da N-Est | 04 Nodi da Est | 02 Nodi da Sud |
| | Temperature | -07 °C | -08 °C | -07 °C |
| | Temp.percepita | -11 °C | -12 °C | -7 °C |
| Zero termico | | 1500-1700 m. | 1800-2000 m. | 1800-2000 m. |
| Fenomeno | | — | | — |
| Stato del cielo | | | | |

## LEGENDA FENOMENI

— Assenza Fenomeni · Nebbia · Foschia · Pioggia debole · Pioggia moderata · Pioggia forte · Temporali

Nevicata debole · Nevicata moderata · Nevicata forte

## STATO DEL CIELO

Sereno · Poco nuvoloso · Nuvoloso · Molto nuvoloso · Coperto

## Parametri meteonivometrici registrati presso i campi di rilevamento il 11/03/2026.

| Località | Comune | Quota (m.s.l.m.) | Altezza neve (cm) | Neve caduta nelle 24 ore (cm) | Temp. Min (°C) | Temp. Max (°C) | Condizioni del tempo |
|---|---|---|---|---|---|---|---|
| MISURINA | Auronzo di Cadore (BL) | 1759 | 47 | 2 | -5 | +16 | Assenza di precipitazioni |
| MONTE FALORIA | Cortina d'Ampezzo (BL) | 2119 | 72 | 3 | -2 | +14 | Assenza di precipitazioni |
| COL DELLA TENDA | Comelico Superiore (BL) | 1930 | 60 | Tracce di neve | -1 | +7 | Nebbia con cielo non visibile |
| PUNTA MARIETTA * | Cortina d'Ampezzo (BL) | 2550 | 95 | 10 | N.P. | N.P. | Nevicata debole intermittente |

(*) Rilievi fuori campo

**L'INFORMAZIONE E' PREVENZIONE - LEGGI L'ATTUALE GRADO DI PERICOLO VALANGHE!**

**IL CAPO DEL CENTRO NAZIONALE METEOMONT**
**(Ten. Col. RFI Emanuela Gini)**
**FIRMA AUTOGRAFA OMESSA AI SENSI**
**DELL'ART.3 DEL D.LGS N.39/1993**

Bollettino realizzato su scala sinottica-regionale (standard EAWS). La sua valutazione non può escludere in alcun modo la necessità di una seria e capace valutazione locale del pericolo (singolo pendio) che può essere anche sensibilmente diverso. Le previsioni meteorologiche sono relative all'orario UTC (per l'Italia +1 in inverno e +2 in estate).