Bulletin d'estimation du risque d'avalanche
(valable en dehors des pistes balisées et ouvertes)

MASSIF : Queyras

Rédigé le jeudi 12 mars 2026 à 15h

Estimation des risques pour le : VENDREDI 13 MARS

QUELQUES PLAQUES SUPERFICIELLES EN UBAC D'ALTITUDE

2

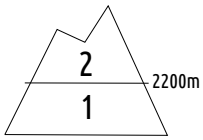

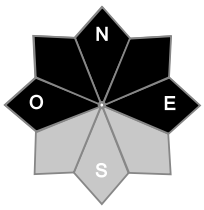

Au-dessus de 2200m indice de risque limité, plus bas indice faible.

Départs spontanés : très rares.

Déclenchements provoqués : quelques plaques superficielles. D'autres plus épaisses en altitude, difficiles à déclencher.

Indices de risque : 5 très fort - 4 fort - 3 marqué - 2 limité - 1 faible -- En noir : les pentes les plus dangereuses

Stabilité du manteau neigeux

Situation avalancheuse typique : neige ventée couche fragile persistante

Départs spontanés : quelques boulettes au soleil. Une avalanche de fond n'est pas exclue sur les secteurs avec un sol favorable (pentes herbeuses, dalles rocheuses). Avalanches de taille moyenne (taille 2).

Déclenchements provoqués : Manteau neigeux généralement bien stabilisé.
- Quelques plaques superficielles peuvent être présentes dans la neige fraiche ventée, plutôt en Ubacs au-dessus de 2000/2200 m. Départs restant de petite taille.
- Un départ volumineux reste non exclu en cas de sollicitation de couches fragiles plus profondément enfouies, présentes en versant est, nord et ouest à partir de 2200 m, voir en versant sud à haute altitude. Déclenchement très difficile au passage d'un skieur, possible là où les épaisseurs de neige sont moins importantes (croupes, bords des couloirs,...), ou en pente fortement humidifiée d'altitude.

Qualité de la neige

L'enneigement est proche des normales en ubacs, mais déficitaire en adrets. Les limites d'enneigement remontent dans les pentes bien exposées au soleil.
Hauteurs de neige observées : 147 cm en versant nord du col Izoard à 2300 m, 67 cm à Cervières à 1610 m, 93 cm à la Nivôse du Col Agnel à 2630 m, 40 cm à Ristolas à 1670 m.

Limite d'enneigement skiable : 1400 m en ubacs, mais au mieux 1900/2000 m en adrets.

État de la neige de surface : manteau neigeux croûté dans les adrets, ainsi qu'en ubacs sous 1800/2000 m, s'humidifiant en cours de journée au soleil. Plus haut dans les pentes nord-ouest à nord-est, on retrouve un peu neige fraiche encore froide, reposant sur un fond dur ou sur de la vielle poudreuse dense au-dessus de 2200/2300 m, parfois travaillée par le vent proche des crêtes.

Aperçu météo pour le vendredi 13 mars

	nuit	matin	après-midi	soir
Temps sec ensoleillé, se voilant légèrement l'après-midi.				
Pluie-Neige				
Iso 0 °C	2 100 m	2 200 m	2 400 m	2 200 m
Vent 2000 m	10 km/h	10 km/h	15 km/h	15 km/h
Vent 3000 m	15 km/h	15 km/h	20 km/h	20 km/h

Épaisseur de neige hors-piste

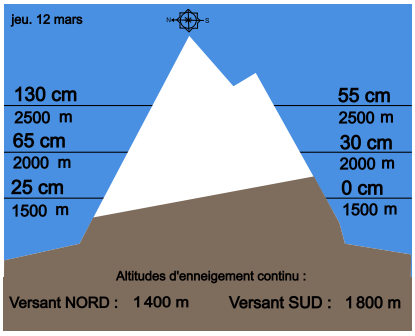

Précipitations à 1800 m

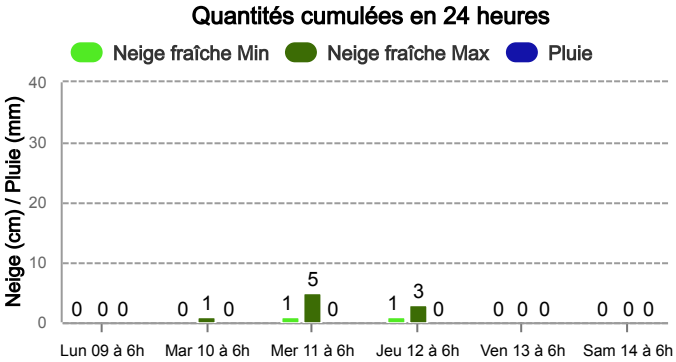

Tendance du samedi 14 mars

Indice de risque marqué

Risque en hausse avec la formation de nouvelles plaques liées aux chutes de neige en journée de samedi.

Pour consulter la vigilance en cours, veuillez vous rendre sur le site https://vigilance.meteofrance.fr/fr

Météo-France - 73 avenue de Paris, 94165 Saint-Mandé cedex - Contact : contact@meteo.fr

Rédigé par Météo-France avec la contribution des observateurs du réseau nivo-météorologiques. Partenariat : ANMSM (Maires de Stations de Montagne), DSF (Domaines Skiables de France), ADSP (Directeurs de Pistes et de la Sécurité des Stations de Sports d'Hiver) et autres acteurs de la montagne.

Bulletin neige & avalanches par téléphone au 0 892 68 10 20 Service 0,35 € / min + prix appel

RÉPUBLIQUE FRANÇAISE
Liberté Égalité Fraternité

METEO FRANCE
À VOS CÔTÉS, DANS UN CLIMAT QUI CHANGE

Bulletin d'estimation du risque d'avalanche

(valable en dehors des pistes balisées et ouvertes)

MASSIF : Queyras

Rédigé le jeudi 12 mars 2026 à 15h

Conditions nivo-météo des 7 derniers jours

	ven. 06/03				sam. 07/03				dim. 08/03				lun. 09/03				mar. 10/03				mer. 11/03				jeu. 12/03			
	03h	09h	15h	21h	03h	09h	15h	21h	03h	09h	15h	21h	03h	09h	15h	21h	03h	09h	15h	21h	03h	09h	15h	21h	03h	09h	15h	21h
Météo																												
Vent (km/h)	40	30	30	25	30	30	30	25	20	25	25	20	20	30	35	35	25	20	20	10	20	25	40	40	35	20	20	15
à 3000m																												
Vent (km/h)	20	20	25	20	20	20	20	15	15	20	20	10	10	20	25	25	15	15	15	5	10	15	25	15	15	15	15	10
à 2000m																												

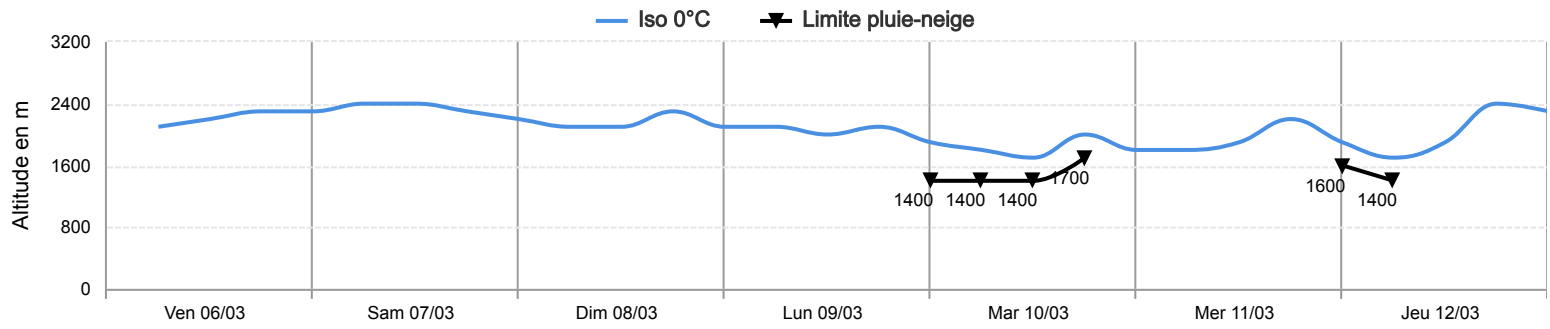

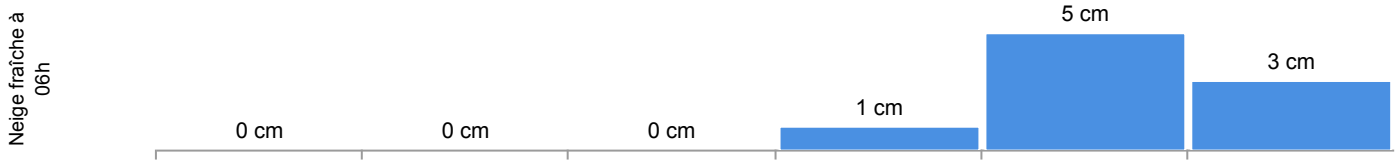

Risque d'avalanche	ven. 06/03	sam. 07/03	dim. 08/03	lun. 09/03	mar. 10/03	mer. 11/03	jeu. 12/03
	2	2	2	2	2	2	2

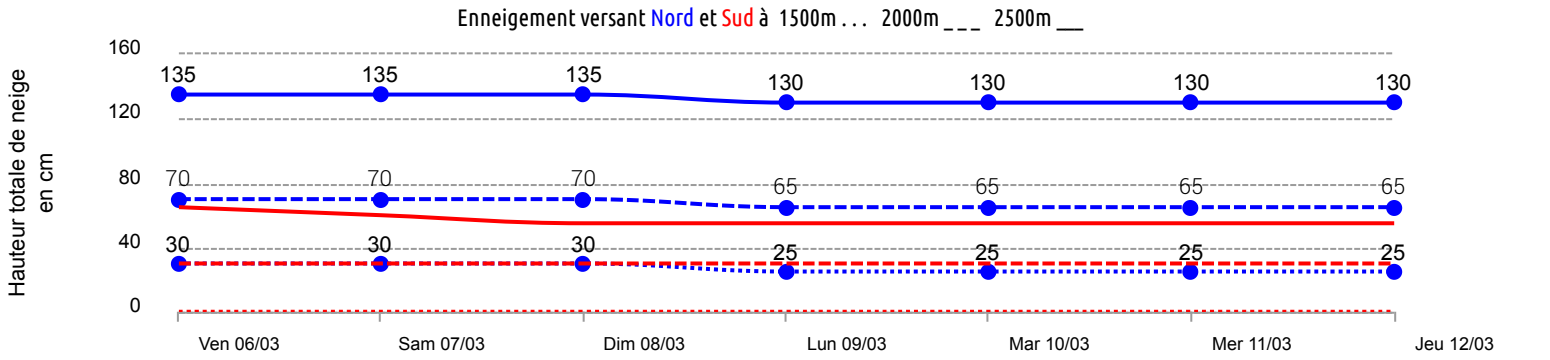

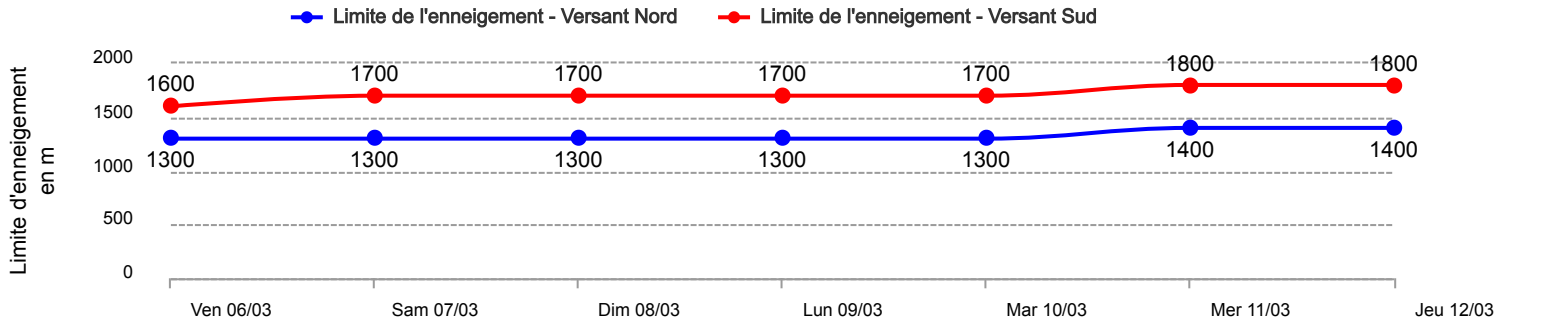

Pour consulter la vigilance en cours, veuillez vous rendre sur le site https://vigilance.meteofrance.fr/fr

Météo-France - 73 avenue de Paris, 94165 Saint-Mandé cedex - Contact : contact@meteo.fr

Bulletin neige & avalanches par téléphone au

0 892 68 10 20 Service 0,35 € / min + prix appel

Rédigé par Météo-France avec la contribution des observateurs du réseau nivo-météorologiques. Partenariat : ANMSM (Maires de Stations de Montagne), DSF (Domaines Skiables de France), ADSP (Directeurs de Pistes et de la Sécurité des Stations de Sports d'Hiver) et autres acteurs de la montagne.