RÉPUBLIQUE FRANÇAISE
*Liberté Égalité Fraternité*

METEO FRANCE
À VOS CÔTÉS, DANS UN CLIMAT QUI CHANGE

# Bulletin d'estimation du risque d'avalanche
## (valable en dehors des pistes balisées et ouvertes)

# MASSIF : Aure Louron

Rédigé le jeudi 12 mars 2026 à 16h

## Estimation des risques pour le : VENDREDI 13 MARS

**MANTEAU NEIGEUX BIEN STABILISE, RARES INSTABILITÉS EN HAUTE MONTAGNE**

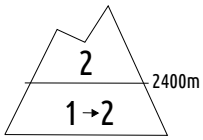


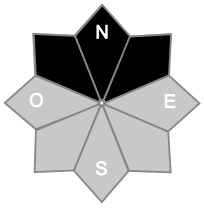


Au-dessus de 2400m indice de risque limité, plus bas indice faible évoluant en limité.

**Départs spontanés :** En cours de journée, sur les pentes très ensoleillées

**Déclenchements provoqués :** Rares plaques en haute montagne.

Indices de risque : 5 très fort - 4 fort - 3 marqué - 2 limité - 1 faible -- En noir : les pentes les plus dangereuses

## Stabilité du manteau neigeux

**Situation avalancheuse typique :** neige humide neige ventée

**Départs spontanés** : Coulées ou avalanches de neige humide (taille moyenne) devenant plus fréquentes dans les pentes les plus ensoleillées, départs le plus souvent près des rochers. départs possibles de plaques vers les pentes Sud au-dessus de 2500m. Rares avalanches de fond encore possible sur tous les versants avec des départs au niveau des fissures.

**Déclenchements provoqués** : Un skieur peut encore déclencher une plaque vers les pentes Nord au-dessus de 2400m, près des crêtes ou des cols. Ces plaques qui se sont formées le dernier week-end sont en cours de stabilisation.

**Autres** : ponts de neige et corniches fragilisés au soleil.

## Qualité de la neige

**Enneigement** : enneigement encore assez bon pour la saison au-dessus de 1600m, plutôt maigre en versants exposés au vent d'Ouest et en versants Sud.
**Limites skiables** : à partir de 1500/1600m en versants froids, plutôt 1800m en versants Sud peu raides
**État de la neige** : neige de printemps, dure le matin puis de plus en plus molle en journée sur la plupart des pentes bien ensoleillées. Neige compacte plus sèche vers les pentes Nord surtout au-dessus de 1800 m.

## Aperçu météo pour le vendredi 13 mars

| | nuit | matin | après-midi | soir |
|---|---|---|---|---|
| | | | | |

Vendredi : Soleil. Nuit de vendredi à samedi : rafraîchissement et neige

| | | | | |
|---|---|---|---|---|
| **Pluie-Neige** | | | | 1 800 m |
| **Iso 0 °C** | 2 700 m | 2 700 m | 2 700 m | 2 300 m |
| **Vent 1500 m** | ↑ 5 km/h | ↑ 10 km/h | ↗ 20 km/h | ↑ 25 km/h |
| **Vent 3000 m** | ↘ 30 km/h | → 35 km/h | → 50 km/h | ↗ 55 km/h |

## Épaisseur de neige hors-piste

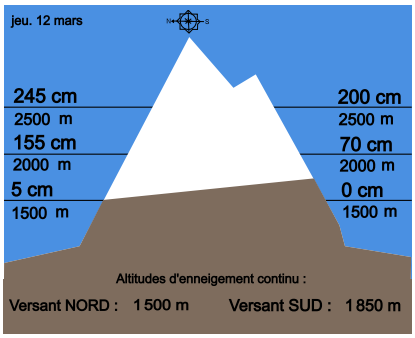


## Précipitations à 1800 m

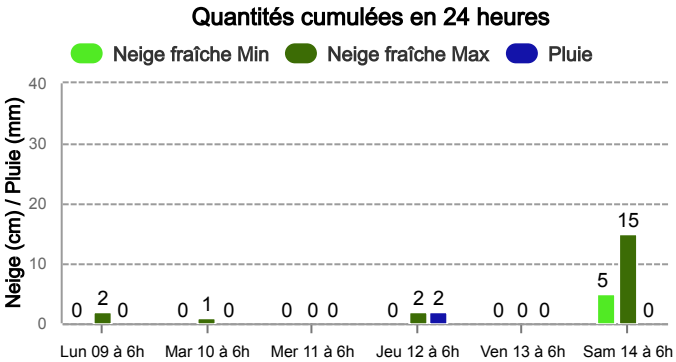


## Tendance du samedi 14 mars

**Indice de risque marqué**

Risque en hausse avec les chutes de neige ventée samedi.

Pour consulter la vigilance en cours, veuillez vous rendre sur le site https://vigilance.meteofrance.fr/fr

Météo-France - 73 avenue de Paris, 94165 Saint-Mandé cedex - Contact : contact@meteo.fr

Rédigé par Météo-France avec la contribution des observateurs du réseau nivo-météorologiques. Partenariat : ANMSM (Maires de Stations de Montagne), DSF (Domaines Skiables de France), ADSP (Directeurs de Pistes et de la Sécurité des Stations de Sports d'Hiver) et autres acteurs de la montagne.

Bulletin neige & avalanches par téléphone au
**0 892 68 10 20** Service 0,35 € / min + prix appel

RÉPUBLIQUE FRANÇAISE
*Liberté Égalité Fraternité*

METEO FRANCE
À VOS CÔTÉS, DANS UN CLIMAT QUI CHANGE

# Bulletin d'estimation du risque d'avalanche

## (valable en dehors des pistes balisées et ouvertes)

# MASSIF : Aure Louron

Rédigé le jeudi 12 mars 2026 à 16h

## Conditions nivo-météo des 7 derniers jours

| | ven. 06/03 | | | | sam. 07/03 | | | | dim. 08/03 | | | | lun. 09/03 | | | | mar. 10/03 | | | | mer. 11/03 | | | | jeu. 12/03 | | | |
|---|---|---|---|---|---|---|---|---|---|---|---|---|---|---|---|---|---|---|---|---|---|---|---|---|---|---|---|---|
| | 03h | 09h | 15h | 21h | 03h | 09h | 15h | 21h | 03h | 09h | 15h | 21h | 03h | 09h | 15h | 21h | 03h | 09h | 15h | 21h | 03h | 09h | 15h | 21h | 03h | 09h | 15h | 21h |
| Météo | | | | | | | | | | | | | | | | | | | | | | | | | | | | |
| Vent (km/h) | 55 | 55 | 30 | 50 | 25 | 20 | 40 | 50 | 30 | 20 | 20 | 15 | 10 | 15 | 20 | 15 | 15 | 10 | 45 | 35 | 40 | 65 | 60 | 55 | 40 | 30 | 40 | 20 |
| à 3000m | | | | | | | | | | | | | | | | | | | | | | | | | | | | |
| Vent (km/h) | 10 | 10 | 15 | 10 | 10 | 15 | 10 | 10 | 10 | 5 | 5 | 5 | 2 | 5 | 5 | 5 | 5 | 5 | 15 | 10 | 20 | 15 | 15 | 5 | 10 | 5 | 10 | 5 |
| à 1500m | | | | | | | | | | | | | | | | | | | | | | | | | | | | |

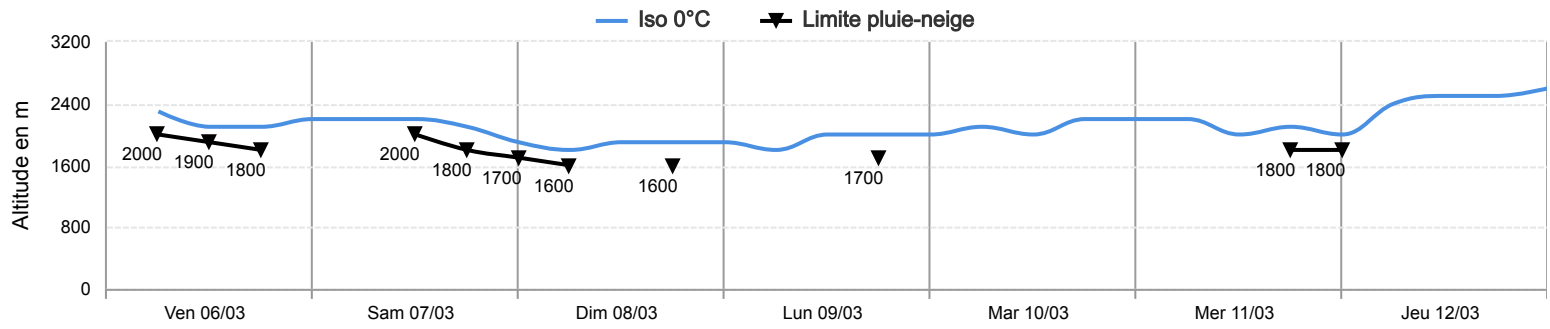


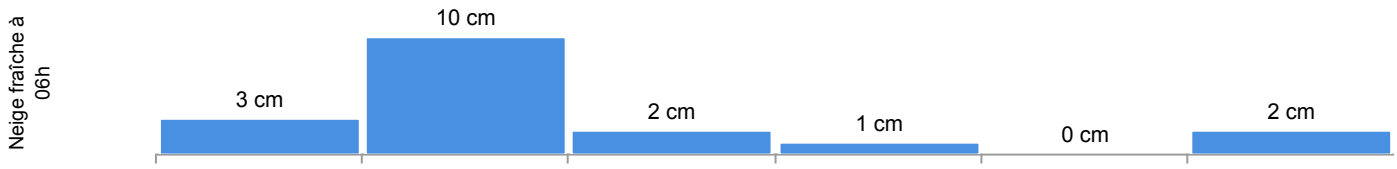


| Risque d'avalanche | ven. 06/03 | sam. 07/03 | dim. 08/03 | lun. 09/03 | mar. 10/03 | mer. 11/03 | jeu. 12/03 |
|---|---|---|---|---|---|---|---|
| | 2 | 2 | 2 | 2 | 2 | 2 | 2 |

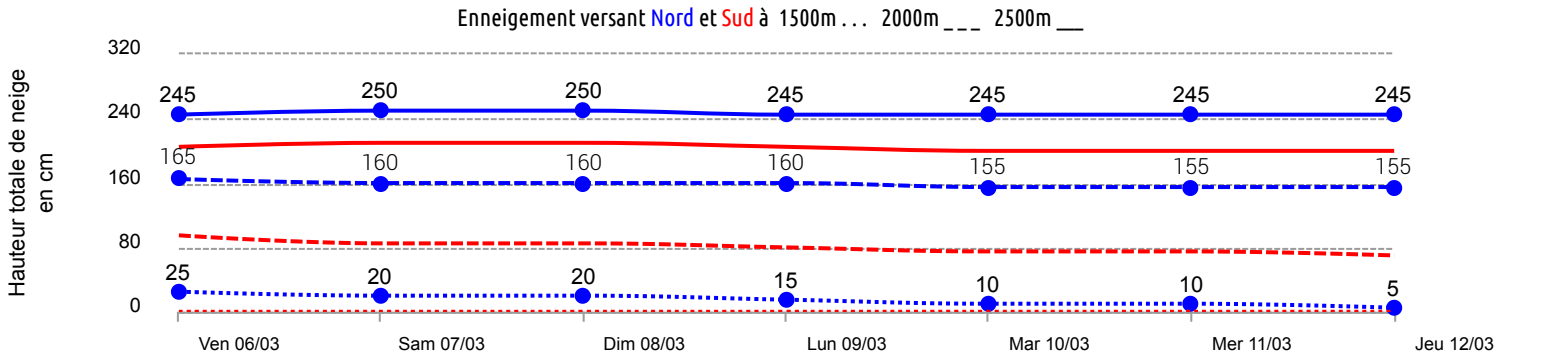


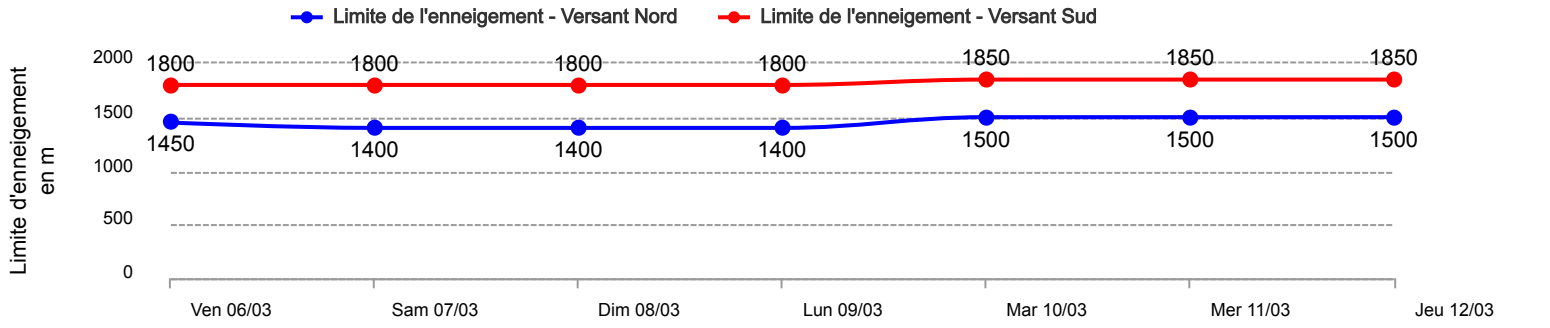


Pour consulter la vigilance en cours, veuillez vous rendre sur le site https://vigilance.meteofrance.fr/fr


Météo-France - 73 avenue de Paris, 94165 Saint-Mandé cedex - Contact : contact@meteo.fr



Rédigé par Météo-France avec la contribution des observateurs du réseau nivo-météorologiques. Partenariat : ANMSM (Maires de Stations de Montagne), DSF (Domaines Skiables de France), ADSP (Directeurs de Pistes et de la Sécurité des Stations de Sports d'Hiver) et autres acteurs de la montagne.



Bulletin neige & avalanches par téléphone au
0 892 68 10 20 Service 0,35 € / min + prix appel