Bulletin d'estimation du risque d'avalanche

(valable en dehors des pistes balisées et ouvertes)

MASSIF : Capcir Puymorens

Rédigé le jeudi 12 mars 2026 à 16h

Estimation des risques pour le : VENDREDI 13 MARS

QUELQUES PLAQUES EN ALTITUDE, AVALANCHE DE NEIGE HUMIDE EN JOURNÉE.

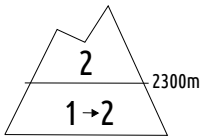

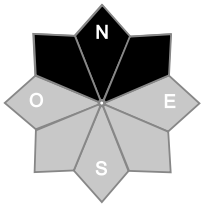

Au-dessus de 2300m indice de risque limité, plus bas indice faible évoluant en limité.

Départs spontanés : départs en avalanches de fond au soleil principalement

Déclenchements provoqués : plaques à vent de faible épaisseur au delà de 2300 m en versant nord facilement déclenchables.

Indices de risque : 5 très fort - 4 fort - 3 marqué - 2 limité - 1 faible -- En noir : les pentes les plus dangereuses

Stabilité du manteau neigeux

Situation avalancheuse typique : avalanches de fond neige ventée

Déclenchements provoqués :
Plaques à vent peu épaisses, mais facilement déclenchables, dans les versants nord bien raides au-dessus de 2300 m, surtout sous les corniches près des crêtes.
Le vent d'ouest à nord-ouest à en effet par endroits bien chargé les pentes sommitales.
Les déclenchements éventuels génèrent des avalanches de taille petite à moyenne, pouvant aller jusqu'en bas des pentes très redressées.
Observables : fissures devant les skis, neige de surface changeante et travaillée par le vent, transport de neige par le vent.

Départs spontanés :
Activité faible avec le bon regel du petit matin, puis reprenant au fil de la journée avec le soleil et la hausse du mercure. Rares avalanches de neige humide avec cassure linéaire, souvent de fond sur les pentes raides favorables (pentes herbeuses ou dalles rocheuses) possibles en toutes orientations, et à toute altitude plein sud. Avalanches de taille moyenne, rarement grande au-dessus de 2000m.
De nombreuses fissures ou gueules de baleines, signes précurseurs de telles avalanches, sont fréquemment observables dans les pentes concernées.
Des coulées en neige humide avec départs ponctuels sont également à attendre au fil de la journée dans les pentes raides des secteurs ensoleillés.

Autre : Des ruptures de corniches parfois larges et épaisses sont toujours possibles à proximité des crêtes.

Qualité de la neige

Enneigement :
L'enneigement est nettement excédentaire dès la moyenne montagne grâce à la succession de nombreuses perturbations neigeuses en janvier/février Les vallons ombragés sont encore bien enneigés notamment en versant est et nord. Il est en général possible de chausser dès 1600/1900 m d'altitude. La limite skiable remonte de jour en jour dans les pentes ensoleillées.

Qualité de la neige :
Conditions printanières, avec toutefois un peu de neige poudreuse en surface résistant dans les combes très ombragées ou orientées nord au-delà de 1900/2000 m.
A plus basse altitude et dans les autres versants, très bon regel nocturne et neige dure au petit matin, devenant meuble et humide en journée, voire très humide ou pourrie au soleil en dessous de 2000 m.

Aperçu météo pour le vendredi 13 mars

nuit	matin	après-midi	soir

Très belle journée ensoleillée avant une dégradation neigeuse en seconde partie de nuit suivante.

Pluie-Neige				
Iso 0 °C	2 600 m	2 600 m	2 700 m	2 600 m
Vent 2000 m	↘ 20 km/h	→ 25 km/h	↗ 25 km/h	↗ 35 km/h
Vent 3000 m	↘ 35 km/h	↗ 35 km/h	↗ 40 km/h	→ 50 km/h

Épaisseur de neige hors-piste

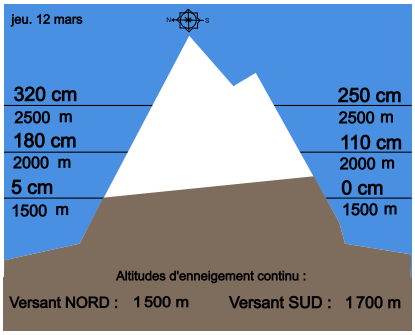

Précipitations à 1800 m

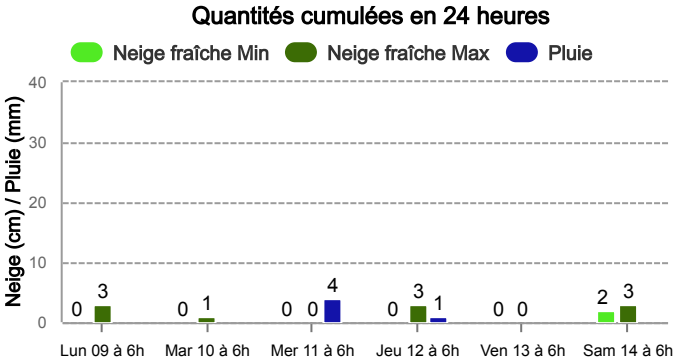

Tendance du samedi 14 mars

Indice de risque marqué

Hausse du risque accidentel dès la moyenne montagne avec les chutes de neige attendues la nuit suivante puis en journée de samedi.

Pour consulter la vigilance en cours, veuillez vous rendre sur le site https://vigilance.meteofrance.fr/fr

Météo-France - 73 avenue de Paris, 94165 Saint-Mandé cedex - Contact : contact@meteo.fr

Rédigé par Météo-France avec la contribution des observateurs du réseau nivo-météorologiques. Partenariat : ANMSM (Maires de Stations de Montagne), DSF (Domaines Skiables de France), ADSP (Directeurs de Pistes et de la Sécurité des Stations de Sports d'Hiver) et autres acteurs de la montagne.

Bulletin neige & avalanches par téléphone au **0 892 68 10 20** Service 0,35 € / min + prix appel

RÉPUBLIQUE FRANÇAISE
Liberté Égalité Fraternité

METEO FRANCE
À VOS CÔTÉS, DANS UN CLIMAT QUI CHANGE

Bulletin d'estimation du risque d'avalanche

(valable en dehors des pistes balisées et ouvertes)

MASSIF : Capcir Puymorens

Rédigé le jeudi 12 mars 2026 à 16h

Conditions nivo-météo des 7 derniers jours

	ven. 06/03				sam. 07/03				dim. 08/03				lun. 09/03				mar. 10/03				mer. 11/03				jeu. 12/03			
	03h	09h	15h	21h	03h	09h	15h	21h	03h	09h	15h	21h	03h	09h	15h	21h	03h	09h	15h	21h	03h	09h	15h	21h	03h	09h	15h	21h
Météo																												
Vent (km/h)	45	50	55	40	40	40	30	25	30	25	25	20	20	15	15	15	15	15	20	15	15	25	40	55	45	35	30	30
à 3000m																												
Vent (km/h)	25	35	35	30	25	30	20	15	20	20	15	10	10	10	10	5	5	5	10	10	10	10	25	35	30	20	20	15
à 2000m																												

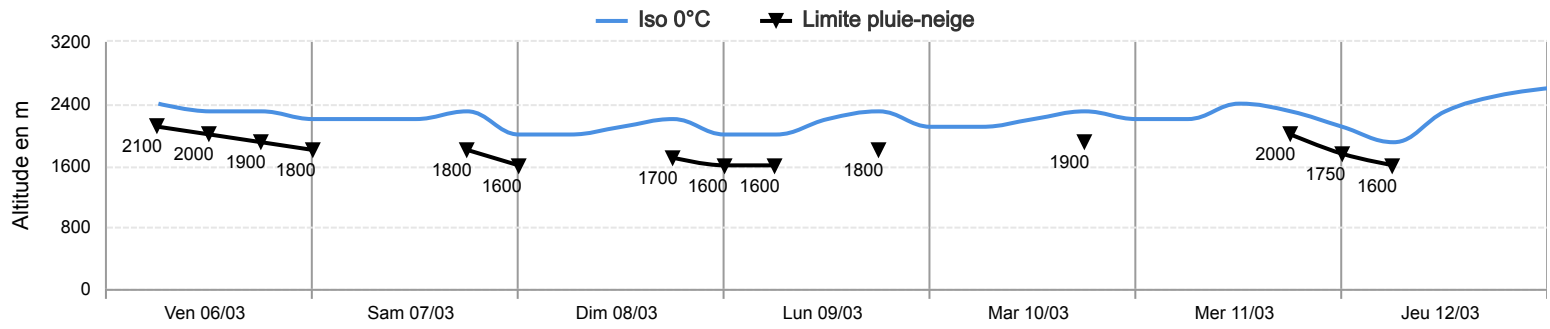

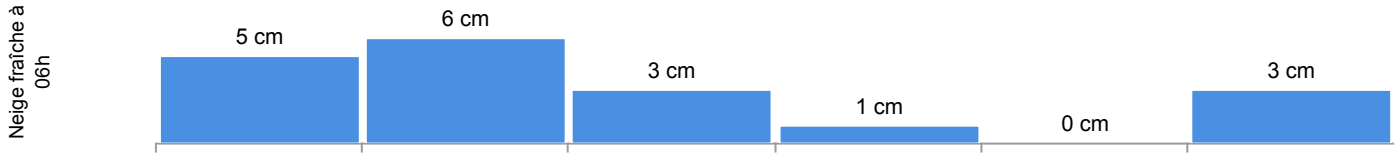

Risque d'avalanche							
	3	3	3	3	2	2	2
	ven. 06/03	sam. 07/03	dim. 08/03	lun. 09/03	mar. 10/03	mer. 11/03	jeu. 12/03

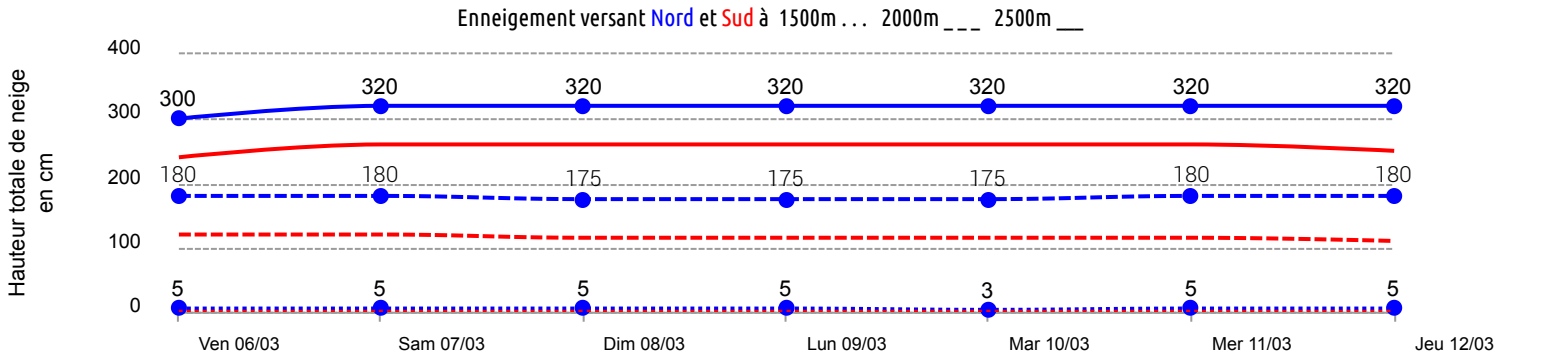

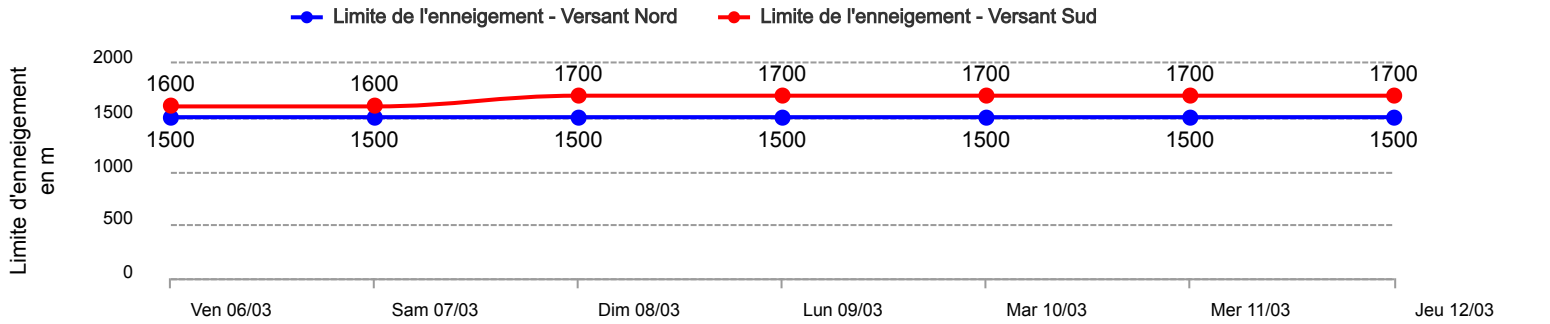

Pour consulter la vigilance en cours, veuillez vous rendre sur le site https://vigilance.meteofrance.fr/fr

Météo-France - 73 avenue de Paris, 94165 Saint-Mandé cedex - Contact : contact@meteo.fr

Rédigé par Météo-France avec la contribution des observateurs du réseau nivo-météorologiques. Partenariat : ANMSM (Maires de Stations de Montagne), DSF (Domaines Skiables de France), ADSP (Directeurs de Pistes et de la Sécurité des Stations de Sports d'Hiver) et autres acteurs de la montagne.

Bulletin neige & avalanches par téléphone au
0 892 68 10 20 Service 0,35 € / min + prix appel