Bulletin d'estimation du risque d'avalanche
(valable en dehors des pistes balisées et ouvertes)
MASSIF : Chablais

Rédigé le jeudi 12 mars 2026 à 16h

Estimation des risques pour le : VENDREDI 13 MARS

ENCORE DE PETITES INSTABILITÉS DANS LA NEIGE RÉCENTE ET DE NOUVELLES SOUS LE VENT DE SUD-OUEST

2

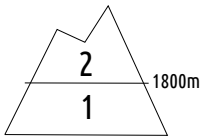

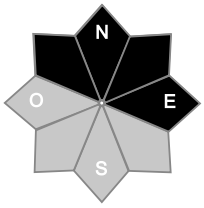

Au-dessus de 1800m indice de risque limité, plus bas indice faible.

Départs spontanés : Rares plaques dues au vent de sud-ouest

Déclenchements provoqués : Plaques friables dans la neige récente et de nouvelles plaques à vent en formation

Indices de risque : 5 très fort - 4 fort - 3 marqué - 2 limité - 1 faible -- En noir : les pentes les plus dangereuses

Stabilité du manteau neigeux

Situation avalancheuse typique : neige fraîche — neige ventée

Déclenchements provoqués :
* Au-dessus de 1800 m : quelques plaques friables dans la neige récente sont encore présentes dans les versants ombragés. Au-dessus de 2400 m, ces plaques friables sont plus réactives, car elles reposent sur des grains anguleux. En journée, le vent de sud-ouest se lève et forme de nouvelles plaques à vent, elles sont situées au voisinage des crêtes. Taille 1 (petite) à 2 (moyenne)
Facteur aggravant : au-dessus de 2200 m, présence d'une sous-couche fragile persistante enfouie. Difficile à déclencher. Une première avalanche dans la neige récente peut dans de rares cas déclencher en cascade cette couche fragile. Taille 2 (moyenne) avec d'épaisses cassures.
* Dans les versants ensoleillés et peu ventés, coulées de neige humide sous les skis. Taille 1 (petite).

Départs spontanés :
* Au-dessus de 1800 dans les versants ombragés : rares départs en plaque dans la neige récente à cause du vent en journée. Taille 1, voir 2.
* Rares départs ponctuels de neige humide dans les versants sud-est à ouest dans l'après-midi avec le réchauffement (et dans les secteurs moins ventés). Taille 1.
* Plaques de fond, de jour comme de nuit, dans les pentes lisses et raides (zones herbeuses, dalles rocheuses). Plutôt sous 2300 m. Taille 1 à 2 avec l'épais manteau neigeux.

Qualité de la neige

Enneigement :
Pour la saison, l'enneigement est correct.
On peut chausser les skis vers 1200/1300 m en nord, est et ouest et 1400/1700 m en sud.
Grosses corniches encore présentes.

Qualité de la neige vendredi :
* Très bon regel cette nuit.
* Sous 2400 m dans les secteurs ensoleillés neige croutée le matin et décaille au fil du soleil.
* Au-dessus de 2400 m et en ubacs, neige récente, ventée près des crêtes.

Aperçu météo pour le vendredi 13 mars

	nuit	matin	après-midi	soir
Belle journée, fin voile, le vent de sud-ouest souffle en journée. +5°C à 2000 m.				
Pluie-Neige				
Iso 0 °C	2 300 m	2 300 m	2 300 m	2 000 m
Vent 2000 m	25 km/h	35 km/h	40 km/h	55 km/h
Vent 2500 m	40 km/h	45 km/h	55 km/h	70 km/h

Épaisseur de neige hors-piste

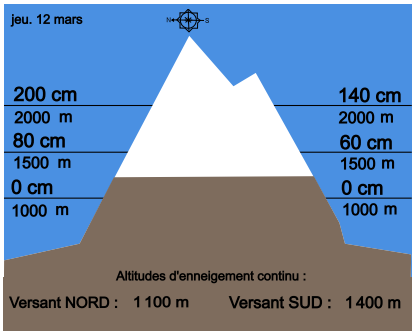

Précipitations à 1800 m

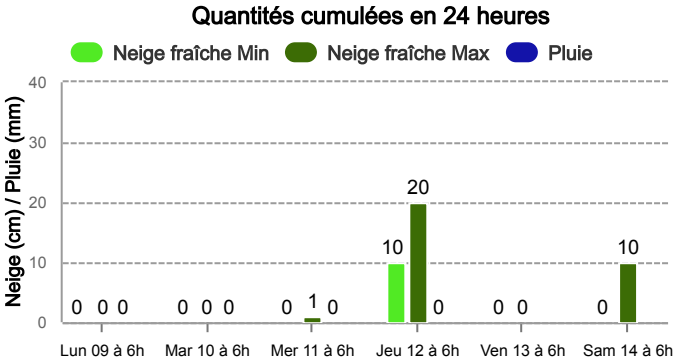

Tendance du samedi 14 mars

3

Indice de risque marqué

Risque en hausse avec l'arrivée d'une perturbation dans la nuit de vendredi à samedi. Nouvelles instabilités dans la neige fraiche, entre +15/30 cm.

Pour consulter la vigilance en cours, veuillez vous rendre sur le site https://vigilance.meteofrance.fr/fr

Météo-France - 73 avenue de Paris, 94165 Saint-Mandé cedex - Contact : contact@meteo.fr

Rédigé par Météo-France avec la contribution des observateurs du réseau nivo-météorologiques. Partenariat : ANMSM (Maires de Stations de Montagne), DSF (Domaines Skiables de France), ADSP (Directeurs de Pistes et de la Sécurité des Stations de Sports d'Hiver) et autres acteurs de la montagne.

Bulletin neige & avalanches par téléphone au 0 892 68 10 20 Service 0,35 € / min + prix appel

RÉPUBLIQUE FRANÇAISE
Liberté Égalité Fraternité

METEO FRANCE
À VOS CÔTÉS, DANS UN CLIMAT QUI CHANGE

Bulletin d'estimation du risque d'avalanche

(valable en dehors des pistes balisées et ouvertes)

MASSIF : Chablais

Rédigé le jeudi 12 mars 2026 à 16h

Conditions nivo-météo des 7 derniers jours

	ven. 06/03				sam. 07/03				dim. 08/03				lun. 09/03				mar. 10/03				mer. 11/03				jeu. 12/03			
	03h	09h	15h	21h	03h	09h	15h	21h	03h	09h	15h	21h	03h	09h	15h	21h	03h	09h	15h	21h	03h	09h	15h	21h	03h	09h	15h	21h
Météo																												
Vent (km/h)	10	25	20	15	10	20	5	20	10	10	10	15	10	10	10	15	15	30	40	40	40	50	60	45	30	20	5	10
à 2500m																												
Vent (km/h)	5	20	15	10	5	10	5	10	5	5	5	5	5	5	5	10	10	20	30	30	30	40	50	30	20	10	5	5
à 2000m																												

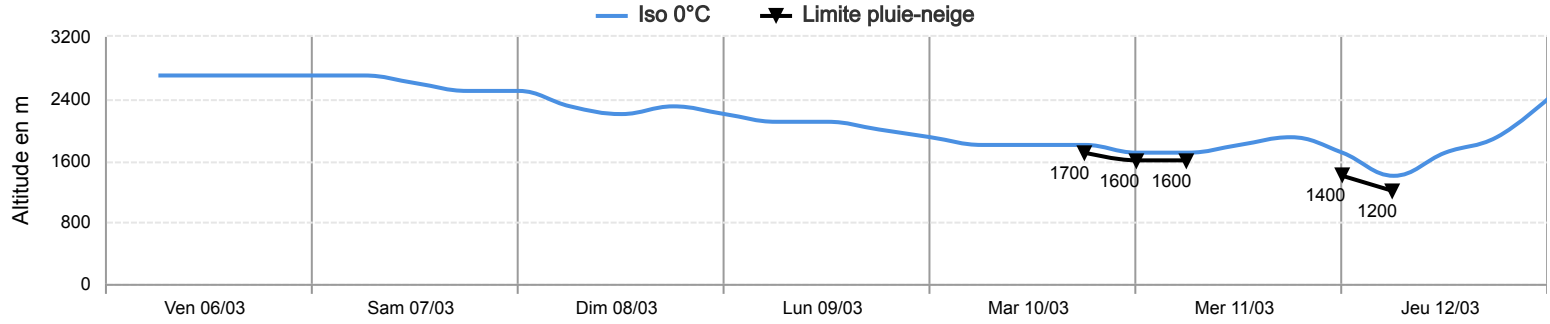

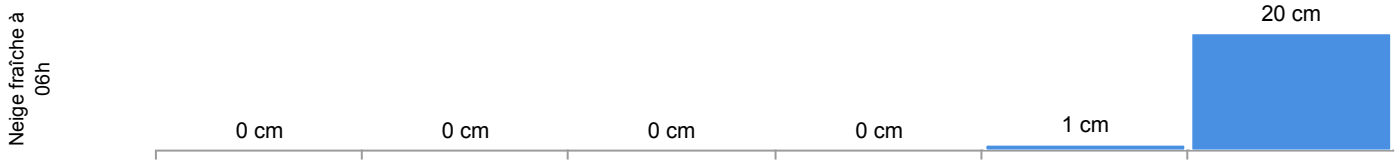

Risque d'avalanche	ven. 06/03	sam. 07/03	dim. 08/03	lun. 09/03	mar. 10/03	mer. 11/03	jeu. 12/03
	2	2	2	2	2	1	2

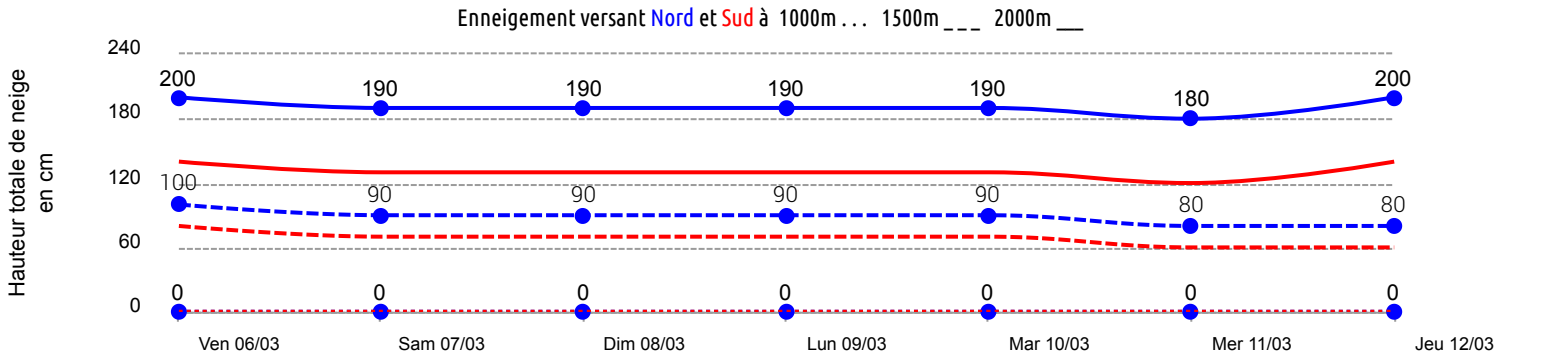

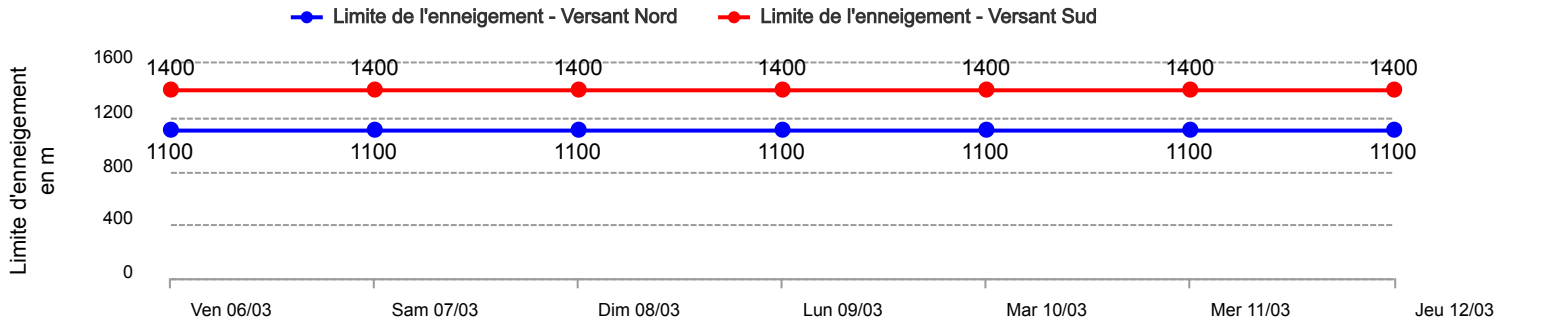

Pour consulter la vigilance en cours, veuillez vous rendre sur le site https://vigilance.meteofrance.fr/fr

Météo-France - 73 avenue de Paris, 94165 Saint-Mandé cedex - Contact : contact@meteo.fr

Rédigé par Météo-France avec la contribution des observateurs du réseau nivo-météorologiques. Partenariat : ANMSM (Maires de Stations de Montagne), DSF (Domaines Skiables de France), ADSP (Directeurs de Pistes et de la Sécurité des Stations de Sports d'Hiver) et autres acteurs de la montagne.

Bulletin neige & avalanches par téléphone au
0 892 68 10 20 Service 0,35 € / min + prix appel