Bulletin d'estimation du risque d'avalanche
(valable en dehors des pistes balisées et ouvertes)

MASSIF : Chartreuse

Rédigé le jeudi 12 mars 2026 à 16h

Estimation des risques pour le : VENDREDI 13 MARS

EN FIN D'APRES-MIDI, POSSIBLE FORMATION DE PLAQUES VERS LES HAUTES CRETES...

2

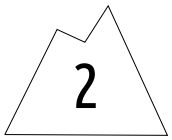

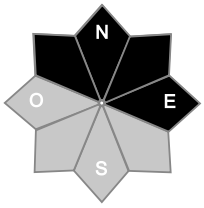

Nord d'altitude

Indices de risque : 5 très fort - 4 fort - 3 marqué - 2 limité - 1 faible -- En noir : les pentes les plus dangereuses

Indice de risque limité.

Départs spontanés : Au soleil, rares coulées de surface. En pentes herbeuses rares avalanche de fond (glissement au terrain ?)

Déclenchements provoqués : Plutôt en fin d'après-midi/soirée sous le vent de Sud-Sud-Ouest : formation de quelques plaques en faces Nord d'altitude...

Stabilité du manteau neigeux

Situation avalancheuse typique : neige ventée avalanches de fond

Neige récente plutôt stabilisée vendredi matin. Mais en cours d'après-midi, renforcement du vent de Sud à Sud-Ouest qui pourra former quelques plaques en faces Nord sommitales (là où la neige est restée poudreuse ?).

Déclenchements provoqués :

Vendredi matin peu de risque de plaque ou de rares instabilités vers les hautes crêtes. Risque de cassure peu de large de plaquefriable en faces Nord ? Localement encore 30 cm mobilisables.

En cours d'après-midi/soirée le vent de Sud à Sud-Ouest va se lever et pourra forme quelques nouvelles plaques instables, où la neige est restée poudreuse, soit en Nord à Nord-Est d'altitude...

En faces ensoleillées pas de risque de plaque. A la faveur du redoux diurne, plutôt un risque (limité) de coulée ponctuelle de neige humide sous les skis (glissant sur l'ancienne couche)

Départs spontanés :

Peu d'activité attendue vendredi. Le matin, bon regel, neige croutée. Pas mal de pentes ont déjà coulées.

Puis à la faveur du soleil, quelques nouvelles petites coulées (superficielles, sur 10/20 cm) seraient possibles en pentes humidifiées.

Enfin dans une très rare pente herbeuse fissurée/secteur de reptation, une avalanche de fond, glissant au terrain n'est pas exclue (de taille moyenne).

Qualité de la neige

Qualification de l'enneigement : L'enneigement est bon pour la saison en versants ombragés au dessus de 1500 m, il est correct encore en Sud...

Limites skiables : Vers 1200/1600m hors sapins, guère de sous couche plus bas.

Qualité de la neige vendredi : Neige récente croutée (en surface) par regel, des restes d'escargots ou coulées dans les pentes raides... Humidification assez rapide au soleil. Vers les sommets neige plus soufflée, encore un peu de poudreuse en Nord sommital...

Aperçu météo pour le vendredi 13 mars

	nuit	matin	après-midi	soir

Nuit claire et fraîche. Vendredi ensoleillé, doux au soleil. Le ciel se voile en cours d'après-midi et le vent se renforce progressivement...

Pluie-Neige				
Iso 0 °C	2 000 m	2 400 m	2 400 m	2 300 m
Vent 1500 m	↓ 10 km/h	↑ 20 km/h	↗ 35 km/h	↗ 45 km/h
Vent 2000 m	↗ 25 km/h	↗ 25 km/h	↗ 45 km/h	↗ 60 km/h

Épaisseur de neige hors-piste

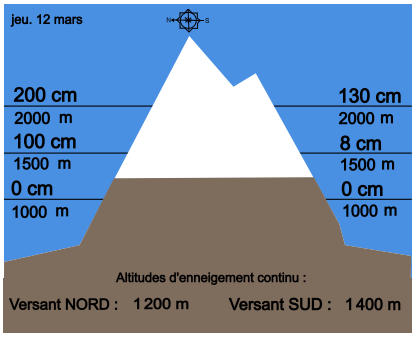

Précipitations à 1800 m

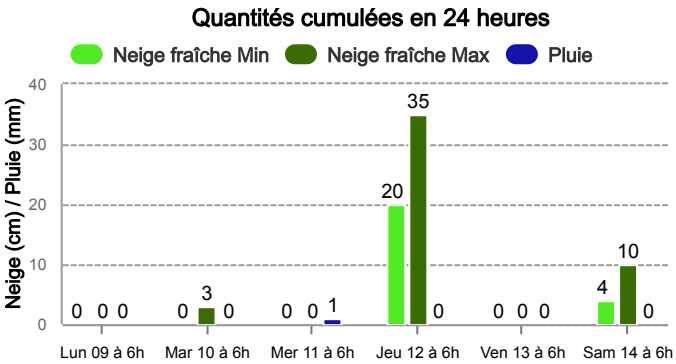

Tendance du samedi 14 mars

3

Indice de risque marqué

Samedi, temps neigeux du matin à l'après-midi donnant jusque 25/30 cm en peu de temps.

Risque d'avalanche devenant marqué en cours de journée...

Pour consulter la vigilance en cours, veuillez vous rendre sur le site https://vigilance.meteofrance.fr/fr

Météo-France - 73 avenue de Paris, 94165 Saint-Mandé cedex - Contact : contact@meteo.fr

Rédigé par Météo-France avec la contribution des observateurs du réseau nivo-météorologiques. Partenariat : ANMSM (Maires de Stations de Montagne), DSF (Domaines Skiables de France), ADSP (Directeurs de Pistes et de la Sécurité des Stations de Sports d'Hiver) et autres acteurs de la montagne.

Bulletin neige & avalanches par téléphone au

0 892 68 10 20 Service 0,35 € / min + prix appel

RÉPUBLIQUE FRANÇAISE
Liberté Égalité Fraternité

METEO FRANCE
À VOS CÔTÉS, DANS UN CLIMAT QUI CHANGE

Bulletin d'estimation du risque d'avalanche
(valable en dehors des pistes balisées et ouvertes)
MASSIF : Chartreuse

Rédigé le jeudi 12 mars 2026 à 16h

Conditions nivo-météo des 7 derniers jours

	ven. 06/03				sam. 07/03				dim. 08/03				lun. 09/03				mar. 10/03				mer. 11/03				jeu. 12/03			
	03h	09h	15h	21h	03h	09h	15h	21h	03h	09h	15h	21h	03h	09h	15h	21h	03h	09h	15h	21h	03h	09h	15h	21h	03h	09h	15h	21h
Météo																												
Vent (km/h)	5	5	5	5	5	5	5	5	15	5	15	10	20	30	35	45	30	20	25	30	30	30	35	45	45	30	20	10
à 2000m																												
Vent (km/h)	0	0	5	5	5	5	10	0	5	10	10	10	10	15	15	30	20	15	20	15	20	25	30	20	25	20	15	5
à 1500m																												

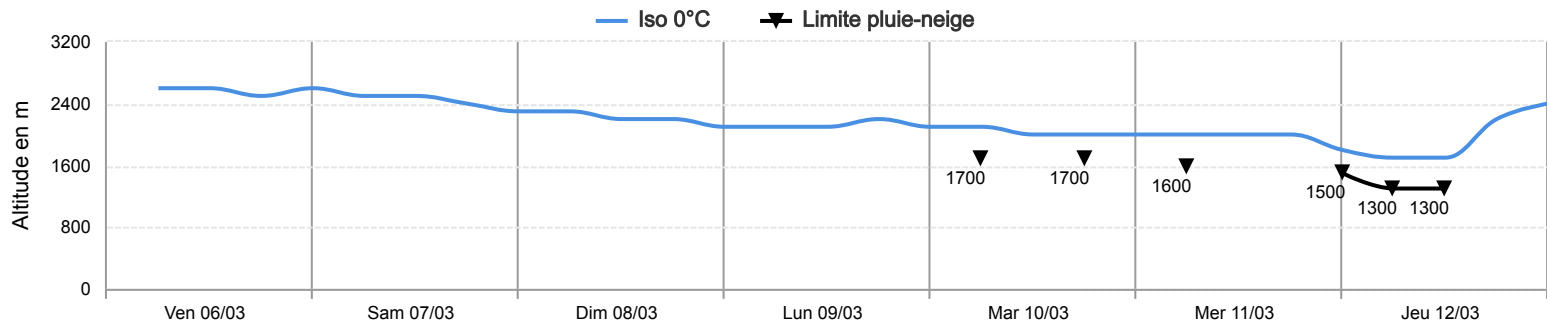

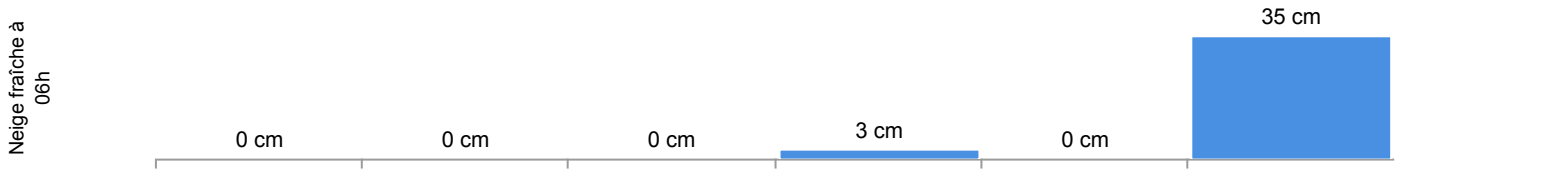

Risque d'avalanche	ven. 06/03	sam. 07/03	dim. 08/03	lun. 09/03	mar. 10/03	mer. 11/03	jeu. 12/03
	2	2	1	1	1	1	2

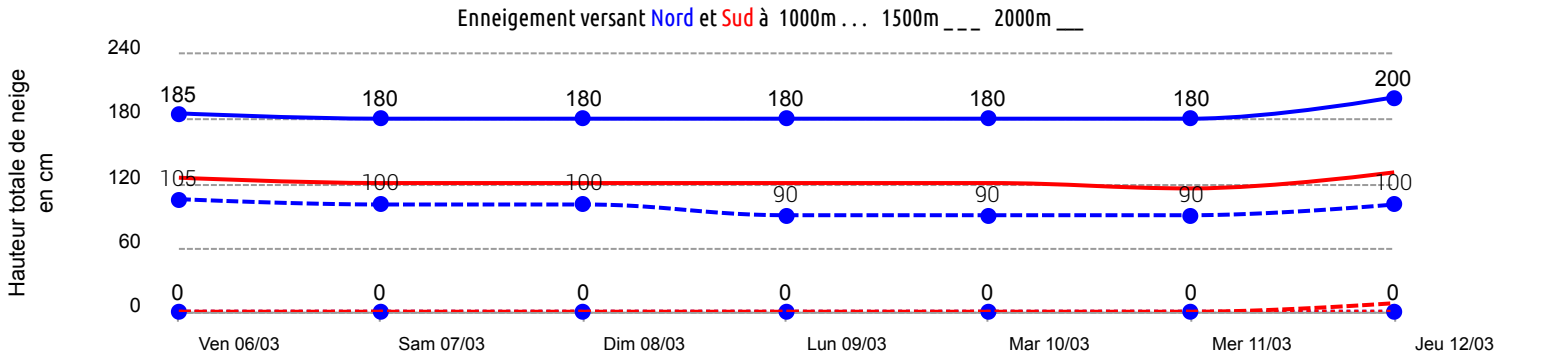

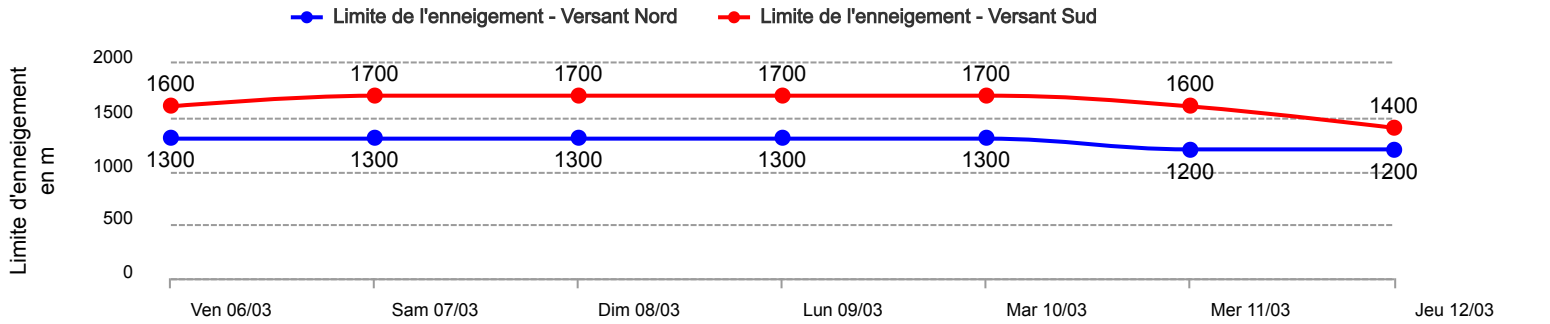

Pour consulter la vigilance en cours, veuillez vous rendre sur le site https://vigilance.meteofrance.fr/fr

Météo-France - 73 avenue de Paris, 94165 Saint-Mandé cedex - Contact : contact@meteo.fr

Rédigé par Météo-France avec la contribution des observateurs du réseau nivo-météorologiques. Partenariat : ANMSM (Maires de Stations de Montagne), DSF (Domaines Skiables de France), ADSP (Directeurs de Pistes et de la Sécurité des Stations de Sports d'Hiver) et autres acteurs de la montagne.

Bulletin neige & avalanches par téléphone au
0 892 68 10 20 Service 0,35 € / min + prix appel