Bulletin d'estimation du risque d'avalanche

(valable en dehors des pistes balisées et ouvertes)

MASSIF : Grandes-Rousses

Rédigé le jeudi 12 mars 2026 à 16h

Estimation des risques pour le : VENDREDI 13 MARS

EN FIN D'APRES-MIDI/SOIREE, POSSIBLE FORMATION DE NOUVELLES PLAQUES INSTABLES EN VERSANTS FROIDS D'ALTITUDE...

3

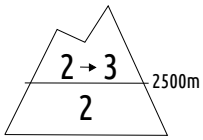

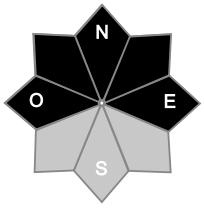

Sous vent de SSO

Au-dessus de 2500m indice de risque limité évoluant en marqué, plus bas indice limité.

Départs spontanés : Au soleil, rares coulées de surface. En pentes herbeuses rares avalanche de fond (glissement au terrain ?)

Déclenchements provoqués : Le matin rares plaques en faces d'altitude. L'après-midi / le soir sous le vent de Sud à Sud-Ouest formation de nouvelles plaques instables en faces Nord (là où la neige est restée poudreuse)...

Indices de risque : 5 très fort - 4 fort - 3 marqué - 2 limité - 1 faible -- En noir : les pentes les plus dangereuses

Stabilité du manteau neigeux

Situation avalancheuse typique : neige ventée couche fragile persistante

Neige récente mieux stabilisée vendredi matin (rares plaques en nord d'altitude). En fin d'après-midi, renforcement du vent de Sud à Sud-Ouest qui pourra former quelques plaques instables en faces Nord d'altitude (là où la neige est restée poudreuse).

Déclenchements provoqués :

Vendredi matin/midi peu de risque de plaque ou de rares instabilités vers les hautes crêtes en faces Nord ? Plaques plutôt friables, localement encore 20 cm mobilisables sur l'Ouest du massif.

En fin d'après-midi/soirée le vent de Sud à Sud-Ouest va se lever et pourra former quelques nouvelles plaques instables, là où la neige est restée poudreuse, surtout en Nord à Est d'altitude (vent plus soutenu au dessus de 2300/2500m environ)...

Noter qu'une sous-couche plus fragile est parfois enfouie en pentes "froides", favorisant une cassure plus large, voire à distance. Signes observables : Transports de neige, fissures sous les skis.

En faces ensoleillées peu de risque de plaque. A la faveur du redoux diurne, plutôt un risque (limité) de coulée ponctuelle de neige humide sous les skis (glissant sur l'ancienne couche)

Départs spontanés :

Peu d'activité attendue vendredi. Le matin, bon regel, neige croutée. Pas mal de pentes ont déjà bougées.

Puis à la faveur du doux soleil, quelques nouvelles petites coulées (superficielles, sur 10/15 cm) seraient possibles en pentes humidifiées.

Dans une très rare pente herbeuse fissurée/secteur de reptation, une avalanche de fond, glissant au terrain n'est pas exclue (de taille moyenne), plutôt le soir ?

Qualité de la neige

Qualification de l'enneigement : L'enneigement est bon pour la saison en versants ombragés au dessus de 1600 m, voire abondant en combes d'altitude. En Sud l'enneigement a régressé mais demeure correct.

Limites skiables : Vers 1300/1700m hors sapins, guère de sous couche plus bas.

Qualité de la neige vendredi : En faces ensoleillées et sous 2200/2500m environ : neige récente croutée (en surface) par regel, des restes de coulées dans les pentes raides... Humidification assez rapide au soleil.

Vers les sommets neige plus soufflée, encore poudreuse en Nord d'altitude...

Aperçu météo pour le vendredi 13 mars

nuit	matin	après-midi	soir

Nuit claire et fraîche. Vendredi ensoleillé, doux au soleil. Le ciel se voile en cours d'après-midi et le vent se renforce progressivement...

Pluie-Neige				
Iso 0 °C	2 100 m	2 500 m	2 500 m	2 300 m
Vent 2000 m	↗ 10 km/h	↗ 10 km/h	↗ 45 km/h	↗ 60 km/h
Vent 3000 m	↑ 15 km/h	↗ 20 km/h	↗ 50 km/h	↗ 65 km/h

Épaisseur de neige hors-piste

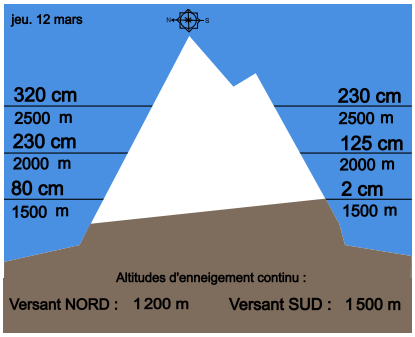

Précipitations à 1800 m

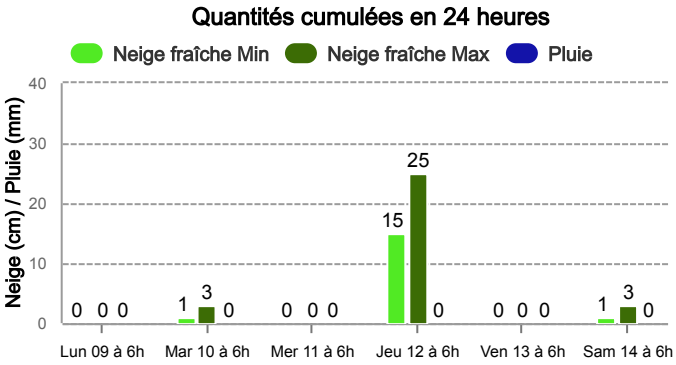

Tendance du samedi 14 mars

3 **Indice de risque marqué**

Samedi, temps neigeux du matin à l'après-midi donnant jusque 30 cm en peu de temps. Risque d'avalanche devenant franchement marqué en cours de journée, dans la plupart des pentes...

Pour consulter la vigilance en cours, veuillez vous rendre sur le site https://vigilance.meteofrance.fr/fr

Météo-France - 73 avenue de Paris, 94165 Saint-Mandé cedex - Contact : contact@meteo.fr

Rédigé par Météo-France avec la contribution des observateurs du réseau nivo-météorologiques. Partenariat : ANMSM (Maires de Stations de Montagne), DSF (Domaines Skiables de France), ADSP (Directeurs de Pistes et de la Sécurité des Stations de Sports d'Hiver) et autres acteurs de la montagne.

Bulletin neige & avalanches par téléphone au 0 892 68 10 20 Service 0,35 € / min + prix appel

RÉPUBLIQUE FRANÇAISE
Liberté Égalité Fraternité

METEO FRANCE
À VOS CÔTÉS, DANS UN CLIMAT QUI CHANGE

Bulletin d'estimation du risque d'avalanche

(valable en dehors des pistes balisées et ouvertes)

MASSIF : Grandes-Rousses

Rédigé le jeudi 12 mars 2026 à 16h

Conditions nivo-météo des 7 derniers jours

	ven. 06/03				sam. 07/03				dim. 08/03				lun. 09/03				mar. 10/03				mer. 11/03				jeu. 12/03			
	03h	09h	15h	21h	03h	09h	15h	21h	03h	09h	15h	21h	03h	09h	15h	21h	03h	09h	15h	21h	03h	09h	15h	21h	03h	09h	15h	21h
Météo																												
Vent (km/h)	20	25	20	20	10	10	15	15	25	15	15	15	15	20	35	40	35	35	20	15	20	30	35	25	40	50	20	10
à 3000m																												
Vent (km/h)	25	25	15	15	10	5	5	5	15	10	10	10	10	15	25	30	25	25	15	10	10	10	25	15	25	25	10	10
à 2000m																												

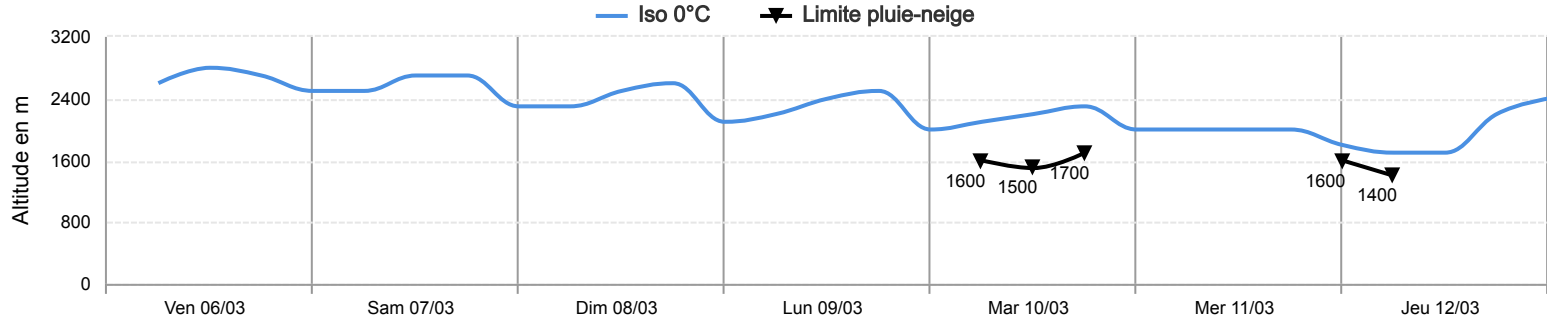

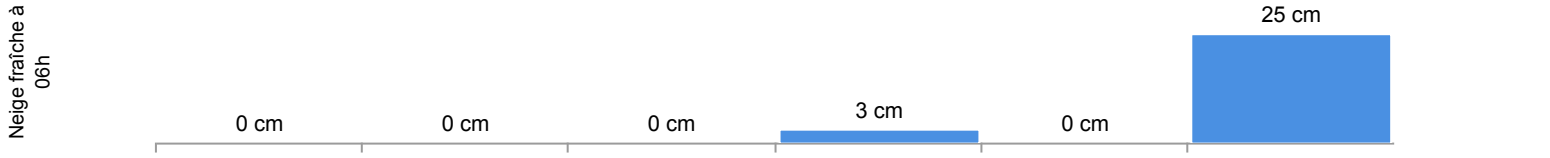

Risque d'avalanche	ven. 06/03	sam. 07/03	dim. 08/03	lun. 09/03	mar. 10/03	mer. 11/03	jeu. 12/03
	2	2	2	2	2	2	2

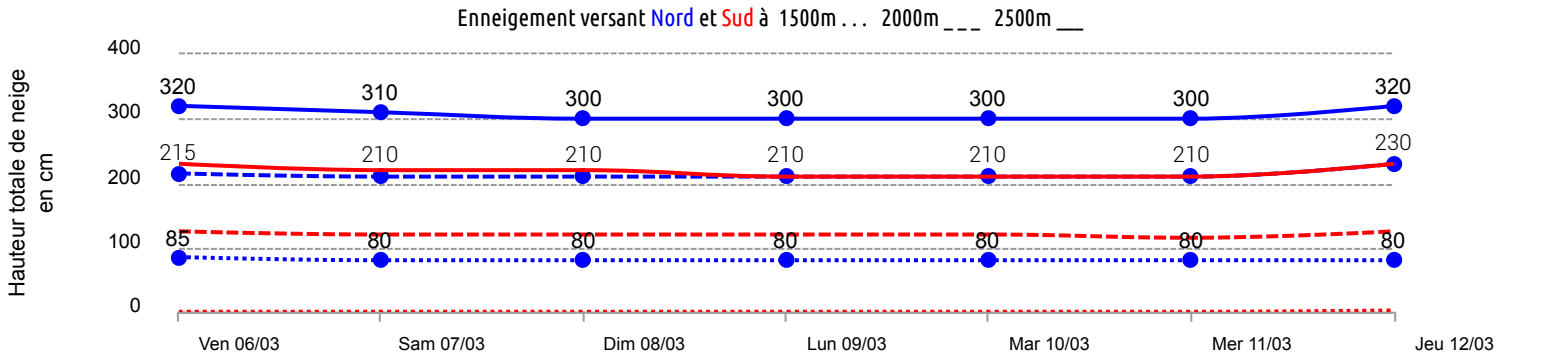

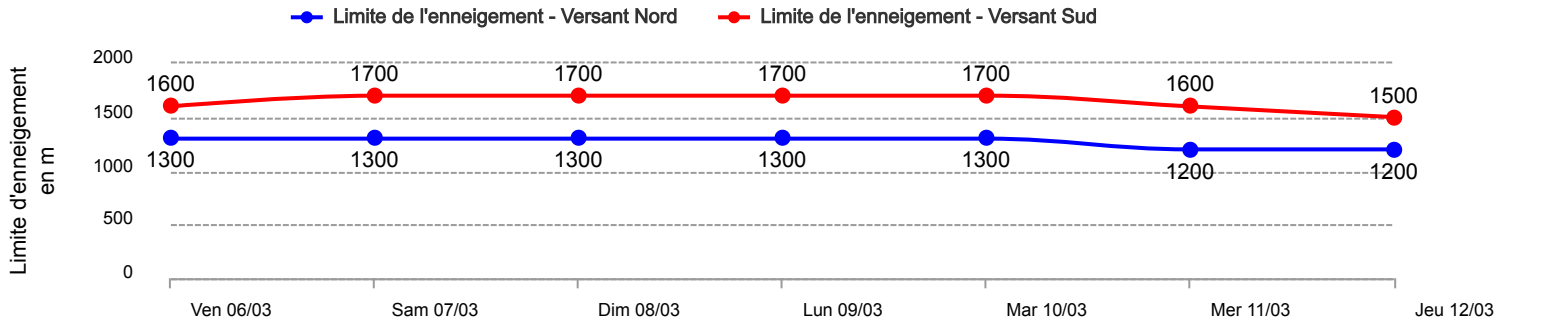

Pour consulter la vigilance en cours, veuillez vous rendre sur le site https://vigilance.meteofrance.fr/fr

Météo-France - 73 avenue de Paris, 94165 Saint-Mandé cedex - Contact : contact@meteo.fr

Rédigé par Météo-France avec la contribution des observateurs du réseau nivo-météorologiques. Partenariat : ANMSM (Maires de Stations de Montagne), DSF (Domaines Skiables de France), ADSP (Directeurs de Pistes et de la Sécurité des Stations de Sports d'Hiver) et autres acteurs de la montagne.

Bulletin neige & avalanches par téléphone au
0 892 68 10 20 Service 0,35 € / min + prix appel