Bulletin d'estimation du risque d'avalanche
(valable en dehors des pistes balisées et ouvertes)

MASSIF : Haut-Var Haut-Verdon

Rédigé le jeudi 12 mars 2026 à 16h

Estimation des risques pour le : VENDREDI 13 MARS

QUELQUES INSTABILITÉS EN ALTITUDE. HUMIDIFICATION SUPERFICIELLE

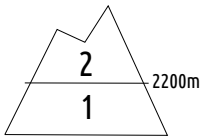

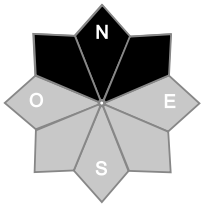

Au-dessus de 2200m indice de risque limité, plus bas indice faible.

Départs spontanés : éventuels départs ponctuels en neige humide

Déclenchements provoqués : quelques plaques superficielles faciles à déclencher

Indices de risque : 5 très fort - 4 fort - 3 marqué - 2 limité - 1 faible -- En noir : les pentes les plus dangereuses

Stabilité du manteau neigeux

Situation avalancheuse typique : neige ventée

Déclenchements provoqués :
- quelques plaques dans la neige récente ventée, essentiellement en ubac au-dessus de 2000/2200 m. Ces instabilités peuvent être déclenchées au passage d'un skieur, mais sont en général de petite taille, plus rarement moyenne.

Départs spontanés :
- éventuels départs ponctuels de petite taille, en neige récente s'humidifiant en pentes raides, près des rochers, au fil de la course du soleil.
- une avalanche de fond de taille moyenne n'est pas exclue en pentes d'un large secteur sud sur sol favorable (pentes herbeuses, dalles rocheuses).

Qualité de la neige

Enneigement plutôt excédentaire sur le Haut-Verdon, dans les normales pour le Haut Var.
Données observées : vers 2000 m, 179 cm en fond de vallon dans le Haut Verdon, 120 cm dans le Haut Var.

Enneigement skiable : vers 1400/1500 m en ubacs, 1800/1900 m en adrets peu pentus.

État de la neige en surface : neige récente, plus ou moins ventée, en ubacs au-dessus de 2000/2200 m, croutée en dessous ainsi que dans les adrets. Reprise de l'humidification au soleil en cours de journée. Sur les crêtes, d'anciennes corniches épaisses côtoient des zones dégarnies.

Aperçu météo pour le vendredi 13 mars

nuit	matin	après-midi	soir
Temps sec et bien ensoleillé. Vent faible.			

Pluie-Neige				
Iso 0 °C	2 200 m	2 200 m	2 300 m	2 100 m
Vent 2000 m	↓ 10 km/h	→ 5 km/h	↑ 15 km/h	↑ 10 km/h
Vent 3000 m	↓ 20 km/h	↘ 10 km/h	↗ 15 km/h	↑ 15 km/h

Épaisseur de neige hors-piste

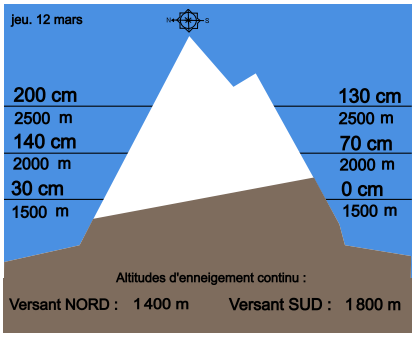

Précipitations à 1800 m

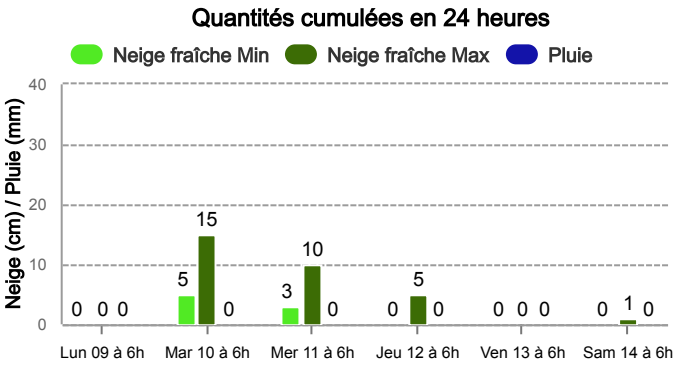

Tendance du samedi 14 mars

Indice de risque marqué

Risque en hausse. Formation de nouvelles instabilités avec les chutes de neige assez conséquentes ventées.

Pour consulter la vigilance en cours, veuillez vous rendre sur le site https://vigilance.meteofrance.fr/fr

Météo-France - 73 avenue de Paris, 94165 Saint-Mandé cedex - Contact : contact@meteo.fr

Rédigé par Météo-France avec la contribution des observateurs du réseau nivo-météorologiques. Partenariat : ANMSM (Maires de Stations de Montagne), DSF (Domaines Skiables de France), ADSP (Directeurs de Pistes et de la Sécurité des Stations de Sports d'Hiver) et autres acteurs de la montagne.

Bulletin neige & avalanches par téléphone au
0 892 68 10 20 Service 0,35 € / min + prix appel

RÉPUBLIQUE FRANÇAISE
Liberté Égalité Fraternité

METEO FRANCE
À VOS CÔTÉS, DANS UN CLIMAT QUI CHANGE

Bulletin d'estimation du risque d'avalanche

(valable en dehors des pistes balisées et ouvertes)

MASSIF : Haut-Var Haut-Verdon

Rédigé le jeudi 12 mars 2026 à 16h

Conditions nivo-météo des 7 derniers jours

	ven. 06/03				sam. 07/03				dim. 08/03				lun. 09/03				mar. 10/03				mer. 11/03				jeu. 12/03			
	03h	09h	15h	21h	03h	09h	15h	21h	03h	09h	15h	21h	03h	09h	15h	21h	03h	09h	15h	21h	03h	09h	15h	21h	03h	09h	15h	21h
Météo																												
Vent (km/h)	65	60	55	50	35	30	25	15	20	15	15	15	15	20	30	50	40	25	20	20	15	30	45	40	40	30	20	20
à 3000m																												
Vent (km/h)	45	40	40	35	25	20	15	10	15	10	15	10	15	15	20	35	5	15	20	5	5	10	20	15	25	25	20	10
à 2000m																												

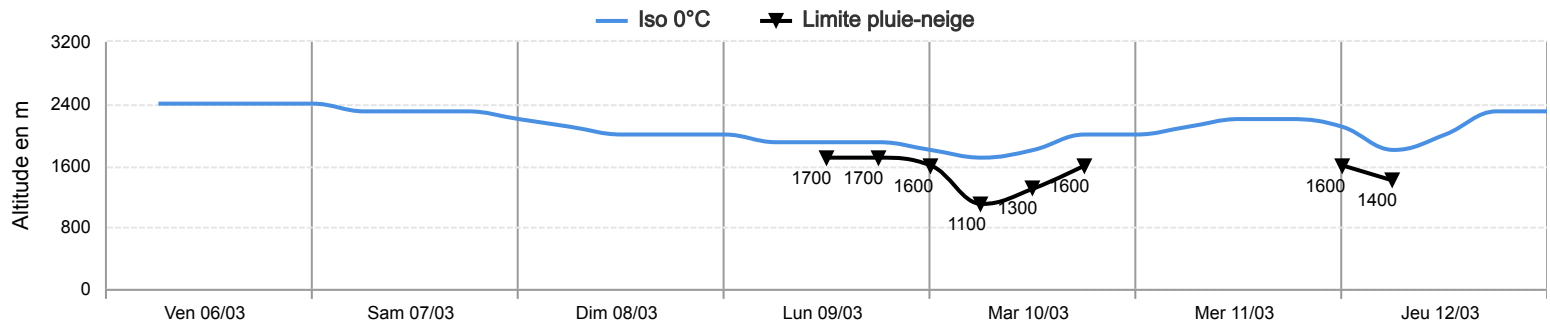

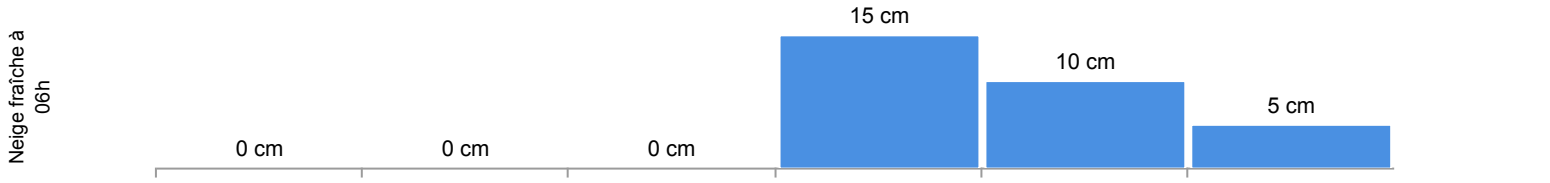

Risque d'avalanche	ven. 06/03	sam. 07/03	dim. 08/03	lun. 09/03	mar. 10/03	mer. 11/03	jeu. 12/03
	2	2	2	1	2	2	2

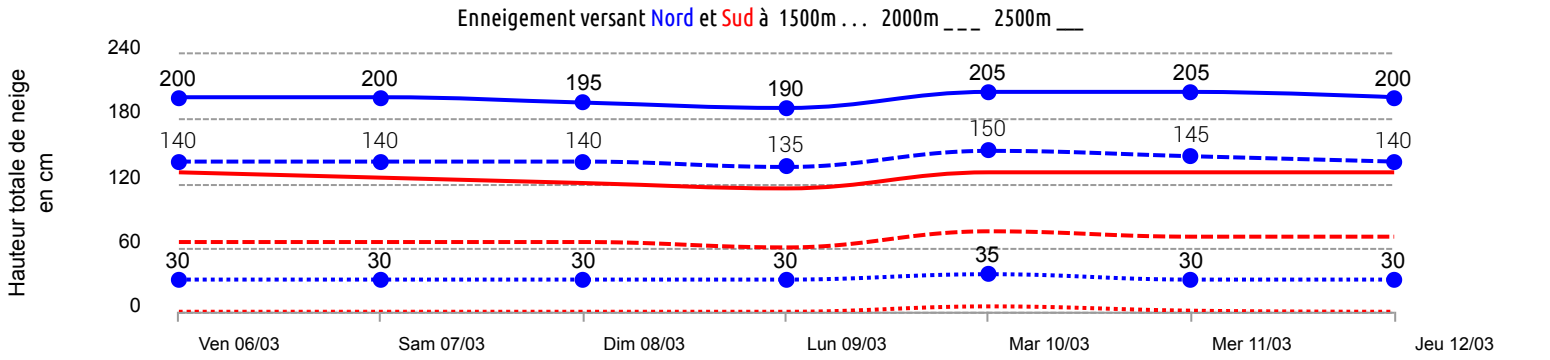

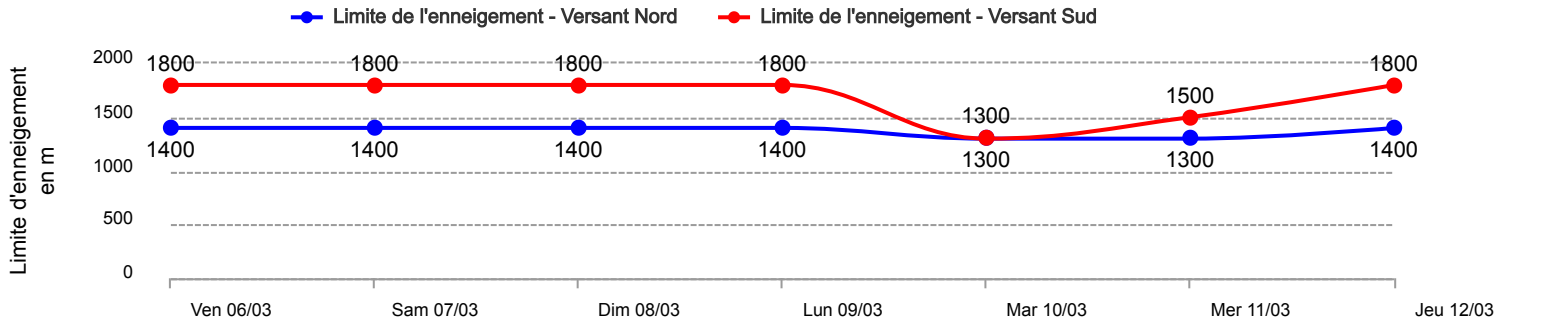

Pour consulter la vigilance en cours, veuillez vous rendre sur le site https://vigilance.meteofrance.fr/fr

Météo-France - 73 avenue de Paris, 94165 Saint-Mandé cedex - Contact : contact@meteo.fr

Rédigé par Météo-France avec la contribution des observateurs du réseau nivo-météorologiques. Partenariat : ANMSM (Maires de Stations de Montagne), DSF (Domaines Skiables de France), ADSP (Directeurs de Pistes et de la Sécurité des Stations de Sports d'Hiver) et autres acteurs de la montagne.

Bulletin neige & avalanches par téléphone au
0 892 68 10 20 Service 0,35 € / min + prix appel