Bulletin d'estimation du risque d'avalanche
(valable en dehors des pistes balisées et ouvertes)

MASSIF : Haute-Bigorre

Rédigé le jeudi 12 mars 2026 à 16h

Estimation des risques pour le : VENDREDI 13 MARS

MANTEAU NEIGEUX BIEN STABILISE, RARES INSTABILITÉS EN HAUTE MONTAGNE

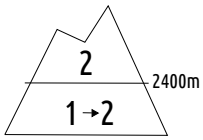

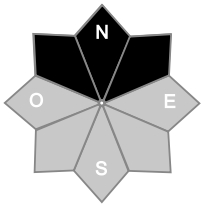

Au-dessus de 2400m indice de risque limité, plus bas indice faible évoluant en limité.

Départs spontanés : En cours de journée, sur les pentes très ensoleillées

Déclenchements provoqués : Rares plaques en haute montagne.

Indices de risque : 5 très fort - 4 fort - 3 marqué - 2 limité - 1 faible -- En noir : les pentes les plus dangereuses

Stabilité du manteau neigeux

Situation avalancheuse typique : neige humide neige ventée

Départs spontanés : Coulées ou avalanches de neige humide (taille moyenne) devenant plus fréquentes dans les pentes les plus ensoleillées, départs le plus souvent près des rochers. départs possibles de plaques vers les pentes sud au-dessus de 2500m. Rare avalanches de fond encore possible sur tous les versants avec des départs au niveau des fissures.

Déclenchements provoqués : Un skieur peut encore déclencher une plaque vers les pentes Nord au-dessus de 2400m, près des crêtes ou des cols. Ces plaques qui se sont formées le dernier week-end sont en cours de stabilisation.

Autres : ponts de neige et corniches fragilisés au soleil.

Qualité de la neige

Enneigement : enneigement encore assez bon pour la saison au-dessus de 1600m, plutôt maigre en versants exposés au vent d'Ouest et en versants Sud.
Limites skiables : à partir de 1500/1600m en versants froids, plutôt 1800m en versants Sud peu raides.
État de la neige : neige de printemps, dure le matin puis de plus en plus molle en journée sur la plupart des pentes bien ensoleillées. Neige compacte plus sèche vers les pentes Nord surtout au-dessus de 1800 m.

Aperçu météo pour le vendredi 13 mars

	nuit	matin	après-midi	soir

Vendredi : Soleil. Nuit de vendredi à samedi : rafraîchissement et neige

Pluie-Neige				1 900 m
Iso 0 °C	2 700 m	2 700 m	2 600 m	2 300 m
Vent 2000 m	10 km/h	15 km/h	25 km/h	30 km/h
Vent 3000 m	20 km/h	30 km/h	45 km/h	45 km/h

Épaisseur de neige hors-piste

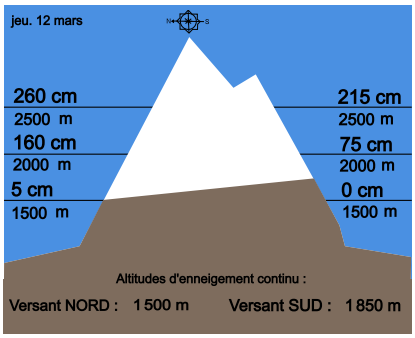

Précipitations à 1800 m

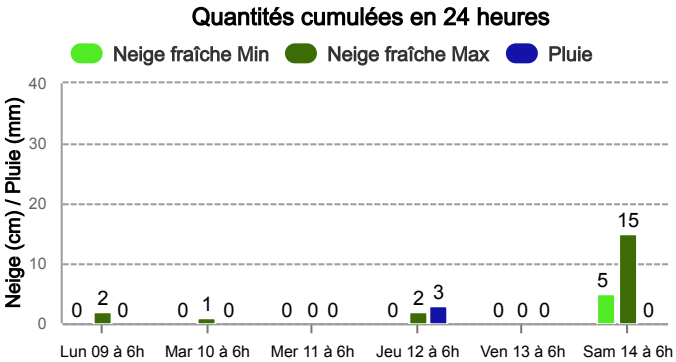

Tendance du samedi 14 mars

Indice de risque marqué

Risque en hausse avec les chutes de neige ventée samedi.

Pour consulter la vigilance en cours, veuillez vous rendre sur le site https://vigilance.meteofrance.fr/fr

Météo-France - 73 avenue de Paris, 94165 Saint-Mandé cedex - Contact : contact@meteo.fr

Rédigé par Météo-France avec la contribution des observateurs du réseau nivo-météorologiques. Partenariat : ANMSM (Maires de Stations de Montagne), DSF (Domaines Skiables de France), ADSP (Directeurs de Pistes et de la Sécurité des Stations de Sports d'Hiver) et autres acteurs de la montagne.

Bulletin neige & avalanches par téléphone au
0 892 68 10 20 Service 0,35 € / min + prix appel

RÉPUBLIQUE FRANÇAISE
Liberté Égalité Fraternité

METEO FRANCE
À VOS CÔTÉS, DANS UN CLIMAT QUI CHANGE

Bulletin d'estimation du risque d'avalanche

(valable en dehors des pistes balisées et ouvertes)

MASSIF : Haute-Bigorre

Rédigé le jeudi 12 mars 2026 à 16h

Conditions nivo-météo des 7 derniers jours

	ven. 06/03				sam. 07/03				dim. 08/03				lun. 09/03				mar. 10/03				mer. 11/03				jeu. 12/03			
	03h	09h	15h	21h	03h	09h	15h	21h	03h	09h	15h	21h	03h	09h	15h	21h	03h	09h	15h	21h	03h	09h	15h	21h	03h	09h	15h	21h
Météo																												
Vent (km/h)	30	25	30	50	25	20	40	50	30	20	20	15	10	15	20	15	15	10	45	35	40	65	60	55	40	30	40	20
à 3000m																												
Vent (km/h)	15	10	15	5	5	10	15	10	5	10	5	5	5	2	5	10	10	5	10	20	25	20	20	15	5	10	10	5
à 2000m																												

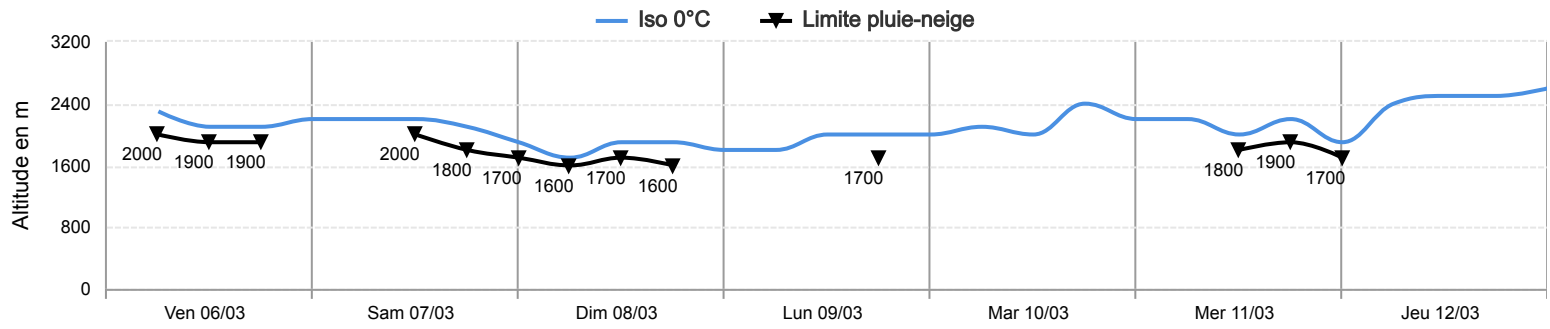

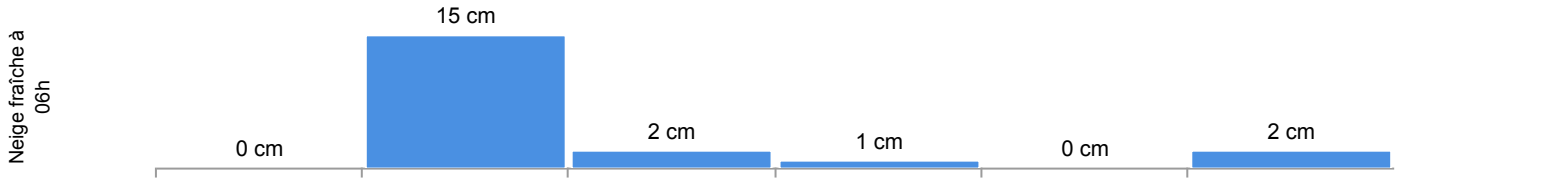

Risque d'avalanche	ven. 06/03	sam. 07/03	dim. 08/03	lun. 09/03	mar. 10/03	mer. 11/03	jeu. 12/03
	2	2	2	2	2	2	2

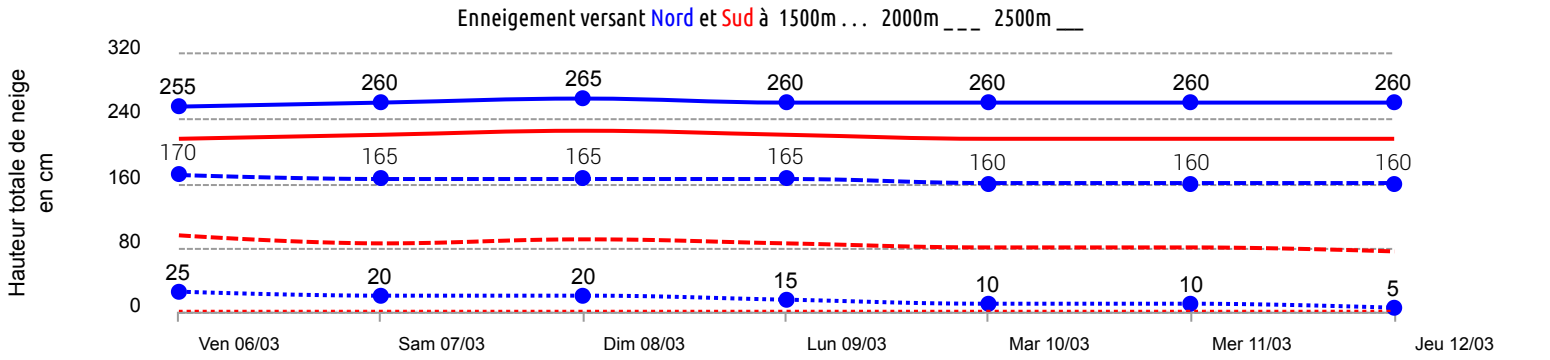

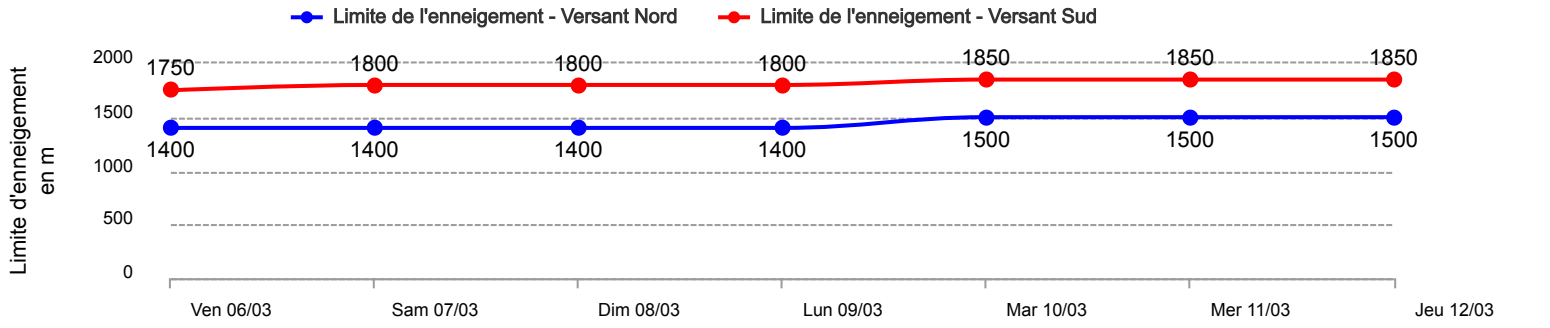

Pour consulter la vigilance en cours, veuillez vous rendre sur le site https://vigilance.meteofrance.fr/fr

Météo-France - 73 avenue de Paris, 94165 Saint-Mandé cedex - Contact : contact@meteo.fr

Rédigé par Météo-France avec la contribution des observateurs du réseau nivo-météorologiques. Partenariat : ANMSM (Maires de Stations de Montagne), DSF (Domaines Skiables de France), ADSP (Directeurs de Pistes et de la Sécurité des Stations de Sports d'Hiver) et autres acteurs de la montagne.

Bulletin neige & avalanches par téléphone au

0 892 68 10 20 Service 0,35 € / min + prix appel