Bulletin d'estimation du risque d'avalanche
(valable en dehors des pistes balisées et ouvertes)

MASSIF : Haute-Maurienne

Rédigé le jeudi 12 mars 2026 à 16h

Estimation des risques pour le : VENDREDI 13 MARS

QUELQUES PLAQUES EN ALTITUDE. COUCHES FRAGILES ENFOUIES GÉNÉRALISÉES MAIS PEU RÉACTIVES.

2

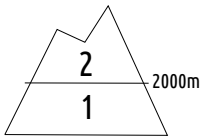

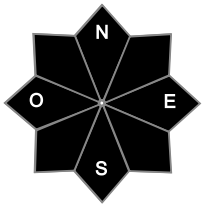

Au-dessus de 2000m indice de risque limité, plus bas indice faible.

Départs spontanés : rares départs ponctuels au Soleil.

Déclenchements provoqués : rares plaques à vent et sur couches fragiles persistantes, tous versants.

Indices de risque : 5 très fort - 4 fort - 3 marqué - 2 limité - 1 faible -- En noir : les pentes les plus dangereuses

Stabilité du manteau neigeux

Situation avalancheuse typique : neige ventée — couche fragile persistante

Déclenchements provoqués :
(1) quelques plaques sont en place dans la neige récente, plutôt en **versant NO à E au-dessus de 2400 m**. Généralement de 10-15 cm, les cassures gagnent en épaisseur en **haute montagne**. Les plaques peuvent être réactives car elles reposent sur des grains anguleux (face plane). De dimension assez modeste, elle engendrent des avalanches petites à moyenne (taille 1 à 2).
(2) des **couches fragiles persistantes** (grains anguleux) sont **enfouies de manière généralisée dans le manteau** au-dessus de 2000 m en large Nord et même en sud de haute altitude (en tous versants). Leur sollicitation est très peu probable mais elles engendrent des avalanches de taille 2 à 3 (moyenne à grande). Le déclenchement est plus probable dans les pentes peu enneigées.

Départs spontanés : rares départs en poire (départs ponctuels) aux abords des cailloux dans les pentes raides, plutôt en versant E/SE d'altitude le matin (taille 1 à 2 = petite à moyenne avalanche).

Qualité de la neige

Enneigement : légèrement excédentaire pour la saison en moyenne montagne, mais en train de devenir déficitaire en basse montagne et en versants sud. Et très déficitaire en haute montagne près de la crête frontalière, voire carrément absent de certains cols ou faces très exposées au vent.

Limite skiable : encore skiable dès 1100/1200 m dans les prairies orientées nord, plutôt 1500/1600 m en sud pas trop raide.

Qualité de la neige :
On trouve une neige croutée en nord jusqu'à 2300/2500 m, recouverte d'une petite couche de neige récente. La croute disparait plus haut, remplacée par des hétérogénéités liées à l'action du vent. En versants O/S/E, neige croutée qui ramollie puis col au gré de l'ensoleillement.

Aperçu météo pour le vendredi 13 mars

	nuit	matin	après-midi	soir
Journée printanière. Grand Soleil et douceur en adret.				
Pluie-Neige				
Iso 0 °C	2 200 m	2 400 m	2 400 m	2 400 m
Vent 2500 m	↓ 5 km/h	↓ 5 km/h	↓ 10 km/h	↗ 20 km/h
Vent 3500 m	↓ 10 km/h	↓ 10 km/h	↘ 15 km/h	↗ 30 km/h

Épaisseur de neige hors-piste

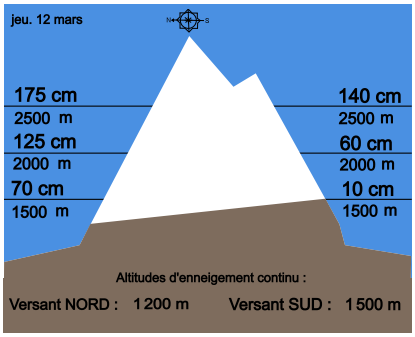

Précipitations à 1800 m

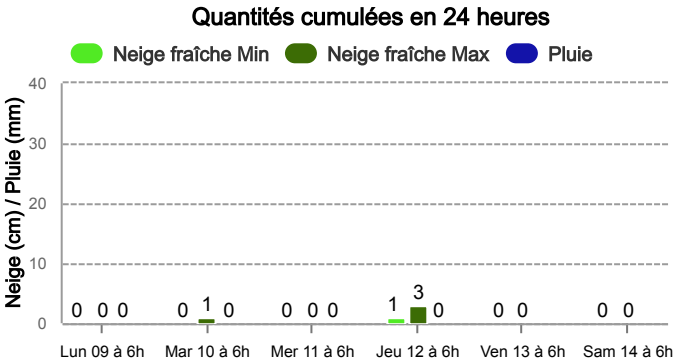

Tendance du samedi 14 mars

3 **Indice de risque marqué**

Coup de vent de Sud et précipitations neigeuses jusqu'à basse altitude. Forte augmentation du risque en montagne.

Pour consulter la vigilance en cours, veuillez vous rendre sur le site https://vigilance.meteofrance.fr/fr

Météo-France - 73 avenue de Paris, 94165 Saint-Mandé cedex - Contact : contact@meteo.fr

Rédigé par Météo-France avec la contribution des observateurs du réseau nivo-météorologiques. Partenariat : ANMSM (Maires de Stations de Montagne), DSF (Domaines Skiables de France), ADSP (Directeurs de Pistes et de la Sécurité des Stations de Sports d'Hiver) et autres acteurs de la montagne.

Bulletin neige & avalanches par téléphone au **0 892 68 10 20** Service 0,35 € / min + prix appel

RÉPUBLIQUE FRANÇAISE
Liberté Égalité Fraternité

METEO FRANCE
À VOS CÔTÉS, DANS UN CLIMAT QUI CHANGE

Bulletin d'estimation du risque d'avalanche
(valable en dehors des pistes balisées et ouvertes)
MASSIF : Haute-Maurienne

Rédigé le jeudi 12 mars 2026 à 16h

Conditions nivo-météo des 7 derniers jours

	ven. 06/03				sam. 07/03				dim. 08/03				lun. 09/03				mar. 10/03				mer. 11/03				jeu. 12/03			
	03h	09h	15h	21h	03h	09h	15h	21h	03h	09h	15h	21h	03h	09h	15h	21h	03h	09h	15h	21h	03h	09h	15h	21h	03h	09h	15h	21h
Météo																												
Vent (km/h)	30	35	30	30	25	30	25	25	20	15	15	15	15	15	20	25	30	30	30	20	20	25	35	45	30	20	20	10
à 3500m																												
Vent (km/h)	30	30	25	25	20	25	20	15	20	15	15	15	15	15	20	30	25	20	15	10	10	10	25	35	20	10	10	5
à 2500m																												

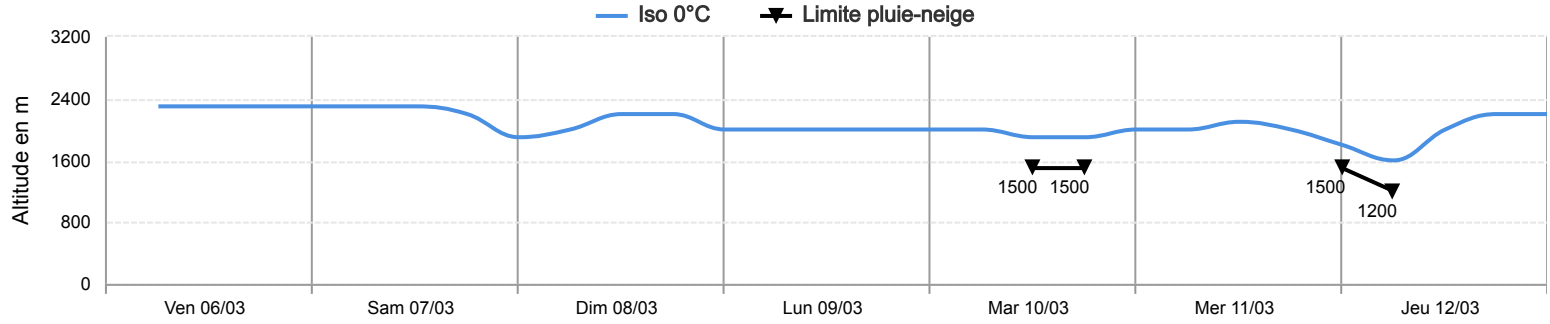

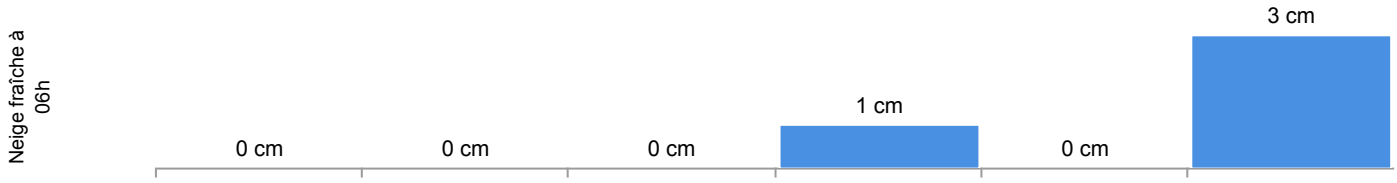

Risque d'avalanche	ven. 06/03	sam. 07/03	dim. 08/03	lun. 09/03	mar. 10/03	mer. 11/03	jeu. 12/03
	2	2	2	2	2	2	2

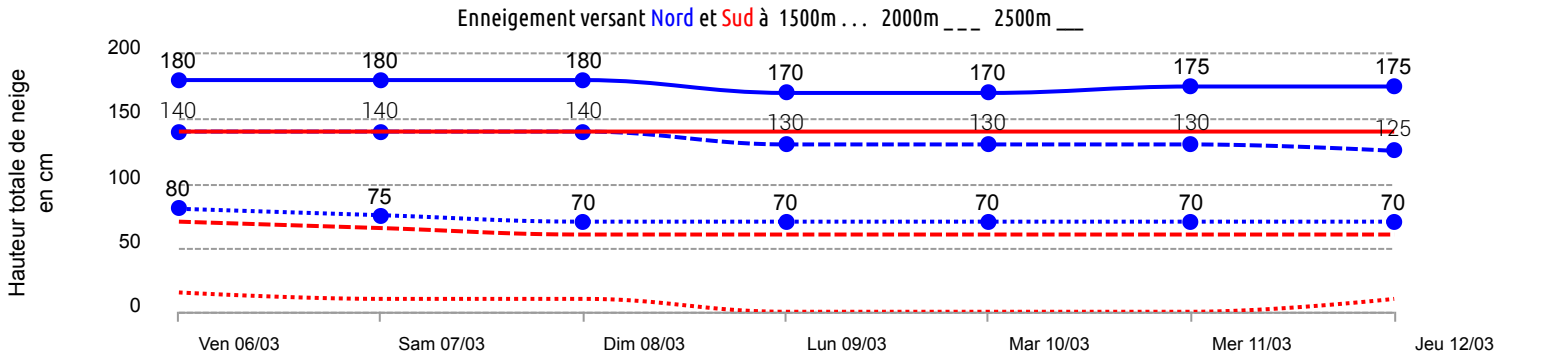

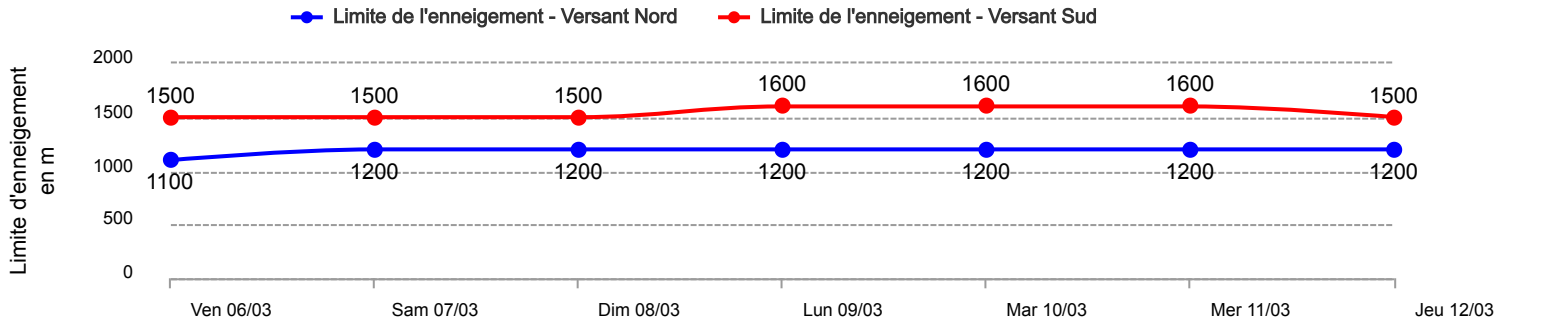

Pour consulter la vigilance en cours, veuillez vous rendre sur le site https://vigilance.meteofrance.fr/fr

Météo-France - 73 avenue de Paris, 94165 Saint-Mandé cedex - Contact : contact@meteo.fr

Rédigé par Météo-France avec la contribution des observateurs du réseau nivo-météorologiques. Partenariat : ANMSM (Maires de Stations de Montagne), DSF (Domaines Skiables de France), ADSP (Directeurs de Pistes et de la Sécurité des Stations de Sports d'Hiver) et autres acteurs de la montagne.

Bulletin neige & avalanches par téléphone au
0 892 68 10 20 Service 0,35 € / min + prix appel