Bulletin d'estimation du risque d'avalanche
(valable en dehors des pistes balisées et ouvertes)
MASSIF : Maurienne

Rédigé le jeudi 12 mars 2026 à 16h

Estimation des risques pour le : VENDREDI 13 MARS

QUELQUES PLAQUES EN ALTITUDE. COUCHES FRAGILES ENFOUIES GÉNÉRALISÉES MAIS PEU RÉACTIVES.

2

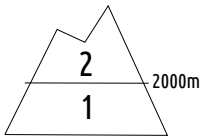

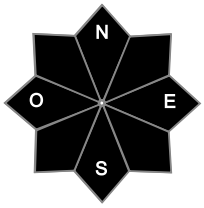

Au-dessus de 2000m indice de risque limité, plus bas indice faible.

Départs spontanés : rares départs ponctuels au Soleil.

Déclenchements provoqués : quelques plaques "de surface" en ubac. Couche fragile persistante enfouie en tous versants.

Indices de risque : 5 très fort - 4 fort - 3 marqué - 2 limité - 1 faible -- En noir : les pentes les plus dangereuses

Stabilité du manteau neigeux

Situation avalancheuse typique : neige ventée — couche fragile persistante

Déclenchements provoqués :
(1) quelques plaques sont en place dans la neige récente **en ubac au-dessus de 2000 m**. En cours de stabilisation dans la tranche 2000-2400 m, elles restent bien réactives plus haut car elles reposent sur une vieille neige sans cohésion (face plane - vieille poudre). Cassures moyennes autour de 30-15 cm d'Ouest en Est du massif, petites à moyennes avalanches possibles. Peu d'observables car plaques d'aspect poudreux. Woumf possible en versants ombragés d'altitude.
(2) à la marge : des **couches fragiles persistantes** (grains anguleux) sont **enfouies de manière généralisée dans le manteau** au-dessus de 2200 m en large Nord et même en sud de haute altitude (en tous versants). Leur sollicitation est très peu probable mais elles engendrent des avalanches de taille 2, rarement 3 (moyenne, rarement grande). Le déclenchement est plus probable dans les pentes peu enneigées.

Départs spontanés : rares départs en poire (départs ponctuels) aux abords des cailloux dans les pentes raides, plutôt en versant E/SE d'altitude le matin (taille 1 = petite avalanche).

Qualité de la neige

Enneigement : en général légèrement excédentaire pour la saison, mais en train de devenir déficitaire en basse montagne et en versants sud.

Limite skiable : encore skiable dès 1100/1200 m dans les prairies orientées nord, plutôt 1600 m en sud pas trop raide.

Qualité de la neige : la neige est bonne à skier dans les ubacs. On trouve 15/7 cm de neige poudreuse d'Ouest en Est, à partir de 2000 m.
Dans les versants Est, Sud et Ouest, elle est croûtée au réveil suite à un mercredi ensoleillé suivi d'une nuit très froide, propice à un bon regel de la neige humide. Au gré de la course du Soleil, les versants ensoleillés chauffent rapidement et transforment en neige collante.

Aperçu météo pour le vendredi 13 mars

nuit	matin	après-midi	soir

Journée printanière. Grand Soleil et douceur en adret.

Pluie-Neige				
Iso 0 °C	2 400 m	2 500 m	2 500 m	2 400 m
Vent 2000 m	10 km/h	15 km/h	25 km/h	35 km/h
Vent 3000 m	20 km/h	25 km/h	35 km/h	45 km/h

Épaisseur de neige hors-piste

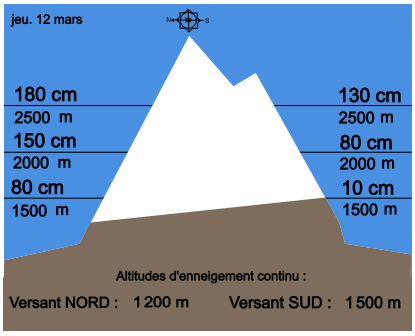

Précipitations à 1800 m

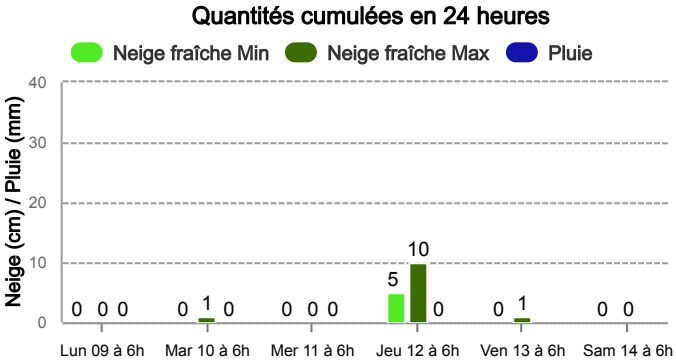

Tendance du samedi 14 mars

3 **Indice de risque marqué**

Coup de vent de Sud et précipitations neigeuses jusqu'à basse altitude. Forte augmentation du risque en montagne.

Pour consulter la vigilance en cours, veuillez vous rendre sur le site https://vigilance.meteofrance.fr/fr

Météo-France - 73 avenue de Paris, 94165 Saint-Mandé cedex - Contact : contact@meteo.fr

Rédigé par Météo-France avec la contribution des observateurs du réseau nivo-météorologiques. Partenariat : ANMSM (Maires de Stations de Montagne), DSF (Domaines Skiables de France), ADSP (Directeurs de Pistes et de la Sécurité des Stations de Sports d'Hiver) et autres acteurs de la montagne.

Bulletin neige & avalanches par téléphone au
0 892 68 10 20 Service 0,35 € / min + prix appel

Bulletin d'estimation du risque d'avalanche

(valable en dehors des pistes balisées et ouvertes)

MASSIF : Maurienne

Rédigé le jeudi 12 mars 2026 à 16h

Conditions nivo-météo des 7 derniers jours

	ven. 06/03				sam. 07/03				dim. 08/03				lun. 09/03				mar. 10/03				mer. 11/03				jeu. 12/03			
	03h	09h	15h	21h	03h	09h	15h	21h	03h	09h	15h	21h	03h	09h	15h	21h	03h	09h	15h	21h	03h	09h	15h	21h	03h	09h	15h	21h
Météo																												
Vent (km/h)	40	45	40	30	20	30	30	30	20	20	20	15	20	20	20	20	25	30	30	20	25	25	30	40	30	25	20	20
à 3000m																												
Vent (km/h)	30	35	30	20	15	20	20	20	15	10	15	10	15	15	20	30	25	30	20	10	15	15	20	30	20	15	10	10
à 2000m																												

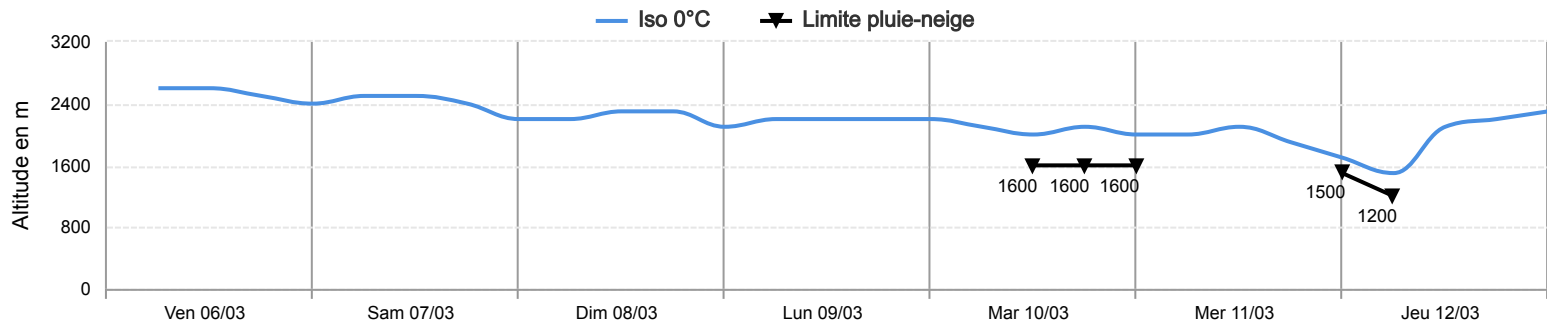



Risque d'avalanche	ven. 06/03	sam. 07/03	dim. 08/03	lun. 09/03	mar. 10/03	mer. 11/03	jeu. 12/03
	2	2	2	2	2	2	2

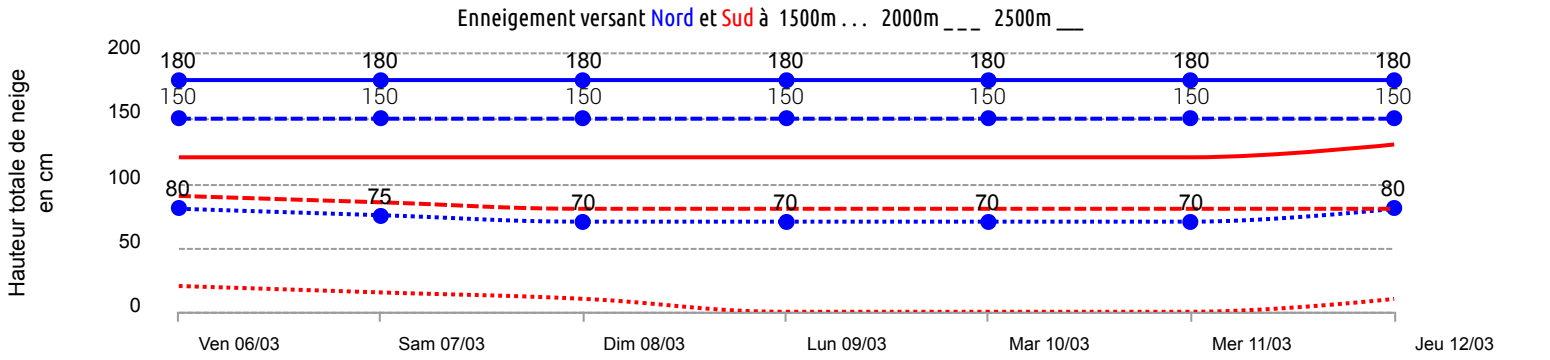

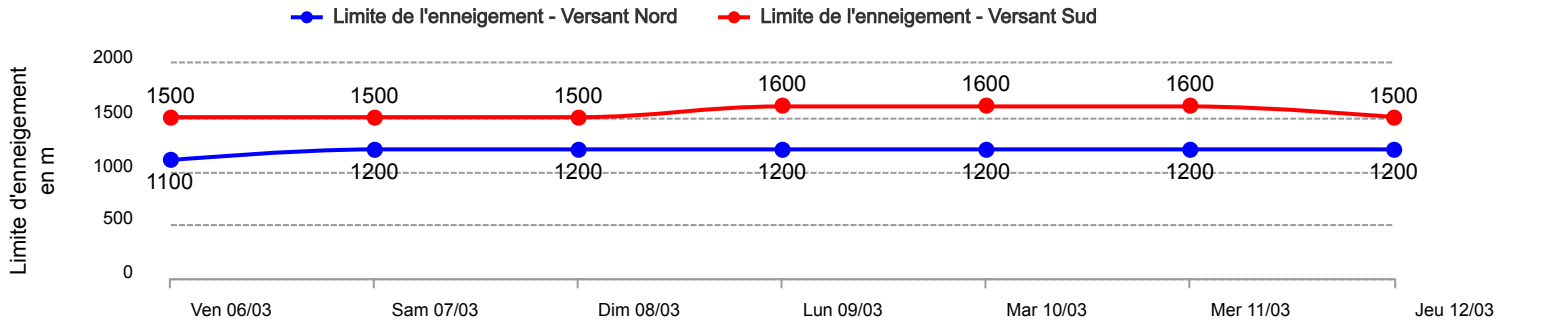

Pour consulter la vigilance en cours, veuillez vous rendre sur le site https://vigilance.meteofrance.fr/fr

Météo-France - 73 avenue de Paris, 94165 Saint-Mandé cedex - Contact : contact@meteo.fr

Rédigé par Météo-France avec la contribution des observateurs du réseau nivo-météorologiques. Partenariat : ANMSM (Maires de Stations de Montagne), DSF (Domaines Skiables de France), ADSP (Directeurs de Pistes et de la Sécurité des Stations de Sports d'Hiver) et autres acteurs de la montagne.

Bulletin neige & avalanches par téléphone au

0 892 68 10 20 Service 0,35 € / min + prix appel