Bulletin d'estimation du risque d'avalanche
(valable en dehors des pistes balisées et ouvertes)

MASSIF : Pays-Basque

Rédigé le jeudi 12 mars 2026 à 16h

Estimation des risques pour le : VENDREDI 13 MARS

MANTEAU NEIGEUX BIEN STABILISE

1

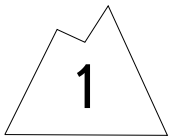

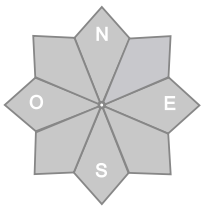

Indice de risque faible.

Départs spontanés : En cours de journée avalanche de neige molle

Déclenchements provoqués : peu probable

Indices de risque : 5 très fort - 4 fort - 3 marqué - 2 limité - 1 faible -- En noir : les pentes les plus dangereuses

Stabilité du manteau neigeux

Situation avalancheuse typique : neige humide

Départs spontanés : Pas d'activité en début de journée avec une neige bien regelée. Ensuite des coulées ou des avalanches de neige humide (taille moyenne) peuvent se produire, le plus souvent avec des départs ponctuels près des rochers. Plus rarement des avalanches de fond sont encore possibles avec des départs au niveau des fissures.
Déclenchements provoqués : Peu probable, éventuellement un skieur peut faciliter le départ de coulées dans les pentes raides en neige très molles.
Autre : Neige dure en fin de nuit.

Qualité de la neige

Enneigement : enneigement encore assez bon pour la saison au dessus de 1600/1700m, plutôt maigre en versants exposés au vent d'Ouest et en versants Sud.
Limites skiables : à partir de 1600m en versants froids, plutôt 1800 à 1900m en versants Sud
État de la neige : en début de matinée, bon regel de la neige en surface. En journée, humidification progressive au soleil, rapide dans les pentes sud-Est à Sud-Ouest raides, plus lent sur les pentes Nord.

Aperçu météo pour le vendredi 13 mars

	nuit	matin	après-midi	soir
Pluie-Neige				1700 m
Iso 0 °C	2700 m	2500 m	2400 m	2000 m
Vent 1000 m	↑ 15 km/h	↗ 25 km/h	↗ 35 km/h	→ 30 km/h
Vent 2000 m	↑ 30 km/h	↗ 50 km/h	↗ 55 km/h	↗ 55 km/h

Épaisseur de neige hors-piste

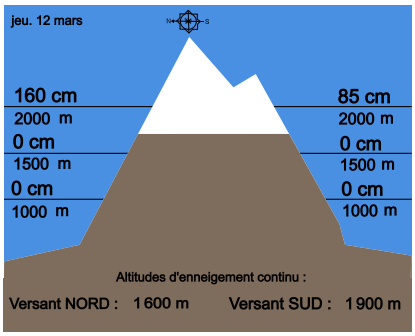

Précipitations à 1800 m

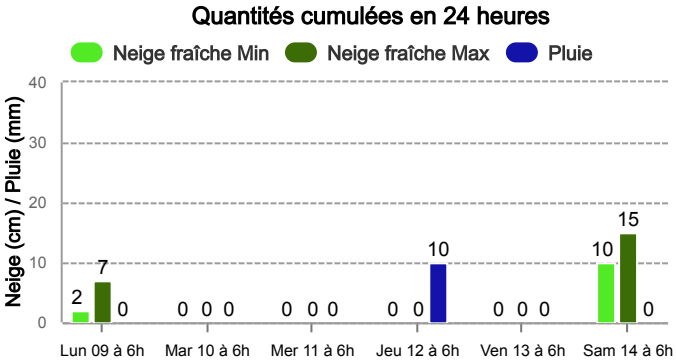

Tendance du samedi 14 mars

2

Indice de risque limité

Risque en hausse avec les chutes de neige ventée samedi.

Pour consulter la vigilance en cours, veuillez vous rendre sur le site https://vigilance.meteofrance.fr/fr

Météo-France - 73 avenue de Paris, 94165 Saint-Mandé cedex - Contact : contact@meteo.fr

Rédigé par Météo-France avec la contribution des observateurs du réseau nivo-météorologiques. Partenariat : ANMSM (Maires de Stations de Montagne), DSF (Domaines Skiables de France), ADSP (Directeurs de Pistes et de la Sécurité des Stations de Sports d'Hiver) et autres acteurs de la montagne.

Bulletin neige & avalanches par téléphone au
0 892 68 10 20 Service 0,35 € / min + prix appel

Bulletin d'estimation du risque d'avalanche

(valable en dehors des pistes balisées et ouvertes)

MASSIF : Pays-Basque

Rédigé le jeudi 12 mars 2026 à 16h

Conditions nivo-météo des 7 derniers jours

	ven. 06/03				sam. 07/03				dim. 08/03				lun. 09/03				mar. 10/03				mer. 11/03				jeu. 12/03			
	03h	09h	15h	21h	03h	09h	15h	21h	03h	09h	15h	21h	03h	09h	15h	21h	03h	09h	15h	21h	03h	09h	15h	21h	03h	09h	15h	21h
Météo																												
Vent (km/h)	30	25	25	15	20	25	30	25	40	35	30	15	25	25	20	20	15	15	30	60	50	45	60	50	30	35	25	20
à 2000m																												
Vent (km/h)	15	15	15	5	5	10	10	5	10	5	5	5	10	10	5	5	10	10	15	10	15	10	20	15	10	15	5	5
à 1000m																												

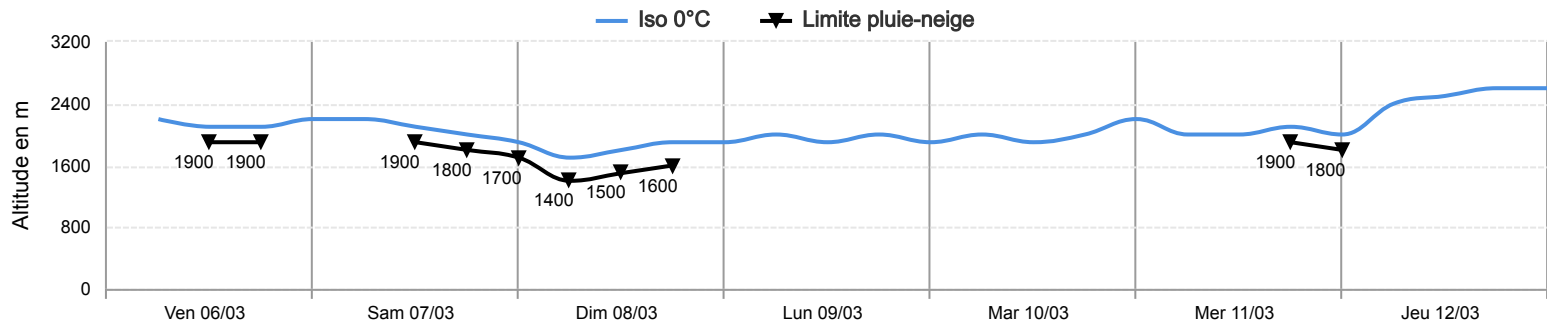

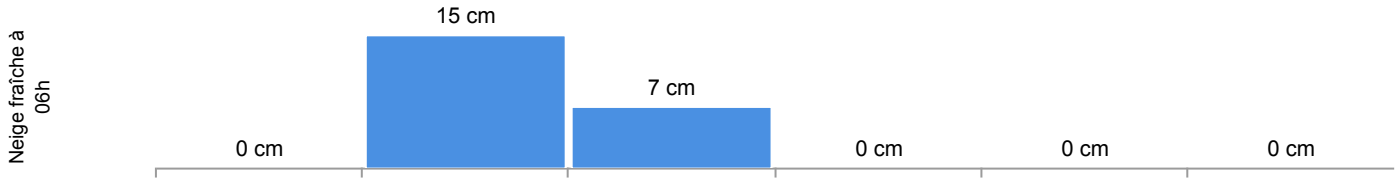

Risque d'avalanche	ven. 06/03	sam. 07/03	dim. 08/03	lun. 09/03	mar. 10/03	mer. 11/03	jeu. 12/03
	2	2	2	2	2	2	2

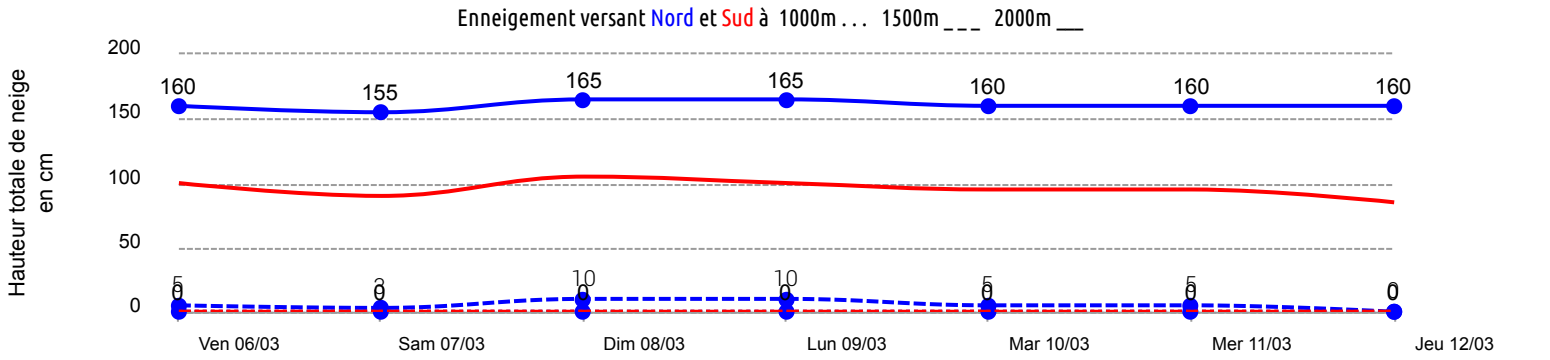

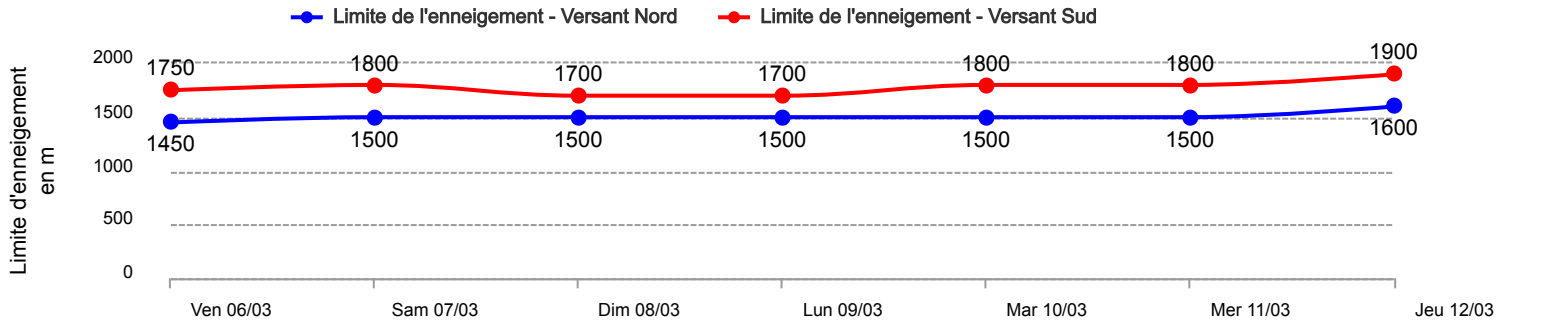

Pour consulter la vigilance en cours, veuillez vous rendre sur le site https://vigilance.meteofrance.fr/fr

Météo-France - 73 avenue de Paris, 94165 Saint-Mandé cedex - Contact : contact@meteo.fr

Bulletin neige & avalanches par téléphone au

0 892 68 10 20 Service 0,35 € / min + prix appel

Rédigé par Météo-France avec la contribution des observateurs du réseau nivo-météorologiques. Partenariat : ANMSM (Maires de Stations de Montagne), DSF (Domaines Skiables de France), ADSP (Directeurs de Pistes et de la Sécurité des Stations de Sports d'Hiver) et autres acteurs de la montagne.