# Bulletin d'estimation du risque d'avalanche
(valable en dehors des pistes balisées et ouvertes)

# MASSIF : Renoso Incudine

Rédigé le jeudi 12 mars 2026 à 16h

## Estimation des risques pour le : VENDREDI 13 MARS

**DÉPARTS POSSIBLES EN NEIGE HUMIDE, QUELQUES PETITES INSTABILITÉS EN NEIGE FRAÎCHE EN ALTITUDE**

1

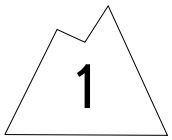


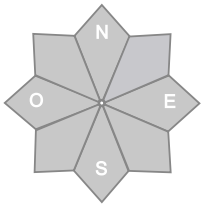


Indice de risque faible.

**Départs spontanés :** Coulées et avalanches de neige fraîche et humide

**Déclenchements provoqués :** Petites plaques à vent en altitude, risque de départs ponctuels sous les skis en neige humide

Indices de risque : 5 très fort - 4 fort - 3 marqué - 2 limité - 1 faible -- En noir : les pentes les plus dangereuses

## Stabilité du manteau neigeux

**Situation avalancheuse typique :** neige fraîche neige humide

**Départs spontanés :** En dessous de 1800 m, des coulées de neige humide (taille 1) sont attendues. Au-dessus de 1800 m, quelques coulées de neige fraîche sont possibles durant les averses, essentiellement dans les pentes raides. La sous-couche étant bien dense ou dure, seule la neige récente reste mobilisable (taille 1).
**Déclenchements provoqués :** des départs ponctuels sous les skis ou raquettes en neige humide peuvent se produire, notamment dans les pentes raides et ensoleillés (taille 1 à 2 suivant l'altitude). De petites plaques à vent formées dans les pentes orientées Ouest à Nord-ouest, au-dessus de 2000 m, sont à présent recouvertes par les nouvelles chutes de neige. Des déclenchement sont possibles surtout par forte surcharge, pouvant engendrer une coulée mobilisant peu de neige (taille 1).
**Autres :** Nombreuses surfaces glacées.

## Qualité de la neige

**Qualification de l'enneigement :** L'enneigement est excellent pour la saison au-dessus de 1600 m. Au Val d'Ese, on relève encore près d'un mètre de neige juste au-dessus de la station. À Ghisoni Capanelle, 1m70 au-dessus de 1800 m et près de 3 mètres dans les combes abritées.
**Limite d'enneigement skiable :** 1500 à 1600 m selon le versant.
**État de la neige** : Le manteau neigeux est à présent tassé et bien consolidé. En dessous de 1800 m, la pluie a humidifié le manteau sur toute son épaisseur, la neige y est souvent lourde et humide. Au-dessus de 1800 à 2000 m, le refroidissement permet une consolidation par regel des couches de neige humide. Des croûtes épaisses se forment et des surfaces dures et glacées se généralisent parfois recouverte d'un peu de neige fraîche. on observe de nombreuses zones de neige colorée avec les dernières remontées de sable. À noter également la présence de corniches parfois volumineuses.

## Aperçu météo pour le vendredi 13 mars

| | nuit | matin | après-midi | soir |
|---|---|---|---|---|
| | | | | |

Averses orageuses dans la nuit, puis ciel est dégagé demain matin et apparition de nuages porteurs d'averses l'après-midi.

| | | | | |
|---|---|---|---|---|
| **Pluie-Neige** | 1 500 m | | 1 800 m | |
| **Iso 0 °C** | 2 000 m | 2 100 m | 2 100 m | 2 300 m |
| **Vent 1500 m** | ↙ 20 km/h | ↙ 20 km/h | → 15 km/h | ↗ 10 km/h |
| **Vent 2000 m** | ↓ 25 km/h | ↓ 15 km/h | ↙ 5 km/h | ↗ 5 km/h |

## Épaisseur de neige hors-piste

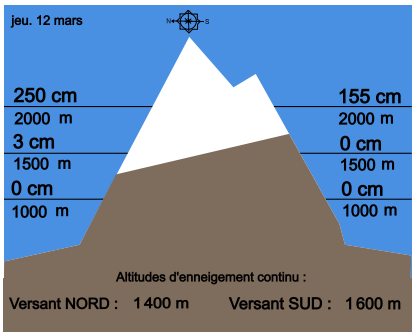


## Précipitations à 1800 m

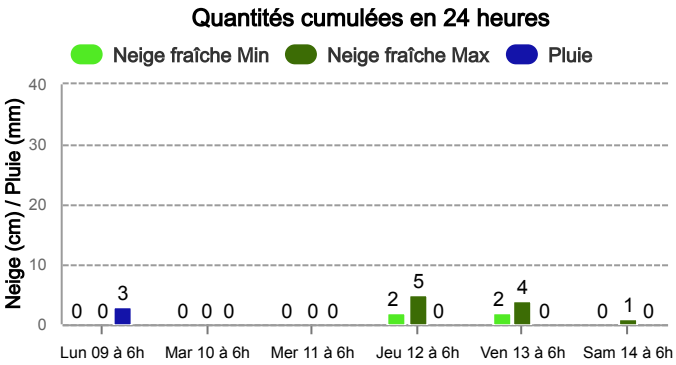


## Tendance du samedi 14 mars

1 **Indice de risque faible**

Temps perturbé en fin de journée de samedi .
Pas d'évolution notable en termes de risque.

Pour consulter la vigilance en cours, veuillez vous rendre sur le site https://vigilance.meteofrance.fr/fr

Météo-France - 73 avenue de Paris, 94165 Saint-Mandé cedex - Contact : contact@meteo.fr

Rédigé par Météo-France avec la contribution des observateurs du réseau nivo-météorologiques. Partenariat : ANMSM (Maires de Stations de Montagne), DSF (Domaines Skiables de France), ADSP (Directeurs de Pistes et de la Sécurité des Stations de Sports d'Hiver) et autres acteurs de la montagne.

Bulletin neige & avalanches par téléphone au
0 892 68 10 20 Service 0,35 € / min + prix appel

RÉPUBLIQUE FRANÇAISE
*Liberté Égalité Fraternité*

METEO FRANCE
À VOS CÔTÉS, DANS UN CLIMAT QUI CHANGE

# Bulletin d'estimation du risque d'avalanche

(valable en dehors des pistes balisées et ouvertes)

# MASSIF : Renoso Incudine

Rédigé le jeudi 12 mars 2026 à 16h

## Conditions nivo-météo des 7 derniers jours

| | ven. 06/03 | | | | sam. 07/03 | | | | dim. 08/03 | | | | lun. 09/03 | | | | mar. 10/03 | | | | mer. 11/03 | | | | jeu. 12/03 | | | |
|---|---|---|---|---|---|---|---|---|---|---|---|---|---|---|---|---|---|---|---|---|---|---|---|---|---|---|---|---|
| | 03h | 09h | 15h | 21h | 03h | 09h | 15h | 21h | 03h | 09h | 15h | 21h | 03h | 09h | 15h | 21h | 03h | 09h | 15h | 21h | 03h | 09h | 15h | 21h | 03h | 09h | 15h | 21h |
| Météo | | | | | | | | | | | | | | | | | | | | | | | | | | | | |
| Vent (km/h) | 60 | 70 | 60 | 50 | 40 | 35 | 20 | 20 | 15 | 10 | 15 | 5 | 15 | 15 | 15 | 20 | 20 | 30 | 20 | 20 | 20 | 30 | 40 | 40 | 30 | 30 | 30 | 30 |
| à 2000m | | | | | | | | | | | | | | | | | | | | | | | | | | | | |
| Vent (km/h) | 45 | 55 | 50 | 40 | 30 | 30 | 15 | 15 | 10 | 5 | 10 | 5 | 5 | 5 | 10 | 15 | 15 | 20 | 15 | 10 | 15 | 20 | 30 | 20 | 30 | 20 | 25 | 15 |
| à 1500m | | | | | | | | | | | | | | | | | | | | | | | | | | | | |

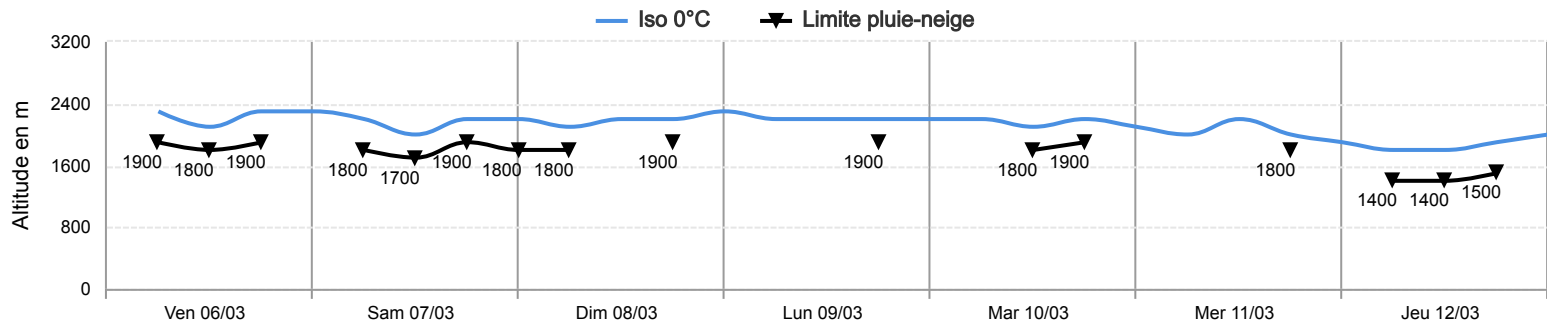


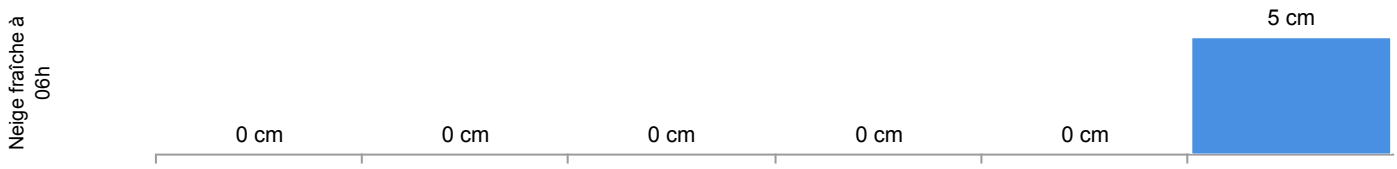


| Risque d'avalanche | | | | | | | |
|---|---|---|---|---|---|---|---|
| | 2 | 2 | 2 | 1 | 1 | 1 | 1 |
| | ven. 06/03 | sam. 07/03 | dim. 08/03 | lun. 09/03 | mar. 10/03 | mer. 11/03 | jeu. 12/03 |

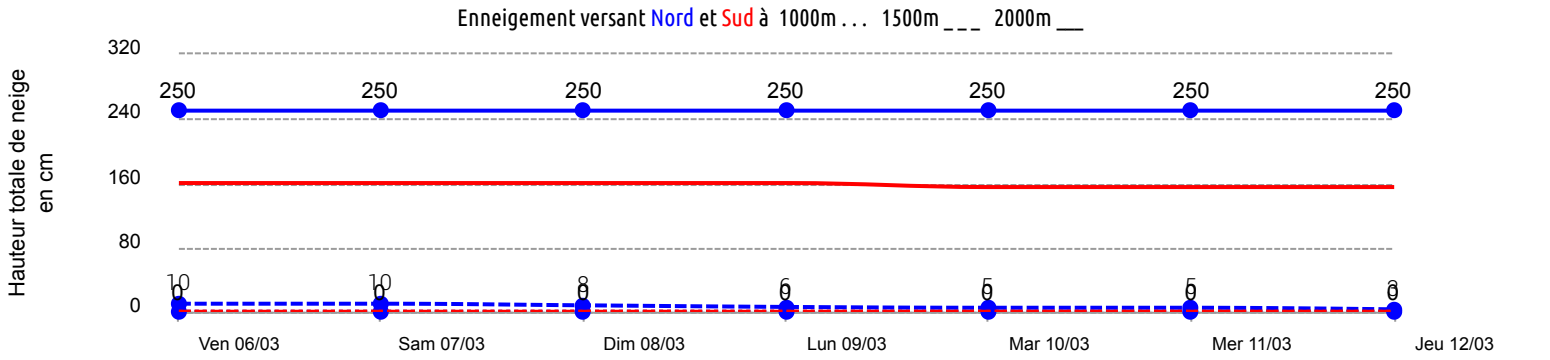


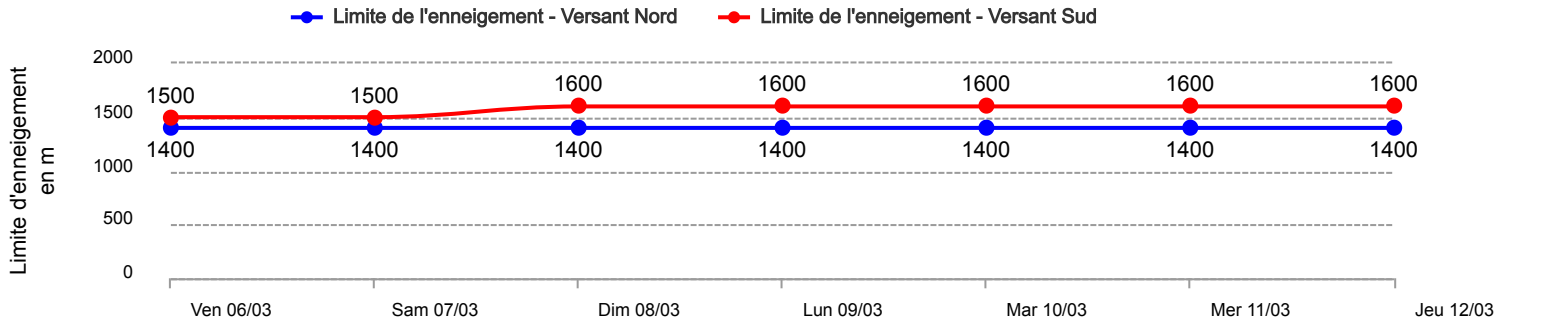


Pour consulter la vigilance en cours, veuillez vous rendre sur le site https://vigilance.meteofrance.fr/fr


Météo-France - 73 avenue de Paris, 94165 Saint-Mandé cedex - Contact : contact@meteo.fr



Rédigé par Météo-France avec la contribution des observateurs du réseau nivo-météorologiques. Partenariat : ANMSM (Maires de Stations de Montagne), DSF (Domaines Skiables de France), ADSP (Directeurs de Pistes et de la Sécurité des Stations de Sports d'Hiver) et autres acteurs de la montagne.



Bulletin neige & avalanches par téléphone au
0 892 68 10 20 Service 0,35 € / min + prix appel