GOBIERNO DE ESPAÑA
VICEPRESIDENCIA TERCERA DEL GOBIERNO
MINISTERIO PARA LA TRANSICIÓN ECOLÓGICA Y EL RETO DEMOGRÁFICO

Boletín de información nivológica y de peligro de aludes

Pirineo Catalán

aemet Agencia Estatal de Meteorología

viernes, 13 de marzo de 2026

Pronóstico hasta las 24 horas del sábado, día 14 de marzo

(Válido fuera de pistas de esquí balizadas y abiertas)

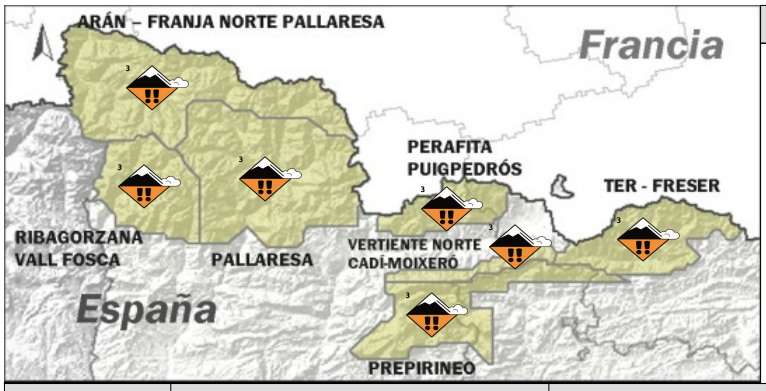

Problemas de aludes

Capas débiles persistentes

Nieve reciente

Placas de viento

Macizo	Peligro	Problemas de aludes, cota, orientación, tamaño	Innivación observada (m)
Arán - Franja norte Pallaresa	3 **Notable**	**Nieve reciente** 2 N O E S **Placas de viento** 1800 3 N O E S	2026-03-12 N S Cota más baja caras N
Ribagorzana - Vall Fosca	3 **Notable**	**Capas débiles persistentes** 2100 2 N O E S **Placas de viento** 2100 2 N O E S	2026-03-12 N S Cota más baja caras N
Pallaresa	3 **Notable**	**Nieve reciente** 2 N O E S **Placas de viento** 2100 2 N O E S	2026-03-12 N S Cota más baja caras N

AEMET. Se autoriza la reproducción de su contenido citando la fuente.

Boletín de información nivológica y de peligro de aludes

Pirineo Catalán

Perafita - Puigpedrós	3 **Notable**	**Nieve reciente**  **Placas de viento** 	2026-03-12 Cota más baja caras N
Ter - Freser	3 **Notable**	**Capas débiles persistentes**  **Placas de viento** 	2026-03-12 Cota más baja caras N
Vertiente norte Cadí - Moixeró	3 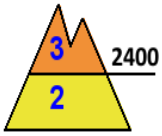 **Notable**	**Capas débiles persistentes**  **Placas de viento** 	2026-03-12 Cota más baja caras N
Prepirineo	3 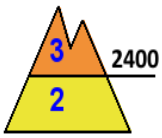 **Notable**	**Capas débiles persistentes**  **Placas de viento** 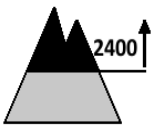 	2026-03-12 Cota más baja caras N

Estado del manto y observaciones recientes

Ayer predominaron los cielos poco nubosos o despejados, propiciando una leve disminución de los espesores y un buen rehielo nocturno esta madrugada. Soplaron vientos entre moderados y fuertes del noroeste en cotas altas que han podido movilizar algunos centímetros de nieve reciente formando pequeñas placas de viento cerca de crestas y cordales.

AEMET. Se autoriza la reproducción de su contenido citando la fuente.

El manto es continuo, en general, desde cotas medias, mostrando cierta disimetría entre solanas y umbrías. Pese a la mengua progresiva, los espesores siguen siendo importantes y se encuentran muy por encima de lo que cabe esperar a estas alturas de la temporada, con alrededor de 120-200 cm por encima de los 2100 metros, sensiblemente más en hoyas, ventisqueros y otras zonas propensas a la acumulación.

En cotas medias y bajas, así como en solanas a mayor altitud, la nieve está humedecida en profundidad y las heladas tienden a encostrarla durante las primeras horas. En umbrías de cotas altas se mantiene fría y seca, con presencia de capas débiles de escarcha y facetas en superficie o recientemente enterradas, y alguna persistente en profundidad.

Evolución del manto y peligro de aludes para el sábado, día 14

Mañana se esperan nevadas durante toda la jornada y un acusado descenso de las temperaturas. Podrían superarse los 25 cm en el Arán y la Franja Norte Pallaresa, mientras que en el resto rondarán los 5-15 cm. Serán muy probables los aludes de nieve reciente de tamaño pequeño (1, riesgo de caída) o mediano (2, capaz de enterrar a una persona), sin descartar alguno mayor en zonas de acumulación por la tarde.

Asimismo, soplarán vientos fuertes sostenidos del norte y noroeste, y a medida que avance el día se irán formando numerosas placas de viento en todas las orientaciones aunque sobre todo en las este y sur. Serán fáciles de fracturar ante una sobrecarga débil (paso de un esquiador) u ocasionalmente de manera natural, provocando aludes de tamaño mediano o localmente grande (3, capaz de enterrar a un grupo de personas), especialmente aquellas que en umbrías descansen sobre capas débiles persistentes superficiales o en profundidad.

Predicción meteorológica para el sábado, día 14

Muy nuboso o cubierto, tendiendo a disminuir la nubosidad durante la tarde, excepto en el valle de Arán y la divisoria fronteriza, donde persistirá nubosidad de estancamiento. Visibilidad localmente reducida en cotas altas. Se esperan precipitaciones débiles a moderadas, en ocasiones en forma de chubasco, remitiendo a media tarde salvo en el valle de Arán y la Franja Norte Pallaresa donde podrán ser persistentes. Cota de nieve: bajando de 1800 a unos 600-800 metros por la tarde. No se descartan tormentas ocasionalmente acompañando a los chubascos. Temperaturas en descenso, notable de las máximas. Las mínimas se darán al final del día. Heladas moderadas, en cotas altas fuertes y persistentes. Viento del norte y noroeste, fuerte con rachas o intervalos muy fuertes en la segunda mitad del día, especialmente en el Ripollés. En cotas bajas soplará inicialmente moderado, con intervalos fuertes a partir de mediodía.

Datos en la atmósfera libre:

Altitud de la isoterma de 0 ºC: 1400 m
Altitud de la isoterma de -10 ºC: 2600 m

Viento a 1500 m: NW 25 km/h
Viento a 3000 m: NW 50 km/h

AEMET. Se autoriza la reproducción de su contenido citando la fuente.

Evolución para el domingo día 15

Nivel de peligro sin grandes cambios.

Escala europea de peligro de aludes

Débil | Limitado | Notable | Fuerte | Muy Fuerte

Problemas de aludes

Nieve reciente | Placas de viento | Capas débiles persistentes | Nieve húmeda | Deslizamientos basales | Sin problema evidente

Nota1: Se recuerda que, siempre que haya nieve, la ausencia total de peligro no existe. Hay que tener presente que en circunstancias desfavorables, con aludes de tamaño 1 (alud pequeño o colada) y tamaño 2 (alud mediano), se pueden sufrir severos daños personales.

Nota2: Los BPA se elaboran en base a información meteorológica así como al estado del manto nivoso a través de sondeos puntuales. Se advierte a los usuarios de la variabilidad de esta información al extrapolarla a zonas extensas de montaña. Por ello, AEMET no se hace responsable de su uso para la toma de decisiones que conciernen a la seguridad personal, ni de los riesgos físicos o materiales de ellas derivadas.

AEMET. Se autoriza la reproducción de su contenido citando la fuente.