GOBIERNO DE ESPAÑA
VICEPRESIDENCIA TERCERA DEL GOBIERNO
MINISTERIO PARA LA TRANSICIÓN ECOLÓGICA Y EL RETO DEMOGRÁFICO

Boletín de información nivológica y de peligro de aludes

Pirineo Navarro y Aragonés

aemet Agencia Estatal de Meteorología

viernes, 13 de marzo de 2026

Pronóstico hasta las 24 horas del sábado, día 14 de marzo

(Válido fuera de pistas de esquí balizadas y abiertas)

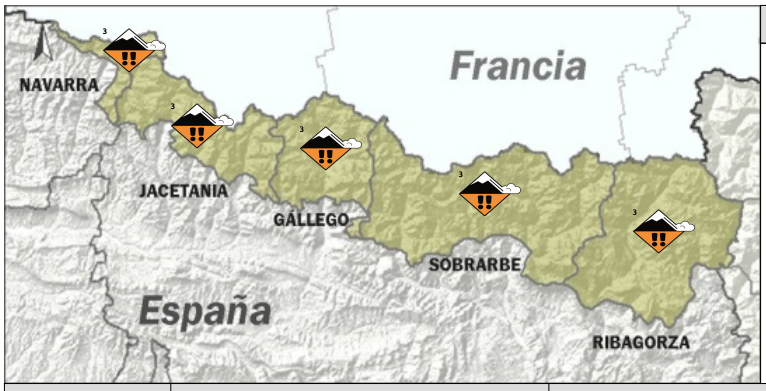

Problemas de aludes

Nieve reciente

Placas de viento

Macizo	Peligro	Problemas de aludes, cota, orientación, tamaño	Innivación observada (m)
Navarra	3 Notable	Nieve reciente: 2 — N, O, E, S Placas de viento: 3 — 1800 — N, O, E, S	2026-03-12 N S Cota más baja caras N
Jacetania	3 Notable	Nieve reciente: 2 — N, O, E, S Placas de viento: 3 — 1800 — N, O, E, S	2026-03-12 N S Cota más baja caras N
Gállego	3 Notable	Nieve reciente: 2 — N, O, E, S Placas de viento: 3 — 1800 — N, O, E, S	2026-03-12 N S Cota más baja caras N

AEMET. Se autoriza la reproducción de su contenido citando la fuente.

Boletín de información nivológica y de peligro de aludes

Pirineo Navarro y Aragonés

Sobrarbe	3 **Notable**	**Nieve reciente**  **Placas de viento** 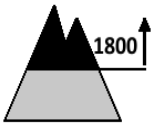 	2026-03-12 Cota más baja caras N
Ribagorza	3 **Notable**	**Nieve reciente**  **Placas de viento** 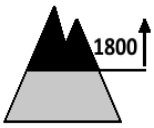 	2026-03-12 Cota más baja caras N

Estado del manto y observaciones recientes

Ayer predominaron los cielos poco nubosos o despejados, propiciando una leve disminución de los espesores y un buen rehielo nocturno esta madrugada. Soplaron vientos entre moderados y fuertes del noroeste en cotas altas que han podido movilizar algunos centímetros de nieve reciente formando pequeñas placas de viento cerca de crestas y cordales.

El manto es continuo desde 1500 metros en caras norte y 1700 en caras sur aproximadamente. Pese a la mengua progresiva, los espesores siguen siendo importantes, rondando los 80-140 cm en torno a 1800 metros y los 120-200 cm por encima de 2100 metros, pudiendo ser sensiblemente mayores en ventisqueros, hoyas y otras zonas propensas a la acumulación.

La nieve está humedecida hasta 2300 metros en umbrías y prácticamente hasta las cumbres en solanas, sumidas hace días en el ciclo de fusión y rehielo. En umbrías de cotas altas la nieve se mantiene fría y seca, y las diversas capas de nieve reciente de los últimos días se han ido faceteando. Se alternan con pequeñas costras de rehielo y alguna de escarcha superficial. En los tests muestran cierta reactividad ante esfuerzos moderados. Las pequeñas placas de viento formadas ayer han podido enterrar algunas de estas capas frágiles. También es posible encontrar en estas umbrías capas débiles persistentes en profundidad aunque se encuentran generalmente inactivas o su disparo es difícil.

Se han observado numerosas purgas naturales y algún alud mediano de nieve húmeda en las últimas 24h.

AEMET. Se autoriza la reproducción de su contenido citando la fuente.

Evolución del manto y peligro de aludes para el sábado, día 14

Mañana se esperan nevadas durante toda la jornada y un acusado descenso de las temperaturas. Podrían acumularse alrededor de unos 10-25 cm, localmente más en cotas altas. Por ello serán muy probables los aludes de nieve reciente de tamaño pequeño (1, riesgo de caída) o mediano (2, capaz de enterrar a una persona), sin descartar alguno mayor en zonas de acumulación por la tarde.

Asimismo, soplarán vientos fuertes sostenidos del norte y noroeste, y a medida que avance el día se irán formando numerosas placas de viento en todas las orientaciones aunque sobre todo en las este y sur. Serán fáciles de fracturar ante una sobrecarga débil (paso de un esquiador) u ocasionalmente de manera natural, provocando aludes de tamaño mediano o localmente grande (3, capaz de enterrar a un grupo de personas), especialmente aquellas que en umbrías por encima de 2300 metros descansen sobre capas débiles persistentes superficiales o en profundidad.

Predicción meteorológica para el sábado, día 14

Muy nuboso o cubierto, tendiendo a disminuir la nubosidad por la tarde, excepto en el entorno de la divisoria fronteriza donde persistirá nubosidad de estancamiento. Visibilidad localmente reducida en cotas altas. Se esperan precipitaciones débiles a moderadas, en ocasiones en forma de chubasco, que serán generalizadas en la primera mitad del día quedando reducidas al entorno de la divisoria en la segunda, donde podrán ser persistentes. Cota de nieve: bajando de 1800 a unos 700-900 metros por la tarde. Temperaturas en descenso, notable en las máximas. Las mínimas se darán al final del día. Heladas moderadas, en cotas altas fuertes y persistentes. Soplarán vientos del norte y noroeste, fuerte con rachas muy fuertes, y algo menos intenso en cotas bajas.

Datos en la atmósfera libre:

Altitud de la isoterma de 0 ºC: 1400 m
Altitud de la isoterma de -10 ºC: 2800 m

Viento a 1500 m: NW 30 km/h
Viento a 3000 m: NW 60 km/h

Evolución para el domingo día 15

Nivel de peligro sin grandes cambios.

(Información elaborada a partir de los datos recibidos de los refugios de Linza, Lizara, Panticosa, Bachimaña, Góriz, Pineta, Estós, Angel Orús, La Renclusa, Cap de Llauset y Belagua, de las estaciones de esquí de Candanchú, Formigal y Panticosa (lagos), de la estación de esquí de fondo de Llanos del Hospital y de Ordesa Pradera)

Escala europea de peligro de aludes

Débil | Limitado | Notable | Fuerte | Muy Fuerte

Problemas de aludes

Nieve reciente | Placas de viento | Capas débiles persistentes | Nieve húmeda | Deslizamientos basales | Sin problema evidente

Nota1: Se recuerda que, siempre que haya nieve, la ausencia total de peligro no existe. Hay que tener presente que en circunstancias desfavorables, con aludes de tamaño 1 (alud pequeño o colada) y tamaño 2 (alud mediano), se pueden sufrir severos daños personales.

AEMET. Se autoriza la reproducción de su contenido citando la fuente.

Nota2: Los BPA se elaboran en base a información meteorológica así como al estado del manto nivoso a través de sondeos puntuales. Se advierte a los usuarios de la variabilidad de esta información al extrapolarla a zonas extensas de montaña. Por ello, AEMET no se hace responsable de su uso para la toma de decisiones que conciernen a la seguridad personal, ni de los riesgos físicos o materiales de ellas derivadas.

AEMET. Se autoriza la reproducción de su contenido citando la fuente.